ICGC Institut Cartogràfic i Geològic de Catalunya

Servei Meteorològic de Catalunya meteo.cat

Boletín de peligro de aludes para el Pirineo de Catalunya
Del 04/03/2026 al 05/03/2026

(Válido fuera pistas de esquí y zonas no controladas)

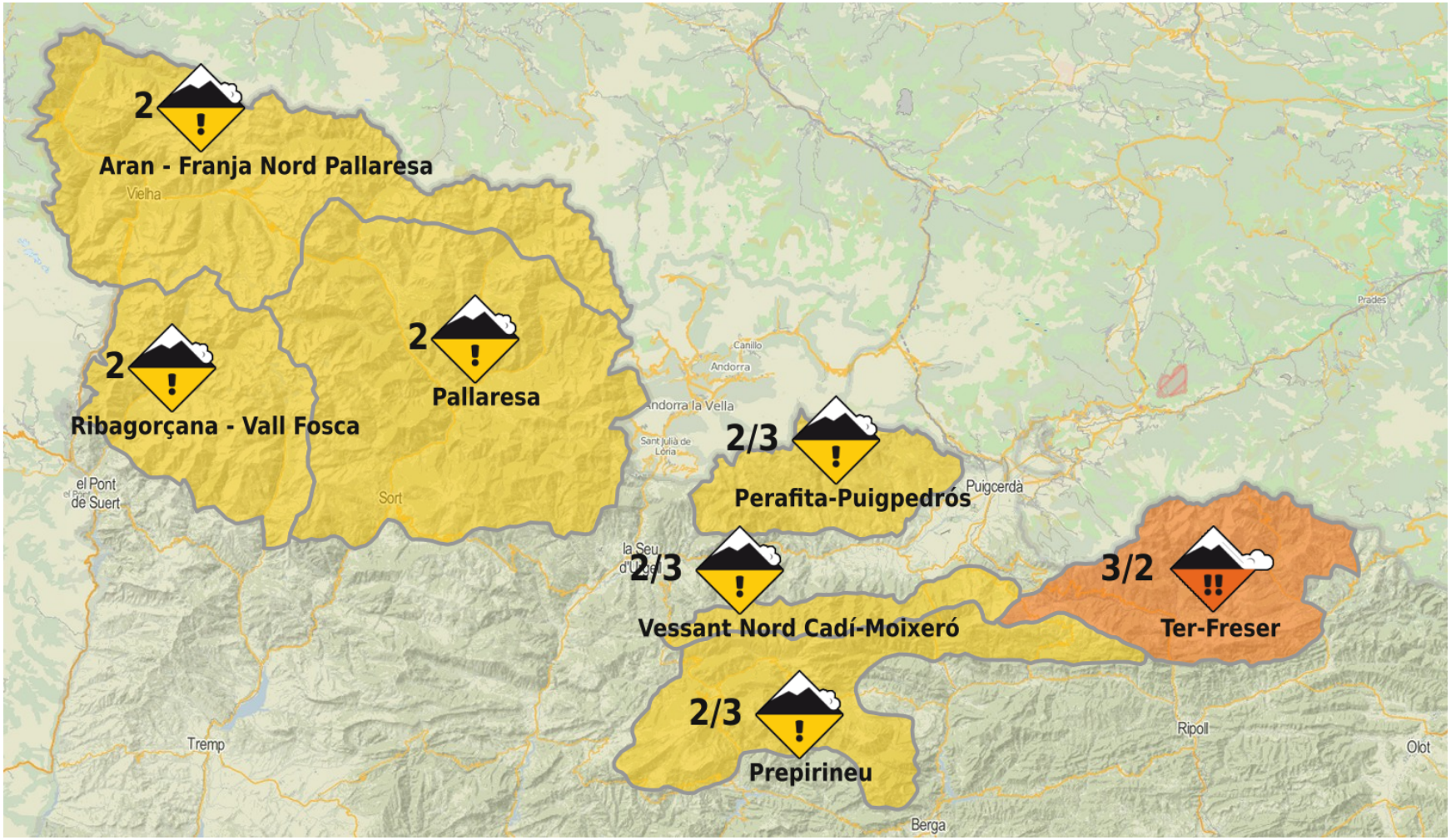

5 MUY FUERTE	4 FUERTE	3 NOTABLE	2 LIMITADO	1 DÉBIL

ICGC Institut Cartogràfic i Geològic de Catalunya

Servei Meteorològic de Catalunya meteo.cat

Boletín de peligro de aludes Aran - Franja Nord Pallaresa Del 04/03/2026 al 05/03/2026

(Válido fuera pistas de esquí y zonas no controladas)

LIMITADO (2).

Situación primaria

Nieve húmeda

Distribución

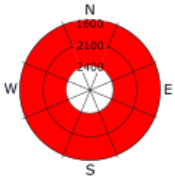

Tamaño

Origen

Tendencia

Situación secundaria

Deslizamientos basales

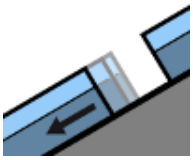

Distribución

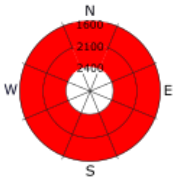

Tamaño

Origen

Tendencia

Estado del manto nivoso

En los últimos días el manto se va humedeciendo y perdiendo cohesión superficialmente por debajo de 2.200-2.300 m debido a lloviznas y nieblas. El jueves pueden caer algunos aludes de nieve húmeda de tamaño 1, pequeño, sin capacidad de enterrar a una persona, pero sí de hacernos perder el equilibrio. El jueves por la mañana, debido a la abundante nubosidad, el manto difícilmente regelará por la mañana, y, de hecho, las costras existentes poco a poco se irán ablandando y debilitando. Los deslizamientos basales volverán a reactivarse progresivamente. Son más probables a partir del mediodía. Serán de tamaño 2, medio, suficiente para enterrar a una persona, puntualmente mayor. Se desprenden en terreno herboso y liso; evite situarse bajo fisuras en el manto. De manera muy local, en umbrías altas podremos encontrar alguna placa de viento, a menudo con presencia de nieve granulada, que será susceptible de caer a nuestro paso. Irán engrosando la tarde del jueves.

Distribución del manto nivoso

Hay nieve por encima de unos 1.400 ma umbrías y 1.600 ma solanas. Los espesores a unos 2.200 m son superiores a los normales y rondan los 120-140 cm en el norte de Aran y los 160-200 cm en la Franja Norte Pallaresa y en el sur de Aran, puntualmente superiores.

Tendencia para las próximas 48-72h

Empeorará la estabilidad del manto por la acumulación prevista de nieve y el transporte. Peligro EN AUMENTO.

El próximo boletín será emitido el día 2026-03-05

5 MUY FUERTE	4 FUERTE	3 NOTABLE	2 LIMITADO	1 DÉBIL

EAWS EUROPEAN AVALANCHE WARNING SERVICES

ICGC Institut Cartogràfic i Geològic de Catalunya

Servei Meteorològic de Catalunya

Boletín de peligro de aludes Ribagorçana - Vall Fosca Del 04/03/2026 al 05/03/2026

(Válido fuera pistas de esquí y zonas no controladas)

LIMITADO (2).

Situación primaria

Nieve húmeda

Distribución

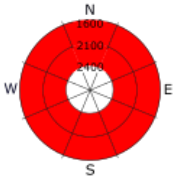

Tamaño

Origen

Tendencia

Situación secundaria

Deslizamientos basales

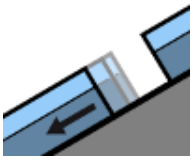

Distribución

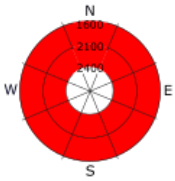

Tamaño

Origen

Tendencia

Estado del manto nivoso

El manto sigue humedeciendo superficialmente por las nieblas y las lloviznas que van teniendo lugar. El jueves serán probables, en cualquier orientación, algunos aludes de nieve húmeda de tamaño 1, pequeño, sin capacidad de enterrar a una persona, pero sí de hacernos perder el equilibrio. Los deslizamientos basales continuarán cayendo, con mayor probabilidad a partir de mediodía. Serán de tamaño 2, medio, suficiente para enterrar a una persona, puntualmente mayor. Se desprenden en terreno herboso y liso; evite situarse bajo fisuras en el manto. Bajo collados y cordales en las cotas más elevadas se está formando alguna pequeña placa de viento en orientaciones norte que se podría desprender al paso de una persona, en caso de chubascos de nieve más intensos. Durante la tarde del jueves, con las nevadas, se podría formar alguna placa local de viento en las umbrías más elevadas, en especial las orientadas a oeste y norte.

Distribución del manto nivoso

Hay nieve en el suelo a 1.500 m en terreno umbrío, y por encima de unos 1.700-1800 m en laderas soleadas. El manto es esquiable por encima de unos 1.600 m en umbrías. Los espesores alcanzan los 100-130 cm en cotas medias. Estos valores son superiores a los normales para la época.

Tendencia para las próximas 48-72h

Deberemos prestar atención sobre todo a las nuevas placas de viento ya los aludes naturales de nieve reciente. Peligro EN AUMENTO.

El próximo boletín será emitido el día 2026-03-05

5 MUY FUERTE	4 FUERTE	3 NOTABLE	2 LIMITADO	1 DÉBIL

EAWS EUROPEAN AVALANCHE WARNING SERVICES

ICGC Institut Cartogràfic i Geològic de Catalunya

Servei Meteorològic de Catalunya

Boletín de peligro de aludes Pallaresa
Del 04/03/2026 al 05/03/2026

(Válido fuera pistas de esquí y zonas no controladas)

LIMITADO (2).

Situación primaria

Nieve húmeda

Distribución

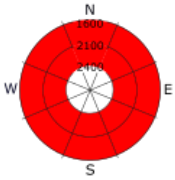

Tamaño

Origen

Tendencia

Situación secundaria

Deslizamientos basales

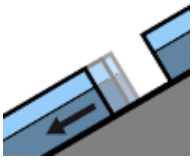

Distribución

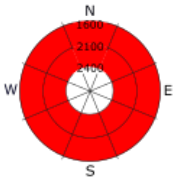

Tamaño

Origen

Tendencia

Estado del manto nivoso

El manto sigue humedeciendo superficialmente por las nieblas y las lloviznas que van teniendo lugar. El jueves serán probables, en cualquier orientación, algunos aludes de nieve húmeda de tamaño 1, pequeño, sin capacidad de enterrar a una persona, pero sí de hacernos perder el equilibrio. Los deslizamientos basales continuarán cayendo, con mayor probabilidad a partir de mediodía. Serán de tamaño 2, medio, suficiente para enterrar a una persona, puntualmente mayor. Se desprenden en terreno herboso y liso; evite situarse bajo fisuras en el manto. Bajo collados y cordales en las cotas más elevadas se está formando alguna pequeña placa de viento en orientaciones norte que se podría desprender al paso de una persona, en caso de chubascos de nieve más intensos. Durante la tarde del jueves, con las nevadas, se podría formar alguna placa local de viento en las umbrías más elevadas, en especial las orientadas a oeste y norte.

Distribución del manto nivoso

Hay nieve en el suelo a 1.500 m en terreno umbrío, esquiable por encima de unos 1.600 m; en orientaciones soleadas la nieve está presente por encima de unos 1.700-1.800 m. Los espesores alcanzan los 110-150 cm en cotas medias.

Tendencia para las próximas 48-72h

Deberemos prestar atención sobre todo a las nuevas placas de viento ya los aludes naturales de nieve reciente. Peligro EN AUMENTO.

El próximo boletín será emitido el día 2026-03-05

5 MUY FUERTE	4 FUERTE	3 NOTABLE	2 LIMITADO	1 DÉBIL

EAWS EUROPEAN AVALANCHE WARNING SERVICES

ICGC Institut Cartogràfic i Geològic de Catalunya

Servei Meteorològic de Catalunya

Boletín de peligro de aludes Perafita-Puigpedrós Del 04/03/2026 al 05/03/2026

(Válido fuera pistas de esquí y zonas no controladas)

LIMITADO (2) hasta media tarde. NOTABLE (3) a partir de entonces.

Situación primaria

Nieve húmeda

Distribución

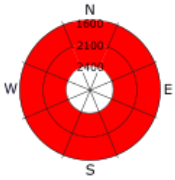

Tamaño

Origen

Tendencia

Situación secundaria

Nieve reciente

Distribución

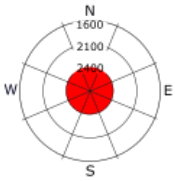

Tamaño

Origen

Tendencia

Estado del manto nivoso

El jueves el manto se encontrará superficialmente húmedo casi hasta las cimas más elevadas. Las lloviznas y las nieblas no permitirán que regele ya lo largo de la jornada el manto continuará ablandando progresivamente a niveles más profundos. Como consecuencia podrán caer aludes de nieve húmeda de forma natural ya cualquier orientación. Serán de tamaño 1, suficiente para producir caídas y lesiones, si bien no se descartan mayores en lugares de fuerte pendiente. Habrá que vigilar con las acumulaciones en forma de lluvia, ya que la caída de aludes se intensificará en caso de acumulaciones o intensidades elevadas. Durante las horas centrales del día descenderá la cota y se acumulará nieve reciente húmeda hasta unos 2.400 m. A partir de media tarde serán probables caídas naturales de aludes de nieve reciente, por lo general de tamaño 1, y que afectarán a todas las orientaciones. También se formarán placas muy locales en las zonas más expuestas al viento a lo largo de la tarde.

Distribución del manto nivoso

Hay nieve en el suelo por encima de unos 1.600 m, si bien en las solanas más derechas el manto sigue retranqueando y la nieve está presente por encima de 1.800 m. Los espesores, aunque irregulares, rondan los 70-90 cm en cotas medias, con frecuentes deflaciones en orientaciones norte y oeste por encima del nivel del bosque. Son grosores por encima de los habituales para la época.

Tendencia para las próximas 48-72h

Se espera un claro aumento del peligro de aludes por la mayor actividad de aludes de nieve reciente y por la formación de placas de viento. Peligro EN AUMENTO.

El próximo boletín será emitido el día 2026-03-05

5 MUY FUERTE	4 FUERTE	3 NOTABLE	2 LIMITADO	1 DÉBIL

EAWS EUROPEAN AVALANCHE WARNING SERVICES

ICGC Institut Cartogràfic i Geològic de Catalunya

Servei Meteorològic de Catalunya

Boletín de peligro de aludes Vessant Nord Cadí-Moixeró Del 04/03/2026 al 05/03/2026

(Válido fuera pistas de esquí y zonas no controladas)

LIMITADO (2) hasta media tarde. NOTABLE (3) a partir de entonces.

Situación primaria

Nieve húmeda

Distribución

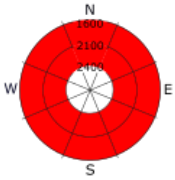

Tamaño

Origen

Tendencia

Situación secundaria

Nieve reciente

Distribución

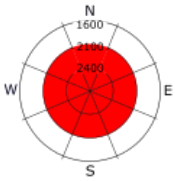

Tamaño

Origen

Tendencia

Estado del manto nivoso

El jueves el manto se encontrará superficialmente húmedo casi hasta las cimas más elevadas. Las lloviznas y las nieblas no permitirán que regele ya lo largo de la jornada el manto continuará ablandando progresivamente a niveles más profundos. Como consecuencia podrán caer aludes de nieve húmeda de forma natural ya cualquier orientación. Serán de tamaño 1, suficiente para producir caídas y lesiones, si bien no se descartan mayores en lugares de fuerte pendiente. Habrá que vigilar con las acumulaciones en forma de lluvia, ya que la caída de aludes se intensificará en caso de acumulaciones o intensidades elevadas. Durante las horas centrales del día descenderá la cota y se acumulará nieve reciente húmeda hasta unos 2.400 m. A partir de media tarde serán probables caídas naturales de aludes de nieve reciente, por lo general de tamaño 1, y que afectarán a todas las orientaciones. También se formarán placas muy locales en las zonas más expuestas al viento a lo largo de la tarde.

Distribución del manto nivoso

En umbrías hay nieve por encima de 1.500 m, esquiable por encima de unos 1.700 m. En solanas la nieve está presente por encima de 1.700 m. Los espesores están alrededor de 130-160 cm en cotas medias. Estos valores siguen siendo muy excedentarios para la época del año.

Tendencia para las próximas 48-72h

Se espera un claro aumento del peligro de aludes por la mayor actividad de aludes de nieve reciente y por la formación de placas de viento. Peligro EN AUMENTO.

El próximo boletín será emitido el día 2026-03-05

5 MUY FUERTE	4 FUERTE	3 NOTABLE	2 LIMITADO	1 DÉBIL

EAWS EUROPEAN AVALANCHE WARNING SERVICES

ICGC Institut Cartogràfic i Geològic de Catalunya

Servei Meteorològic de Catalunya

Boletín de peligro de aludes Prepirineu
Del 04/03/2026 al 05/03/2026

(Válido fuera pistas de esquí y zonas no controladas)

LIMITADO (2) hasta media tarde. NOTABLE (3) a partir de entonces.

Situación primaria

Nieve húmeda

Distribución

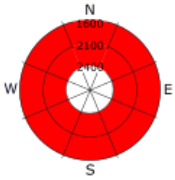

Tamaño

Origen

Tendencia

Situación secundaria

Nieve reciente

Distribución

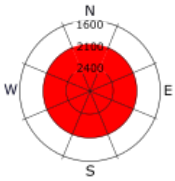

Tamaño

Origen

Tendencia

Estado del manto nivoso

El jueves el manto se encontrará superficialmente húmedo casi hasta las cimas más elevadas. Las lloviznas y las nieblas no permitirán que regele ya lo largo de la jornada el manto continuará ablandando progresivamente a niveles más profundos. Como consecuencia podrán caer aludes de nieve húmeda de forma natural ya cualquier orientación. Serán de tamaño 1, suficiente para producir caídas y lesiones, si bien no se descartan mayores en lugares de fuerte pendiente. Habrá que vigilar con las acumulaciones en forma de lluvia, ya que la caída de aludes se intensificará en caso de acumulaciones o intensidades elevadas. Durante las horas centrales del día descenderá la cota y se acumulará nieve reciente húmeda hasta unos 2.400 m. A partir de media tarde serán probables caídas naturales de aludes de nieve reciente, por lo general de tamaño 1, y que afectarán a todas las orientaciones. También se formarán placas muy locales en las zonas más expuestas al viento a lo largo de la tarde.

Distribución del manto nivoso

Hay nieve en el suelo por encima de unos 1.600 m, si bien en las solanas más derechas el manto sigue retranqueando y la nieve está presente por encima de 1.800 m. Los espesores, aunque irregulares, rondan los 70-90 cm en cotas medias, con frecuentes deflaciones en orientaciones norte y oeste por encima del nivel del bosque.

Tendencia para las próximas 48-72h

Se espera un claro aumento del peligro de aludes por la mayor actividad de aludes de nieve reciente y por la formación de placas de viento. Peligro EN AUMENTO.

El próximo boletín será emitido el día 2026-03-05

5 MUY FUERTE	4 FUERTE	3 NOTABLE	2 LIMITADO	1 DÉBIL

EAWS EUROPEAN AVALANCHE WARNING SERVICES

ICGC Institut Cartogràfic i Geològic de Catalunya

meteo.cat Servei Meteorològic de Catalunya

Boletín de peligro de aludes Ter-Freser
Del 04/03/2026 al 05/03/2026

(Válido fuera pistas de esquí y zonas no controladas)

NOTABLE (3) a partir de mediodía. LIMITADO (2) por la mañana.

Situación primaria

Nieve húmeda

Distribución

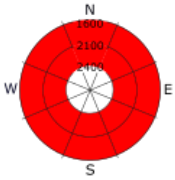

Tamaño

Origen

Tendencia

Situación secundaria

Nieve reciente

Distribución

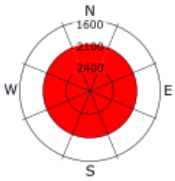

Tamaño

Origen

Tendencia

Estado del manto nivoso

Se espera una jornada de cambios, con peligro en aumento y aparición de nuevos problemas. Por la mañana encontraremos un manto húmedo en superficie hasta 2.600 m, con lloviznas más frecuentes en el Valle del Ter, nieblas y temperaturas elevadas. No se espera que rehiele y se esperan aludes de nieve húmeda en cualquier orientación, de tamaño 1, pero que podrán alcanzar tamaño 2 (con capacidad para enterrar a una persona) en función de las acumulaciones de lluvia. En laderas lisas, herbosas y de fuerte pendiente también podrá continuar la actividad natural de deslizamientos basales, y se recomienda evitar el terreno bajo grietas hasta el suelo. Durante el episodio irán ganando protagonismo los problemas de nieve reciente y placas de viento, especialmente a partir de mediodía. La nieve, densa y húmeda, que se vaya acumulando podrá desprenderse de forma natural en forma de aludes de tamaño 1 y 2. Durante la tarde se formarán placas de viento por encima de unos 2.400 m.

Distribución del manto nivoso

El manto nivoso presenta grosores muy excedentarios para la época del año. En lugares no afectados por el viento los grosores oscila entre 70-90 cm a unos 2.000 my 160-190 cm por encima de 2.400 m. Es esquiable a partir de unos 1600 m. Aparecen deflaciones por encima del nivel del bosque, sobre todo en lugares bien expuestos al viento de norte y oeste.

Tendencia para las próximas 48-72h

Aumentará claramente el problema de nieve reciente y, de forma destacada, el de placas de viento, que irá tomando protagonismo afectando cada vez a más terreno. Peligro EN AUMENTO.

El próximo boletín será emitido el día 2026-03-05

5 MUY FUERTE	4 FUERTE	3 NOTABLE	2 LIMITADO	1 DÉBIL

EAWS EUROPEAN AVALANCHE WARNING SERVICES