BUTLLETÍ DEL PERILL D'ALLAUS DEL PRINCIPAT D'ANDORRA

Elaborat el 04/03/2026 16:00
Propera actualització 05/03/2026 a les 16h

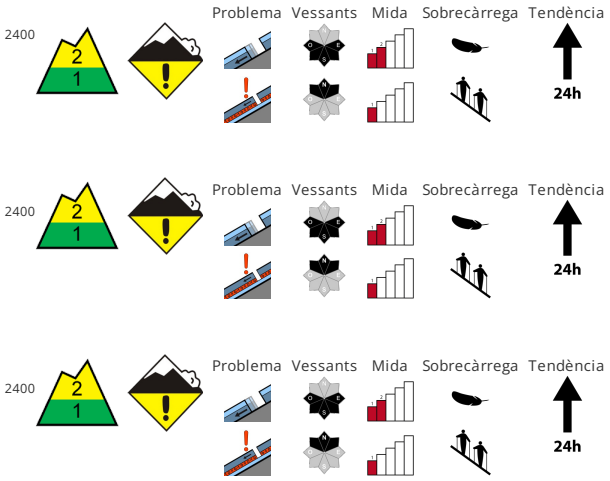

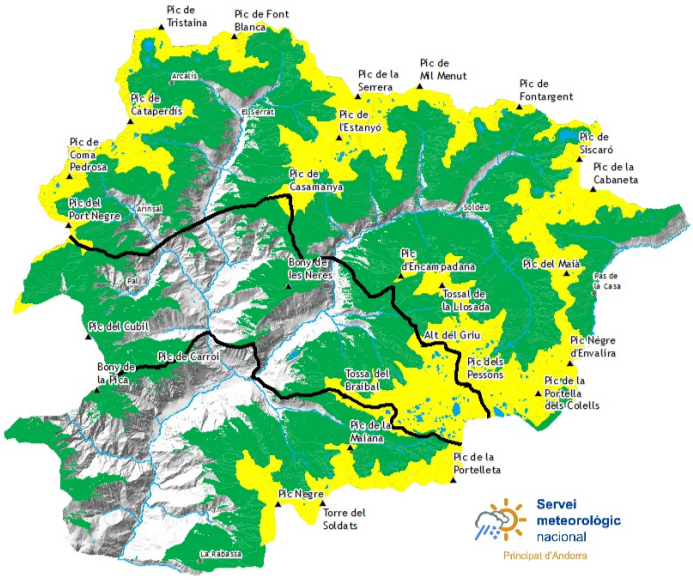

ESTABILITAT DEL MANTELL NIVAL

Poden desencadenar-se allaus de lliscament basal a qualsevol hora del dia o de la nit. Això es dona especialment en vessants assolellats. Amb la humidificació, en totes les orientacions són possibles algunes purgues de neu humida de mida petita. Dijous :. Amb la intensificació de la precipitació, a partir del migdia el perill d'allaus de neu humida augmentarà progressivament. Encara als vessants molt inclinats orientats a nord a la part central del mantell de neu hi ha capes febles. Això es dona especialment en vessants extremadament drets i per sobre dels 2400 m aproximadament. Aquestes poden de vegades ser desencadenades de manera aïllada com a mínim per una sobrecàrrega forta i assolir mida mitjana.

QUALITAT DE LA NEU

Dimecres: Cauran localment fins a 5 cm de neu. Dijous : En particular al sud-est a partir del migdia cauran en alguns sectors 10 cm de neu per sobre dels 2400 m aproximadament, localment fins a 15 cm. Caurà pluja fins a cotes mitges especialment als al sud-est. Les condicions són primaverals. El refredament nocturn serà reduït. La superfície del mantell de neu es regelarà tot just s'estovarà ràpidament. Els gruixos de neu varien molt per sobre dels 2100 m aproximadament per la influència del vent. Evitar les zones amb esquerdes de lliscament basal.

GRUIXOS DEL MANTELL NIVAL FORA DE PISTA

Zona nord		Gruix neu		
Mantell Nival		1500m	2000m	2500m
N	1600 m	30 cm	150 cm	200 cm
S	1900 m	0 cm	100 cm	150 cm

Zona centre		Gruix neu		
Mantell Nival		1500m	2000m	2500m
N	1600 m	20 cm	150 cm	200 cm
S	1900 m	0 cm	100 cm	150 cm

Zona sud		Gruix neu		
Mantell Nival		1500m	2000m	2500m
N	1600 m	20 cm	120 cm	150 cm
S	1900 m	0 cm	60 cm	100 cm

Govern d'Andorra

EAWS EUROPEAN AVALANCHE WARNING SERVICES

Aquest butlletí ha estat elaborat seguint les normes i recomanacions de l'**European Avalanche Warning Services**, del qual el **Servei meteorològic Nacional** n'és membre

BUTLLETÍ DEL PERILL D'ALLAUS DEL PRINCIPAT D'ANDORRA

Servei meteorològic nacional
Principat d'Andorra

Informació detallada per espais naturals protegits

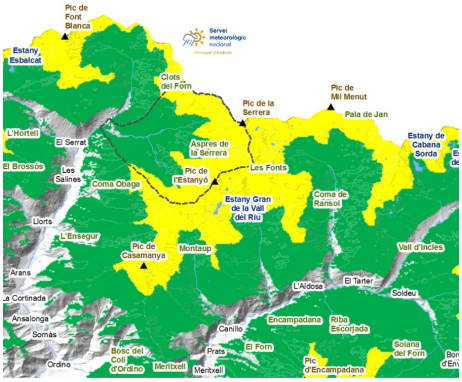

SORTENY

La neu poca neu nova, barrejada amb fang, caiguda dins dimecres no canviarà les condicions d´estabilitat. A partir del migdia de dijous les precipitacions amb una cota de neu a 2400m humidificaran la neu en totes les orientacions a cotes inferiors i crearan febles acumulacions per sobre.

Trobem neu a tots els camins des de Llorts i l´accés amb esquís fins al Refugi és continu. Als vessants nord hi ha neu pols reciclada (grans facetats) molt agradable d´esquiar. Aquesta neu reposa a sobre de plaques que amaguen algunes capes febles persistents als indrets més alts i escarpats. Tot i que aquestes només les tenim identificades en alguns indrets molt inclinats orientats al nord (obacs), les hem de tenir en compte per escollir el nostre itinerari amb seguretat i no perdre el costum de circular per indrets segurs.

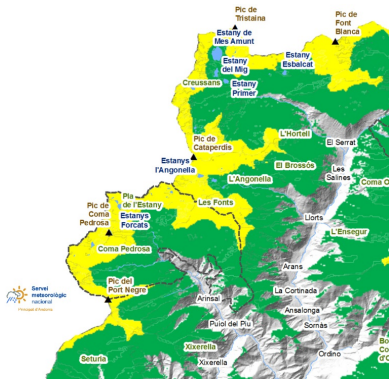

COMAPEDROSA

L´accés des d´Arinsal està quedant cada vegada amb menys neu, i la neu contínua cada vegada la trobem més amunt. A les parts altes del Parc, però, les condicions són molt bones i es poden fer nombroses excursions, sempre mantenint l´elecció acurada de l´itinerari i l´horari de les excursions. Les precipitacions en forma líquida a cotes baixes contribuiran en reduir els accessos esquiables.

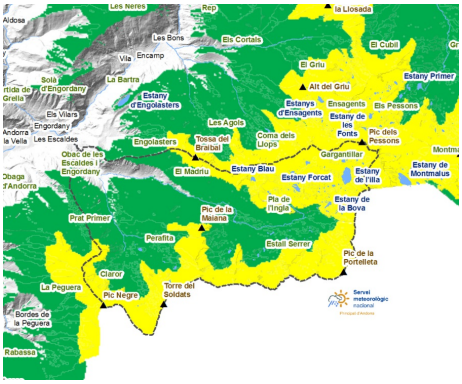

MADRIU-PERAFITA-CLAROR

Als vessants sud i a cotes baixes les condicions són primaverals, neu lleugerament regelada al matí i tova al migdia. Als vessants nord i en altitud la neu es manté pols.

Govern d'Andorra

EAWS
EUROPEAN AVALANCHE WARNING SERVICES

Aquest butlletí ha estat elaborat seguint les normes i recomanacions de l'**European Avalanche Warning Services**, del qual el **Servei meteorològic Nacional** n'és membre

BUTLLETÍ DEL PERILL D'ALLAUS DEL PRINCIPAT D'ANDORRA

Servei meteorològic nacional
Principat d'Andorra

Gruixos de neu nova dels darrers dies (de les últimes 24h mesurat a les 06:00h UTC)

	28/02/2026	01/03/2026	02/03/2026	03/03/2026
FEDA (Central)	0 cm	0 cm	0 cm	0 cm
Engolasters - FEDA	0 cm	0 cm	0 cm	0 cm
Ransol - FEDA	2 cm	0 cm	0 cm	4 cm
Fontverd	0 cm	0 cm	0 cm	0 cm
Setúria	0 cm	0 cm	0 cm	0 cm
Bony de les Neres	0 cm	0 cm	0 cm	0 cm
Grau Roig - FEDA	0 cm	0 cm	0 cm	0 cm
Caborreu	1 cm	0 cm	0 cm	0 cm
Sorteny	2 cm	0 cm	0 cm	0 cm
Perafita	0 cm	0 cm	0 cm	4 cm
Tossa Espiolets	1 cm	0 cm	0 cm	2 cm
La Solana	5 cm	0 cm	0 cm	0 cm
Vall del Riu FEDA	0 cm	0 cm	0 cm	3 cm
Envalira Antenes	0 cm	0 cm	0 cm	4 cm