BUTLLETÍ DEL PERILL D'ALLAUS DEL PRINCIPAT D'ANDORRA

Elaborado el 04/03/2026 16:00
Proxima actualización 05/03/2026 a las 16h

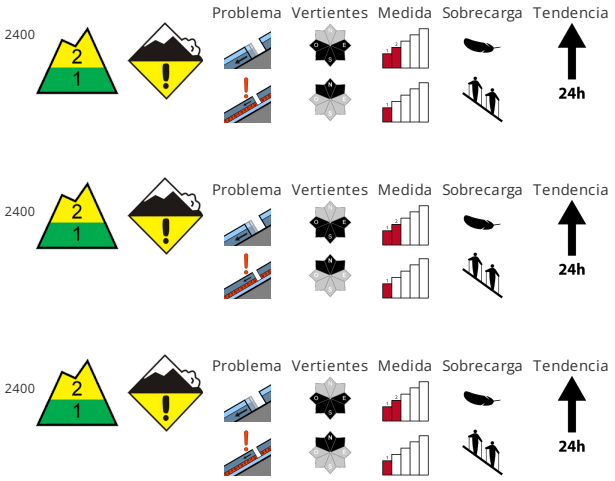

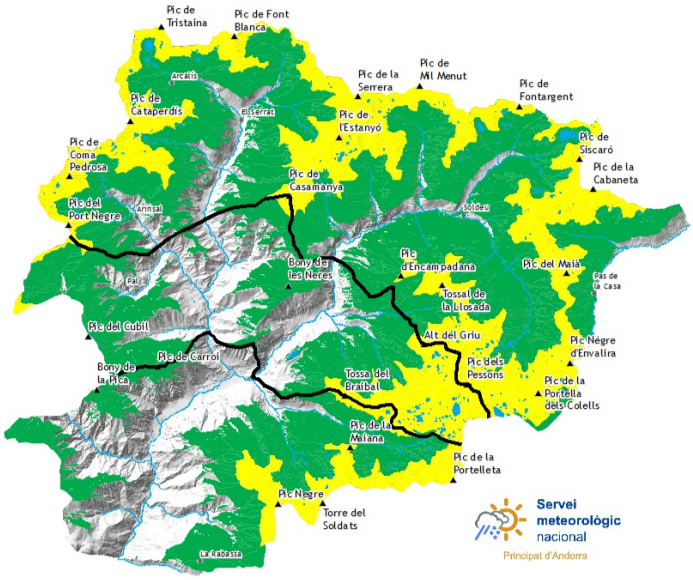

CALIDAD DE LA NIEVE

Pueden desencadenarse aludes de deslizamiento basal a cualquier hora del día o de la noche. Esto se da especialmente en las laderas solanas. Con la humidificación, en todas las orientaciones son posibles algunas purgas de nieve húmeda de tamaño pequeño. Jueves :. Con la intensificación de la precipitación, a partir del mediodía el peligro de aludes de nieve húmeda aumentará progresivamente. Todavía en las laderas muy inclinadas orientadas a norte en la parte central del manto de nieve hay capas débiles. Esto se da especialmente en las laderas extremadamente pendientes y por encima de los 2400 m aproximadamente. Estos pueden a veces ser desencadenadas de manera aislada como mínimo por una sobrecarga fuerte y alcanzar un tamaño mediano.

ESTABILIDAD DEL MANTO NIVOSO

Caerán localmente hasta 5 cm de nieve. Jueves :. En particular en el sudeste a partir del mediodía caerán en algunos sectores 15 cm de nieve por encima de los 2400 m aproximadamente, localmente hasta 15 cm. Caerá lluvia hasta cotas medias especialmente en los sudeste. Las condiciones son primaverales. El enfriamiento nocturno será reducido. La superficie del manto de nieve se volverá a helar apenas se ablandará rápidamente. Los espesores de nieve varían mucho por encima de los 2100 m aproximadamente por la influencia del viento. Evitar las zonas con grietas de deslizamiento basal.

ESPESORES DEL MANTO NIVOSO FUERA DE PISTA

Zona norte		Espesor nieve		
Manto Nival		1500m	2000m	2500m
N	1600 m	30 cm	150 cm	200 cm
S	1900 m	0 cm	100 cm	150 cm

zona centro		Espesor nieve		
Manto Nival		1500m	2000m	2500m
N	1600 m	20 cm	150 cm	200 cm
S	1900 m	0 cm	100 cm	150 cm

Zona sur		Espesor nieve		
Manto Nival		1500m	2000m	2500m
N	1600 m	20 cm	120 cm	150 cm
S	1900 m	0 cm	60 cm	100 cm

Govern d'Andorra

EAWS EUROPEAN AVALANCHE WARNING SERVICES

Aquest butlletí ha estat elaborat seguint les normes i recomanacions de l'**European Avalanche Warning Services**, del qual el **Servei meteorològic Nacional** n'és membre

BUTLLETÍ DEL PERILL D'ALLAUS DEL PRINCIPAT D'ANDORRA

Servei meteorològic nacional
Principat d'Andorra

Información detallada por espacios naturales protegidos

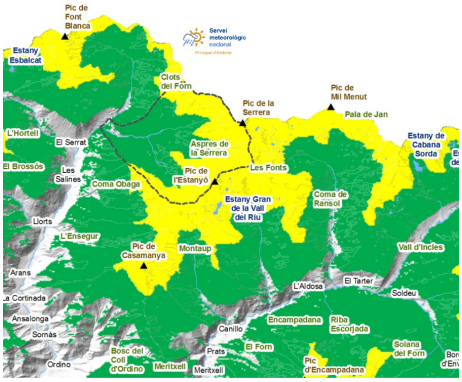

SORTENY

La nieve poca nieve nueva, mezclada con barro, caída dentro del miércoles no cambiará las condiciones de estabilidad. A partir del mediodía del jueves las precipitaciones con una cota de nieve a 2400m humidificarán la nieve en todas las orientaciones en cotas inferiores y crearán débiles acumulaciones por encima. \r\n Encontramos nieve en todos los caminos desde Llorts y el acceso con esquís hasta el Refugi es continuo. En las vertientes norte hay nieve polvo reciclado (grandes facetados) muy agradable de esquiar. Esta nieve reposa sobre placas que esconden algunas capas débiles persistentes en los lugares más altos y escarpados. Aunque éstas sólo las tenemos identificadas en algunos lugares muy inclinados orientados al norte (umbrías), debemos tenerlas en cuenta para escoger nuestro itinerario con seguridad y no perder la costumbre de circular por lugares seguros.

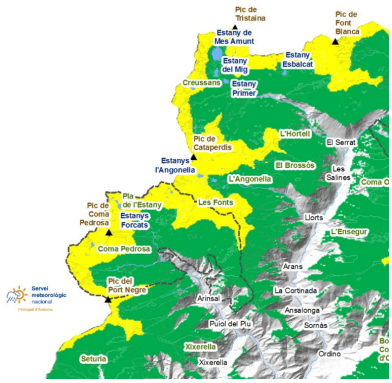

COMAPEDROSA

El acceso desde Arinsal está quedando cada vez con menos nieve, y la nieve continua la encontramos cada vez más arriba. Sin embargo, en las partes altas del Parque las condiciones son muy buenas y se pueden hacer numerosas excursiones, siempre manteniendo la elección cuidadosa del itinerario y el horario de las excursiones. Las precipitaciones en forma líquida en cotas bajas contribuirán al reducir los accesos esquiables.

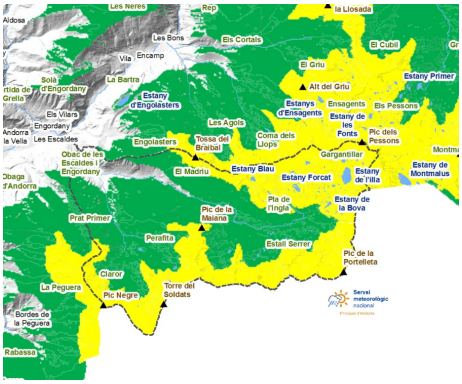

MADRIU-PERAFITA-CLAROR

En las vertientes sur y en cotas bajas las condiciones son primaverales, nieve ligeramente rehelada por la mañana y blanda al mediodía. En las vertientes norte y en altitud la nieve se mantiene polvo.

Govern d'Andorra

EAWS
EUROPEAN AVALANCHE WARNING SERVICES

Aquest butlletí ha estat elaborat seguint les normes i recomanacions de l'**European Avalanche Warning Services**, del qual el **Servei meteorològic Nacional** n'és membre

BUTLLETÍ DEL PERILL D'ALLAUS DEL PRINCIPAT D'ANDORRA

Servei meteorològic nacional
Principat d'Andorra

Espesores de nieve nueva de los últimos días (de las ultimas 24h mesurado a las 06:00h UTC)

	28/02/2026	01/03/2026	02/03/2026	03/03/2026
FEDA (Central)	0 cm	0 cm	0 cm	0 cm
Engolasters - FEDA	0 cm	0 cm	0 cm	0 cm
Ransol - FEDA	2 cm	0 cm	0 cm	4 cm
Fontverd	0 cm	0 cm	0 cm	0 cm
Setúria	0 cm	0 cm	0 cm	0 cm
Bony de les Neres	0 cm	0 cm	0 cm	0 cm
Grau Roig - FEDA	0 cm	0 cm	0 cm	0 cm
Caborreu	1 cm	0 cm	0 cm	0 cm
Sorteny	2 cm	0 cm	0 cm	0 cm
Perafita	0 cm	0 cm	0 cm	4 cm
Tossa Espiolets	1 cm	0 cm	0 cm	2 cm
La Solana	5 cm	0 cm	0 cm	0 cm
Vall del Riu FEDA	0 cm	0 cm	0 cm	3 cm
Envalira Antenes	0 cm	0 cm	0 cm	4 cm