MINISTERO DELLA DIFESA

meteomont Servizio Nazionale di previsione neve e valanghe

EAWS EUROPEAN AVALANCHE WARNING SERVICES

CARABINIERI

In collaborazione con: arpav

DOLOMITI SETTENTRIONALI

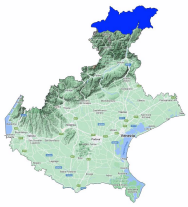

Bollettino Valanghe N. 363/2026 del 04/03/2026 ore 14.00

Validità 48 ore prossima emissione 05/03/2026

A cura del Servizio METEOMONT dell'ARMA dei CARABINIERI

In collaborazione con Servizio Meteorologico dell'Aeronautica militare

SITUAZIONE alle 14:00 del 04/03/2026

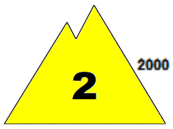

SITUAZIONE TIPO: passaggio da poca a molta neve.



SITUAZIONE TIPO: situazione primaverile.

Quota neve (mslm)	Nord	Sud
	1000 - 1400	1200 - 1800

Altezza Neve (cm)	Neve al suolo	Neve Fresca	Quota (mslm)
	074	00	2119
	60	00	1530

VALANGHE OSSERVATE: Nessuna valanga.

PREVISIONI 05/03/2026

GRADO DI PERICOLO: MODERATO 2

SITUAZIONE TIPO: passaggio da poca a molta neve.

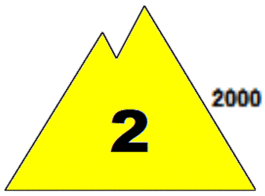

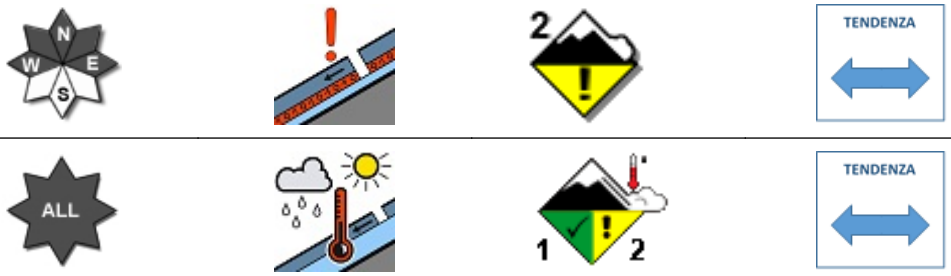

SITUAZIONE TIPO: situazione primaverile.

MANTO NEVOSO: La stabilità del manto nevoso è scarsa su alcuni punti (aree) per versanti da ovest a est al di sopra di 2000 mslm, possibili valanghe di dimensioni medie.
La stabilità del manto nevoso è scarsa su alcuni punti (aree) per tutte le esposizioni al di sotto di 2000 mslm, possibili valanghe di dimensioni medie.

AVVERTENZE

Il rialzo termico diurno richiede un'attenta valutazione temporale dell'escursione che eviti l'attraversamento di pendii ripidi nelle ore più calde della giornata.

SCALA EUROPEA DEL GRADO DI PERICOLO VALANGHE

LEGENDA PROBLEMA

Bollettino realizzato su scala sinottica-regionale (standard EAWS). La sua valutazione non può escludere in alcun modo la necessità di una seria e capace valutazione locale del pericolo (singolo pendio) che può essere anche sensibilmente diverso. Le previsioni meteorologiche sono relative all'orario UTC (per l'Italia +1 in inverno e +2 in estate).

DOLOMITI SETTENTRIONALI

PREVISIONE METEO

Quota		05/03/2026 h6:00	05/03/2026 h12:00	05/03/2026 h18:00
1000	Venti	01 Nodi da Nord	01 Nodi da Nord	02 Nodi da N-Est
	Temperature	+02 °C	+02 °C	+03 °C
	Temp.percepita	2 °C	2 °C	3 °C
2000	Venti	01 Nodi da Nord	01 Nodi da S-Ovest	01 Nodi da Nord
	Temperature	+01 °C	+01 °C	+03 °C
	Temp.percepita	1 °C	1 °C	3 °C
3000	Venti	01 nodi da N-Ovest	03 Nodi da S-Ovest	03 Nodi da Ovest
	Temperature	-03 °C	-03 °C	-02 °C
	Temp.percepita	-3 °C	-5 °C	-4 °C
Zero termico		1900-2100 m.	2400-2600 m.	2600-2800 m.
Fenomeno		—	—	—
Stato del cielo				

LEGENDA FENOMENI

— Assenza Fenomeni · Nebbia · Foschia · Pioggia debole · Pioggia moderata · Pioggia forte · Temporali

Nevicata debole · Nevicata moderata · Nevicata forte

STATO DEL CIELO

Sereno · Poco nuvoloso · Nuvoloso · Molto nuvoloso · Coperto

Parametri meteonivometrici registrati presso i campi di rilevamento il 04/03/2026.

Località	Comune	Quota (m.s.l.m.)	Altezza neve (cm)	Neve caduta nelle 24 ore (cm)	Temp. Min (°C)	Temp. Max (°C)	Condizioni del tempo
MISURINA	Auronzo di Cadore (BL)	1759	49	0	-7	+17	Assenza di precipitazioni
MONTE AGUDO	Auronzo di Cadore (BL)	1530	60	0	-3	+5	Assenza di precipitazioni
MONTE FALORIA	Cortina d'Ampezzo (BL)	2119	74	0	-6	+9	Assenza di precipitazioni
COL DELLA TENDA	Comelico Superiore (BL)	1930	70	1	-4	+10	Assenza di precipitazioni

(*) Rilievi fuori campo

L'INFORMAZIONE E' PREVENZIONE - LEGGI L'ATTUALE GRADO DI PERICOLO VALANGHE!

IL CAPO DEL CENTRO NAZIONALE METEOMONT
(Ten. Col. RFI Emanuela Gini)
FIRMA AUTOGRAFA OMESSA AI SENSI
DELL'ART.3 DEL D.LGS N.39/1993

Bollettino realizzato su scala sinottica-regionale (standard EAWS). La sua valutazione non può escludere in alcun modo la necessità di una seria e capace valutazione locale del pericolo (singolo pendio) che può essere anche sensibilmente diverso. Le previsioni meteorologiche sono relative all'orario UTC (per l'Italia +1 in inverno e +2 in estate).