MINISTERO DELLA DIFESA

meteomont Servizio Nazionale di previsione neve e valanghe

EAWS EUROPEAN AVALANCHE WARNING SERVICES

CARABINIERI

In collaborazione con: arpav

DOLOMITI MERIDIONALI

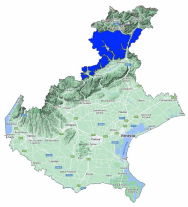

Bollettino Valanghe N. 365/2026 del 04/03/2026 ore 14.00
Validità 48 ore prossima emissione 05/03/2026

A cura del Servizio METEOMONT dell'ARMA dei CARABINIERI
In collaborazione con Servizio Meteorologico dell'Aeronautica militare

SITUAZIONE alle 14:00 del 04/03/2026

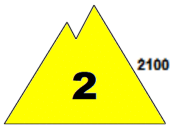

SITUAZIONE TIPO: passaggio da poca a molta neve.



SITUAZIONE TIPO: situazione primaverile.

Quota neve (mslm)	Nord	Sud
	1400 - 1600	1600 - 2200

Altezza Neve (cm)	Neve al suolo	Neve Fresca	Quota (mslm)
	92	00	1913
	55	00	1820

VALANGHE OSSERVATE: Nessuna valanga.

PREVISIONI 05/03/2026

GRADO DI PERICOLO: MODERATO 2

SITUAZIONE TIPO: passaggio da poca a molta neve.

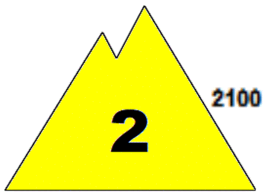

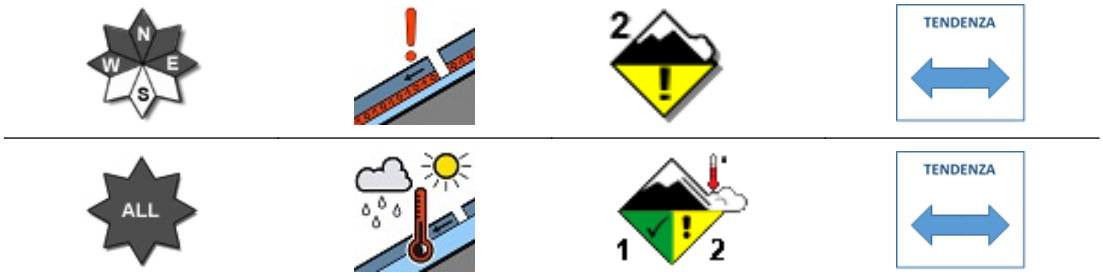

SITUAZIONE TIPO: situazione primaverile.

MANTO NEVOSO: La stabilità del manto nevoso è scarsa su alcuni punti (aree) per versanti da ovest a est al di sopra di 2100 mslm, possibili valanghe di dimensioni medie.
La stabilità del manto nevoso è scarsa su alcuni punti (aree) per tutte le esposizioni al di sotto di 2100 mslm, possibili valanghe di dimensioni medie.

AVVERTENZE

Il rialzo termico diurno richiede un'attenta valutazione temporale dell'escursione che eviti l'attraversamento di pendii ripidi nelle ore più calde della giornata.

SCALA EUROPEA DEL GRADO DI PERICOLO VALANGHE

LEGENDA PROBLEMA

Bollettino realizzato su scala sinottica-regionale (standard EAWS). La sua valutazione non può escludere in alcun modo la necessità di una seria e capace valutazione locale del pericolo (singolo pendio) che può essere anche sensibilmente diverso. Le previsioni meteorologiche sono relative all'orario UTC (per l'Italia +1 in inverno e +2 in estate).

MINISTERO DELLA DIFESA

meteomont
Servizio Nazionale di previsione neve e valanghe

EAWS EUROPEAN AVALANCHE WARNING SERVICES

CARABINIERI

In collaborazione con: arpav

DOLOMITI MERIDIONALI

PREVISIONE METEO

Quota		05/03/2026 h6:00	05/03/2026 h12:00	05/03/2026 h18:00
1000	Venti	01 Nodi da S-Ovest	01 Nodi da Est	02 Nodi da Sud
	Temperature	+04 °C	+05 °C	+04 °C
	Temp.percepita	4 °C	5 °C	4 °C
2000	Venti	01 Nodi da S-Ovest	02 Nodi da S-Ovest	01 Nodi da S-Ovest
	Temperature	+00 °C	+02 °C	+02 °C
	Temp.percepita	0 °C	2 °C	2 °C
3000	Venti	02 nodi da N-Ovest	05 Nodi da Ovest	05 nodi da Ovest
	Temperature	-03 °C	-03 °C	-01 °C
	Temp.percepita	-3 °C	-7 °C	-4 °C
Zero termico		2100-2300 m.	2500-2700 m.	2600-2800 m.
Fenomeno		—	—	—
Stato del cielo				

LEGENDA FENOMENI

— Assenza Fenomeni · Nebbia · Foschia · Pioggia debole · Pioggia moderata · Pioggia forte · Temporali

Nevicata debole · Nevicata moderata · Nevicata forte

STATO DEL CIELO

Sereno · Poco nuvoloso · Nuvoloso · Molto nuvoloso · Coperto

Parametri meteonivometrici registrati presso i campi di rilevamento il 04/03/2026.

Località	Comune	Quota (m.s.l.m.)	Altezza neve (cm)	Neve caduta nelle 24 ore (cm)	Temp. Min (°C)	Temp. Max (°C)	Condizioni del tempo
LE BUSE	Falcade (BL)	1820	55	0	-4	+15	Assenza di precipitazioni
PESCUL -RIF. FERTAZZA	Selva di Cadore (BL)	1860	62	3	N.P.	N.P.	Assenza di precipitazioni
COL DEI BALDI *	Selva di Cadore (BL)	1920	92	0	-3	+13	Assenza di precipitazioni
P.SO PADON	Livinallongo del Col di Lana (BL)	2369	65	0	-6	+10	Assenza di precipitazioni
SOTTO PIZ SERAUTA *	Rocca Pietore (BL)	2872	320	0	N.P.	N.P.	Assenza di precipitazioni

(*) Rilievi fuori campo

L'INFORMAZIONE E' PREVENZIONE - LEGGI L'ATTUALE GRADO DI PERICOLO VALANGHE!

IL CAPO DEL CENTRO NAZIONALE METEOMONT
(Ten. Col. RFI Emanuela Gini)
FIRMA AUTOGRAFA OMESSA AI SENSI
DELL'ART.3 DEL D.LGS N.39/1993