# TERMINILLO MONTI REATINI E LAGA OVEST

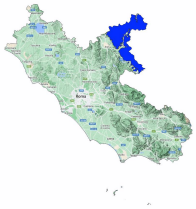

Bollettino Valanghe N. 304/2026 del 03/03/2026 ore 14.00
Validità 48 ore prossima emissione 04/03/2026

**A cura del Servizio METEOMONT dell'ARMA dei CARABINIERI**
**In collaborazione con Servizio Meteorologico dell'Aeronautica militare**

## SITUAZIONE alle 14:00 del 03/03/2026

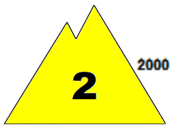


**SITUAZIONE TIPO: passaggio da poca a molta neve.**

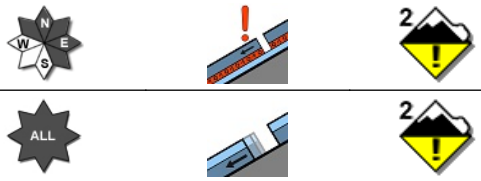


**SITUAZIONE TIPO: neve da slittamento.**

| Quota neve (mslm) | Nord | Sud |
|---|---|---|
| | 1600 | 1700 |

| Altezza Neve (cm) | Neve al suolo | Neve Fresca | Quota (mslm) |
|---|---|---|---|
| | 044 | 000 | 1770 |
| | 000 | 000 | 1350 |

**VALANGHE OSSERVATE: Nessuna valanga.**

## PREVISIONI 04/03/2026

## GRADO DI PERICOLO: MODERATO 2

## SITUAZIONE TIPO: passaggio da poca a molta neve.

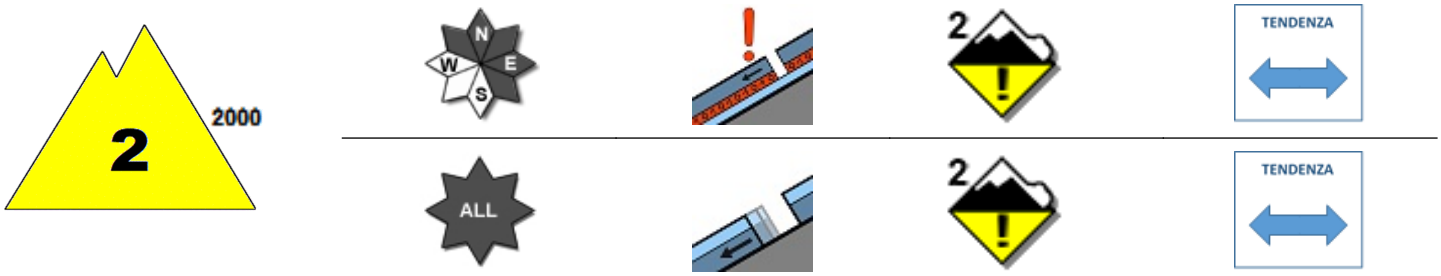


## SITUAZIONE TIPO: neve da slittamento.

**MANTO NEVOSO: La stabilità del manto nevoso è discreta su alcuni punti (aree) per versanti da nord ovest a sud est compresi al di sopra di 2000 mslm, possibili valanghe di dimensioni medie.**
**La stabilità del manto nevoso è discreta su alcuni punti (aree) per tutte le esposizioni al di sotto di 2000 mslm, possibili valanghe di dimensioni medie.**

## AVVERTENZE

Viste le condizioni del manto nevoso, le attività al di fuori delle piste battute e segnalate richiedono buone capacità di valutazione del pericolo locale.

## SCALA EUROPEA DEL GRADO DI PERICOLO VALANGHE

## LEGENDA PROBLEMA

**Bollettino realizzato su scala sinottica-regionale (standard EAWS). La sua valutazione non può escludere in alcun modo la necessità di una seria e capace valutazione locale del pericolo (singolo pendio) che può essere anche sensibilmente diverso. Le previsioni meteorologiche sono relative all'orario UTC (per l'Italia +1 in inverno e +2 in estate).**

MINISTERO DELLA DIFESA

meteomont
Servizio Nazionale di previsione neve e valanghe

EAWS EUROPEAN AVALANCHE WARNING SERVICES

CARABINIERI

# TERMINILLO MONTI REATINI E LAGA OVEST

## PREVISIONE METEO

| Quota | | 04/03/2026 h6:00 | 04/03/2026 h12:00 | 04/03/2026 h18:00 |
|---|---|---|---|---|
| 1000 | Venti | 02 Nodi da S-Ovest | 02 Nodi da S-Ovest | 01 Nodi da Sud |
| | Temperature | +05 °C | +07 °C | +06 °C |
| | Temp.percepita | 5 °C | 7 °C | 6 °C |
| 2000 | Venti | 04 Nodi da S-Ovest | 04 Nodi da S-Ovest | 01 Nodi da S-Ovest |
| | Temperature | +02 °C | +02 °C | +03 °C |
| | Temp.percepita | -0 °C | -0 °C | 3 °C |
| 3000 | Venti | 06 Nodi da Ovest | 05 Nodi da Ovest | 02 nodi da Ovest |
| | Temperature | -03 °C | -04 °C | -04 °C |
| | Temp.percepita | -7 °C | -8 °C | -4 °C |
| Zero termico | | 2300-2500 m. | 2300-2500 m. | 2300-2500 m. |
| Fenomeno | | — | — | — |
| Stato del cielo | | | | |

## LEGENDA FENOMENI

— Assenza Fenomeni · Nebbia · Foschia · Pioggia debole · Pioggia moderata · Pioggia forte · Temporali

Nevicata debole · Nevicata moderata · Nevicata forte

## STATO DEL CIELO

Sereno · Poco nuvoloso · Nuvoloso · Molto nuvoloso · Coperto

## Parametri meteonivometrici registrati presso i campi di rilevamento il 03/03/2026.

| Località | Comune | Quota (m.s.l.m.) | Altezza neve (cm) | Neve caduta nelle 24 ore (cm) | Temp. Min (°C) | Temp. Max (°C) | Condizioni del tempo |
|---|---|---|---|---|---|---|---|
| PESCHIERE | Amatrice (RI) | 1270 | 0 | 0 | +2 | +10 | Assenza di precipitazioni |
| M. CAIDURO | Cittareale (RI) | 1300 | 0 | 0 | +2 | +9 | Assenza di precipitazioni |
| VALLONINA | Leonessa (RI) | 1350 | 0 | 0 | +1 | +10 | Assenza di precipitazioni |
| GIRO DELL'ANELLO - VILLA CHIGI * | Micigliano (RI) | 1773 | 44 | 0 | N.P. | N.P. | Assenza di precipitazioni |

(*) Rilievi fuori campo

**L'INFORMAZIONE E' PREVENZIONE - LEGGI L'ATTUALE GRADO DI PERICOLO VALANGHE!**

IL CAPO DEL CENTRO NAZIONALE METEOMONT
(Ten. Col. RFI Emanuela Gini)
FIRMA AUTOGRAFA OMESSA AI SENSI
DELL'ART.3 DEL D.LGS N.39/1993

Bollettino realizzato su scala sinottica-regionale (standard EAWS). La sua valutazione non può escludere in alcun modo la necessità di una seria e capace valutazione locale del pericolo (singolo pendio) che può essere anche sensibilmente diverso. Le previsioni meteorologiche sono relative all'orario UTC (per l'Italia +1 in inverno e +2 in estate).