Bulletin d'estimation du risque d'avalanche
(valable en dehors des pistes balisées et ouvertes)

MASSIF : Aure Louron

Rédigé le mercredi 4 mars 2026 à 16h

Estimation des risques pour le : JEUDI 05 MARS

AVALANCHES DE FOND, QUELQUES NOUVELLES PLAQUES EN HAUTE-MONTAGNE.

2

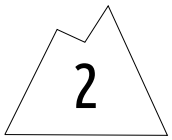

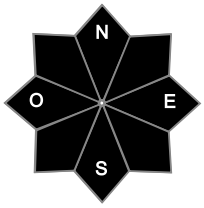

glissement/ plaques

Indices de risque : 5 très fort - 4 fort - 3 marqué - 2 limité - 1 faible -- En noir : les pentes les plus dangereuses

Indice de risque limité.

Départs spontanés : Avalanches de fond.

Déclenchements provoqués : Quelques nouvelles plaques en haute-montagne

Stabilité du manteau neigeux

Situation avalancheuse typique : avalanches de fond neige ventée

Départs spontanés : En neige humide. **Risque d'avalanches de fond (de glissement)**, plus présent en journée, possible **en toutes orientations** en moyenne montagne mais surtout en versants ensoleillés plus haut. Important l'intégralité du manteau, elles peuvent atteindre une taille moyenne à grande.
Signes parfois à observer : **gueules de baleine** (fissures qui s'ouvrent dans le manteau perpendiculairement à la pente). Trouées d'avalanche récentes jusqu'à l'herbe, à proximité.
Des départs ponctuels en versants ensoleillés sont aussi attendus, mais restent de tailles petites à moyennes, quelques rares départs de plaques en pentes raides avec les faibles apports neigeux de l'après-midi, taille 1.

Déclenchements provoqués : **Au-dessus de 2250 m vers les pentes d'un large secteur Nord**, le manteau neigeux est encore hivernal. De nouvelles petites plaques fragiles sont créent par les chutes de neige en après-midi, possibles avalanche de taille 1 par faible sollicitation.
Des couches fragiles sont enfouies dans le manteau neigeux, souvent difficilement sollicitables à cause de leur profondeur, mais le déclenchement d'une avalanche est encore possible aux zones où le manteau est plus mince, rapprochant les couches fragiles de la surface : entrées des combes, ruptures de pentes par exemple.

Autres : Les expositions nord d'altitude, en particulier nord-ouest sont souvent glacées le matin et très glissantes.

Qualité de la neige

La fonte est faible en nord mais les versants sud se dégarnissent peu à peu, l'enneigement est bon au-dessus de 1800 m en nord mais bien irrégulièrement réparti, crêtes dégarnies en particulier à l'ouest, combes plus chargées et corniches restant souvent imposantes.
Limites skiables : à partir de 1600/1700 m.
État de la neige : Manteau printanier en sud et sous 2200/2300 m en nord, regelé le matin, ramollissant encore sous des éclaircies en matinée. En nord, au-dessus de 2250 m, alternance de neige sèche et meuble et de zones en neige très dure ou en glace. Une petite couche de neige vient se déposer au-dessus de 2300 m en après-midi et soirée.

Aperçu météo pour le jeudi 05 mars

	nuit	matin	après-midi	soir

Ciel voilé en matinée, s'ennuageant rapidement en après-midi avec des pluies et un ciel devenant bouché en flux de sud-est modéré, ainsi que la nuit..

Pluie-Neige			2 400 m	2 300 m
Iso 0 °C	2 800 m	2 700 m	2 600 m	2 400 m
Vent 1500 m	↑ 30 km/h	↑ 25 km/h	↓ 20 km/h	↙ 20 km/h
Vent 3000 m	↑ 45 km/h	↖ 45 km/h	← 40 km/h	↖ 35 km/h

Épaisseur de neige hors-piste

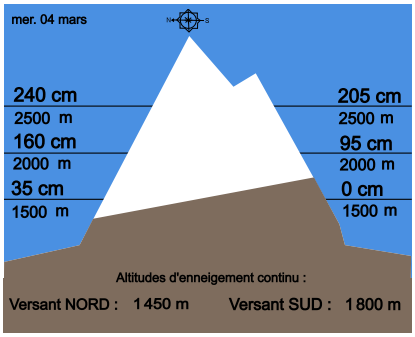

Précipitations à 1800 m

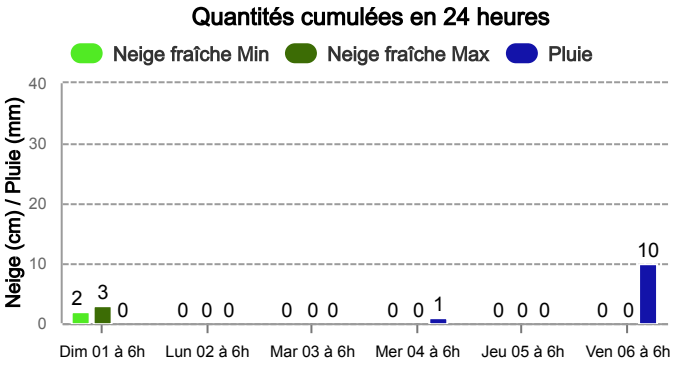

Tendance du vendredi 06 mars

2

Indice de risque limité

Conditions similaires avec des apports neigeux équivalents en après-midi et soirée.

Pour consulter la vigilance en cours, veuillez vous rendre sur le site https://vigilance.meteofrance.fr/fr

Météo-France - 73 avenue de Paris, 94165 Saint-Mandé cedex - Contact : contact@meteo.fr

Rédigé par Météo-France avec la contribution des observateurs du réseau nivo-météorologiques. Partenariat : ANMSM (Maires de Stations de Montagne), DSF (Domaines Skiables de France), ADSP (Directeurs de Pistes et de la Sécurité des Stations de Sports d'Hiver) et autres acteurs de la montagne.

Bulletin neige & avalanches par téléphone au 0 892 68 10 20 Service 0,35 € / min + prix appel

RÉPUBLIQUE FRANÇAISE
Liberté Égalité Fraternité

METEO FRANCE
À VOS CÔTÉS, DANS UN CLIMAT QUI CHANGE

Bulletin d'estimation du risque d'avalanche

(valable en dehors des pistes balisées et ouvertes)

MASSIF : Aure Louron

Rédigé le mercredi 4 mars 2026 à 16h

Conditions nivo-météo des 7 derniers jours

	jeu. 26/02				ven. 27/02				sam. 28/02				dim. 01/03				lun. 02/03				mar. 03/03				mer. 04/03			
	03h	09h	15h	21h	03h	09h	15h	21h	03h	09h	15h	21h	03h	09h	15h	21h	03h	09h	15h	21h	03h	09h	15h	21h	03h	09h	15h	21h
Météo																												
Vent (km/h)	20	25	30	40	30	30	30	40	45	45	25	15	25	40	55	60	60	50	35	30	20	15	15	15	25	35	45	45
à 3000m																												
Vent (km/h)	10	15	15	25	15	20	20	10	10	10	15	5	10	20	25	35	35	30	20	15	20	10	10	10	10	20	25	30
à 1500m																												

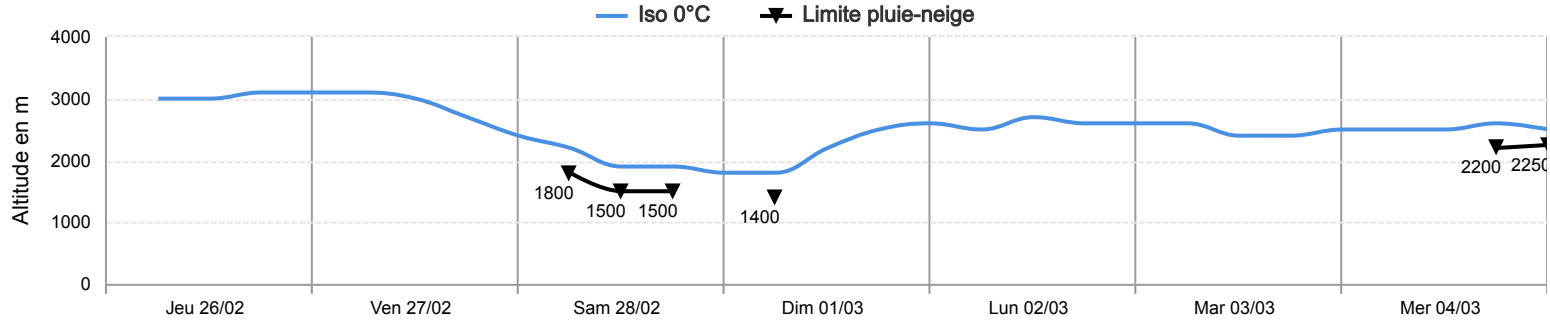

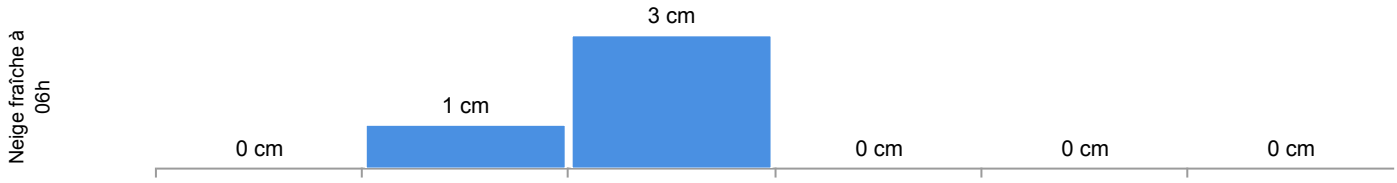

Risque d'avalanche	jeu. 26/02	ven. 27/02	sam. 28/02	dim. 01/03	lun. 02/03	mar. 03/03	mer. 04/03
	2	2	2	2	2	2	2

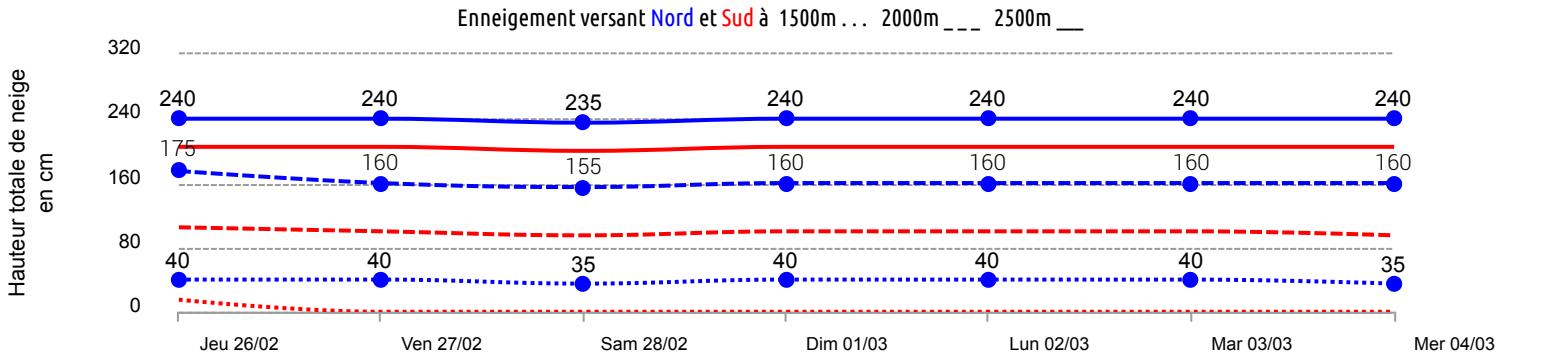

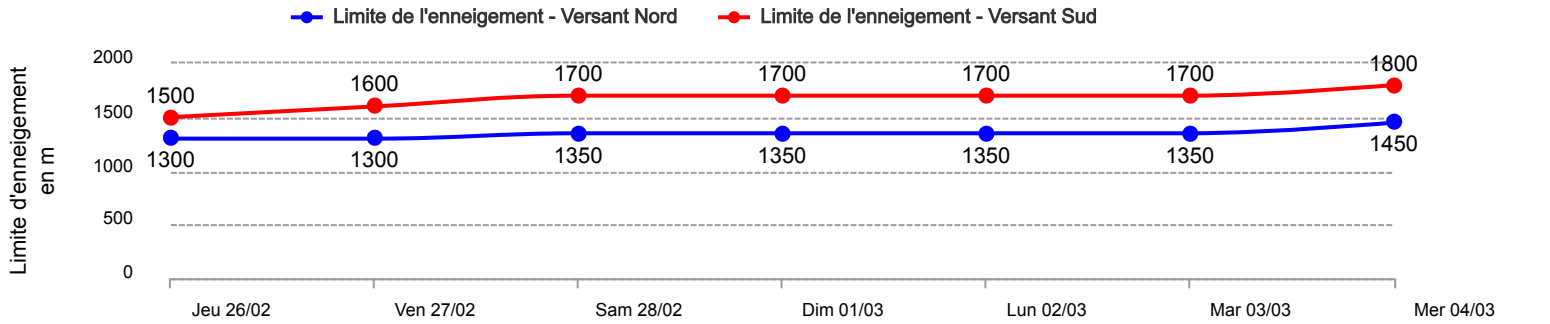

Pour consulter la vigilance en cours, veuillez vous rendre sur le site https://vigilance.meteofrance.fr/fr

Météo-France - 73 avenue de Paris, 94165 Saint-Mandé cedex - Contact : contact@meteo.fr

Rédigé par Météo-France avec la contribution des observateurs du réseau nivo-météorologiques. Partenariat : ANMSM (Maires de Stations de Montagne), DSF (Domaines Skiables de France), ADSP (Directeurs de Pistes et de la Sécurité des Stations de Sports d'Hiver) et autres acteurs de la montagne.

Bulletin neige & avalanches par téléphone au
0 892 68 10 20 Service 0,35 € / min + prix appel