Bulletin d'estimation du risque d'avalanche

(valable en dehors des pistes balisées et ouvertes)

MASSIF : Capcir Puymorens

Rédigé le mercredi 4 mars 2026 à 16h

Estimation des risques pour le : JEUDI 05 MARS

MANTEAU NEIGEUX PRINTANIER ET RARES STRUCTURES DE PLAQUES EN NORD D'ALTITUDE.

2

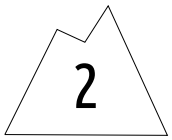

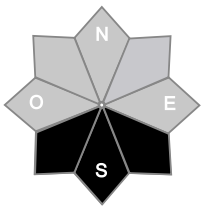

avalanches de fond

Indice de risque limité.

Départs spontanés : Avalanches de fond, rarement grandes.

Déclenchements provoqués : Structures de plaques encore présentes difficilement déclenchables.

Indices de risque : 5 très fort - 4 fort - 3 marqué - 2 limité - 1 faible -- En noir : les pentes les plus dangereuses

Stabilité du manteau neigeux

Situation avalancheuse typique : avalanches de fond couche fragile persistante

Départs spontanés :
De rares, mais parfois épaisses avalanches de fond peuvent se produire en mobilisant des quantités conséquentes de neige lourde. Il est fait état, dans de nombreuses orientations et plutôt sous 2200 m, de larges fissures visibles (gueules de baleine) dans des pentes au sol souvent lisse, signes avant-coureurs de telles avalanches. Le départ de ces avalanches de fond est plus fréquent de l'après-midi à la soirée mais peut aussi se produire à d'autres moments de la journée. Les petites pluies jusqu'à 2200m d'altitude attendues en soirée de jeudi peuvent être un phénomène déclencheur, elles sont plus abondantes sur le Madres et le Capcir où l'activité avalancheuse pourra être plus significative.

Déclenchements provoqués :
Quelques plaques sont encore en place au-dessus de 2200/2400 m dans les secteurs restés en neige froide, donc plutôt orientés nord. Ces plaques sont souvent épaisses et dures en altitude et deviennent de plus en plus difficilement déclenchables. Dans certaines conditions, en bordure de couloir raide et froid, une plaque de neige dure plu fine peut rompre avec propagation avec une couche fragile plus proche de la surface.
Observables : neige travaillée par le vent en surface, corniche surplombant la pente.

Autre: Risque de glissade/dévissage en raison de la présence de neige parfois très dure voire de glace vive notamment sur les crêtes pelées par le vent.

Qualité de la neige

Enneigement :
L'enneigement est encore légèrement excédentaire dès la moyenne montagne après les nombreuses perturbations neigeuses depuis le début de l'année. Les vallons ombragés sont encore bien enneigés avec des quantités de neige importantes dès 1400 m notamment en versant Est et nord.
La limite skiable remonte autour de 1500 à 1600m plein Sud alors que certaines vallées ombragées sont encore enneigées dès 1200 à 1300m. A haute altitude, les pentes Ouest ont souvent été rabotées par le vent.

Qualité de la neige :
Mercredi matin, regel nocturne moyen après une nuit douce et voilée. En journée, reprise de l'humidification sous les nuages avec une neige devenant lourde et humide jusqu'à 2200/2400m en tous versants. La neige reste froide et compacte en versant Nord au dessus de 2300 à 2500m environ.
Par contre, les crêtes et sommets sont souvent pelés ou en neige dure, parfois en glace, en versants Ouest principalement. L'arrivée d'un peu de neige en altitude jeudi soir rendra ce manteau neigeux plus agréable à skier mais la pluie risque de le pourrir en dessous de 2000m.

Aperçu météo pour le jeudi 05 mars

	nuit	matin	après-midi	soir

Doux, nuageux, quelques gouttes sur Puymorens, pluies plus abondantes sur le Madres...

Pluie-Neige		2 100 m	2 200 m	2 100 m
Iso 0 °C	2 700 m	2 700 m	2 500 m	2 400 m
Vent 2000 m	↑ 20 km/h	↖ 25 km/h	↖ 30 km/h	↖ 25 km/h
Vent 3000 m	↑ 35 km/h	↖ 35 km/h	↖ 40 km/h	← 30 km/h

Pour consulter la vigilance en cours, veuillez vous rendre sur le site https://vigilance.meteofrance.fr/fr

Météo-France - 73 avenue de Paris, 94165 Saint-Mandé cedex - Contact : contact@meteo.fr

Rédigé par Météo-France avec la contribution des observateurs du réseau nivo-météorologiques. Partenariat : ANMSM (Maires de Stations de Montagne), DSF (Domaines Skiables de France), ADSP (Directeurs de Pistes et de la Sécurité des Stations de Sports d'Hiver) et autres acteurs de la montagne.

Bulletin neige & avalanches par téléphone au
0 892 68 10 20 Service 0,35 € / min + prix appel

RÉPUBLIQUE FRANÇAISE
Liberté Égalité Fraternité

METEO FRANCE
À VOS CÔTÉS, DANS UN CLIMAT QUI CHANGE

Bulletin d'estimation du risque d'avalanche

(valable en dehors des pistes balisées et ouvertes)

MASSIF : Capcir Puymorens

Rédigé le mercredi 4 mars 2026 à 16h

Épaisseur de neige hors-piste

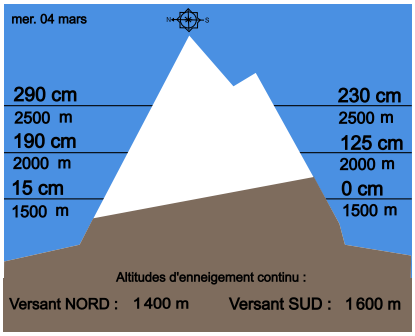

Précipitations à 1800 m

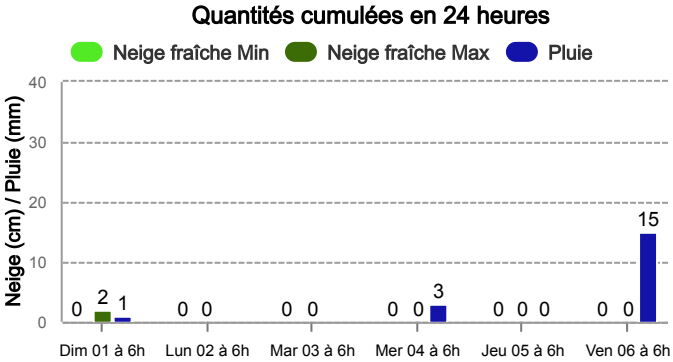

Tendance du vendredi 06 mars

Indice de risque limité

Maintient d'un risque limité en général, éventuel passage en risque 3 suivant les précipitations attendues vendredi sur le Capcir.

Pour consulter la vigilance en cours, veuillez vous rendre sur le site https://vigilance.meteofrance.fr/fr

Météo-France - 73 avenue de Paris, 94165 Saint-Mandé cedex - Contact : contact@meteo.fr

Rédigé par Météo-France avec la contribution des observateurs du réseau nivo-météorologiques. Partenariat : ANMSM (Maires de Stations de Montagne), DSF (Domaines Skiables de France), ADSP (Directeurs de Pistes et de la Sécurité des Stations de Sports d'Hiver) et autres acteurs de la montagne.

Bulletin neige & avalanches par téléphone au

0 892 68 10 20 Service 0,35 € / min + prix appel

RÉPUBLIQUE FRANÇAISE
Liberté Égalité Fraternité

METEO FRANCE
À VOS CÔTÉS, DANS UN CLIMAT QUI CHANGE

Bulletin d'estimation du risque d'avalanche

(valable en dehors des pistes balisées et ouvertes)

MASSIF : Capcir Puymorens

Rédigé le mercredi 4 mars 2026 à 16h

Conditions nivo-météo des 7 derniers jours

	jeu. 26/02				ven. 27/02				sam. 28/02				dim. 01/03				lun. 02/03				mar. 03/03				mer. 04/03			
	03h	09h	15h	21h	03h	09h	15h	21h	03h	09h	15h	21h	03h	09h	15h	21h	03h	09h	15h	21h	03h	09h	15h	21h	03h	09h	15h	21h
Météo																												
Vent (km/h)	20	15	15	15	20	20	25	30	20	20	20	20	20	20	25	20	30	45	45	35	35	25	20	15	25	20	35	30
à 3000m																												
Vent (km/h)	10	10	10	10	15	15	15	20	10	10	15	10	10	15	20	15	20	30	35	25	25	20	20	10	15	15	25	20
à 2000m																												

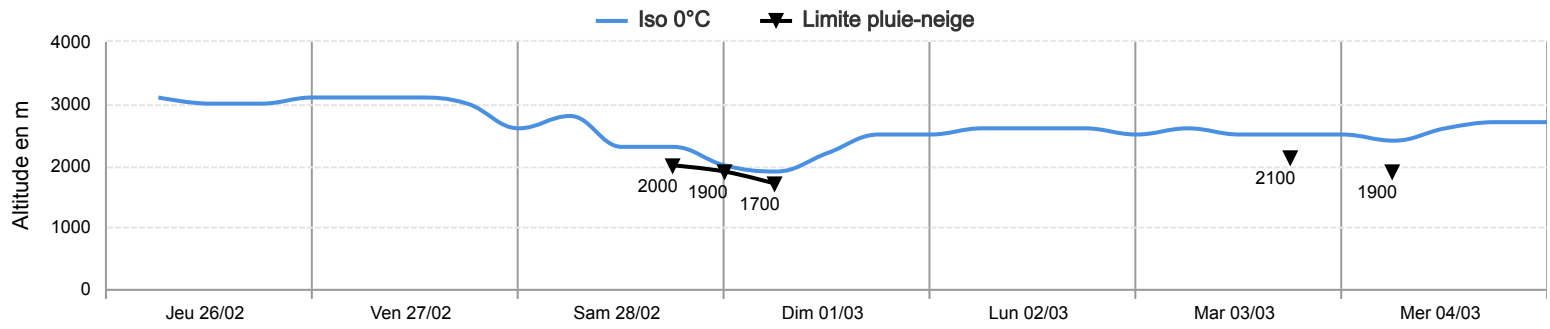

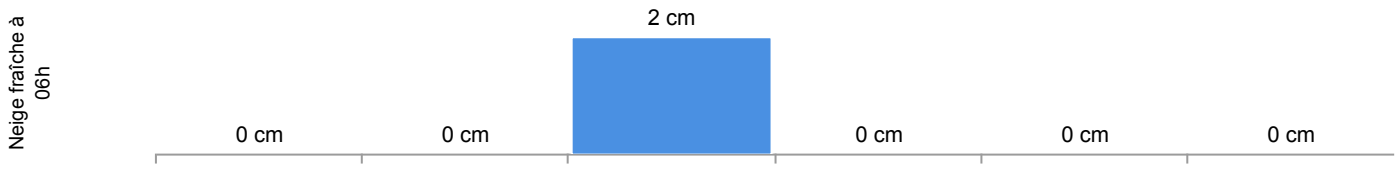

Risque d'avalanche	jeu. 26/02	ven. 27/02	sam. 28/02	dim. 01/03	lun. 02/03	mar. 03/03	mer. 04/03
	2	2	2	2	2	2	2

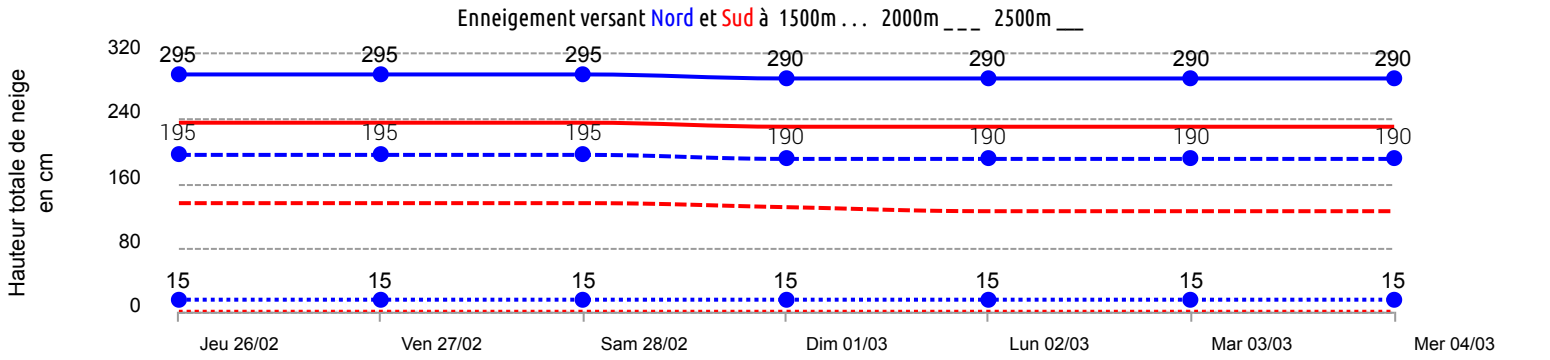

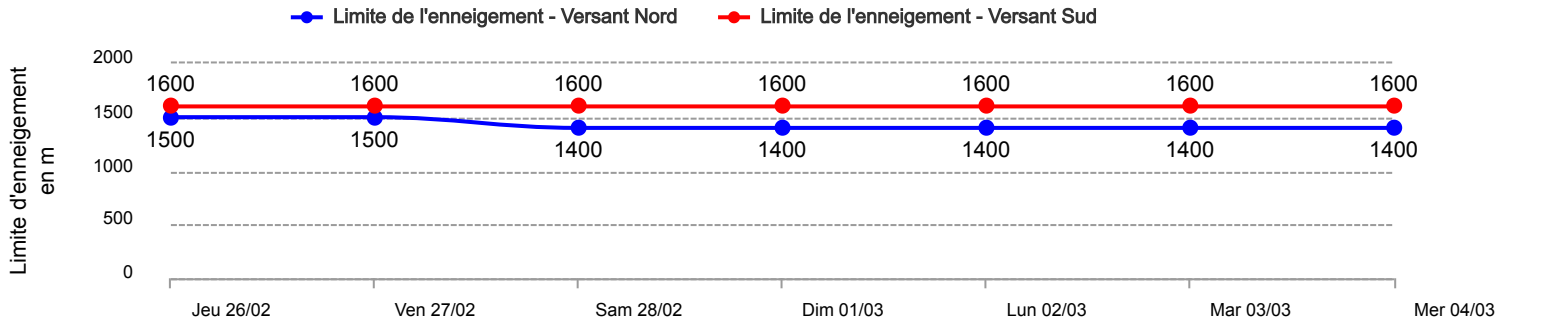

Pour consulter la vigilance en cours, veuillez vous rendre sur le site https://vigilance.meteofrance.fr/fr

Météo-France - 73 avenue de Paris, 94165 Saint-Mandé cedex - Contact : contact@meteo.fr

Rédigé par Météo-France avec la contribution des observateurs du réseau nivo-météorologiques. Partenariat : ANMSM (Maires de Stations de Montagne), DSF (Domaines Skiables de France), ADSP (Directeurs de Pistes et de la Sécurité des Stations de Sports d'Hiver) et autres acteurs de la montagne.

Bulletin neige & avalanches par téléphone au
0 892 68 10 20 Service 0,35 € / min + prix appel