Bulletin d'estimation du risque d'avalanche
(valable en dehors des pistes balisées et ouvertes)

MASSIF : Cerdagne Canigou

Rédigé le mercredi 4 mars 2026 à 16h

Estimation des risques pour le : JEUDI 05 MARS

MANTEAU NEIGEUX STABLE EN MATINÉE, DÉGRADATION PLUVIO-NEIGEUSE EN SOIRÉE POUVANT PROVOQUER DE GROSSES AVALANCHES DE FOND.

3

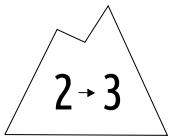

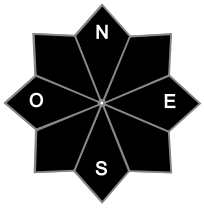

Sur Canigou

Indices de risque : 5 très fort - 4 fort - 3 marqué - 2 limité - 1 faible -- En noir : les pentes les plus dangereuses

Indice de risque limité évoluant en marqué.

Départs spontanés : Avalanches de fond possibles par humidification, augmentation du risque sous la pluie

Déclenchements provoqués : Peu probables.

Stabilité du manteau neigeux

Situation avalancheuse typique : neige humide avalanches de fond

Départs spontanés :
Peu probable le matin puis l'activité avalancheuse peut reprendre au fil de la journée sous les nuages puis surtout sous les précipitations attendues en fin d'après-midi devenant abondantes du Vallespir au Canigou en soirée et la nuit suivante. Le risque est d'autant plus marqué sous la limite pluie-neige soit 2000 à 2200m où le manteau neigeux déjà bien humide va se gorger d'eau jusqu'à saturation, une grande avalanche (T3) est alors possible. Plus haut, quelques avalanches de neige humide peuvent se produire en surface entre 2000 et 2400m environ et encore plus haut des coulées de neige sèche sont envisageables par accumulation en versant Nord principalement.

Déclenchements provoqués :
Peu probables ou alors par forte surcharge sur le manteau neigeux. Au fil de la soirée, de nouvelles accumulations se créent à haute altitude (>2400m) sous le vent de Sud à Sud-Est. Ces nouvelles structures de plaques peuvent être temporairement faciles à déclencher.

Autre: Risque de glissade/dévissage en raison de la présence de neige parfois très dure voire de glace vive notamment sur les crêtes pelées par le vent au dessus de 2500m.

Qualité de la neige

Enneigement :
L'enneigement est largement supérieur à celui des cinq dernières années et se situe au plus haut par rapport aux statistiques plus anciennes. Malgré la douceur de la semaine passée, la neige a plutôt bien résisté avec de bonnes quantités permettant de chausser dès 1500 à 1600m d'altitude. La limite skiable remonte doucement dans les pentes ensoleillées. Le manteau neigeux atteint rapidement 1m d'épaisseur et dépasse encore les 2m au dessus de 2200m.

Qualité de la neige :
Regel nocturne correct avec une neige dure et portante jeudi matin. L'arrivée de la perturbation en journée douce mais active humidifie fortement la neige en dessous de 2000m la rendant rapidement pourrie jusqu'en profondeur. De nouvelles chutes de neige ventées sont attendues à haute altitude. Proche des crêtes et sommet, l'enneigement reste très hétérogène avec des secteurs bien soufflés et parfois glacés, particulièrement sur les flancs ouest.

Aperçu météo pour le jeudi 05 mars

	nuit	matin	après-midi	soir

Nette dégradation jeudi après-midi puis la nuit suivante sur le Canigou.

	nuit	matin	après-midi	soir
Pluie-Neige		2 000 m	2 100 m	2 100 m
Iso 0 °C	2 700 m	2 600 m	2 500 m	2 400 m
Vent 2000 m	↖ 30 km/h	↖ 30 km/h	← 30 km/h	← 25 km/h
Vent 3000 m	↑ 45 km/h	← 50 km/h	← 50 km/h	↖ 50 km/h

Épaisseur de neige hors-piste

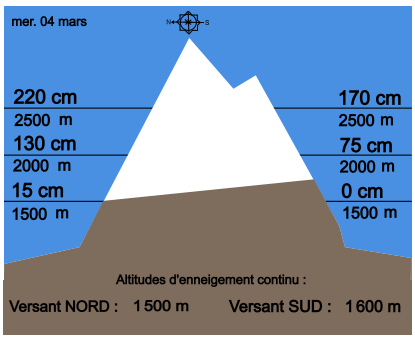

Précipitations à 1800 m

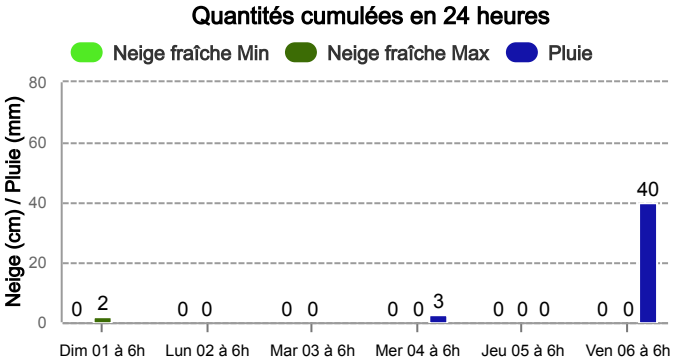

Tendance du vendredi 06 mars

4 **Indice de risque fort**

Probable passage en risque 4 vendredi sur le Canigou si les fortes précipitations se confirment.

Pour consulter la vigilance en cours, veuillez vous rendre sur le site https://vigilance.meteofrance.fr/fr

Météo-France - 73 avenue de Paris, 94165 Saint-Mandé cedex - Contact : contact@meteo.fr

Rédigé par Météo-France avec la contribution des observateurs du réseau nivo-météorologiques. Partenariat : ANMSM (Maires de Stations de Montagne), DSF (Domaines Skiables de France), ADSP (Directeurs de Pistes et de la Sécurité des Stations de Sports d'Hiver) et autres acteurs de la montagne.

Bulletin neige & avalanches par téléphone au **0 892 68 10 20** Service 0,35 € / min + prix appel

RÉPUBLIQUE FRANÇAISE
Liberté Égalité Fraternité

METEO FRANCE
À VOS CÔTÉS, DANS UN CLIMAT QUI CHANGE

Bulletin d'estimation du risque d'avalanche
(valable en dehors des pistes balisées et ouvertes)
MASSIF : Cerdagne Canigou

Rédigé le mercredi 4 mars 2026 à 16h

Conditions nivo-météo des 7 derniers jours

	jeu. 26/02				ven. 27/02				sam. 28/02				dim. 01/03				lun. 02/03				mar. 03/03				mer. 04/03			
	03h	09h	15h	21h	03h	09h	15h	21h	03h	09h	15h	21h	03h	09h	15h	21h	03h	09h	15h	21h	03h	09h	15h	21h	03h	09h	15h	21h
Météo																												
Vent (km/h)	20	15	15	15	20	20	25	30	30	30	30	20	20	25	25	25	40	50	50	40	45	35	25	25	40	35	40	25
à 3000m																												
Vent (km/h)	10	10	10	10	15	15	15	20	15	15	20	10	10	15	20	15	20	30	30	25	30	25	20	15	25	20	25	15
à 2000m																												

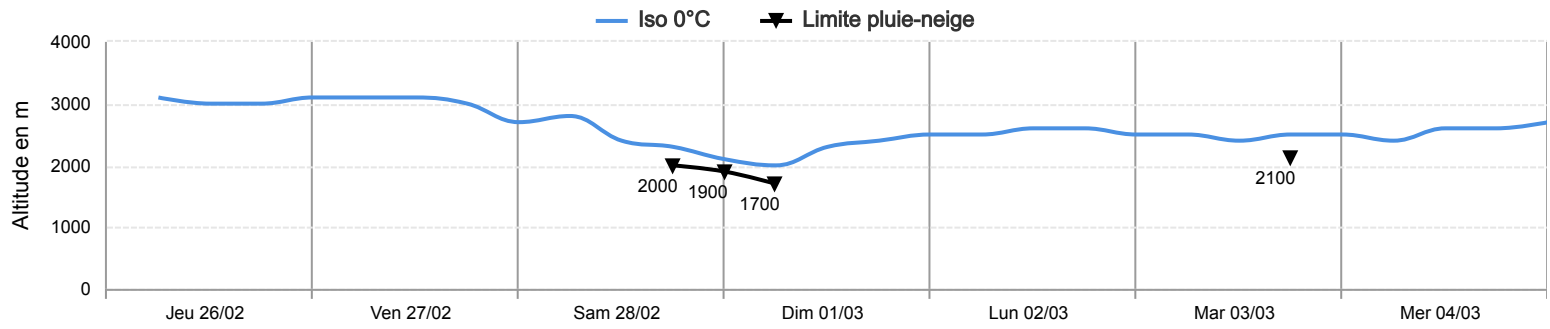

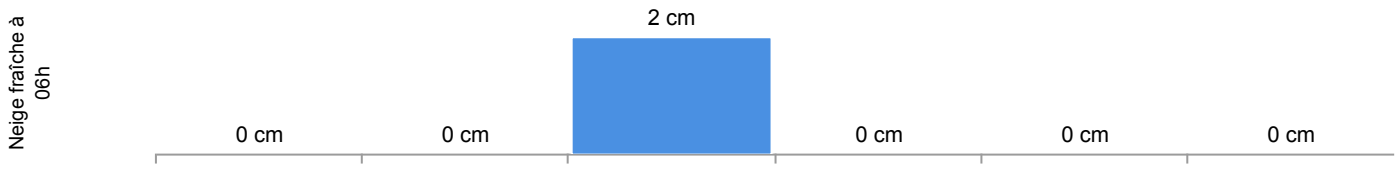

Risque d'avalanche	jeu. 26/02	ven. 27/02	sam. 28/02	dim. 01/03	lun. 02/03	mar. 03/03	mer. 04/03
	2	2	2	2	2	2	2

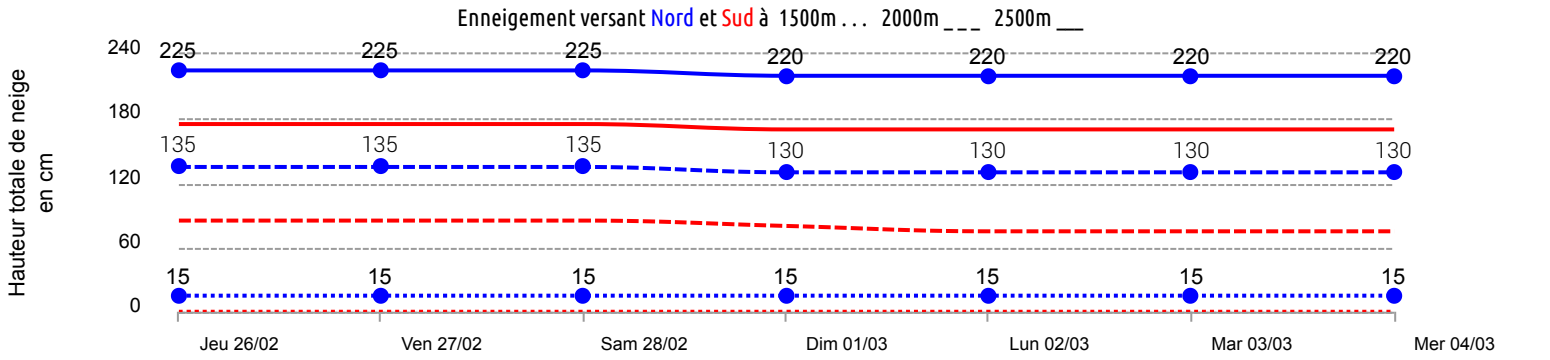

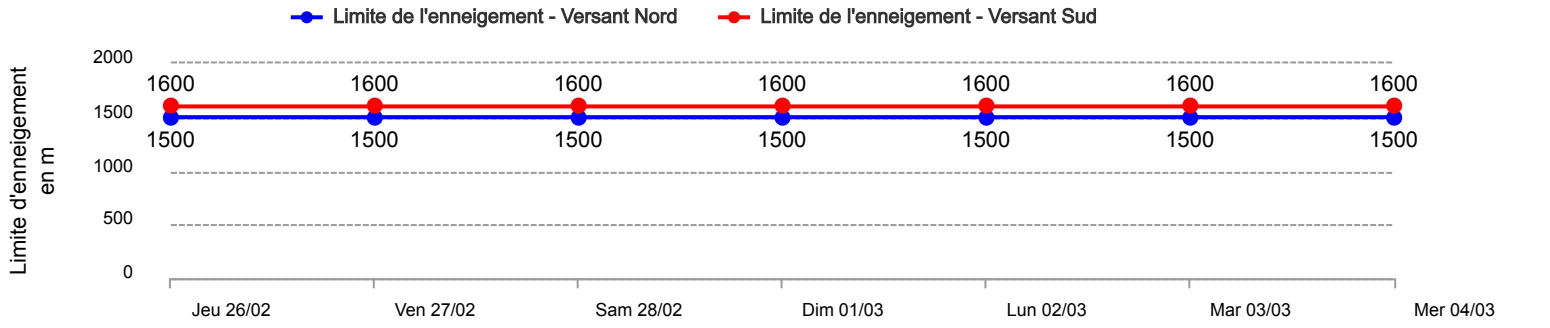

Pour consulter la vigilance en cours, veuillez vous rendre sur le site https://vigilance.meteofrance.fr/fr

Météo-France - 73 avenue de Paris, 94165 Saint-Mandé cedex - Contact : contact@meteo.fr

Rédigé par Météo-France avec la contribution des observateurs du réseau nivo-météorologiques. Partenariat : ANMSM (Maires de Stations de Montagne), DSF (Domaines Skiables de France), ADSP (Directeurs de Pistes et de la Sécurité des Stations de Sports d'Hiver) et autres acteurs de la montagne.

Bulletin neige & avalanches par téléphone au
0 892 68 10 20 Service 0,35 € / min + prix appel