GOBIERNO DE ESPAÑA
VICEPRESIDENCIA TERCERA DEL GOBIERNO
MINISTERIO PARA LA TRANSICIÓN ECOLÓGICA Y EL RETO DEMOGRÁFICO

Boletín de información nivológica y de peligro de aludes

Pirineo Catalán

aemet Agencia Estatal de Meteorología

jueves, 5 de marzo de 2026

Pronóstico hasta las 24 horas del viernes, día 6 de marzo

(Válido fuera de pistas de esquí balizadas y abiertas)

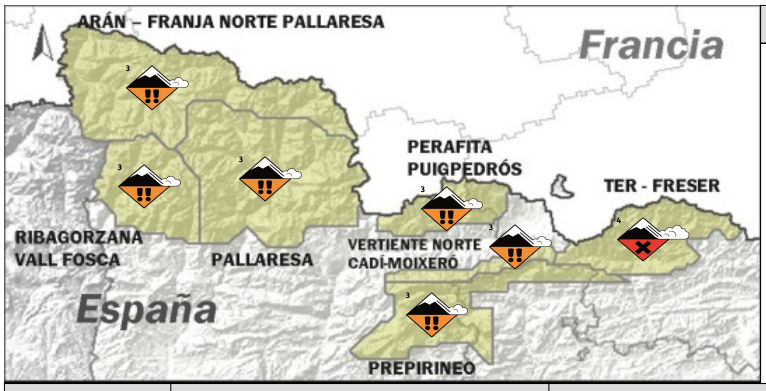

Problemas de aludes

- Placas de viento
- Nieve húmeda
- Deslizamientos basales

Macizo	Peligro	Problemas de aludes, cota, orientación, tamaño	Innivación observada (m)
Arán - Franja norte Pallaresa	3 Notable; 2→3 Por la tarde	Placas de viento: 2200, N O E S, 2 Deslizamientos basales: 2300, N O E S, 2	2026-03-05 N S Cota más baja caras N
Ribagorzana - Vall Fosca	3 Notable; 2→3 Por la tarde	Placas de viento: 2200, N O E S, 2 Deslizamientos basales: 2300, N O E S, 2	2026-03-05 N S Cota más baja caras N
Pallaresa	3 Notable; 2→3 Por la tarde	Placas de viento: 2200, N O E S, 2 Deslizamientos basales: 2300, N O E S, 2	2026-03-05 N S Cota más baja caras N

AEMET. Se autoriza la reproducción de su contenido citando la fuente.

Boletín de información nivológica y de peligro de aludes

Pirineo Catalán

Perafita - Puigpedrós	3 **Notable**	**Placas de viento** 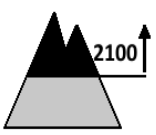 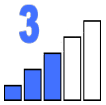 **Nieve húmeda** 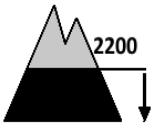 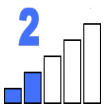	2026-03-05 Cota más baja caras N
Ter - Freser	4 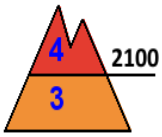 **Fuerte**	**Placas de viento** 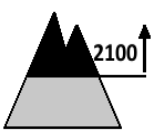 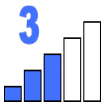 **Nieve húmeda** 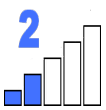	2026-03-05 Cota más baja caras N
Vertiente norte Cadí - Moixeró	3 **Notable**	**Placas de viento**  **Nieve húmeda** 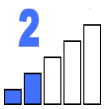	2026-03-05 Cota más baja caras N
Prepirineo	3 **Notable**	**Placas de viento** 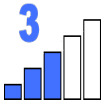 **Nieve húmeda** 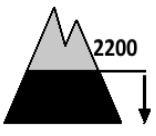 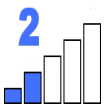	2026-03-05 Cota más baja caras N

Estado del manto y observaciones recientes

Ayer se registraron algunas precipitaciones débiles y ocasionales, en forma de nieve a partir del entorno de los 1900-2100 metros, que podrán haber añadido algún centímetro de nieve reciente en cotas altas. A pesar de esto, en la red de observación hoy se han registrado nuevas pérdidas notables de espesor, aunque estos continúan siendo superiores a lo que sería habitual a estas alturas de la temporada. Por encima de unos 2200 metros se superan los 150-200 cm en muchas zonas, aún más en ventisqueros, hoyas y otras zonas propensas a la acumulación.

AEMET. Se autoriza la reproducción de su contenido citando la fuente.

En cotas medias y bajas, así como en solanas a mayor altitud, el manto es primaveral y está humedecido en profundidad, sometido a ciclo de fusión-rehielo débil. En cotas altas, la nieve se mantiene más seca y aún podemos encontrar placas de viento que no se hayan estabilizado por completo. También en estas zonas podría persistir alguna capa débil enterrada que pueda seguir latente.

Evolución del manto y peligro de aludes para el viernes, día 6

Problemas de nieve reciente y placas de viento en cotas altas. Problemas de nieve húmeda y deslizamientos basales en cotas medias y bajas.

A lo largo de los días de hoy y mañana se esperan precipitaciones significativas, en forma de nieve por encima de unos 1900-2100 metros. De esta manera, en cotas altas se esperan acumulaciones de nieve reciente que podrían alcanzar los 50-80 cm en algunos enclaves del macizo del Ter-Freser y los 20-50 cm en otros enclaves de los macizos orientales. Sin embargo, en la mitad occidental se esperan acumulaciones de unos 10-20 cm. Con todo esto, serán probables los problemas de nieve reciente, con aludes naturales de tamaño pequeño (1, riesgo de caída), mediano (2, capaz de enterrar a una persona), o incluso grande (3, capaz de enterrar a un grupo de personas) en los macizos orientales. Además, las nevadas irán acompañadas de vientos fuertes de componente este, por lo que se espera que formen placas de viento a sotavento, preferentemente en orientaciones norte, oeste y sur. Estas estructuras de nueva formación podrán colapsar ante sobrecargas débiles (paso de un sólo esquiador), generando aludes de tamaño pequeño o mediano en los macizos occidentales, alcanzando el tamaño grande en los macizos orientales. Tampoco se descarta que pueda reactivarse alguna capa débil persistente, especialmente en zonas de manto más delgado o erosionado.

En cotas medias y bajas, las copiosas lluvias junto con la ausencia de rehielo nocturno agravarán el problema de nieve húmeda, siendo probables los aludes espontáneos de tamaño pequeño o mediano (localmente grande en los macizos orientales), así como los deslizamientos basales en zonas herbosas o de roca lisa, que podrían movilizar una cantidad de nieve considerable y alcanzar tamaño mediano o grande.

Predicción meteorológica para el viernes, día 6

Predominio de cielos muy nubosos o cubiertos, con visibilidad localmente reducida. Precipitaciones débiles o localmente moderadas en los macizos occidentales. En los orientales moderadas o localmente fuertes, a veces como chubascos, que podrán ser persistentes. Cota de nieve: 1900-2100 metros, descendiendo a últimas horas. Algunas tormentas podrán acompañar ocasionalmente a los chubascos. Temperaturas mínimas generalmente en ligero ascenso, salvo en el Arán, Ripollès y Prepirineo, donde descenderán ligeramente. Máximas en ligero o moderado descenso. Heladas débiles en la alta montaña. Viento fuerte en el tercio oriental y Prepirineo. En el resto, predominio de moderado de componente este, sin descartar rachas fuertes en cotas altas y zonas expuestas.

AEMET. Se autoriza la reproducción de su contenido citando la fuente.

Datos en la atmósfera libre:

Altitud de la isoterma de 0 ºC: 2300 m
Altitud de la isoterma de -10 ºC: 4000 m

Viento a 1500 m: SE 30 km/h
Viento a 3000 m: SE 60 km/h

Evolución para el sábado día 7

Nivel de peligro con pocos cambios.

Escala europea de peligro de aludes

Débil Limitado Notable Fuerte Muy Fuerte

Problemas de aludes

Nieve reciente Placas de viento Capas débiles persistentes Nieve húmeda Deslizamientos basales Sin problema evidente

Nota1: Se recuerda que, siempre que haya nieve, la ausencia total de peligro no existe. Hay que tener presente que en circunstancias desfavorables, con aludes de tamaño 1 (alud pequeño o colada) y tamaño 2 (alud mediano), se pueden sufrir severos daños personales.

Nota2: Los BPA se elaboran en base a información meteorológica así como al estado del manto nivoso a través de sondeos puntuales. Se advierte a los usuarios de la variabilidad de esta información al extrapolarla a zonas extensas de montaña. Por ello, AEMET no se hace responsable de su uso para la toma de decisiones que conciernen a la seguridad personal, ni de los riesgos físicos o materiales de ellas derivadas.

AEMET. Se autoriza la reproducción de su contenido citando la fuente.