GOBIERNO DE ESPAÑA
VICEPRESIDENCIA TERCERA DEL GOBIERNO
MINISTERIO PARA LA TRANSICIÓN ECOLÓGICA Y EL RETO DEMOGRÁFICO

Boletín de información nivológica y de peligro de aludes

Pirineo Navarro y Aragonés

aemet Agencia Estatal de Meteorología

jueves, 5 de marzo de 2026 (corrección)

Pronóstico hasta las 24 horas del viernes, día 6 de marzo

(Válido fuera de pistas de esquí balizadas y abiertas)

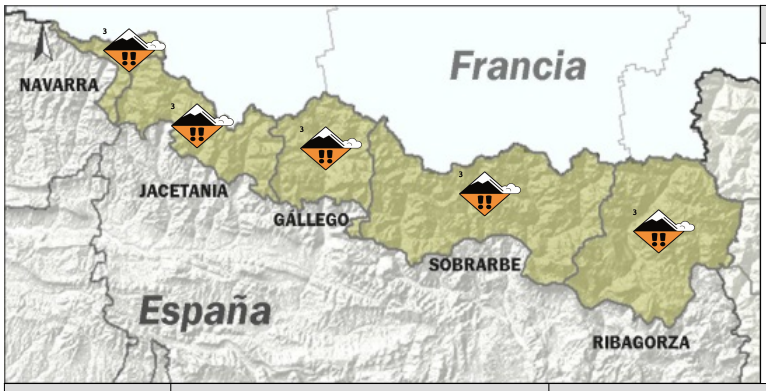

Problemas de aludes

Placas de viento

Deslizamientos basales

Macizo	Peligro	Problemas de aludes, cota, orientación, tamaño	Innivación observada (m)
Navarra	3 2→3 2000 2 Durante el día **Notable**	**Placas de viento** 2100 N O E S 2 **Deslizamientos basales** 2200 N O E S 2	2026-03-05 N S Cota más baja caras N
Jacetania	3 2→3 2000 2 Durante el día **Notable**	**Placas de viento** 2100 N O E S 2 **Deslizamientos basales** 2200 N O E S 2	2026-03-05 N S Cota más baja caras N
Gállego	3 2→3 2000 2 Durante el día **Notable**	**Placas de viento** 2100 N O E S 2 **Deslizamientos basales** 2200 N O E S 2	2026-03-05 N S Cota más baja caras N

AEMET. Se autoriza la reproducción de su contenido citando la fuente.

Sobrarbe	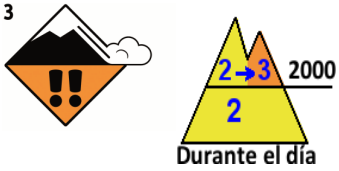 **Notable**	**Placas de viento** 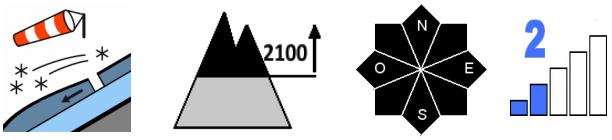 **Deslizamientos basales** 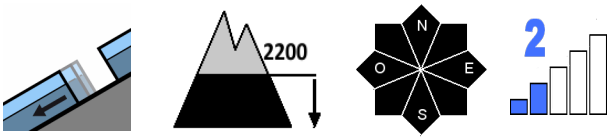	2026-03-05 Cota más baja caras N
Ribagorza	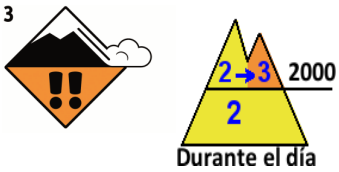 **Notable**	**Placas de viento** 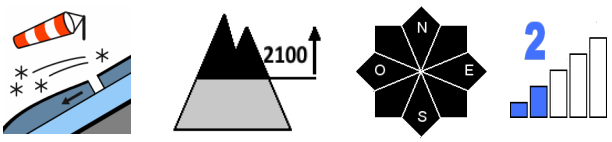 **Deslizamientos basales** 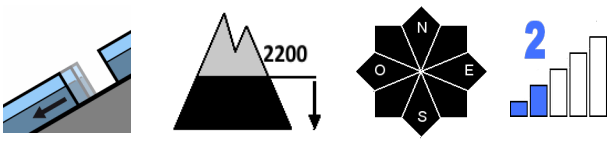	2026-03-05 Cota más baja caras N

Estado del manto y observaciones recientes

Ayer se registraron algunas precipitaciones débiles y ocasionales, en forma de nieve a partir del entorno de los 1800-2100 metros, que podrán haber añadido algún centímetro de nieve reciente en cotas altas. A pesar de esto, en la red de observación hoy se han registrado nuevas pérdidas notables de espesor, aunque estos continúan siendo superiores a lo que sería habitual a estas alturas de la temporada.

En general la nieve es continua desde los 1400 metros en orientaciones norte y desde los 1600-1700 metros en las sur. Aunque el manto es muy abundante desde cotas medias, se observa una asimetría norte-sur, con pérdidas notables en las solanas, donde incluso se pueden encontrar zonas desprovistas de nieve. Conforme ascendemos en altitud estos van incrementando, alcanzando los 160 cm a unos 1800 metros y los 2800 cm a unos 2300, e incluso los 4 metros en ventisqueros, hoyas y otras zonas propensas a la acumulación de cotas altas. Cabe destacar que la nieve reciente caída en días anteriores, se depositó con algo de polvo sahariano, empeorando así las condiciones de esquí.

En cotas medias y bajas, así como en solanas a mayor altitud, el manto es primaveral y está humedecido hasta su base por debajo de los 2200 metros, con ciclo de fusión-rehielo débil. En cotas altas, la nieve está generalmente seca y, en umbrías, algunas zonas localizadas al abrigo del viento aún conservan algunas placas de viento que pueden descansar sobre capas débiles de facetas o nieve granulada. Los tests apuntan que podrían desencadenarse ante sobrecargas fuertes. Asimismo, en la base del manto aún siguen presentes algunas capas débiles persistentes, generalmente inactivas.

Se han reportado algunas purgas pequeñas de nieve húmeda en cotas medias.

AEMET. Se autoriza la reproducción de su contenido citando la fuente.

Evolución del manto y peligro de aludes para el viernes, día 6

Problemas de nieve reciente y placas de viento en cotas altas. Problemas de nieve húmeda y deslizamientos basales en cotas medias y bajas.

Esta tarde se esperan nevadas por encima de los 2100 metros, que continuarán durante el día de mañana con una cota de nieve que descenderá al entorno de los 1800 metros. Así, se espera que al final de la jornada de mañana se puedan haber acumulado unos nuevos 10-20 cm de nieve reciente en cotas altas, sin descartar acumulados localmente superiores. Con todo esto, serán probables los problemas de nieve reciente, con aludes naturales de tamaño pequeño (1, riesgo de caída) o mediano (2, capaz de enterrar a una persona). Además, las nevadas irán acompañadas de vientos fuertes de componente este, por lo que se espera que formen placas de viento a sotavento, preferentemente en orientaciones norte, oeste y sur. Estas estructuras de nueva formación podrán colapsar ante sobrecargas débiles (paso de un sólo esquiador), generando aludes de tamaño pequeño o mediano. Dada la presencia en umbrías de algunas placas viejas o costras sobre capas débiles, la rotura de las placas recientes podría movilizar mayor cantidad de nieve y desencadenar aludes localmente grandes (3, capaz de enterrar a un grupo de personas). Tampoco se descarta que pueda reactivarse alguna capa débil persistente, especialmente en zonas de manto más delgado o erosionado.

En cotas medias y bajas, las lluvias copiosas junto con la ausencia de rehielo nocturno agravarán el problema de nieve húmeda, siendo probables los aludes espontáneos de tamaño pequeño o mediano, así como los deslizamientos basales en zonas herbosas o de roca lisa, que podrían movilizar una cantidad de nieve considerable y alcanzar tamaño mediano o localmente grande.

Predicción meteorológica para el viernes, día 6

Pirineo navarro:
Muy nuboso o cubierto, con visibilidad localmente reducida. Se esperan precipitaciones débiles o moderadas, en ocasiones en forma de chubasco. Cota de nieve en torno a 1700-1900 metros. Algunas tormentas podrán acompañar ocasionalmente a los chubascos. Temperaturas mínimas en ligero ascenso y máximas en moderado o notable descenso. Alguna helada débil en cumbres. Viento generalmente moderado de componente este, con rachas fuertes en cotas altas y zonas expuestas.

Pirineo aragonés:
Predominio de cielos muy nubosos o cubiertos, con visibilidad localmente reducida. Se esperan precipitaciones débiles o moderadas, en ocasiones en forma de chubasco. Cota de nieve en torno a 1800-2000 metros. Algunas tormentas podrían acompañar ocasionalmente a los chubascos. Temperaturas en descenso, ligero en las mínimas, moderado o localmente notable en las máximas. Heladas débiles en la alta montaña, localmente moderadas. Predominio de viento moderado de componente este, sin descartar rachas fuertes en cotas altas y zonas expuestas, más probables en la Jacetania.

AEMET. Se autoriza la reproducción de su contenido citando la fuente.

Datos en la atmósfera libre:

Altitud de la isoterma de 0 ºC: 2400 m
Altitud de la isoterma de -10 ºC: 3900 m

Viento a 1500 m: VRB 10 km/h
Viento a 3000 m: SE 50 km/h

Evolución para el sábado día 7

Nivel de peligro con pocos cambios.

(Información elaborada a partir de los datos recibidos de los refugios de Linza, Lizara, Panticosa, Góriz, Pineta, Estós, Angel Orús, La Renclusa, Cap de Llauset y Belagua, de las estaciones de esquí de Candanchú, Formigal y Panticosa (lagos), de la estación de esquí de fondo de Llanos del Hospital y de Ordesa Pradera)

Escala europea de peligro de aludes

Débil | Limitado | Notable | Fuerte | Muy Fuerte

Problemas de aludes

Nieve reciente | Placas de viento | Capas débiles persistentes | Nieve húmeda | Deslizamientos basales | Sin problema evidente

Nota1: Se recuerda que, siempre que haya nieve, la ausencia total de peligro no existe. Hay que tener presente que en circunstancias desfavorables, con aludes de tamaño 1 (alud pequeño o colada) y tamaño 2 (alud mediano), se pueden sufrir severos daños personales.

Nota2: Los BPA se elaboran en base a información meteorológica así como al estado del manto nivoso a través de sondeos puntuales. Se advierte a los usuarios de la variabilidad de esta información al extrapolarla a zonas extensas de montaña. Por ello, AEMET no se hace responsable de su uso para la toma de decisiones que conciernen a la seguridad personal, ni de los riesgos físicos o materiales de ellas derivadas.

AEMET. Se autoriza la reproducción de su contenido citando la fuente.