Freitag 06.03.2026

Veröffentlicht am 05.03.2026 um 17:00

Vormittag

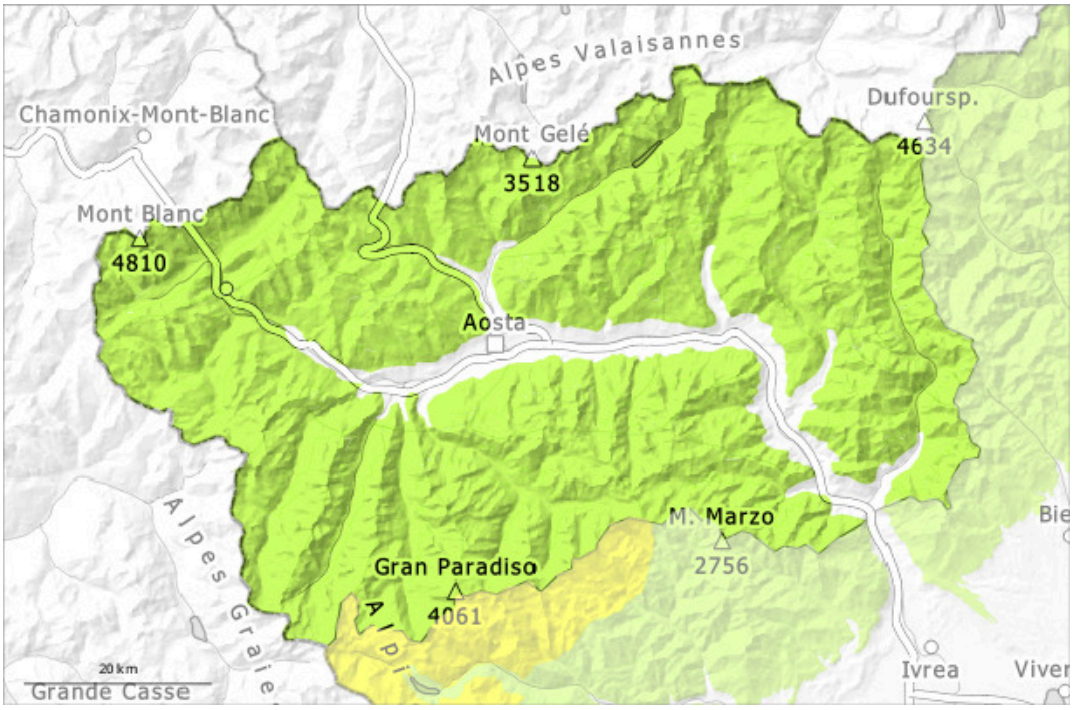

Nachmittag

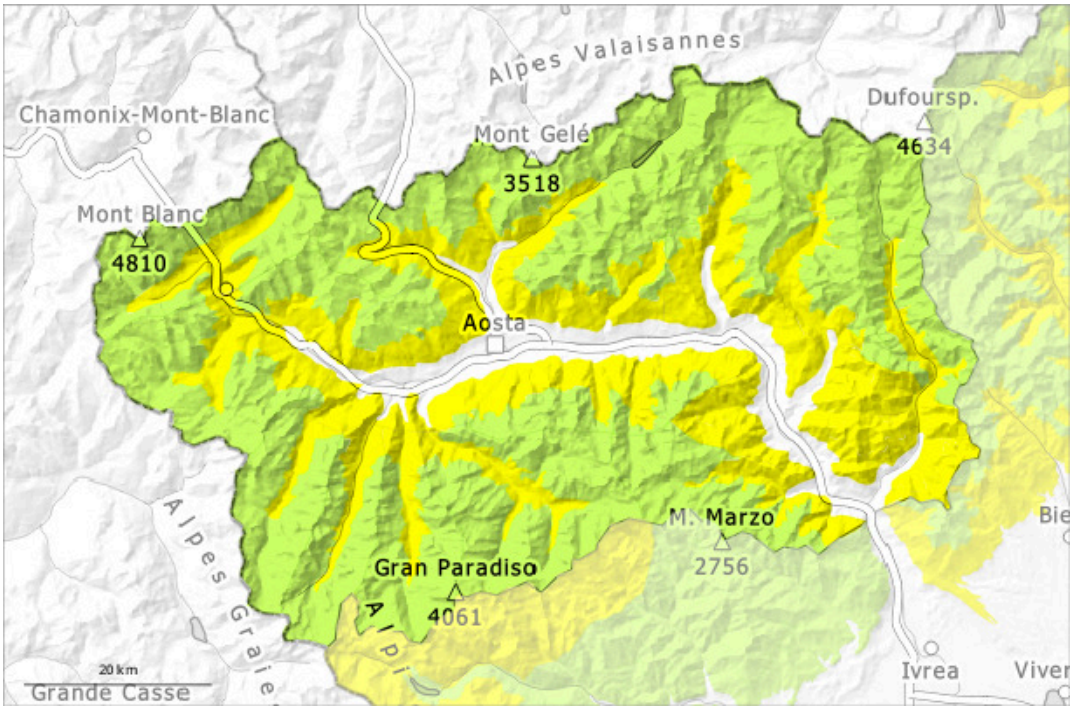

1	2	3	4	5
gering	mäßig	erheblich	groß	sehr groß

Freitag 06.03.2026

Veröffentlicht am 05.03.2026 um 17:00

Gefahrenstufe 2 - Mäßig

AM:

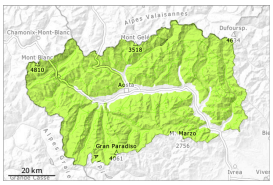

Tendenz: Lawinengefahr bleibt gleich
am Samstag, den 07.03.2026

Altschnee

2400m

PM:

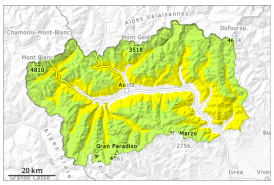

2600m

Tendenz: Lawinengefahr bleibt gleich
am Samstag, den 07.03.2026

Nassschnee

2600m
2000m

Altschnee

2400m

Die Tourenverhältnisse sind mehrheitlich günstig.

Die Schneeoberfläche gefriert nur in hohen Lagen tragfähig, v.a. bei bedeckter Nacht.
Leichter Anstieg der Gefahr mit der tageszeitlichen Erwärmung. Vor allem in mittleren Lagen sind im Tagesverlauf einzelne meist kleine feuchte und nasse Lawinen möglich, v.a. aus extrem steilen noch nicht vollständig entladenen Einzugsgebieten.
Tiefer in der Schneedecke sind Schwachschichten vorhanden. Lawinen können sehr vereinzelt in tiefen Schichten ausgelöst werden und vereinzelt mittlere Größe erreichen. Diese Gefahrenstellen liegen vor allem an eher schneearmen Stellen sowie im selten befahrenen Tourengelände.

Schneedecke

Gefahrenmuster gm.1: bodennahe schwachschicht | gm.10: frühjahrssituation

Die Wetterbedingungen begünstigten v.a. an Sonnenhängen eine Verfestigung der Schneedecke. Der obere Teil der Schneedecke ist weitgehend stabil, mit einer oft tragfähigen Schmelzharschkruste an der Oberfläche. Dort besteht im Steilgelände Absturzgefahr.
Besonders steile Schattenhänge hohe Lagen und Hochgebirge: In der Altschneedecke sind Schwachschichten vorhanden. Der obere Teil der Schneedecke ist aufbauend umgewandelt, mit einer Oberfläche aus kantig aufgebauten Kristallen.
In Kamm- und Passlagen sowie in hohen Lagen liegen je nach Windeinfluss sehr unterschiedliche Schneehöhen.

Tendenz

Die Verhältnisse für Touren und zum Freeriden sind recht günstig. Auf der harten Schneeoberfläche besteht im Steilgelände Absturzgefahr. Mit der tageszeitlichen Erwärmung nimmt die Gefahr von feuchten und nassen Lawinen am Vormittag kaum ab.