ICGC Institut Cartogràfic i Geològic de Catalunya

Servei Meteorològic de Catalunya meteo.cat

Boletín de peligro de aludes para el Pirineo de Catalunya
Del 05/03/2026 al 06/03/2026

(Válido fuera pistas de esquí y zonas no controladas)

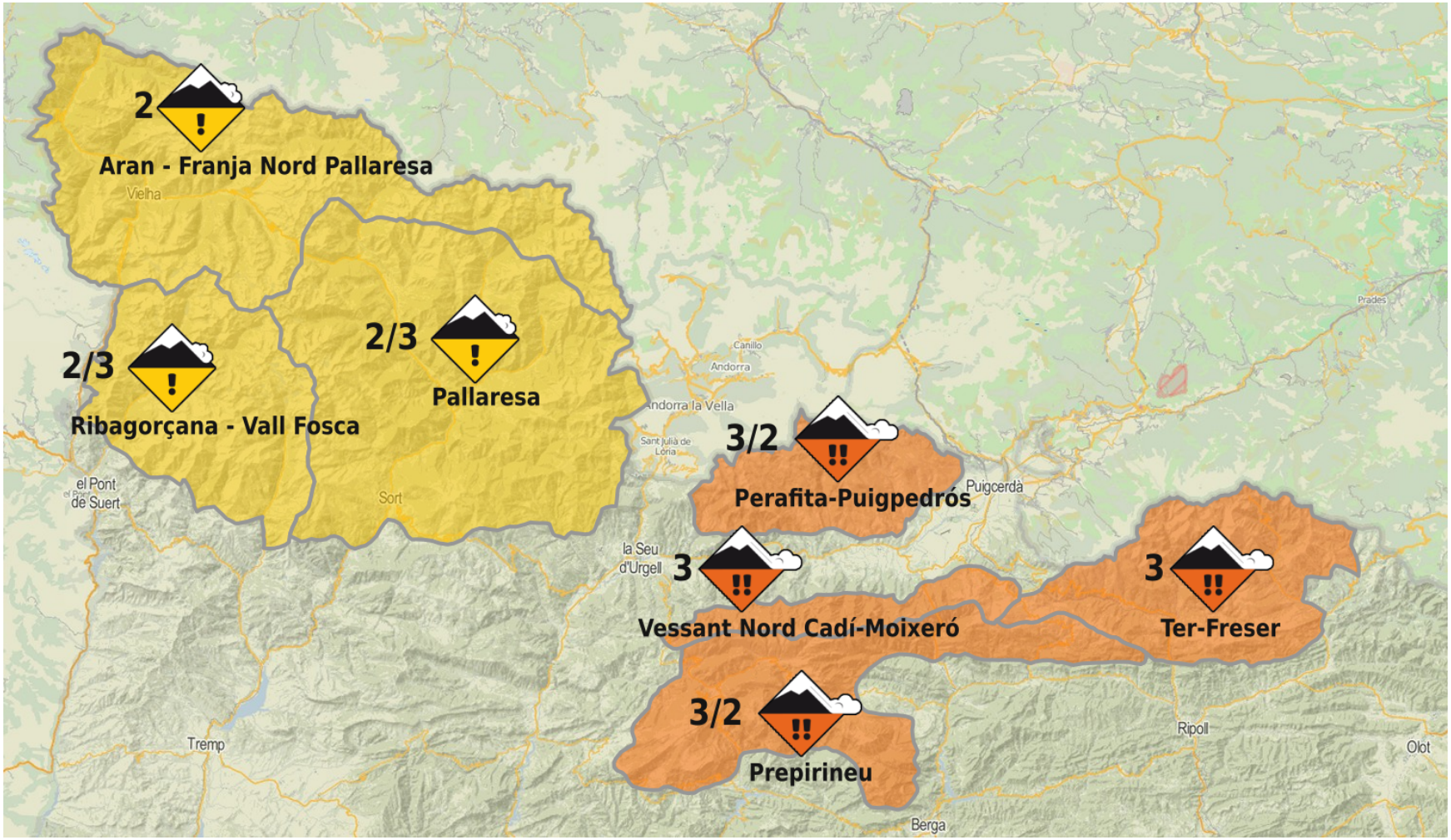

5 MUY FUERTE	4 FUERTE	3 NOTABLE	2 LIMITADO	1 DÉBIL

ICGC Institut Cartogràfic i Geològic de Catalunya

Servei Meteorològic de Catalunya

Boletín de peligro de aludes Aran - Franja Nord Pallaresa Del 05/03/2026 al 06/03/2026

(Válido fuera pistas de esquí y zonas no controladas)

LIMITADO (2).

Situación primaria

Deslizamientos basales **Distribución** **Tamaño** **Origen** **Tendencia**

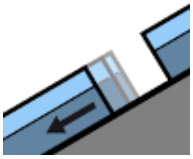

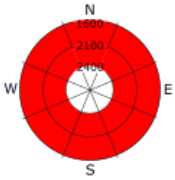

Situación secundaria

Nieve venteada **Distribución** **Tamaño** **Origen** **Tendencia**

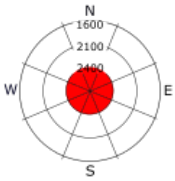

Estado del manto nivoso

Por la tarde del jueves empezará a llover por debajo de 2.400 m (unos 5-10 mm), bajando el límite de la lluvia a unos 2.000 m por la mañana del viernes. Los deslizamientos basales se volverán a reactivar y pobablemente se concentre la actividad en cotas medias de las umbrías, donde días pasados todavía no había habido actividad. Serán de tamaño 2, mediano, suficiente para enterrar a una persona, puntualmente mayor. Se desprenden en terreno herboso y liso; evitad situaros bajo fisuras en el manto. Progresivamente, el viernes la cota de nieve irá bajando y en cotas altas se irán formando placas de viento en todas las orientaciones, pero sobre todo en las vertientes norte y oeste; podrán caer aludes de placa al paso de personas y en general serán de tamaño 1, pequeño, con capacidad de derribarnos y arrastrarnos.

Distribución del manto nivoso

Hay nieve por encima de unos 1.400-1-500 m en umbrías y 1.700 m en solanas. Los espesores a unos 2.200 m son superiores a los normales en la Franja Norte de la Pallaresa y en la mitad sur del Aran donde rondan los 160-200 cm. En la mitad norte del Arán hay unos 120-140 cm de grosor total.

Tendencia para las próximas 48-72h

Volveremos hacia un manto más seco en cotas altas con mayor frecuencia y mayor tamaño de placas de viento. Peligro ESTACIONARIO O EN LIGERO AUMENTO en cotas altas.

El próximo boletín será emitido el día 2026-03-06

5 MUY FUERTE	4 FUERTE	3 NOTABLE	2 LIMITADO	1 DÉBIL

EAWS EUROPEAN AVALANCHE WARNING SERVICES

ICGC Institut Cartogràfic i Geològic de Catalunya

Servei Meteorològic de Catalunya meteo.cat

Boletín de peligro de aludes Ribagorçana - Vall Fosca Del 05/03/2026 al 06/03/2026

(Válido fuera pistas de esquí y zonas no controladas)

LIMITADO (2) NOTABLE (3) durante la tarde del viernes.

Situación primaria

Nieve venteada

Distribución

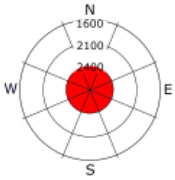

Tamaño

Origen

Tendencia

Situación secundaria

Nieve húmeda

Distribución

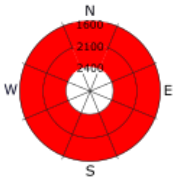

Tamaño

Origen

Tendencia

Estado del manto nivoso

Está previsto que el jueves por la tarde empiece a nevar por encima de 2.300-2.400 m bajando algo de cota. El viernes seguiría nevando a unos 2.000 m y por la mañana podríamos encontrar un grosor de nieve reciente de 10-15 cm por encima de 2.300-2.400 m, grosor en aumento durante la jornada. Por encima de 2.200 m podrán caer aludes de nieve reciente de forma natural en laderas de fuerte pendiente y a cualquier orientación; serán de tamaño 1, pequeño, suficiente para derribarnos y arrastrarnos. En las cotas más altas, bajo collados y cordales se formarán placas de viento sobretodo en orientaciones norte y oeste, que caerán al paso de una persona; localmente de tamaño 2, mediano, suficiente para enterrar a una persona. Por debajo de 2.200 m caerán aludes de nieve húmeda debido a la lluvia, a cualquier orientación, por lo general de tamaño 1, pequeña. Durante el viernes, la probabilidad de aludes irá aumentando durante la jornada.

Distribución del manto nivoso

Hay nieve en el suelo a 1.600 m en terreno umbrío, y por encima de unos 1.800 m en laderas soleadas. El manto es esquiable por encima de unos 1.700 m en umbrías. Los espesores alcanzan los 100-130 cm en cotas medias. Estos valores son aún superiores a los normales para la época.

Tendencia para las próximas 48-72h

Volveremos hacia un manto más seco en cotas altas con mayor frecuencia y mayor tamaño de placas de viento. Peligro ESTACIONARIO O EN LIGERO AUMENTO en cotas altas.

El próximo boletín será emitido el día 2026-03-06

5 MUY FUERTE	4 FUERTE	3 NOTABLE	2 LIMITADO	1 DÉBIL

EAWS EUROPEAN AVALANCHE WARNING SERVICES

ICGC Institut Cartogràfic i Geològic de Catalunya

Servei Meteorològic de Catalunya

Boletín de peligro de aludes Pallaresa
Del 05/03/2026 al 06/03/2026

(Válido fuera pistas de esquí y zonas no controladas)

LIMITADO (2)
NOTABLE (3) durante la tarde del viernes.

Situación primaria

Nieve venteada

Distribución

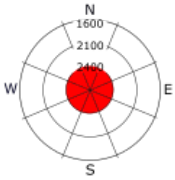

Tamaño

Origen

Tendencia

Situación secundaria

Nieve húmeda

Distribución

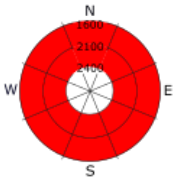

Tamaño

Origen

Tendencia

Estado del manto nivoso

Está previsto que el jueves por la tarde empiece a nevar por encima de 2.300-2.400 m bajando algo de cota. El viernes seguiría nevando a unos 2.000 m y por la mañana podríamos encontrar un grosor de nieve reciente de 10-15 cm por encima de 2.300-2.400 m, grosor en aumento durante la jornada. Por encima de 2.200 m podrán caer aludes de nieve reciente de forma natural en laderas de fuerte pendiente y a cualquier orientación; serán de tamaño 1, pequeño, suficiente para derribarnos y arrastrarnos. En las cotas más altas, bajo collados y cordales se formarán placas de viento en sobretodo orientaciones norte y oeste, que caerán al paso de una persona; localmente de tamaño 2, mediano, suficiente para enterrar a una persona. Por debajo de 2.200 m caerán aludes de nieve húmeda debido a la lluvia, a cualquier orientación, por lo general de tamaño 1, pequeña. Durante el viernes, la probabilidad de aludes irá aumentando durante la jornada.

Distribución del manto nivoso

Hay nieve en el suelo a 1.600 m en terreno umbrío, esquiable por encima de unos 1.700 m; en orientaciones soleadas la nieve está presente por encima de unos 1.800 m. Los espesores alcanzan los 110-150 cm en cotas medias.

Tendencia para las próximas 48-72h

Volveremos hacia un manto más seco en cotas altas con mayor frecuencia y mayor tamaño de placas de viento. Peligro ESTACIONARIO O EN LIGERO AUMENTO en cotas altas.

El próximo boletín será emitido el día 2026-03-06

5 MUY FUERTE	4 FUERTE	3 NOTABLE	2 LIMITADO	1 DÉBIL

EAWS EUROPEAN AVALANCHE WARNING SERVICES

ICGC Institut Cartogràfic i Geològic de Catalunya

Servei Meteorològic de Catalunya

Boletín de peligro de aludes Perafita-Puigpedrós Del 05/03/2026 al 06/03/2026

(Válido fuera pistas de esquí y zonas no controladas)

NOTABLE (3) viernes.
LIMITADO (2) jueves.

Situación primaria

Nieve venteada

Distribución

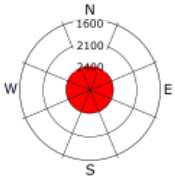

Tamaño

Origen

Tendencia

Situación secundaria

Nieve húmeda

Distribución

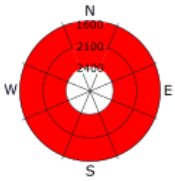

Tamaño

Origen

Tendencia

Estado del manto nivoso

Por la mañana del jueves ya ha empezado a nevar por encima de 2.100 m. El viernes continuará nevando y por la mañana habrá un grosor de nieve reciente de unos 10-15 cm por encima de 2.200 m, grosor en aumento durante la jornada. Por encima de 2.100 m podrán caer aludes de nieve reciente de forma natural en laderas de fuerte pendiente y a cualquier orientación; a partir de mediodía del viernes serán de tamaño 2, mediano, con capacidad de enterrar a una persona. Bajo collados y cordales se formarán algunas placas de viento sobretodo en orientaciones norte y oeste, que caerán al paso de una persona; por lo general de tamaño 2, mediano. Por debajo de 2.100 m caerán aludes de nieve húmeda debido a la lluvia, a cualquier orientación, en general de tamaño 1, pequeño, suficiente para derribarnos y arrastrarnos. La probabilidad de caída de aludes aumentará a lo largo de la jornada.

Distribución del manto nivoso

Hay nieve en el suelo por encima de unos 1.600-1.700 m. El manto es esquiable por encima de unos 1.800 m. Los espesores, aunque irregulares, rondan los 70-90 cm en cotas medias, con frecuentes deflaciones en orientaciones norte y oeste por encima del nivel del bosque. Son grosores por encima de los habituales para la época.

Tendencia para las próximas 48-72h

Volveremos hacia un manto más seco en cotas altas con mayor frecuencia y mayor tamaño de placas de viento. Peligro ESTACIONARIO O EN LIGERO AUMENTO en cotas altas.

El próximo boletín será emitido el día 2026-03-06

5 MUY FUERTE	4 FUERTE	3 NOTABLE	2 LIMITADO	1 DÉBIL

EAWS EUROPEAN AVALANCHE WARNING SERVICES

ICGC Institut Cartogràfic i Geològic de Catalunya

Servei Meteorològic de Catalunya

Boletín de peligro de aludes
Vessant Nord Cadí-Moixeró
Del 05/03/2026 al 06/03/2026

(Válido fuera pistas de esquí y zonas no controladas)

NOTABLE (3)

Situación primaria

Nieve reciente

Distribución

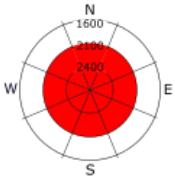

Tamaño

Origen

Tendencia

Situación secundaria

Nieve húmeda

Distribución

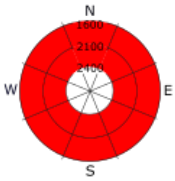

Tamaño

Origen

Tendencia

Estado del manto nivoso

Por la mañana del jueves ya ha empezado a nevar por encima de 2.100 m. El viernes continuará nevando y por la mañana habrá un grosor de nieve reciente de 15-20 cm por encima de 2.200 m, grosor en aumento durante la jornada. Se espera alta actividad de aludes. Por un lado, por encima de 2.100 m, podrán caer aludes de nieve reciente de forma natural en laderas de fuerte pendiente y a cualquier orientación; serán de tamaño 2, mediano, con capacidad de enterrar a una persona. En las cotas más altas, bajo collados y cordales se formarán placas de viento en orientaciones norte y oeste, que caerán al paso de una persona; por lo general de tamaño 2, mediano. Por debajo de 2.100 m caerán aludes de nieve húmeda debido a la lluvia, a cualquier orientación, en general de tamaño 1, pequeño, suficiente para derribarnos y arrastrarnos.

Distribución del manto nivoso

En umbrías hay nieve por encima de 1.600 m, esquiable por encima de unos 1.700 m. En solanas la nieve está presente por encima de 1.800 m. Los grosores están alrededor de 140-160 cm a 2.200 m. Estos valores siguen siendo muy excedentarios para la época del año.

Tendencia para las próximas 48-72h

Volveremos hacia un manto más seco en cotas altas con mayor frecuencia y mayor tamaño de placas de viento. Peligro ESTACIONARIO O EN LIGERO AUMENTO en cotas altas.

El próximo boletín será emitido el día 2026-03-06

5 MUY FUERTE	4 FUERTE	3 NOTABLE	2 LIMITADO	1 DÉBIL

EAWS EUROPEAN AVALANCHE WARNING SERVICES

ICGC Institut Cartogràfic i Geològic de Catalunya

Servei Meteorològic de Catalunya

Boletín de peligro de aludes Prepirineu
Del 05/03/2026 al 06/03/2026

(Válido fuera pistas de esquí y zonas no controladas)

NOTABLE (3) viernes.
LIMITADO (2) jueves.

Situación primaria

Nieve reciente

Distribución

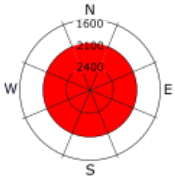

Tamaño

Origen

Tendencia

Situación secundaria

Nieve húmeda

Distribución

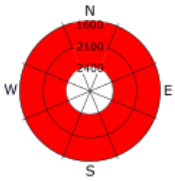

Tamaño

Origen

Tendencia

Estado del manto nivoso

Por la mañana del jueves ya ha empezado a nevar por encima de 2.100 m. El viernes continuará nevando y por la mañana habrá un grosor de nieve reciente de unos 10-15 cm por encima de 2.200 m, grosor en aumento durante la jornada. Por encima de 2.100 m podrán caer aludes de nieve reciente de forma natural en laderas de fuerte pendiente y a cualquier orientación; a partir de mediodía del viernes serán de tamaño 2, mediano, con capacidad de enterrar a una persona. En las cotas más altas, bajo collados y cordales se formarán algunas placas de viento sobretodo en orientaciones norte y oeste, que caerán al paso de una persona; por lo general de tamaño 2, mediano. Por debajo de 2.100 m caerán aludes de nieve húmeda debido a la lluvia, a cualquier orientación, en general de tamaño 1, pequeño, suficiente para derribarnos y arrastrarnos. La probabilidad de caída de aludes aumentará a lo largo de la jornada.

Distribución del manto nivoso

En umbrías hay nieve por encima de 1.600 m, esquiable por encima de unos 1.700 m. En solanas la nieve está presente por encima de 1.800 m. Los espesores, aunque irregulares, rondan los 70-90 cm en cotas medias.

Tendencia para las próximas 48-72h

Volveremos hacia un manto más seco en cotas altas con mayor frecuencia y mayor tamaño de placas de viento. Peligro ESTACIONARIO O EN LIGERO AUMENTO en cotas altas.

El próximo boletín será emitido el día 2026-03-06

5 MUY FUERTE	4 FUERTE	3 NOTABLE	2 LIMITADO	1 DÉBIL

EAWS EUROPEAN AVALANCHE WARNING SERVICES

ICGC Institut Cartogràfic i Geològic de Catalunya

meteo.cat Servei Meteorològic de Catalunya

Boletín de peligro de aludes Ter-Freser Del 05/03/2026 al 06/03/2026

(Válido fuera pistas de esquí y zonas no controladas)

NOTABLE (3)

Situación primaria

Nieve venteada

Distribución

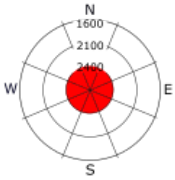

Tamaño

Origen

Tendencia

Situación secundaria

Nieve húmeda

Distribución

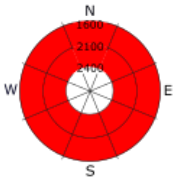

Tamaño

Origen

Tendencia

Estado del manto nivoso

A mediodía del jueves ya ha empezado a nevar por encima de 2.300 m. El viernes continuará nevando y por la mañana puede haber un grosor de nieve reciente de 15-25 cm por encima de 2.200 m, grosor en aumento durante la jornada. A medida que avance el viernes, aumentará la actividad de aludes. Por encima de 2.100 m podrán caer aludes de nieve reciente de forma natural en laderas de fuerte pendiente y a cualquier orientación; serán de tamaño 2, mediano, con capacidad de enterrar a una persona. En cotas altas, bajo collados y cordales se formarán placas de viento, sobre todo en orientaciones norte y oeste, que caerán al paso de una persona; por lo general de tamaño 2, mediano. Por debajo de 2.100 m caerán aludes de nieve húmeda debido a la lluvia, a cualquier orientación, por lo general de tamaño 2, mediano.

Distribución del manto nivoso

El manto nivoso presenta grosores muy excedentarios para la época del año. En lugares no afectados por el viento los grosores oscilan entre 70-90 cm a unos 2.000 m y 160-190 cm por encima de 2.400 m. Es esquiable a partir de unos 1.600 m. Aparecen deflaciones por encima del nivel del bosque, sobre todo en lugares bien expuestos al viento de norte y oeste.

Tendencia para las próximas 48-72h

Volveremos hacia un manto más seco en cotas altas con mayor frecuencia y mayor tamaño de placas de viento. Peligro ESTACIONARIO O EN LIGERO AUMENTO en cotas altas.

El próximo boletín será emitido el día 2026-03-06

5 MUY FUERTE	4 FUERTE	3 NOTABLE	2 LIMITADO	1 DÉBIL

EAWS EUROPEAN AVALANCHE WARNING SERVICES