BUTLLETÍ DEL PERILL D'ALLAUS DEL PRINCIPAT D'ANDORRA

Elaborado el 05/03/2026 16:00
Proxima actualización 06/03/2026 a las 16h

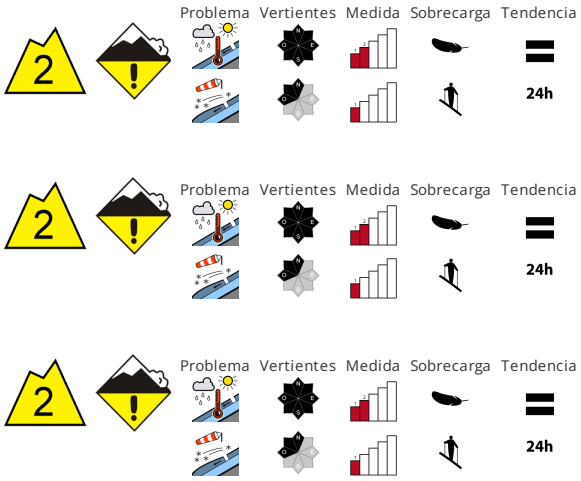

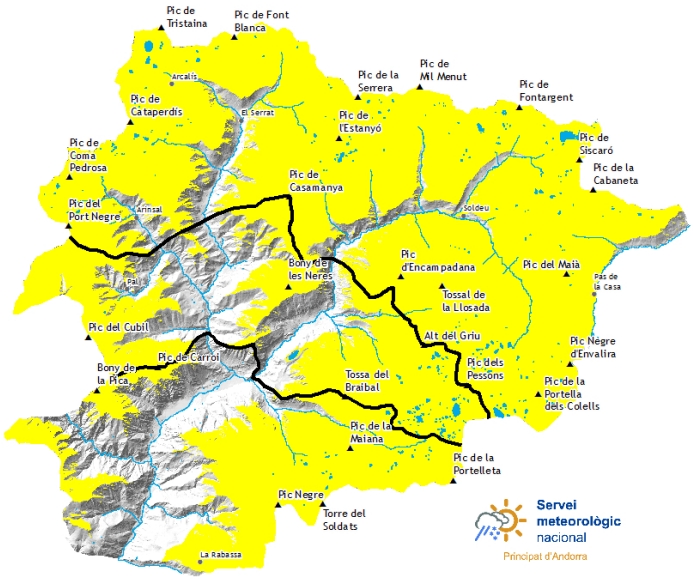

CALIDAD DE LA NIEVE

Con la intensificación de la precipitación, por debajo de los 2400 m aproximadamente son probables avalanchas de nieve húmeda. Estos pueden desencadenarse de manera natural y alcanzar un tamaño mediano. Además son de esperar aludes de deslizamiento basal en cualquier momento. En cotas altas :. El viento del sudeste transportará la nieve reciente. A partir del mediodía se formarán placas de viento en su mayoría de tamaño pequeño en las laderas cercanas a los cordales orientadas a oeste, noroeste y norte. Estos lugares están parcialmente cubiertos de nieve reciente y resultan difíciles de reconocer. Los lugares peligrosos son resultan difíciles de reconocer con poca visibilidad.

ESTABILIDAD DEL MANTO NIVOSO

En particular en el sudeste a partir del mediodía caerán en algunos sectores 15 cm de nieve por encima de los 2400 m aproximadamente, localmente hasta 15 cm. Caerá lluvia hasta en cotas altas especialmente en los sudeste. El enfriamiento nocturno será muy limitado. Los espesores de nieve varían mucho por encima de los 2100 m aproximadamente por la influencia del viento. Evitar las zonas con grietas de deslizamiento basal.

ESPESORES DEL MANTO NIVOSO FUERA DE PISTA

Zona norte		Espesor nieve		
Manto Nival		1500m	2000m	2500m
N	1600 m	30 cm	150 cm	200 cm
S	1900 m	0 cm	100 cm	150 cm

zona centro		Espesor nieve		
Manto Nival		1500m	2000m	2500m
N	1600 m	20 cm	150 cm	200 cm
S	1900 m	0 cm	100 cm	150 cm

Zona sur		Espesor nieve		
Manto Nival		1500m	2000m	2500m
N	1600 m	20 cm	120 cm	150 cm
S	1900 m	0 cm	60 cm	100 cm

Govern d'Andorra

EAWS EUROPEAN AVALANCHE WARNING SERVICES

Aquest butlletí ha estat elaborat seguint les normes i recomanacions de l'**European Avalanche Warning Services**, del qual el **Servei meteorològic Nacional** n'és membre

BUTLLETÍ DEL PERILL D'ALLAUS DEL PRINCIPAT D'ANDORRA

Servei meteorològic nacional
Principat d'Andorra

Información detallada por espacios naturales protegidos

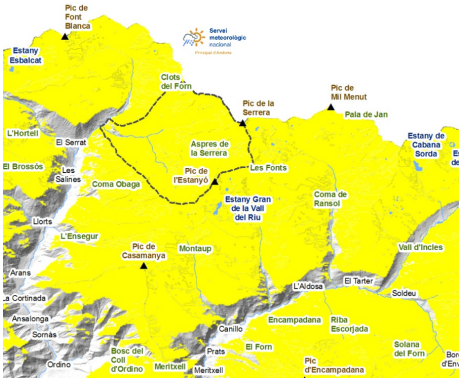

SORTENY

A partir del mediodía del jueves se esperan precipitaciones con barro y una cota de nieve en torno a los 2200 m, humidificará el manto en todas las orientaciones, por debajo de esta cota; mientras que por encima se podrán formar débiles acumulaciones de unos 5 cm en este sector. En altura, el viento podrá transportar la poca nieve disponible y formar pequeñas acumulaciones irregulares.

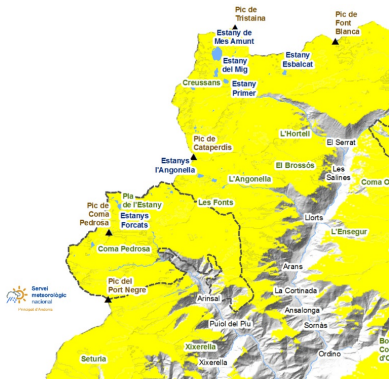

COMAPEDROSA

El acceso desde Arinsal está quedando cada vez con menos nieve, y la lluvia prevista aún retirará más la línea de nieve continua. Mientras duren las precipitaciones la mala visibilidad hace desaconsejar las excursiones al Parque, pero una vez hayan finalizado, las condiciones permanecerán generalmente estables y se podrán realizar numerosas excursiones, siempre manteniendo una elección cuidadosa del itinerario.

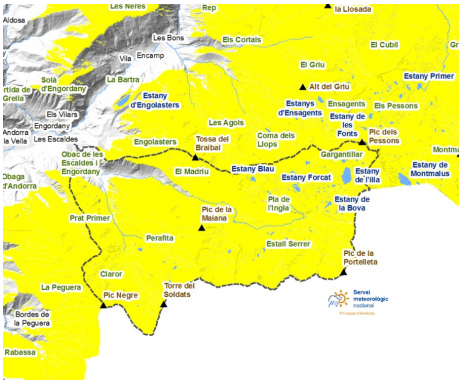

MADRIU-PERAFITA-CLAROR

El manto es en general delgado e irregular, con mejor continuidad de nieve en las vertientes norte y umbrías, donde en altura todavía se encuentra nieve seca reciclada. Será el sector más afectado por las precipitaciones y, por tanto, donde preveamos la mayor actividad.

Govern d'Andorra

EAWS
EUROPEAN AVALANCHE WARNING SERVICES

Aquest butlletí ha estat elaborat seguint les normes i recomanacions de l'**European Avalanche Warning Services**, del qual el **Servei meteorològic Nacional** n'és membre

BUTLLETÍ DEL PERILL D'ALLAUS DEL PRINCIPAT D'ANDORRA

Servei meteorològic nacional
Principat d'Andorra

Espesores de nieve nueva de los últimos días (de las ultimas 24h mesurado a las 06:00h UTC)

	01/03/2026	02/03/2026	03/03/2026	04/03/2026
FEDA (Central)	0 cm	0 cm	0 cm	0 cm
Engolasters - FEDA	0 cm	0 cm	0 cm	0 cm
Bony de les Neres	0 cm	0 cm	0 cm	0 cm
Sorteny	0 cm	0 cm	0 cm	3 cm
Perafita	0 cm	0 cm	4 cm	3 cm
Tossa Espiolets	0 cm	0 cm	2 cm	0 cm
Grau Roig - FEDA	0 cm	0 cm	0 cm	0 cm
Fontverd	0 cm	0 cm	0 cm	0 cm
Ransol - FEDA	0 cm	0 cm	0 cm	0 cm
Setúria	0 cm	0 cm	0 cm	0 cm
Caborreu	0 cm	0 cm	0 cm	0 cm
La Solana	0 cm	0 cm	0 cm	0 cm
Envalira Antenes	0 cm	0 cm	4 cm	0 cm
Vall del Riu FEDA	0 cm	0 cm	3 cm	0 cm