BUTLLETÍ DEL PERILL D'ALLAUS DEL PRINCIPAT D'ANDORRA

Servei meteorològic nacional
Principat d'Andorra

Préparé le 05/03/2026 16:00
Prochaine mise à jour le 06/03/2026 à 16h

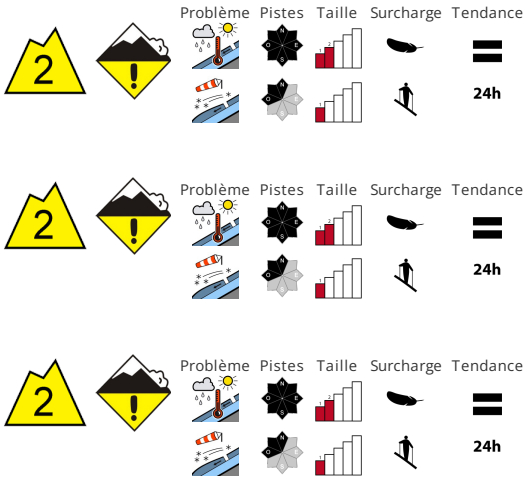

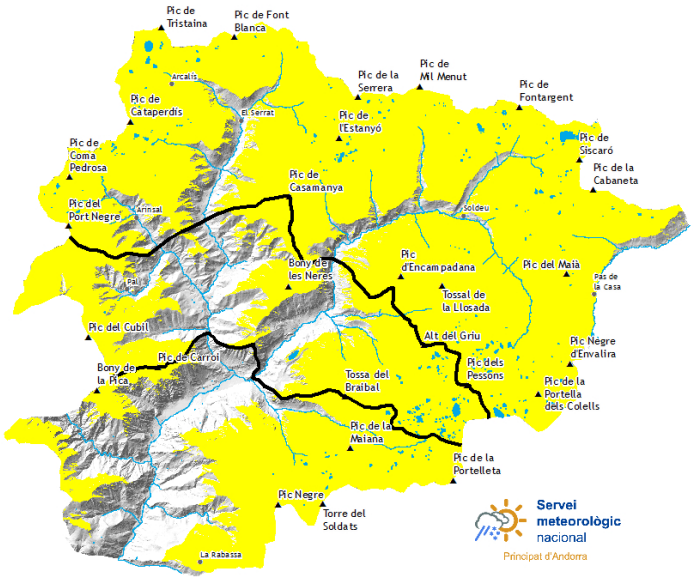

STABILITÉ DU MANTEAU NEIGEUX

Avec l'intensification des précipitations des avalanches humides sont à attendre en dessous d'environ 2400 m. Explication: celles-ci ne peut signifier que celles-ci avalanches peuvent se déclencher spontanément et atteindre une taille moyenne.. En outre, des avalanches de glissement sont à attendre à tout moment.. À haute altitude (-):. Le vent du sud-est transporte la neige fraîche.. Des accumulations de neige soufflée en général petites se forment à partir de midi sur les pentes exposées à l'ouest , au nord-ouest et au nord proches des crêtes. Ces endroits sont en partie couverts de neige fraîche, et difficilement identifiables.. Les endroits dangereux sont à peine identifiables par mauvaise visibilité..

QUALITÈ DE LA NEIGE

À partir de midi il tombera surtout au sud-est au-dessus d'environ 2400 m par régions 15 cm de neige , localement jusqu'à 15 cm.. Il tombe de la pluie jusqu'à haute altitude spécialement au sud-est. Le rayonnement nocturne est fortement réduit.. On trouve suivant l'influence du vent des hauteurs de neiges très différentes au-dessus d'environ 2100 m. Les zones présentant des fissures de glissement doivent être évitées..

EPAISSEUR DE NEIGE HORS PISTE

Zone nord		Epaisseur de neige		
Nival manteau		1500m	2000m	2500m
N	1600 m	30 cm	150 cm	200 cm
S	1900 m	0 cm	100 cm	150 cm

Zone centre		Epaisseur de neige		
Nival manteau		1500m	2000m	2500m
N	1600 m	20 cm	150 cm	200 cm
S	1900 m	0 cm	100 cm	150 cm

Zone sud		Epaisseur de neige		
Nival manteau		1500m	2000m	2500m
N	1600 m	20 cm	120 cm	150 cm
S	1900 m	0 cm	60 cm	100 cm

Govern d'Andorra

EAWS
EUROPEAN AVALANCHE WARNING SERVICES

Aquest butlletí ha estat elaborat seguint les normes i recomanacions de l'**European Avalanche Warning Services**, del qual el **Servei meteorològic Nacional** n'és membre

BUTLLETÍ DEL PERILL D'ALLAUS DEL PRINCIPAT D'ANDORRA

Servei meteorològic nacional
Principat d'Andorra

Des informations détaillées par espace naturel protégé

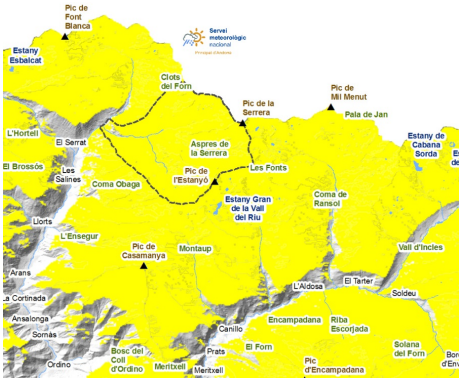

SORTENY

A partir de jeudi midi, des précipitations avec de la boue et un niveau de neige autour de 2200 m sont attendus, cela humidifiera le manteau dans toutes les directions, en dessous de ce niveau ; tandis que de faibles accumulations d'environ 5 cm pourraient se former en amont dans ce secteur. En altitude, le vent pourra transporter le peu de neige disponible et former de petites accumulations irrégulières. , , , , ,

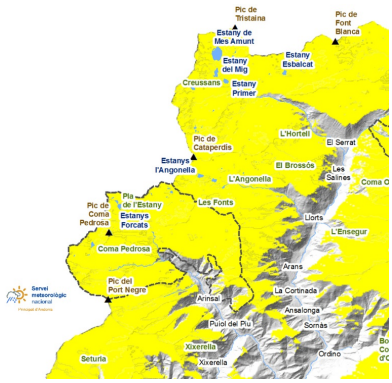

COMAPEDROSA

L'accès depuis Arinsal reçoit de moins en moins de neige, et la pluie prévue retardera encore davantage la ligne de neige continue. Tant que les précipitations durent, la mauvaise visibilité rend les excursions dans le Parc déconseillées, mais une fois celles-ci terminées, les conditions resteront généralement stables et de nombreuses excursions pourront être réalisées, en gardant toujours un choix judicieux de l'itinéraire. , , ,

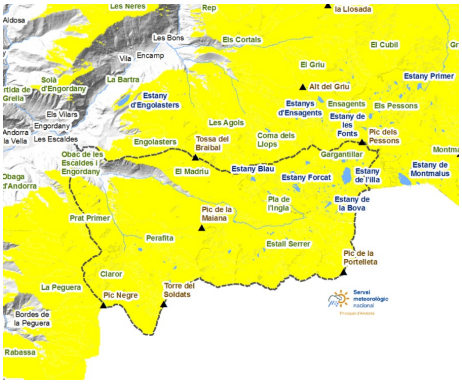

MADRIU-PERAFITA-CLAROR

Le manteau est généralement mince et irrégulier, avec une meilleure continuité neigeuse sur les versants nord et obac, où l'on trouve encore de la neige sèche recyclée en haute altitude. Ce sera le secteur le plus touché par les précipitations et, par conséquent, celui où l'on prévoit la plus grande activité. , , ,

Govern d'Andorra

EAWS
EUROPEAN AVALANCHE WARNING SERVICES

Aquest butlletí ha estat elaborat seguint les normes i recomanacions de l'**European Avalanche Warning Services**, del qual el **Servei meteorològic Nacional** n'és membre

BUTLLETÍ DEL PERILL D'ALLAUS DEL PRINCIPAT D'ANDORRA

Servei meteorològic nacional
Principat d'Andorra

Couche de neige fraiche des derniers jours (De 24 h mesurée à 06:00 h UTC)

	01/03/2026	02/03/2026	03/03/2026	04/03/2026
FEDA (Central)	0 cm	0 cm	0 cm	0 cm
Engolasters - FEDA	0 cm	0 cm	0 cm	0 cm
Bony de les Neres	0 cm	0 cm	0 cm	0 cm
Sorteny	0 cm	0 cm	0 cm	3 cm
Perafita	0 cm	0 cm	4 cm	3 cm
Tossa Espiolets	0 cm	0 cm	2 cm	0 cm
Grau Roig - FEDA	0 cm	0 cm	0 cm	0 cm
Fontverd	0 cm	0 cm	0 cm	0 cm
Ransol - FEDA	0 cm	0 cm	0 cm	0 cm
Setúria	0 cm	0 cm	0 cm	0 cm
Caborreu	0 cm	0 cm	0 cm	0 cm
La Solana	0 cm	0 cm	0 cm	0 cm
Envalira Antenes	0 cm	0 cm	4 cm	0 cm
Vall del Riu FEDA	0 cm	0 cm	3 cm	0 cm