MINISTERO DELLA DIFESA

meteomont Servizio Nazionale di previsione neve e valanghe

EAWS EUROPEAN AVALANCHE WARNING SERVICES

CARABINIERI

ALPI RETICHE

Bollettino Valanghe N. 366/2026 del 05/03/2026 ore 14.00
Validità 48 ore prossima emissione 06/03/2026

A cura del Servizio METEOMONT dell'ARMA dei CARABINIERI
In collaborazione con Servizio Meteorologico dell'Aeronautica militare

SITUAZIONE alle 14:00 del 05/03/2026

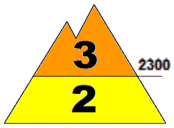

SITUAZIONE TIPO: passaggio da poca a molta neve.



SITUAZIONE TIPO: situazione primaverile.

Quota neve (mslm)	Nord	Sud
	1100 - 1400	1900 - 2500

Altezza Neve (cm)	Neve al suolo	Neve Fresca	Quota (mslm)
	62	0	2582
	26	0	1580

VALANGHE OSSERVATE: Alcune valanghe di medie dimensioni, I due tipi di valanghe di neve di superficie.

PREVISIONI 06/03/2026

GRADO DI PERICOLO: MARCATO 3

SITUAZIONE TIPO: passaggio da poca a molta neve.

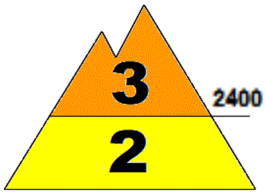



SITUAZIONE TIPO: situazione primaverile.

MANTO NEVOSO: La stabilità del manto nevoso è molto scarsa su alcuni punti (aree) per tutte le esposizioni al di sopra di 2400 mslm, possibili valanghe di dimensioni medie.
La stabilità del manto nevoso è molto scarsa su pochi punti (aree) per isolati pendii al di sotto di 2400 mslm, possibili valanghe di dimensioni medie.

AVVERTENZE

Il rialzo termico diurno richiede un'attenta valutazione temporale dell'escursione che eviti l'attraversamento di pendii ripidi nelle ore più calde della giornata.

SCALA EUROPEA DEL GRADO DI PERICOLO VALANGHE

LEGENDA PROBLEMA

Bollettino realizzato su scala sinottica-regionale (standard EAWS). La sua valutazione non può escludere in alcun modo la necessità di una seria e capace valutazione locale del pericolo (singolo pendio) che può essere anche sensibilmente diverso. Le previsioni meteorologiche sono relative all'orario UTC (per l'Italia +1 in inverno e +2 in estate).

ALPI RETICHE

PREVISIONE METEO

Quota		06/03/2026 h6:00	06/03/2026 h12:00	06/03/2026 h18:00
1000	Venti	01 Nodi da N-Est	00 Calma	01 nodi da N-Ovest
	Temperature	+03 °C	+02 °C	+03 °C
	Temp.percepita	3 °C	2 °C	3 °C
2000	Venti	01 Nodi da N-Est	00 Calma	01 nodi da N-Ovest
	Temperature	+03 °C	+02 °C	+03 °C
	Temp.percepita	3 °C	2 °C	3 °C
3000	Venti	03 Nodi da S-Ovest	02 Nodi da Sud	02 Nodi da S-Est
	Temperature	-02 °C	-02 °C	-01 °C
	Temp.percepita	-4 °C	-2 °C	-1 °C
Zero termico		1900-2100 m.	2000-2200 m.	2500-2700 m.
Fenomeno		—	—	—
Stato del cielo				

LEGENDA FENOMENI

— Assenza Fenomeni · Nebbia · Foschia · Pioggia debole · Pioggia moderata · Pioggia forte · Temporali

Nevicata debole · Nevicata moderata · Nevicata forte

STATO DEL CIELO

Sereno · Poco nuvoloso · Nuvoloso · Molto nuvoloso · Coperto

Parametri meteonivometrici registrati presso i campi di rilevamento il 05/03/2026.

Località	Comune	Quota (m.s.l.m.)	Altezza neve (cm)	Neve caduta nelle 24 ore (cm)	Temp. Min (°C)	Temp. Max (°C)	Condizioni del tempo
SPONDA	Livigno (SO)	2150	60	0	-6	+7	Assenza di precipitazioni
BORMIO2000-LECCIONA	Valdisotto (SO)	2050	60	0	N.P.	N.P.	Assenza di precipitazioni
DOSSO DEL VALLONE	Valfurva (SO)	2582	62	0	-4	+1	Assenza di precipitazioni
SANTA APOLLONIA	Vezza d'Oglio (BS)	1599	13	0	N.P.	N.P.	Assenza di precipitazioni
ALPE PALU'	Chiesa in Valmalenco (SO)	2010	74	0	-1	+6	Assenza di precipitazioni
COLONIA VIGILI	Ponte di Legno (BS)	1640	49	0	-4	+10	Assenza di precipitazioni
SCLANERA *	Valfurva (SO)	2350	78	0	N.P.	N.P.	Assenza di precipitazioni

(*) Rilievi fuori campo

L'INFORMAZIONE E' PREVENZIONE - LEGGI L'ATTUALE GRADO DI PERICOLO VALANGHE!

IL CAPO DEL CENTRO NAZIONALE METEOMONT
(Ten. Col. RFI Emanuela Gini)
FIRMA AUTOGRAFA OMESSA AI SENSI
DELL'ART.3 DEL D.LGS N.39/1993

Bollettino realizzato su scala sinottica-regionale (standard EAWS). La sua valutazione non può escludere in alcun modo la necessità di una seria e capace valutazione locale del pericolo (singolo pendio) che può essere anche sensibilmente diverso. Le previsioni meteorologiche sono relative all'orario UTC (per l'Italia +1 in inverno e +2 in estate).