Bulletin d'estimation du risque d'avalanche

(valable en dehors des pistes balisées et ouvertes)

MASSIF : Ubaye

Rédigé le jeudi 5 mars 2026 à 15h

Estimation des risques pour le : VENDREDI 06 MARS

INSTABILITÉS SUPERFICIELLES EN UBACS DE HAUTE ALTITUDE, SURTOUT VERS L'ITALIE

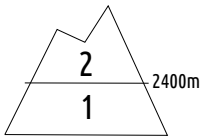

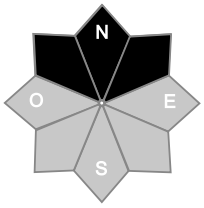

Au-dessus de 2400m indice de risque limité, plus bas indice faible.

Départs spontanés : départs localisés et peu volumineux de plaques à vent à haute altitude ; rares avalanches de glissement en adrets

Déclenchements provoqués : instabilités superficielles à haute altitude, en Haute Ubaye surtout

Indices de risque : 5 très fort - 4 fort - 3 marqué - 2 limité - 1 faible -- En noir : les pentes les plus dangereuses

Stabilité du manteau neigeux

Situation avalancheuse typique : neige ventée couche fragile persistante

Déclenchements provoqués : instabilités limitées à de rares pentes d'altitude supérieure à 2400 m environ, en orientations nord-ouest, nord et nord-est, et surtout en Haute Ubaye, à proximité immédiate de l'Italie. Déclenchement possible au passage d'un skieur, pouvant engendrer des avalanches généralement de taille 1, petite, et rarement de taille 2, moyenne. Ces plaques superficielles se forment pendant la petite chute de neige en fort régime de lombarde la nuit de jeudi à vendredi. Des plaques beaucoup plus anciennes et épaisses peuvent encore être présentes dans la neige restée sèche, soit au-dessus de 2200 m en versants ouest, nord et est ; elles sont cependant très localisées et leur déclenchement par un seul skieur est difficile, mais elles peuvent mobiliser d'importants volumes en cas de départ (taille 2, voire 3, grande, non exclue).

Départs spontanés : rares et peu volumineux ; en Haute Ubaye, vers la frontière italienne, départs de plaques à vent de taille 1 à 2, dans les zones de plus forte accumulation par la lombarde. Activité en neige humide peu probable, et celle sous forme d'avalanches de glissement en atténuation ; un départ de taille 2 n'est pas exclu en pentes d'un large secteur sud, en terrain favorable (pentes herbeuses, dalles rocheuses).

Qualité de la neige

Enneigement proche des normales pour un début mars.
Données observées : 65 cm à la Nivôse de Restefond à 2550 m (secteur venté), 88 cm au-dessus de Larche à 2270 m en adret.

Enneigement skiable : vers 1500 m en ubacs, 1800/1900 m en adrets peu pentus.

État de la neige en surface : manteau neigeux bien densifié par le gel/regel des jours précédents en adrets, ainsi qu'en ubacs de basse altitude ; le regel vendredi matin est un peu moins bon, et l'humidification en journée plus limitée. Neige sèche souvent durcie par le vent en ubacs de haute altitude, au-dessus de 2200/2300 m, parfois en vieille neige meuble dans les pentes et combes abritées, et surmontée d'un peu de neige plus récente. Anciennes corniches épaisses.

Aperçu météo pour le vendredi 06 mars

	nuit	matin	après-midi	soir
Généralement couvert, un peu plus venté et frais, toujours une importante concentration de poussières déseertiques				
Pluie-Neige	1 800 m	1 800 m		
Iso 0 °C	2 300 m	2 100 m	2 400 m	2 500 m
Vent 2000 m	45 km/h	45 km/h	45 km/h	50 km/h
Vent 3000 m	55 km/h	65 km/h	60 km/h	55 km/h

Épaisseur de neige hors-piste

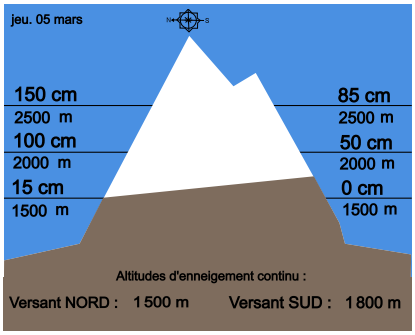

Précipitations à 1800 m

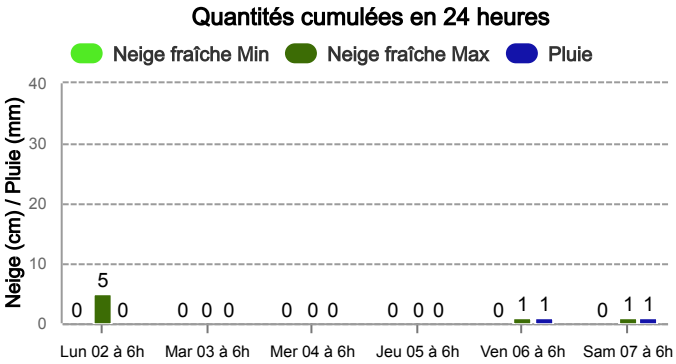

Tendance du samedi 07 mars

Indice de risque limité

Peu d'évolution de la situation nivologique.
Risque limité aux ubacs de haute altitude.

Pour consulter la vigilance en cours, veuillez vous rendre sur le site https://vigilance.meteofrance.fr/fr

Météo-France - 73 avenue de Paris, 94165 Saint-Mandé cedex - Contact : contact@meteo.fr

Rédigé par Météo-France avec la contribution des observateurs du réseau nivo-météorologiques. Partenariat : ANMSM (Maires de Stations de Montagne), DSF (Domaines Skiables de France), ADSP (Directeurs de Pistes et de la Sécurité des Stations de Sports d'Hiver) et autres acteurs de la montagne.

Bulletin neige & avalanches par téléphone au **0 892 68 10 20** Service 0,35 € / min + prix appel

RÉPUBLIQUE FRANÇAISE
Liberté Égalité Fraternité

METEO FRANCE
À VOS CÔTÉS, DANS UN CLIMAT QUI CHANGE

Bulletin d'estimation du risque d'avalanche

(valable en dehors des pistes balisées et ouvertes)

MASSIF : Ubaye

Rédigé le jeudi 5 mars 2026 à 15h

Conditions nivo-météo des 7 derniers jours

	ven. 27/02				sam. 28/02				dim. 01/03				lun. 02/03				mar. 03/03				mer. 04/03				jeu. 05/03			
	03h	09h	15h	21h	03h	09h	15h	21h	03h	09h	15h	21h	03h	09h	15h	21h	03h	09h	15h	21h	03h	09h	15h	21h	03h	09h	15h	21h
Météo																												
Vent (km/h)	10	10	10	10	10	20	20	15	20	20	20	20	10	15	15	10	10	10	10	10	10	10	10	10	20	20	30	45
à 3000m																												
Vent (km/h)	5	5	10	5	5	10	15	5	5	10	15	10	10	15	15	10	10	5	10	10	5	5	10	10	25	30	35	40
à 2000m																												

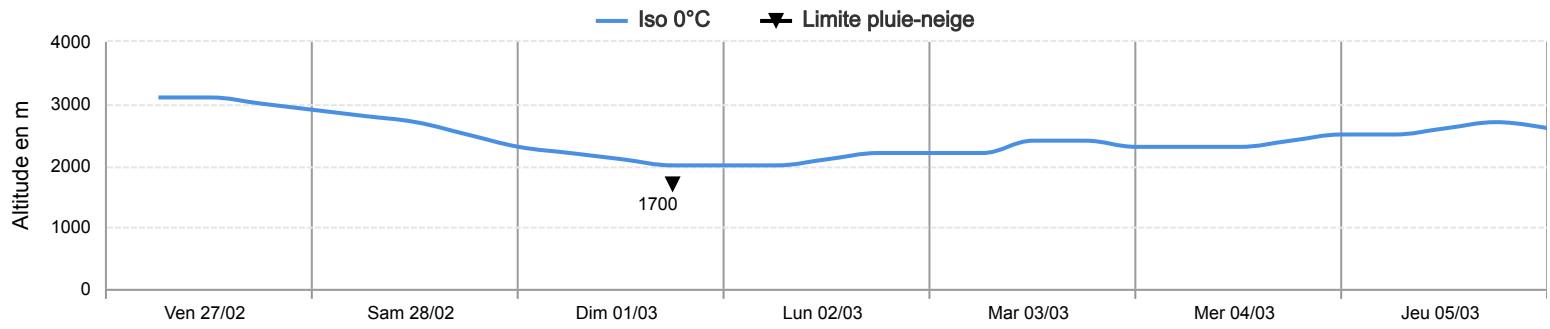

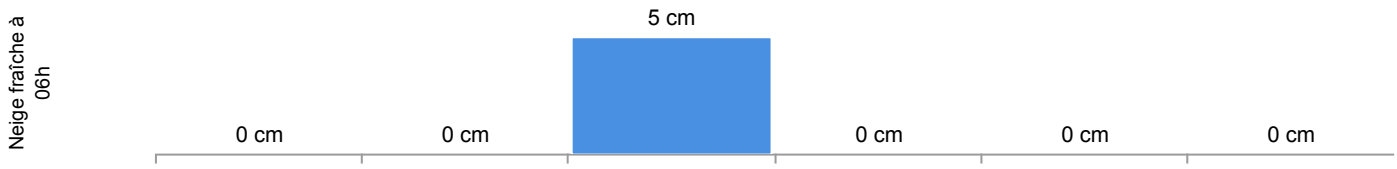

Risque d'avalanche	ven. 27/02	sam. 28/02	dim. 01/03	lun. 02/03	mar. 03/03	mer. 04/03	jeu. 05/03
	2	2	2	2	2	2	2

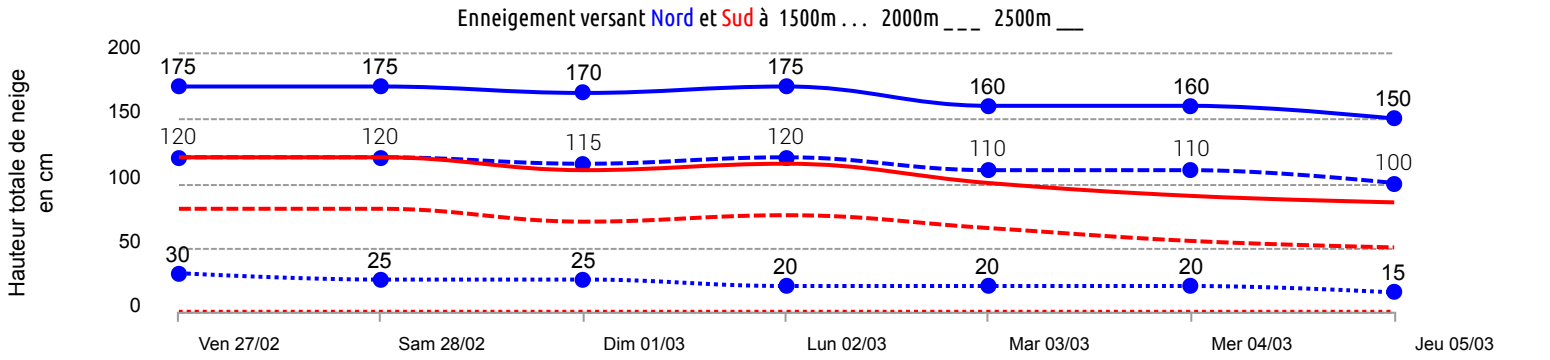

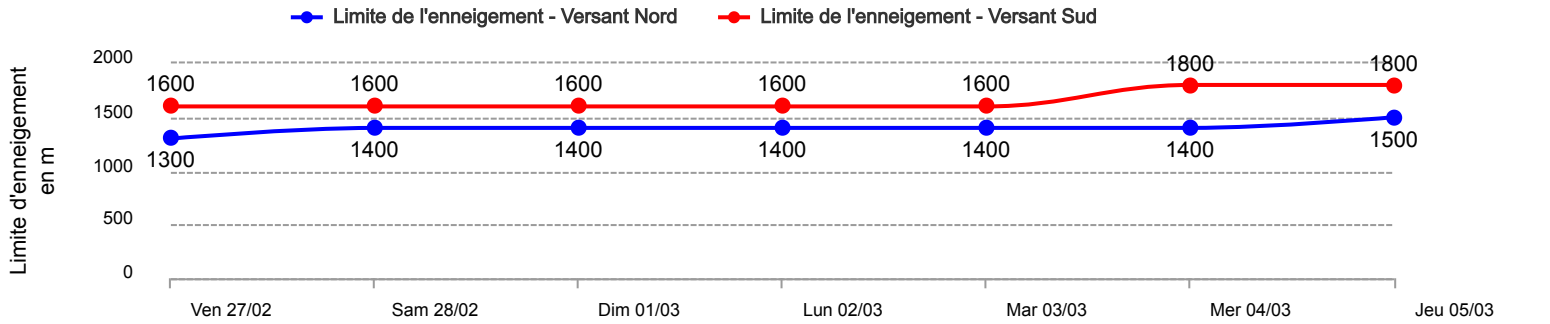

Pour consulter la vigilance en cours, veuillez vous rendre sur le site https://vigilance.meteofrance.fr/fr

Météo-France - 73 avenue de Paris, 94165 Saint-Mandé cedex - Contact : contact@meteo.fr

Rédigé par Météo-France avec la contribution des observateurs du réseau nivo-météorologiques. Partenariat : ANMSM (Maires de Stations de Montagne), DSF (Domaines Skiables de France), ADSP (Directeurs de Pistes et de la Sécurité des Stations de Sports d'Hiver) et autres acteurs de la montagne.

Bulletin neige & avalanches par téléphone au

0 892 68 10 20 Service 0,35 € / min + prix appel