Bulletin d'estimation du risque d'avalanche

(valable en dehors des pistes balisées et ouvertes)

MASSIF : Aspe Ossau

Rédigé le jeudi 5 mars 2026 à 16h

Estimation des risques pour le : VENDREDI 06 MARS

AVALANCHES DE FOND, QUELQUES NOUVELLES PLAQUES EN HAUTE-MONTAGNE.

2

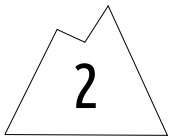

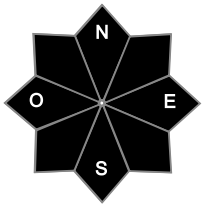

Plaques et fonte

Indices de risque : 5 très fort - 4 fort - 3 marqué - 2 limité - 1 faible -- En noir : les pentes les plus dangereuses

Indice de risque limité.

Départs spontanés : Avalanches de fond.

Déclenchements provoqués : Quelques plaques en haute-montagne

Stabilité du manteau neigeux

Situation avalancheuse typique :

avalanches de fond

couche fragile persistante

Départs spontanés : En neige humide. Départs ponctuels et avalanches de fond, possibles en **toutes orientations sous 2200m** dès le matin, dans l'ambiance douce et humide. Les plus importantes, emportant l'intégralité du manteau, peuvent atteindre une taille moyenne à grande, surtout en pentes est mieux enneigées. Faible activité plus haut par températures négatives et en l'absence de rayonnement solaire.
Signes parfois à observer : **gueules de baleine** (fissures qui s'ouvrent dans le manteau perpendiculairement à la pente). Trouées d'avalanche récentes jusqu'à l'herbe, à proximité.

Déclenchements provoqués : **Au-dessus de 2400/2500 m vers les pentes Nord**, le manteau neigeux est encore hivernal.
Des couches fragiles sont enfouies dans le manteau neigeux, souvent difficilement sollicitables à cause de leur profondeur, mais le déclenchement d'une avalanche est encore possible aux zones où le manteau est plus mince, rapprochant les couches fragiles de la surface : entrées des combes, ruptures de pentes par exemple ou par le déclenchement d'une plaque récente décrite ci-dessus.

Autres : Peu ou pas de dégel attendu au-dessus de 2300m Neige restant dure et glissante.

Qualité de la neige

Enneigement : La fonte est faible en nord mais les versants sud se dégarnissent peu à peu, l'enneigement est bon au-dessus de 1800 m en nord mais bien irrégulièrement réparti, crêtes dégarnies en particulier à l'ouest, combes plus chargées et corniches restant souvent imposantes.
Limites skiables : à partir de 1600/1700 m.
État de la neige : Manteau printanier en sud et sous 2400/2500 m en nord, regelé le matin, ramollissant rapidement en tous versants sous 2200m avec l'arrivée des nuages, restant dur plus haut. En nord, au-dessus de 2300 m, alternance de neige sèche et meuble dans les combes et de zones en neige très dure ou en glace sur les zones vontées. Une petite couche de neige vient se déposer au-dessus de 2100 m en journée.

Aperçu météo pour le vendredi 06 mars

	nuit	matin	après-midi	soir
	1800 m			
Pluie-Neige		1 900 m	1 900 m	1 900 m
Iso 0 °C	2 300 m	2 100 m	2 100 m	2 100 m
Vent 1500 m	10 km/h	10 km/h	15 km/h	10 km/h
Vent 3000 m	20 km/h	15 km/h	20 km/h	15 km/h

Arrivée rapide de nuages réduisant la visibilité et apportant de faibles précipitations. Quelques éclaircies possibles l'après-midi.

Épaisseur de neige hors-piste

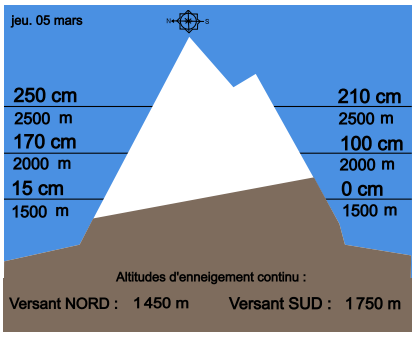

Précipitations à 1800 m

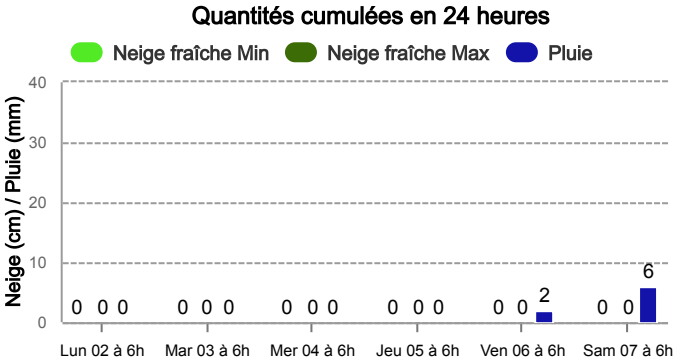

Tendance du samedi 07 mars

2

Indice de risque limité

Retour d'éclaircies favorisant les départs au soleil.

Pour consulter la vigilance en cours, veuillez vous rendre sur le site https://vigilance.meteofrance.fr/fr

Météo-France - 73 avenue de Paris, 94165 Saint-Mandé cedex - Contact : contact@meteo.fr

Rédigé par Météo-France avec la contribution des observateurs du réseau nivo-météorologiques. Partenariat : ANMSM (Maires de Stations de Montagne), DSF (Domaines Skiables de France), ADSP (Directeurs de Pistes et de la Sécurité des Stations de Sports d'Hiver) et autres acteurs de la montagne.

Bulletin neige & avalanches par téléphone au

0 892 68 10 20 Service 0,35 € / min + prix appel

Bulletin d'estimation du risque d'avalanche

(valable en dehors des pistes balisées et ouvertes)

MASSIF : Aspe Ossau

Rédigé le jeudi 5 mars 2026 à 16h

Conditions nivo-météo des 7 derniers jours

	ven. 27/02				sam. 28/02				dim. 01/03				lun. 02/03				mar. 03/03				mer. 04/03				jeu. 05/03			
	03h	09h	15h	21h	03h	09h	15h	21h	03h	09h	15h	21h	03h	09h	15h	21h	03h	09h	15h	21h	03h	09h	15h	21h	03h	09h	15h	21h
Météo																												
Vent (km/h)	40	45	30	25	15	10	10	10	15	20	60	65	55	45	50	40	35	15	15	15	25	25	30	40	45	45	35	25
à 3000m																												
Vent (km/h)	25	25	20	10	10	10	15	5	10	15	35	45	40	35	30	30	25	10	10	10	15	10	15	20	25	25	20	10
à 1500m																												

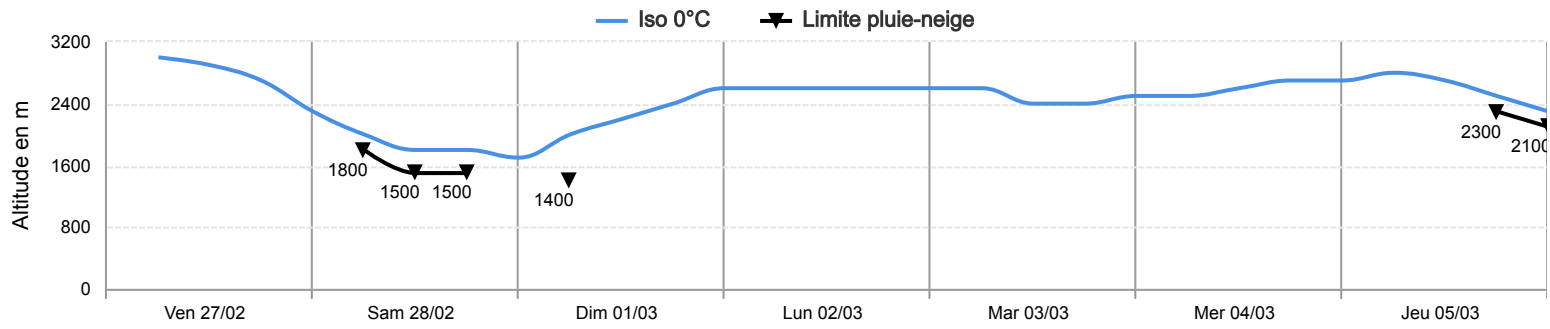

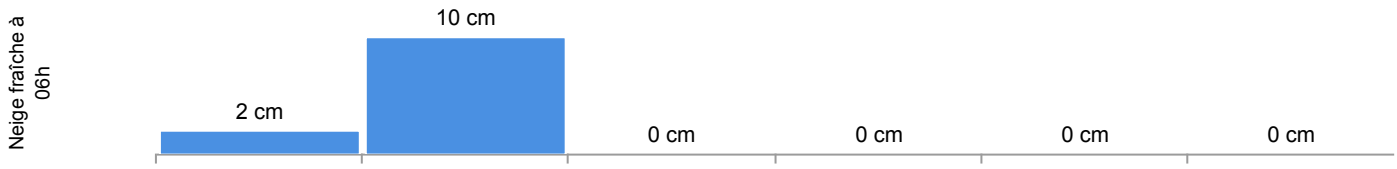

Risque d'avalanche	ven. 27/02	sam. 28/02	dim. 01/03	lun. 02/03	mar. 03/03	mer. 04/03	jeu. 05/03
	2	2	2	2	2	2	2

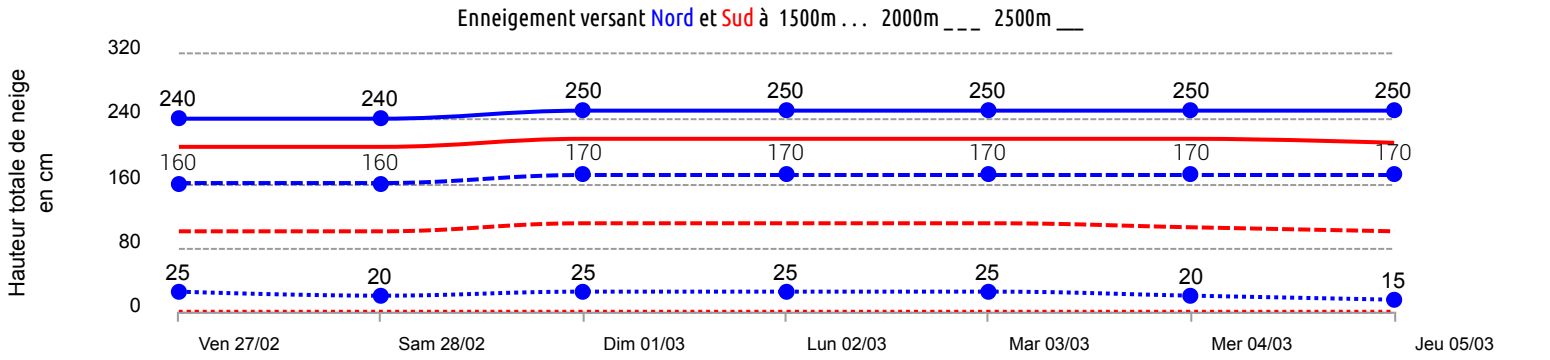

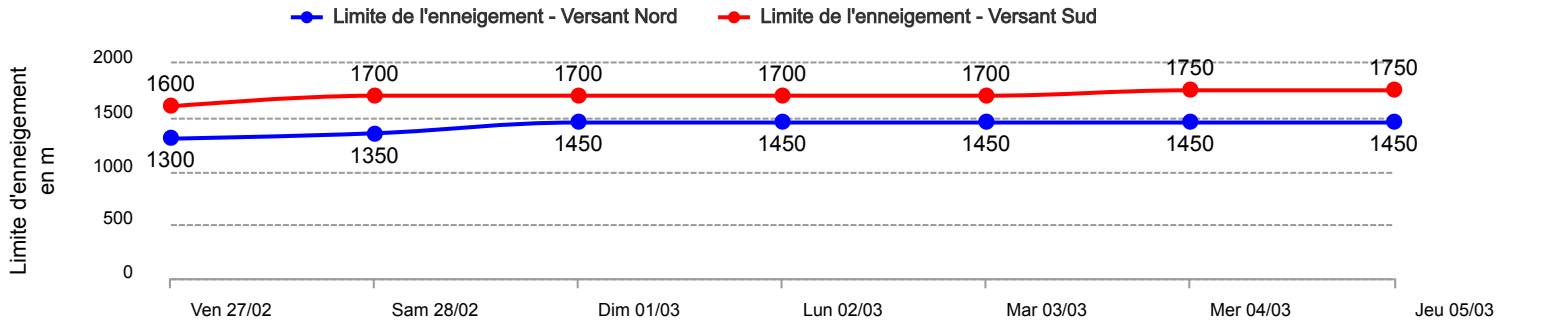

Pour consulter la vigilance en cours, veuillez vous rendre sur le site https://vigilance.meteofrance.fr/fr

Météo-France - 73 avenue de Paris, 94165 Saint-Mandé cedex - Contact : contact@meteo.fr

Rédigé par Météo-France avec la contribution des observateurs du réseau nivo-météorologiques. Partenariat : ANMSM (Maires de Stations de Montagne), DSF (Domaines Skiables de France), ADSP (Directeurs de Pistes et de la Sécurité des Stations de Sports d'Hiver) et autres acteurs de la montagne.

Bulletin neige & avalanches par téléphone au 0 892 68 10 20 Service 0,35 € / min + prix appel