# Bulletin d'estimation du risque d'avalanche

(valable en dehors des pistes balisées et ouvertes)

# MASSIF : Aure Louron

Rédigé le jeudi 5 mars 2026 à 16h

## Estimation des risques pour le : VENDREDI 06 MARS

**AVALANCHES DE FOND, QUELQUES NOUVELLES PLAQUES EN HAUTE-MONTAGNE.**

2

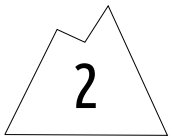


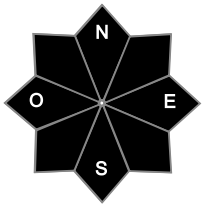


Plaques et fonte

Indices de risque : 5 très fort - 4 fort - 3 marqué - 2 limité - 1 faible -- En noir : les pentes les plus dangereuses

Indice de risque limité.

**Départs spontanés :** Avalanches de fond.

**Déclenchements provoqués :** Quelques plaques en haute-montagne

## Stabilité du manteau neigeux

**Situation avalancheuse typique :**

avalanches de fond

couche fragile persistante

Départs spontanés : En neige humide. Départs ponctuels et avalanches de fond, possibles en **toutes orientations sous 2200m** dès le matin, dans l'ambiance douce et humide. Les plus importantes, emportant l'intégralité du manteau, peuvent atteindre une taille moyenne à grande, surtout en pentes est mieux enneigées. Faible activité plus haut par températures négatives et en l'absence de rayonnement solaire.
Signes parfois à observer : **gueules de baleine** (fissures qui s'ouvrent dans le manteau perpendiculairement à la pente). Trouées d'avalanche récentes jusqu'à l'herbe, à proximité.

Déclenchements provoqués : **Au-dessus de 2200/2300 m vers les pentes Nord**, le manteau neigeux est encore hivernal.
Des couches fragiles sont enfouies dans le manteau neigeux, souvent difficilement sollicitables à cause de leur profondeur, mais le déclenchement d'une avalanche est encore possible aux zones où le manteau est plus mince, rapprochant les couches fragiles de la surface : entrées des combes, ruptures de pentes par exemple ou par le déclenchement d'une plaque récente décrite ci-dessus.

Autres : Peu ou pas de dégel attendu au-dessus de 2300m Neige restant dure et glissante.

## Qualité de la neige

**Enneigement** : La fonte est faible en nord mais les versants sud se dégarnissent peu à peu, l'enneigement est bon au-dessus de 1800 m en nord mais bien irrégulièrement réparti, crêtes dégarnies en particulier à l'ouest, combes plus chargées et corniches restant souvent imposantes.
**Limites skiables** : à partir de 1600/1700 m.
**État de la neige** : Manteau printanier en sud et sous 2200/2300 m en nord, regelé le matin, ramollissant rapidement en tous versants sous 2200m avec l'arrivée des nuages, restant dur plus haut. En nord, au-dessus de 2300 m, alternance de neige sèche et meuble dans les combes et de zones en neige très dure ou en glace sur les zones vontées. Une petite couche de neige vient se déposer au-dessus de 2100 m en journée.

## Aperçu météo pour le vendredi 06 mars

| | nuit | matin | après-midi | soir |
|---|---|---|---|---|
| | | | | |
| | Arrivée rapide de nuages réduisant la visibilité et apportant de faibles précipitations. Quelques éclaircies possibles l'après-midi. | | | |
| **Pluie-Neige** | | 1 900 m | 1 900 m | |
| **Iso 0 °C** | 2 400 m | 2 200 m | 2 200 m | 2 200 m |
| **Vent 1500 m** | 10 km/h | 10 km/h | 15 km/h | 5 km/h |
| **Vent 3000 m** | 55 km/h | 55 km/h | 45 km/h | 45 km/h |

## Épaisseur de neige hors-piste

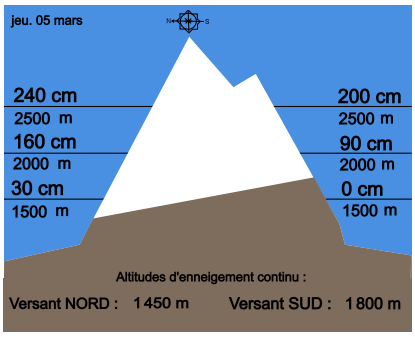


## Précipitations à 1800 m

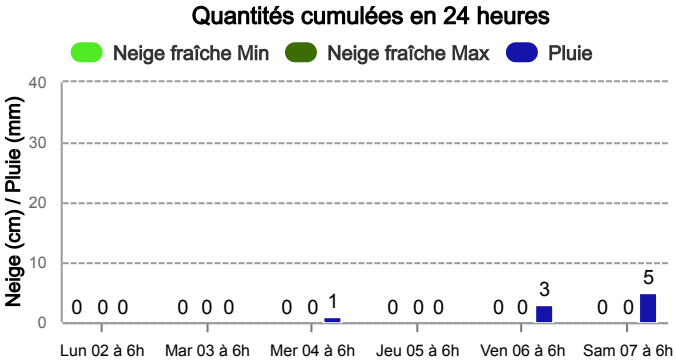


## Tendance du samedi 07 mars

2

**Indice de risque limité**

Retour d'éclaircies favorisant les départs au soleil.

Pour consulter la vigilance en cours, veuillez vous rendre sur le site https://vigilance.meteofrance.fr/fr

Météo-France - 73 avenue de Paris, 94165 Saint-Mandé cedex - Contact : contact@meteo.fr

Rédigé par Météo-France avec la contribution des observateurs du réseau nivo-météorologiques. Partenariat : ANMSM (Maires de Stations de Montagne), DSF (Domaines Skiables de France), ADSP (Directeurs de Pistes et de la Sécurité des Stations de Sports d'Hiver) et autres acteurs de la montagne.

Bulletin neige & avalanches par téléphone au

0 892 68 10 20 Service 0,35 € / min + prix appel

RÉPUBLIQUE FRANÇAISE
*Liberté Égalité Fraternité*

METEO FRANCE
À VOS CÔTÉS, DANS UN CLIMAT QUI CHANGE

# Bulletin d'estimation du risque d'avalanche

## (valable en dehors des pistes balisées et ouvertes)

# MASSIF : Aure Louron

Rédigé le jeudi 5 mars 2026 à 16h

## Conditions nivo-météo des 7 derniers jours

| | ven. 27/02 | | | | sam. 28/02 | | | | dim. 01/03 | | | | lun. 02/03 | | | | mar. 03/03 | | | | mer. 04/03 | | | | jeu. 05/03 | | | |
|---|---|---|---|---|---|---|---|---|---|---|---|---|---|---|---|---|---|---|---|---|---|---|---|---|---|---|---|---|
| | 03h | 09h | 15h | 21h | 03h | 09h | 15h | 21h | 03h | 09h | 15h | 21h | 03h | 09h | 15h | 21h | 03h | 09h | 15h | 21h | 03h | 09h | 15h | 21h | 03h | 09h | 15h | 21h |
| Météo | | | | | | | | | | | | | | | | | | | | | | | | | | | | |
| Vent (km/h) | 30 | 30 | 30 | 40 | 45 | 45 | 25 | 15 | 25 | 40 | 55 | 60 | 60 | 50 | 35 | 30 | 20 | 15 | 15 | 15 | 25 | 35 | 45 | 45 | 45 | 45 | 40 | 35 |
| à 3000m | | | | | | | | | | | | | | | | | | | | | | | | | | | | |
| Vent (km/h) | 15 | 20 | 20 | 10 | 10 | 10 | 15 | 5 | 10 | 20 | 25 | 35 | 35 | 30 | 20 | 15 | 20 | 10 | 10 | 10 | 10 | 20 | 25 | 30 | 30 | 25 | 20 | 20 |
| à 1500m | | | | | | | | | | | | | | | | | | | | | | | | | | | | |

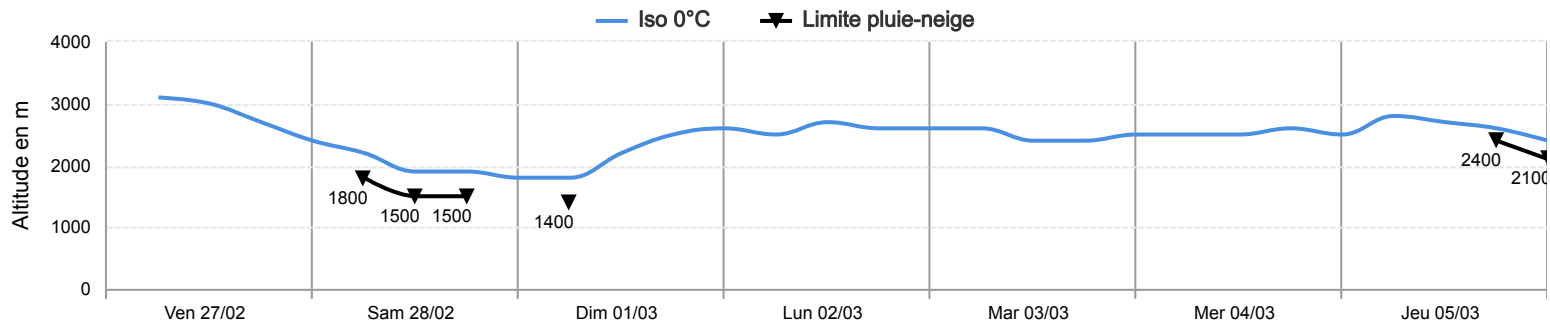


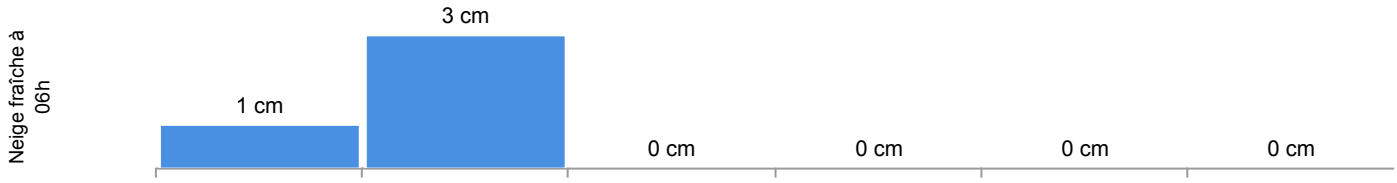


| Risque d'avalanche | ven. 27/02 | sam. 28/02 | dim. 01/03 | lun. 02/03 | mar. 03/03 | mer. 04/03 | jeu. 05/03 |
|---|---|---|---|---|---|---|---|
| | 2 | 2 | 2 | 2 | 2 | 2 | 2 |

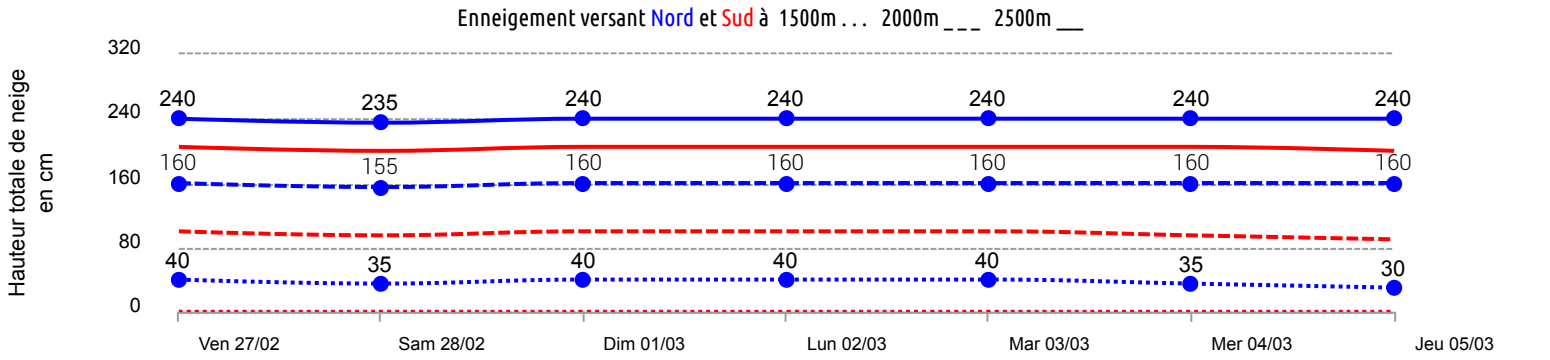


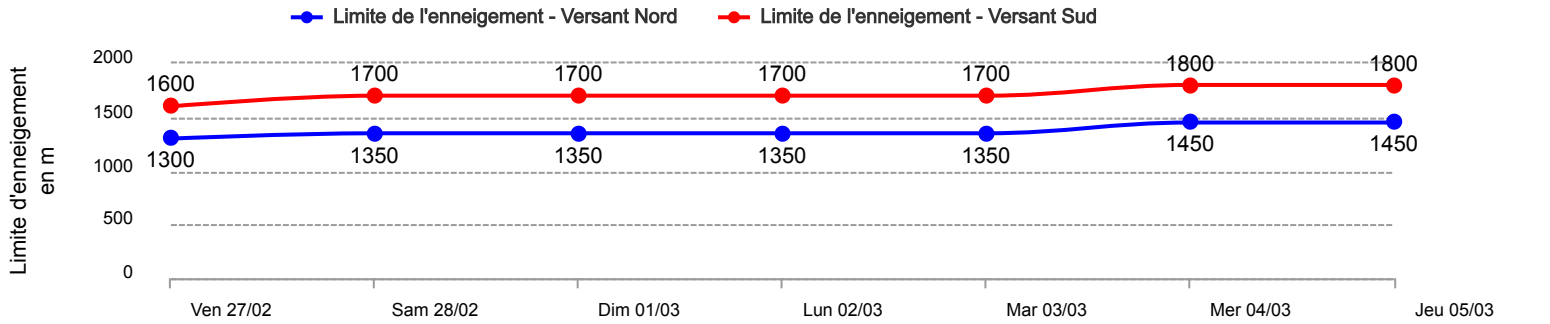


Pour consulter la vigilance en cours, veuillez vous rendre sur le site https://vigilance.meteofrance.fr/fr


Météo-France - 73 avenue de Paris, 94165 Saint-Mandé cedex - Contact : contact@meteo.fr



Rédigé par Météo-France avec la contribution des observateurs du réseau nivo-météorologiques. Partenariat : ANMSM (Maires de Stations de Montagne), DSF (Domaines Skiables de France), ADSP (Directeurs de Pistes et de la Sécurité des Stations de Sports d'Hiver) et autres acteurs de la montagne.



Bulletin neige & avalanches par téléphone au
0 892 68 10 20 Service 0,35 € / min + prix appel