Bulletin d'estimation du risque d'avalanche

(valable en dehors des pistes balisées et ouvertes)

MASSIF : Beaufortain

Rédigé le jeudi 5 mars 2026 à 16h

Estimation des risques pour le : VENDREDI 06 MARS

MANTEAU PLUTÔT STABLE, RARES AVALANCHES DE GLISSEMENT ET FORMATION DE PLAQUES SOUS LE FOEHN.

2

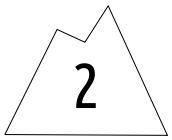

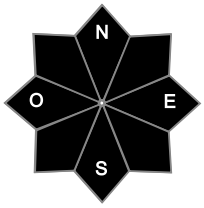

Indice de risque limité.

Départs spontanés : rares avalanches de glissement.

Déclenchements provoqués : rares petites plaques en formation sous le foehn.

Indices de risque : 5 très fort - 4 fort - 3 marqué - 2 limité - 1 faible -- En noir : les pentes les plus dangereuses

Stabilité du manteau neigeux

Situation avalancheuse typique : avalanches de fond neige ventée

Déclenchements provoqués : **rares petites plaques à vent** en formation sous le foehn. Elles sont localisées **au-dessus de 2000 m** dans les **versants froids** (nord) où la neige était restée poudreuse jusqu'à présent. **Déclenchement** parfois **facile** mais **cassures 10-20 cm maximum**.

Départs spontanés : **rares avalanches de glissement** (plaques de fond), plutôt **sous 2400 m** mais parfois plus haut sur des terrains très propices (dalles rocheuses raides notamment). Les versants est, sud et ouest sont les principaux concernés. Le manteau neigeux actuel étant épais, les **volumes mobilisés peuvent être conséquents** : tailles généralement **moyennes** mais **une grande avalanche n'est pas exclue**.

Qualité de la neige

Enneigement : fonte rapide de la neige en sud et aux basses altitudes sous les assauts du soleil, de la douceur puis désormais du foehn. Ailleurs, malgré le tassement, l'enneigement reste très bon pour la saison.

Limite skiable : encore skiable dès 1100 m dans les prairies orientées nord, plutôt 1400/1500 m en sud pas trop raide.

Qualité de la neige : mauvais regel sous 1800/2000 m avec potentiellement une fine croute désagréable sous cette altitude. Au-dessus,
- en nord, neige encore froide, poudreuse dense dans les vallons soumis au foehn, ou frisette (vieille poudre) agréable à skier.
- en sud/est/ouest, neige dure qui ramollit très difficilement en journée (voile dense).

Aperçu météo pour le vendredi 06 mars

nuit	matin	après-midi	soir

Ciel très voilé, accompagné de poussières sahariennes abaissant fortement la visibilité. Foehn modéré dans les vallons exposés.

Pluie-Neige				
Iso 0 °C	2 700 m	2 600 m	2 600 m	2 600 m
Vent 2000 m	30 km/h	30 km/h	25 km/h	20 km/h
Vent 3000 m	30 km/h	30 km/h	30 km/h	30 km/h

Épaisseur de neige hors-piste

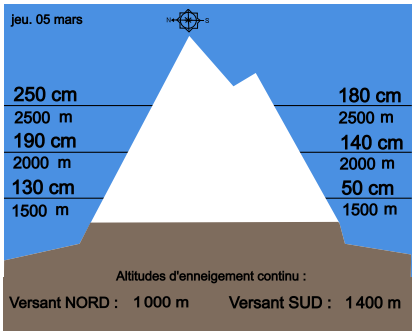

Précipitations à 1800 m

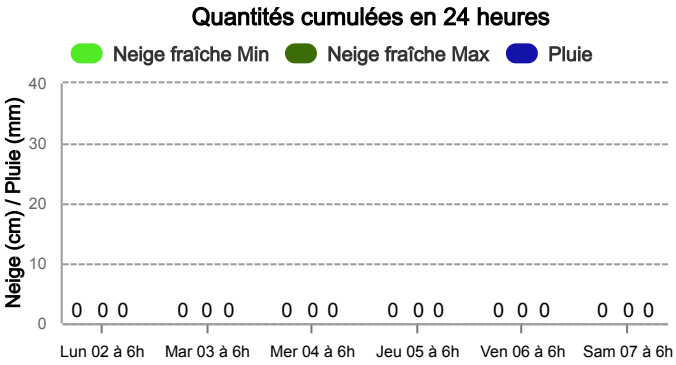

Tendance du samedi 07 mars

2

Indice de risque limité

Peu d'évolution. Le ciel est dégagé en journée, ce qui devrait permettre une humidification à nouveau efficace dans les versants ensoleillés. Le risque reste limité le temps que les petites plaques à vent se stabilisent.

Pour consulter la vigilance en cours, veuillez vous rendre sur le site https://vigilance.meteofrance.fr/fr

Météo-France - 73 avenue de Paris, 94165 Saint-Mandé cedex - Contact : contact@meteo.fr

Rédigé par Météo-France avec la contribution des observateurs du réseau nivo-météorologiques. Partenariat : ANMSM (Maires de Stations de Montagne), DSF (Domaines Skiables de France), ADSP (Directeurs de Pistes et de la Sécurité des Stations de Sports d'Hiver) et autres acteurs de la montagne.

Bulletin neige & avalanches par téléphone au

0 892 68 10 20 Service 0,35 € / min + prix appel

RÉPUBLIQUE FRANÇAISE
Liberté Égalité Fraternité

METEO FRANCE
À VOS CÔTÉS, DANS UN CLIMAT QUI CHANGE

Bulletin d'estimation du risque d'avalanche

(valable en dehors des pistes balisées et ouvertes)

MASSIF : Beaufortain

Rédigé le jeudi 5 mars 2026 à 16h

Conditions nivo-météo des 7 derniers jours

	ven. 27/02				sam. 28/02				dim. 01/03				lun. 02/03				mar. 03/03				mer. 04/03				jeu. 05/03			
	03h	09h	15h	21h	03h	09h	15h	21h	03h	09h	15h	21h	03h	09h	15h	21h	03h	09h	15h	21h	03h	09h	15h	21h	03h	09h	15h	21h
Météo																												
Vent (km/h)	15	15	20	20	25	25	20	20	20	20	20	20	15	15	15	15	15	15	10	10	15	15	20	20	20	25	30	30
à 3000m																												
Vent (km/h)	5	5	10	10	10	10	10	10	5	10	10	10	10	10	5	5	5	5	5	5	5	5	10	15	15	20	25	30
à 2000m																												

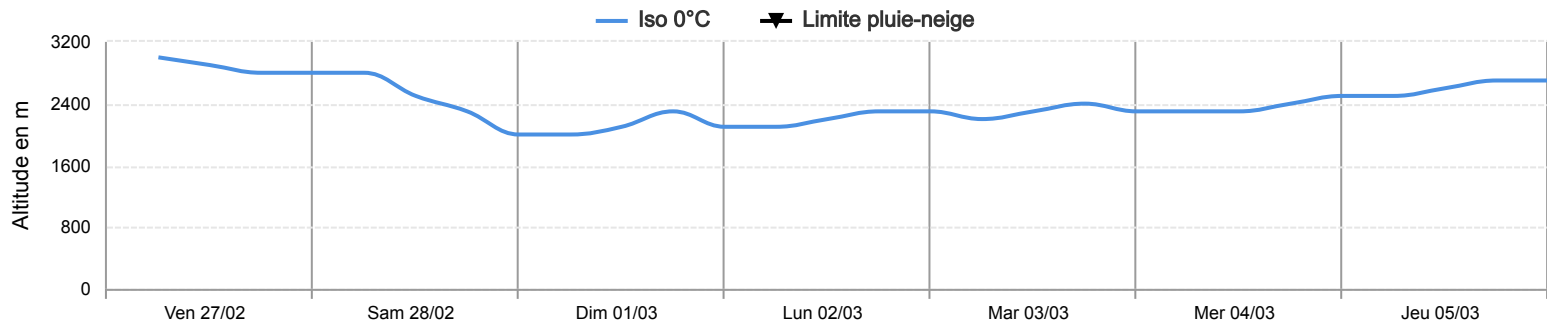

Neige fraîche à 06h

Ven 27/02	Sam 28/02	Dim 01/03	Lun 02/03	Mar 03/03	Mer 04/03
0 cm	0 cm	0 cm	0 cm	0 cm	0 cm

Risque d'avalanche	ven. 27/02	sam. 28/02	dim. 01/03	lun. 02/03	mar. 03/03	mer. 04/03	jeu. 05/03
	3	2	2	2	2	2	2

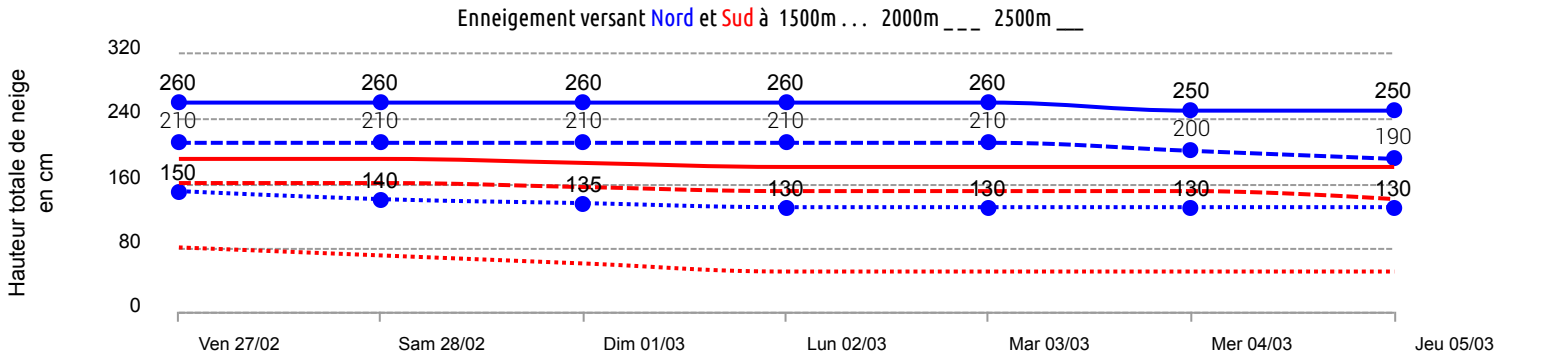

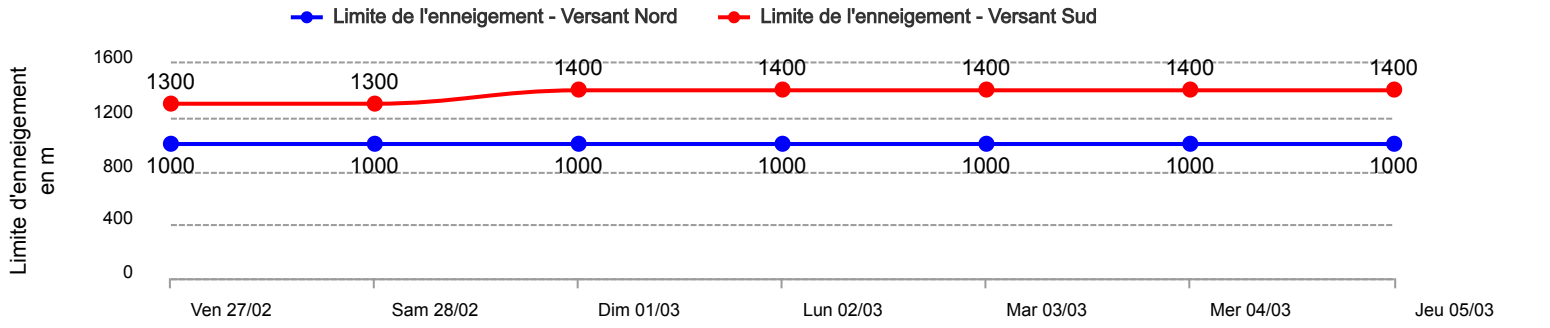

Pour consulter la vigilance en cours, veuillez vous rendre sur le site https://vigilance.meteofrance.fr/fr

Météo-France - 73 avenue de Paris, 94165 Saint-Mandé cedex - Contact : contact@meteo.fr

Bulletin neige & avalanches par téléphone au

0 892 68 10 20 Service 0,35 € / min + prix appel

Rédigé par Météo-France avec la contribution des observateurs du réseau nivo-météorologiques. Partenariat : ANMSM (Maires de Stations de Montagne), DSF (Domaines Skiables de France), ADSP (Directeurs de Pistes et de la Sécurité des Stations de Sports d'Hiver) et autres acteurs de la montagne.