RÉPUBLIQUE FRANÇAISE
Liberté Égalité Fraternité

METEO FRANCE
À VOS CÔTÉS, DANS UN CLIMAT QUI CHANGE

Bulletin d'estimation du risque d'avalanche

(valable en dehors des pistes balisées et ouvertes)

MASSIF : Cerdagne Canigou

Rédigé le jeudi 5 mars 2026 à 16h

Estimation des risques pour le : VENDREDI 06 MARS

GRANDES AVALANCHES DE NEIGE HUMIDE POSSIBLE SOUS 2000/2100M; MANTEAU NEIGEUX INSTABLE DANS LES CHUTES DE NEIGE CONSÉQUENTES EN ALTITUDE

3

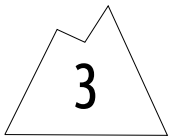

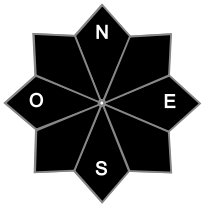

Sur Canigou

Indices de risque : 5 très fort - 4 fort - 3 marqué - 2 limité - 1 faible -- En noir : les pentes les plus dangereuses

Indice de risque marqué.

Départs spontanés : Avalanches de neige humide possible jusqu'au sol sous 2000m, avalanches de neige sèche en altitude avec des cumuls devenant importants

Déclenchements provoqués : Manteau neigeux instable en haute montagne avec des cumuls de neige fraiche conséquents

Stabilité du manteau neigeux

Situation avalancheuse typique : neige fraîche neige humide

Épisode avec des cumuls de neige conséquents au-dessus de 2300 m avec + 50/70 cm et localement plus vers le Canigou et + plutôt 20/40 cm vers le Puigmal.

Déclenchements provoqués :

En tous versants, mais surtout sous le vent de Sud-Est, au-dessus de 2200/2300m, des déclenchements d'avalanches sont possibles au passage d'un skieur. Les avalanches sont plutôt de taille moyenne mais pourront devenir grande en cours de journée avec les cumuls de neige importants. En effet, de nouvelles structures de plaques se forment au fil de la journée et des chutes de neige. Un déclenchement peut alors entraîner l'ensemble des chutes de neige avec des avalanches plus volumineuses notamment vers le Canigou, là où les cumuls attendus sont les plus importants.

Observables: quantités critiques de neige fraiche (30/50 cm et localement plus), fissures sous les skis, avalanche dans la neige récente en pente raide.

Départs spontanés :

- Avalanches de neige humide attendues sous 2100 m, moyenne à grande. Les pluies localement conséquentes (Canigou) remontant jusqu'à 2000/2100 m ce soir et demain peuvent favoriser les départs avec une humidification encore plus en profondeur et notamment dans les pentes raides de secteur Nord-Est où les quantités de neige en place sont conséquentes.
- Avalanches de neige sèche possibles en altitude au fil des chutes de neige, dans les pentes raides d'un large secteur Ouest à Nord. Ces avalanches pourront alors emporter l'ensemble des chutes de neige en cours.

Qualité de la neige

Enneigement :

L'enneigement est largement supérieur à celui des cinq dernières années et se situe au plus haut par rapport aux statistiques plus anciennes. Malgré la douceur de la semaine passée, la neige a plutôt bien résisté avec de bonnes quantités permettant de chausser dès 1500 à 1600m d'altitude. La limite skiable remonte doucement dans les pentes ensoleillées. Le manteau neigeux atteint rapidement 1m d'épaisseur et dépasse encore les 2m au dessus de 2200m.

Qualité de la neige :

Vendredi matin, la neige est humide dès le matin sous 2000/2100m avec les récentes pluies. En journée, elle s'humidifie encore plus profondément avec une neige lourde et très humide en tous versants. Plus haut, seulement à partir de 2300/2400 m, on trouvera une épaisse couche de neige fraiche dense et devenant plus légère en altitude. Elle sera déjà importante le matin et augmente au fil de la journée. La couverture sera parfois hétérogène avec le transport de neige par le vent en journée et surtout entre le Canigou (+50/70 cm en 24h) et le Puigmal (+20/40 cm en 24h).

Aperçu météo pour le vendredi 06 mars

	nuit	matin	après-midi	soir
Pluies conséquentes sous 2000m et cumuls de neige importants en haute montagne associé à un vent soutenu d'est à sud-est.				
Pluie-Neige	2 100 m	2 000 m	1 900 m	2 000 m
Iso 0 °C	2 400 m	2 300 m	2 300 m	2 200 m
Vent 2000 m	35 km/h	35 km/h	45 km/h	30 km/h
Vent 3000 m	60 km/h	60 km/h	60 km/h	55 km/h

Pour consulter la vigilance en cours, veuillez vous rendre sur le site https://vigilance.meteofrance.fr/fr

Météo-France - 73 avenue de Paris, 94165 Saint-Mandé cedex - Contact : contact@meteo.fr

Rédigé par Météo-France avec la contribution des observateurs du réseau nivo-météorologiques. Partenariat : ANMSM (Maires de Stations de Montagne), DSF (Domaines Skiables de France), ADSP (Directeurs de Pistes et de la Sécurité des Stations de Sports d'Hiver) et autres acteurs de la montagne.

Bulletin neige & avalanches par téléphone au

0 892 68 10 20 Service 0,35 € / min + prix appel

Bulletin d'estimation du risque d'avalanche

(valable en dehors des pistes balisées et ouvertes)

MASSIF : Cerdagne Canigou

Rédigé le jeudi 5 mars 2026 à 16h

Épaisseur de neige hors-piste

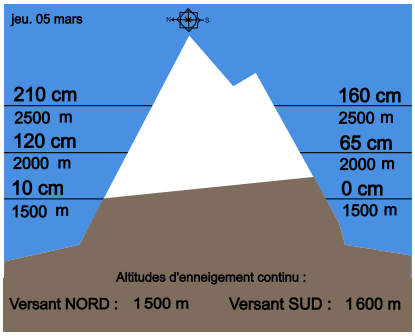

Précipitations à 1800 m

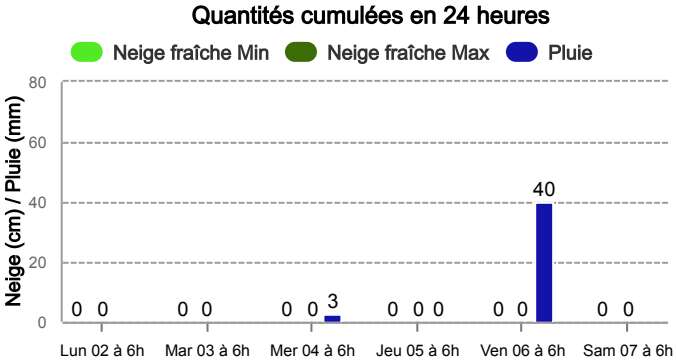

Tendance du samedi 07 mars

Indice de risque marqué

Stationnaire malgré une stabilisation à venir dans la neige fraiche.

Pour consulter la vigilance en cours, veuillez vous rendre sur le site https://vigilance.meteofrance.fr/fr

Météo-France - 73 avenue de Paris, 94165 Saint-Mandé cedex - Contact : contact@meteo.fr

Rédigé par Météo-France avec la contribution des observateurs du réseau nivo-météorologiques. Partenariat : ANMSM (Maires de Stations de Montagne), DSF (Domaines Skiables de France), ADSP (Directeurs de Pistes et de la Sécurité des Stations de Sports d'Hiver) et autres acteurs de la montagne.

Bulletin neige & avalanches par téléphone au

0 892 68 10 20 Service 0,35 € / min + prix appel

RÉPUBLIQUE FRANÇAISE
Liberté Égalité Fraternité

METEO FRANCE
À VOS CÔTÉS, DANS UN CLIMAT QUI CHANGE

Bulletin d'estimation du risque d'avalanche
(valable en dehors des pistes balisées et ouvertes)
MASSIF : Cerdagne Canigou

Rédigé le jeudi 5 mars 2026 à 16h

Conditions nivo-météo des 7 derniers jours

	ven. 27/02				sam. 28/02				dim. 01/03				lun. 02/03				mar. 03/03				mer. 04/03				jeu. 05/03			
	03h	09h	15h	21h	03h	09h	15h	21h	03h	09h	15h	21h	03h	09h	15h	21h	03h	09h	15h	21h	03h	09h	15h	21h	03h	09h	15h	21h
Météo																												
Vent (km/h)	20	20	25	30	30	30	30	20	20	25	25	25	40	50	50	40	45	35	25	25	40	35	40	25	45	50	50	50
à 3000m																												
Vent (km/h)	15	15	15	20	15	15	20	10	10	15	20	15	20	30	30	25	30	25	20	15	25	20	25	15	30	30	30	30
à 2000m																												

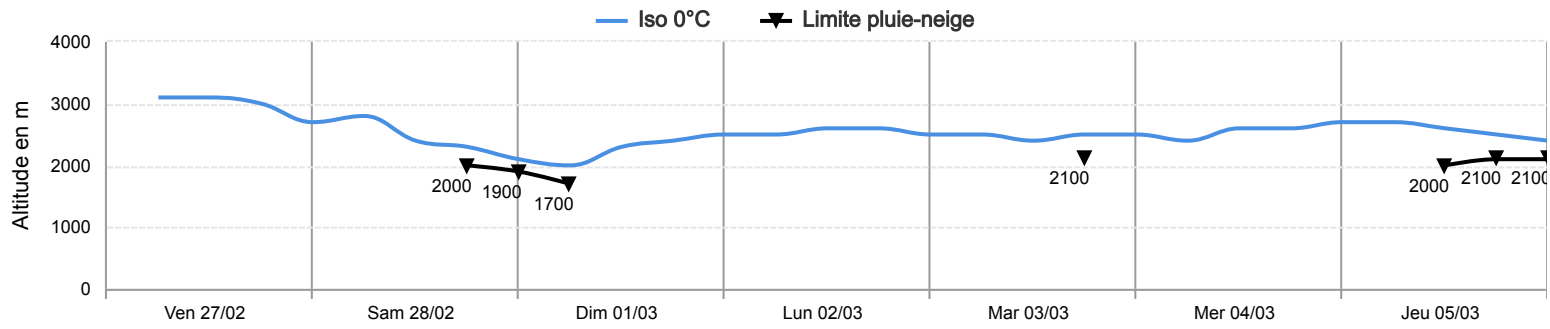

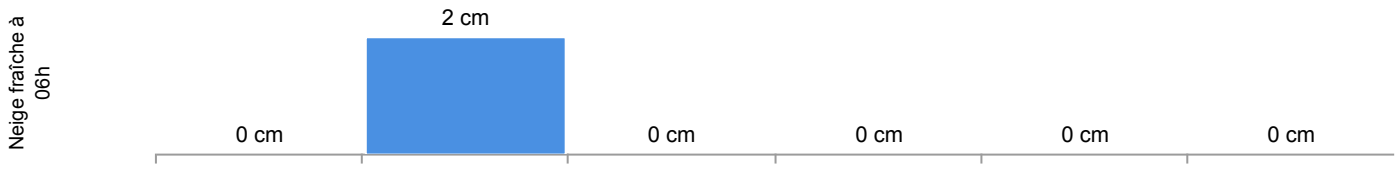

Risque d'avalanche	ven. 27/02	sam. 28/02	dim. 01/03	lun. 02/03	mar. 03/03	mer. 04/03	jeu. 05/03
	2	2	2	2	2	2	3

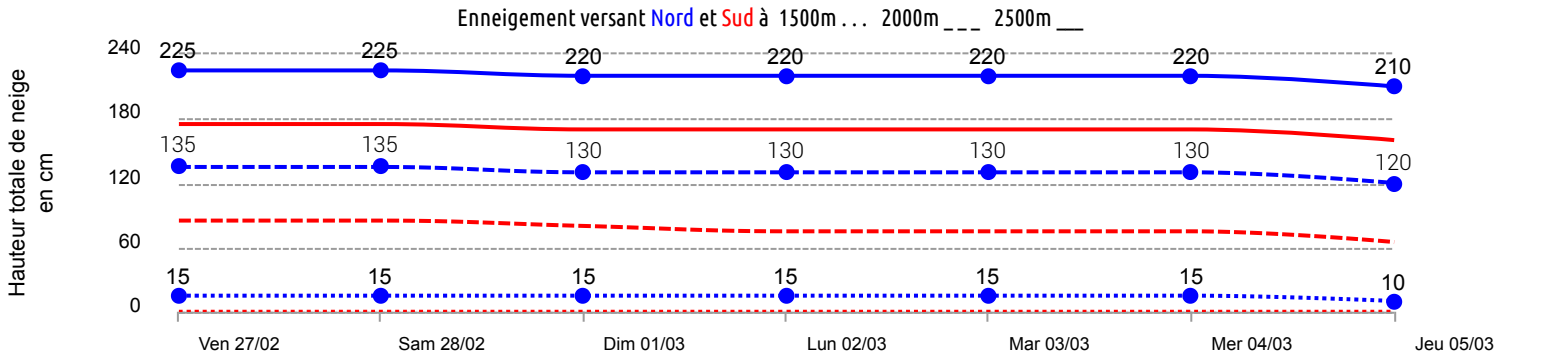

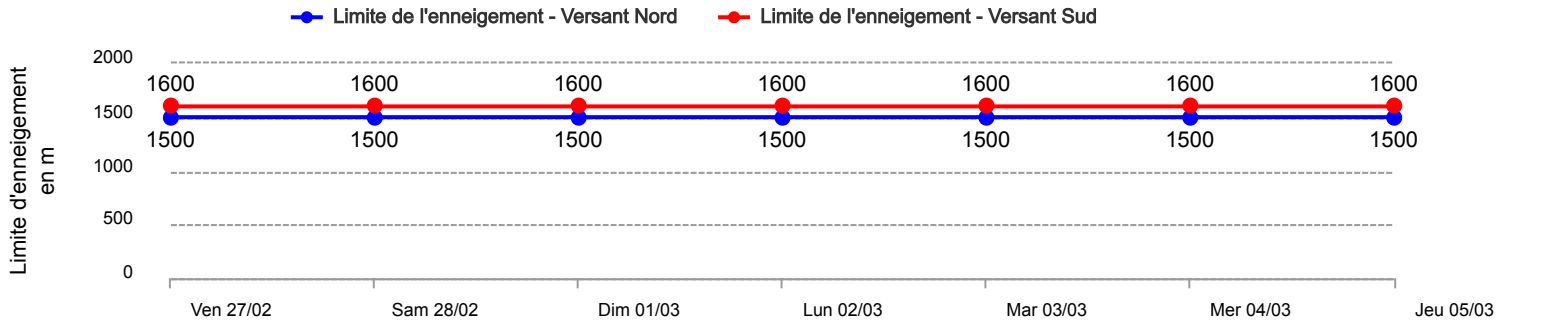

Pour consulter la vigilance en cours, veuillez vous rendre sur le site https://vigilance.meteofrance.fr/fr

Météo-France - 73 avenue de Paris, 94165 Saint-Mandé cedex - Contact : contact@meteo.fr

Rédigé par Météo-France avec la contribution des observateurs du réseau nivo-météorologiques. Partenariat : ANMSM (Maires de Stations de Montagne), DSF (Domaines Skiables de France), ADSP (Directeurs de Pistes et de la Sécurité des Stations de Sports d'Hiver) et autres acteurs de la montagne.

Bulletin neige & avalanches par téléphone au
0 892 68 10 20 Service 0,35 € / min + prix appel