Bulletin d'estimation du risque d'avalanche

(valable en dehors des pistes balisées et ouvertes)

MASSIF : Couserans

Rédigé le jeudi 5 mars 2026 à 16h

Estimation des risques pour le : VENDREDI 06 MARS

HUMIDIFICATION GÉNÉRALISÉ SOUS 2100 M; QUELQUES STRUCTURES DE PLAQUES EN ALTITUDE AVEC LE TRANSPORT DE NEIGE PAR LE VENT

2

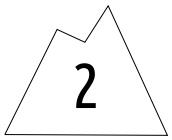

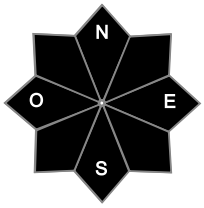

Indice de risque limité.

Départs spontanés : Avalanches de neige humide, rarement grandes

Déclenchements provoqués : Nouvelles fines structures de plaques en altitude

Indices de risque : 5 très fort - 4 fort - 3 marqué - 2 limité - 1 faible -- En noir : les pentes les plus dangereuses

Stabilité du manteau neigeux

Situation avalancheuse typique : neige humide neige ventée

Départs spontanés :

Activité attendue demain avec des avalanches de neige humide de taille petite à moyenne, plus rarement grande. Les pluies remontant jusqu'à 2100 m à partir de ce soir et demain en journée peuvent favoriser les départs de telles avalanches avec une humidification encore plus en profondeur et notamment dans quelques versants ombragés où le manteau neigeux n'est pas encore humidifié totalement. De plus, il est reporté dans de nombreuses orientations de larges fissures : ce nouvel apport d'eau liquide pourrait ainsi favoriser le départ d'épaisses avalanches de fond

Déclenchements provoqués :

Petites avalanches de plaques déclenchables dans les nouvelles chutes de neige. Des nouvelles structures de plaques vont se former au-dessus de 2200/2400 m dans les secteurs où les chutes seront sous forme de neige plus froide : elles seront souvent assez fines et localisées dans les versants nord d'altitude, plutôt proche des crêtes. Ces accumulations se situent par contre sur des couches fragiles plus enfouies en nord d'altitude qui sont difficilement déclenchables mais qui pourraient alors donner de rares avalanches plus volumineuses.

Observables : neige travaillée par le vent en surface, corniche surplombant la pente

Qualité de la neige

Enneigement :

L'enneigement est encore excédentaire après les perturbations neigeuses depuis le début de l'année, même si les derniers jours font bien fondre et tasser la neige. Les vallons ombragés sont encore enneigés avec des quantités de neige importantes dès 1400/1600 m notamment en versant Est et Nord.

La limite skiable remonte par rapport à hier autour de 1500/1600m plein Sud alors que certaines vallées ombragées sont encore enneigées dès 1300m. Sur les parties hautes du massif, les pentes Ouest ont souvent été rabotées par le vent.

Qualité de la neige :

Vendredi matin, pas de regel nocturne à basse altitude après une nuit douce et un peu de pluie sous 2100m. Dès le matin, on a une couche de neige humide en profondeur et qui va devenir encore plus lourde et humide en journée avec encore quelques pluies jusqu'à 2000/2100 m en tous versants.

Plus haut, on trouvera une fine couche de neige fraiche, souvent collante et compacte sous 2500 m, plus froide en altitude avec 5 à 10 cm de neige souvent travaillée par le vent en journée, restant alors poudreuse dans les combes abritées de haute montagne.

Aperçu météo pour le vendredi 06 mars

	nuit	matin	après-midi	soir
Ciel très nuageux et neige seulement en altitude avec un vent général de secteur sud-est.				
Pluie-Neige	2 100 m	1 900 m	2 000 m	
Iso 0 °C	2 500 m	2 200 m	2 300 m	2 200 m
Vent 2000 m	↑ 20 km/h	↖ 15 km/h	↖ 15 km/h	↖ 15 km/h
Vent 3000 m	↖ 35 km/h	↖ 25 km/h	↖ 25 km/h	↖ 25 km/h

Épaisseur de neige hors-piste

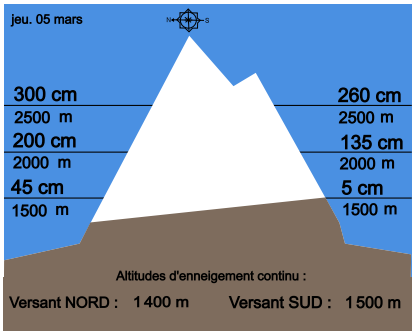

Précipitations à 1800 m

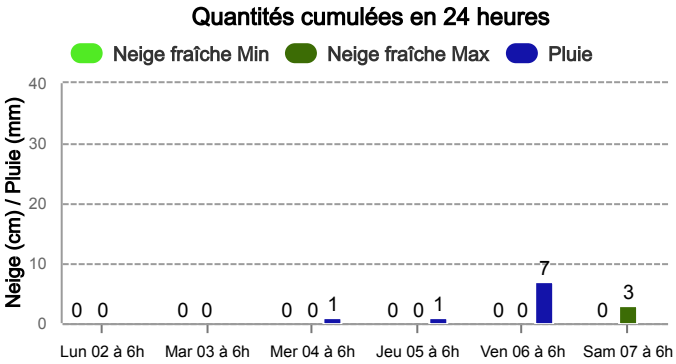

Tendance du samedi 07 mars

2

Indice de risque limité

Maintien d'un risque limité avec tout de même une amélioration des conditions météorologiques pour samedi

Pour consulter la vigilance en cours, veuillez vous rendre sur le site https://vigilance.meteofrance.fr/fr

Météo-France - 73 avenue de Paris, 94165 Saint-Mandé cedex - Contact : contact@meteo.fr

Rédigé par Météo-France avec la contribution des observateurs du réseau nivo-météorologiques. Partenariat : ANMSM (Maires de Stations de Montagne), DSF (Domaines Skiables de France), ADSP (Directeurs de Pistes et de la Sécurité des Stations de Sports d'Hiver) et autres acteurs de la montagne.

Bulletin neige & avalanches par téléphone au 0 892 68 10 20 Service 0,35 € / min + prix appel

RÉPUBLIQUE FRANÇAISE
Liberté Égalité Fraternité

METEO FRANCE
À VOS CÔTÉS, DANS UN CLIMAT QUI CHANGE

Bulletin d'estimation du risque d'avalanche
(valable en dehors des pistes balisées et ouvertes)

MASSIF : Couserans

Rédigé le jeudi 5 mars 2026 à 16h

Conditions nivo-météo des 7 derniers jours

	ven. 27/02				sam. 28/02				dim. 01/03				lun. 02/03				mar. 03/03				mer. 04/03				jeu. 05/03			
	03h	09h	15h	21h	03h	09h	15h	21h	03h	09h	15h	21h	03h	09h	15h	21h	03h	09h	15h	21h	03h	09h	15h	21h	03h	09h	15h	21h
Météo																												
Vent (km/h)	20	20	25	30	25	20	20	15	20	30	35	40	40	50	50	40	45	25	25	20	30	30	35	35	40	35	25	35
à 3000m																												
Vent (km/h)	15	15	15	20	10	10	15	5	10	15	20	30	35	40	35	30	40	20	15	15	20	15	20	25	30	25	15	15
à 2000m																												

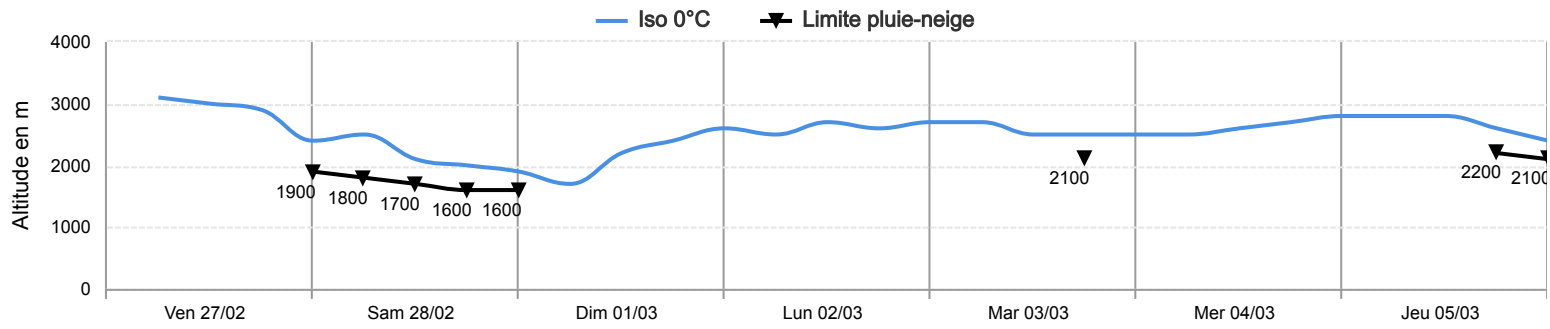

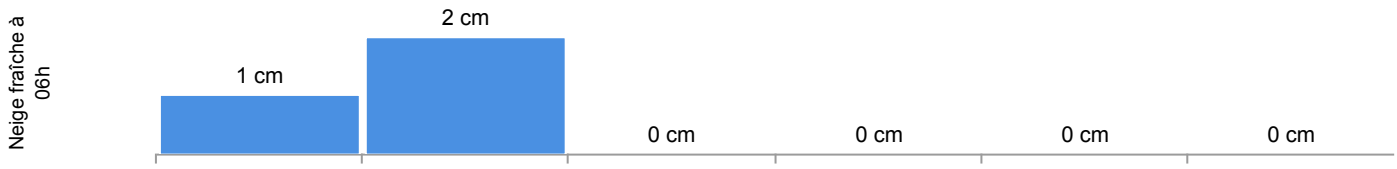

Risque d'avalanche	ven. 27/02	sam. 28/02	dim. 01/03	lun. 02/03	mar. 03/03	mer. 04/03	jeu. 05/03
	2	2	2	2	2	2	2

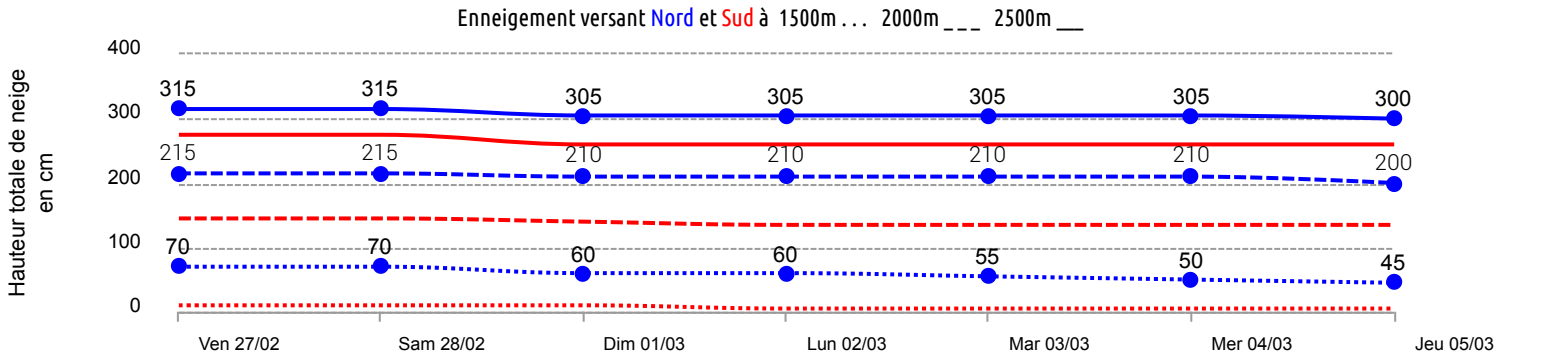

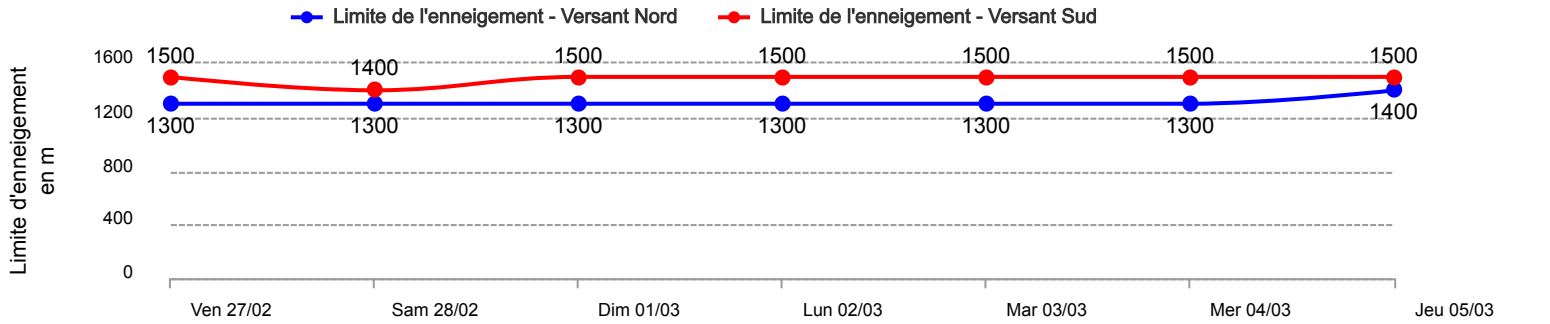

Pour consulter la vigilance en cours, veuillez vous rendre sur le site https://vigilance.meteofrance.fr/fr

Météo-France - 73 avenue de Paris, 94165 Saint-Mandé cedex - Contact : contact@meteo.fr

Rédigé par Météo-France avec la contribution des observateurs du réseau nivo-météorologiques. Partenariat : ANMSM (Maires de Stations de Montagne), DSF (Domaines Skiables de France), ADSP (Directeurs de Pistes et de la Sécurité des Stations de Sports d'Hiver) et autres acteurs de la montagne.

Bulletin neige & avalanches par téléphone au
0 892 68 10 20 Service 0,35 € / min + prix appel