RÉPUBLIQUE FRANÇAISE
Liberté Égalité Fraternité

METEO FRANCE
À VOS CÔTÉS, DANS UN CLIMAT QUI CHANGE

Bulletin d'estimation du risque d'avalanche
(valable en dehors des pistes balisées et ouvertes)

MASSIF : Devoluy

Rédigé le jeudi 5 mars 2026 à 16h

Estimation des risques pour le : VENDREDI 06 MARS

COUCHES FRAGILES DIFFICILES À SOLLICITER, POSSIBLE PLAQUE DE FOND

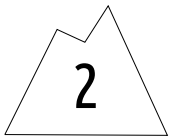

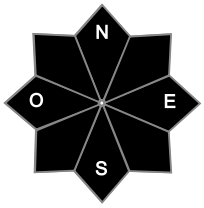

Indice de risque limité.

Départs spontanés : possible avalanche de fond.

Déclenchements provoqués : rares avalanches de plaque sur couche fragile persistante en versants nord.

Indices de risque : 5 très fort - 4 fort - 3 marqué - 2 limité - 1 faible -- En noir : les pentes les plus dangereuses

Stabilité du manteau neigeux

Situation avalancheuse typique : couche fragile persistante avalanches de fond

Déclenchements provoqués :
- une avalanche de plaque reste encore envisageable dans les versants de large nord au-dessus de 2000/2200 m. Même si leur déclenchement est généralement difficile, une couche fragile persistante insuffisamment enfouie à la base du manteau neigeux peut localement être sollicitée dans les secteurs peu enneigés, abords de croupes et bords des couloirs. Avalanche pouvant être de grande taille, avec cassure épaisse et propagation à distance.

Départs spontanés :
- une avalanche de fond emportant la totalité du manteau neigeux jusqu'au sol peut céder spontanément à n'importe quel moment du jour ou de la nuit sur terrain favorable (pentes herbeuses, dalles rocheuses), parfois précédée par l'ouverture d'une reptation (ou gueule de baleine). Avalanche de taille moyenne.
- les départs de neige humide semblent peu probables.

Qualité de la neige

L'enneigement est excédentaire. Les limites d'enneigement remontent dans les pentes bien exposées au soleil.

Limite d'enneigement skiable : 1200/1300 m en ubacs, 1500/1700 m en adrets pas trop raides.

État de la neige de surface : croute souvent peu portante le matin, s'humidifiant modérément au fil de la journée. En versants nord-est à nord-ouest au-dessus de 2200/2300 m, vieille poudreuse encore meuble, plus travaillée par le vent proche des crêtes.

Aperçu météo pour le vendredi 06 mars

	nuit	matin	après-midi	soir
	voile nuageux épais. Quelques flocons épars parfois possibles au dessus de 1800/2000 m			
Pluie-Neige				
Iso 0 °C	2 400 m	2 400 m	2 500 m	2 500 m
Vent 2000 m	25 km/h	20 km/h	20 km/h	15 km/h
Vent 3000 m	45 km/h	55 km/h	45 km/h	40 km/h

Épaisseur de neige hors-piste

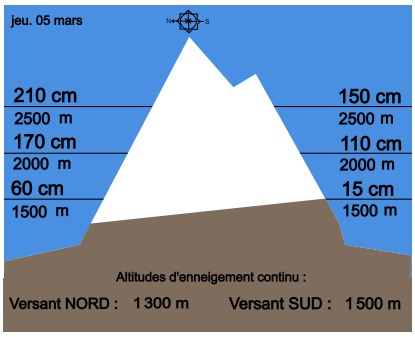

Précipitations à 1800 m

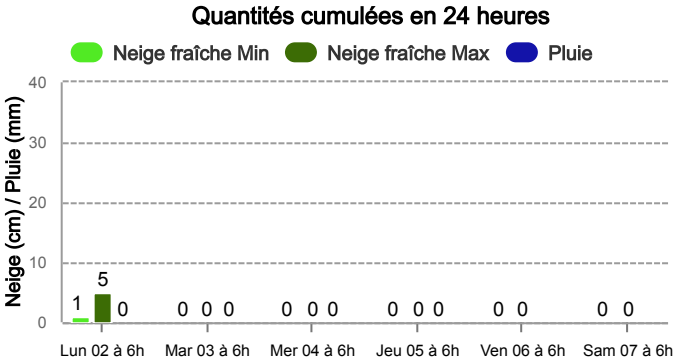

Tendance du samedi 07 mars

Indice de risque limité

risque restant limité avec peu dévolution des conditions nivologiques.

Pour consulter la vigilance en cours, veuillez vous rendre sur le site https://vigilance.meteofrance.fr/fr

Météo-France - 73 avenue de Paris, 94165 Saint-Mandé cedex - Contact : contact@meteo.fr

Rédigé par Météo-France avec la contribution des observateurs du réseau nivo-météorologiques. Partenariat : ANMSM (Maires de Stations de Montagne), DSF (Domaines Skiables de France), ADSP (Directeurs de Pistes et de la Sécurité des Stations de Sports d'Hiver) et autres acteurs de la montagne.

Bulletin neige & avalanches par téléphone au
0 892 68 10 20 Service 0,35 € / min + prix appel

RÉPUBLIQUE FRANÇAISE
Liberté Égalité Fraternité

METEO FRANCE
À VOS CÔTÉS, DANS UN CLIMAT QUI CHANGE

Bulletin d'estimation du risque d'avalanche

(valable en dehors des pistes balisées et ouvertes)

MASSIF : Devoluy

Rédigé le jeudi 5 mars 2026 à 16h

Conditions nivo-météo des 7 derniers jours

	ven. 27/02				sam. 28/02				dim. 01/03				lun. 02/03				mar. 03/03				mer. 04/03				jeu. 05/03			
	03h	09h	15h	21h	03h	09h	15h	21h	03h	09h	15h	21h	03h	09h	15h	21h	03h	09h	15h	21h	03h	09h	15h	21h	03h	09h	15h	21h
Météo																												
Vent (km/h)	10	10	15	20	30	30	25	20	15	20	25	20	20	30	30	25	20	10	10	5	5	0	5	15	15	25	20	25
à 3000m																												
Vent (km/h)	5	0	5	10	15	15	15	10	10	10	20	15	15	25	25	20	15	10	10	5	5	5	10	10	15	20	15	15
à 2000m																												

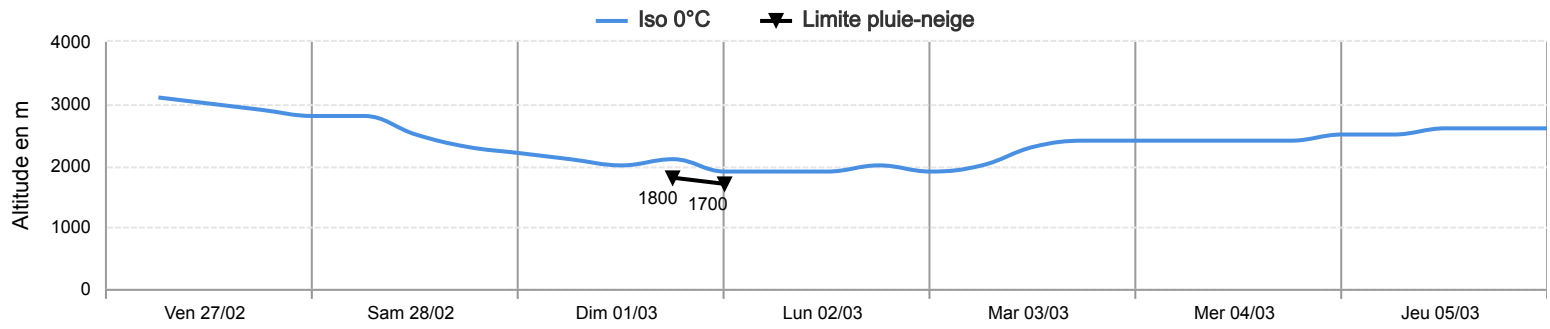

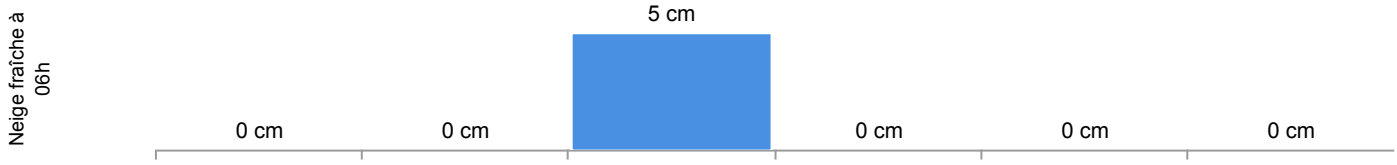

Risque d'avalanche	ven. 27/02	sam. 28/02	dim. 01/03	lun. 02/03	mar. 03/03	mer. 04/03	jeu. 05/03
	2	2	2	2	2	2	2

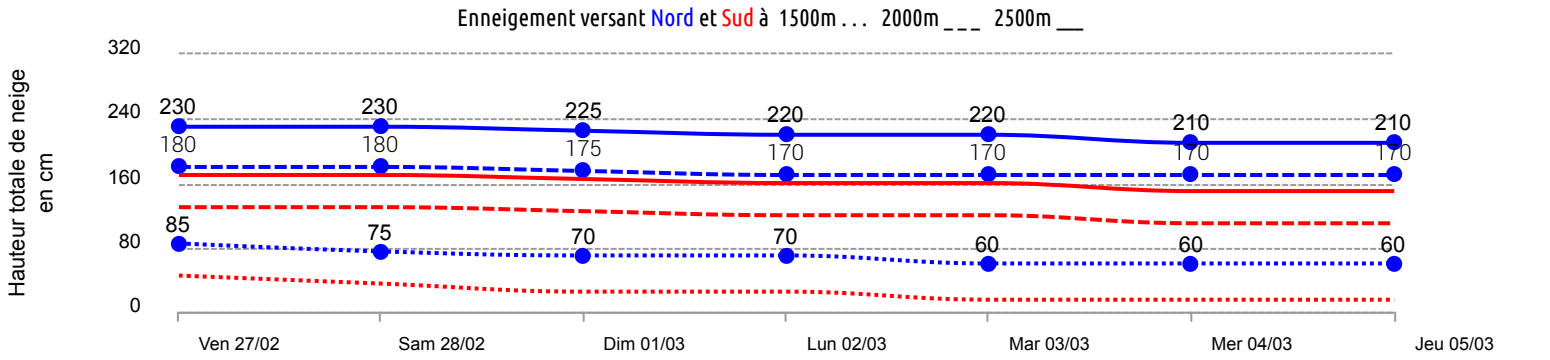

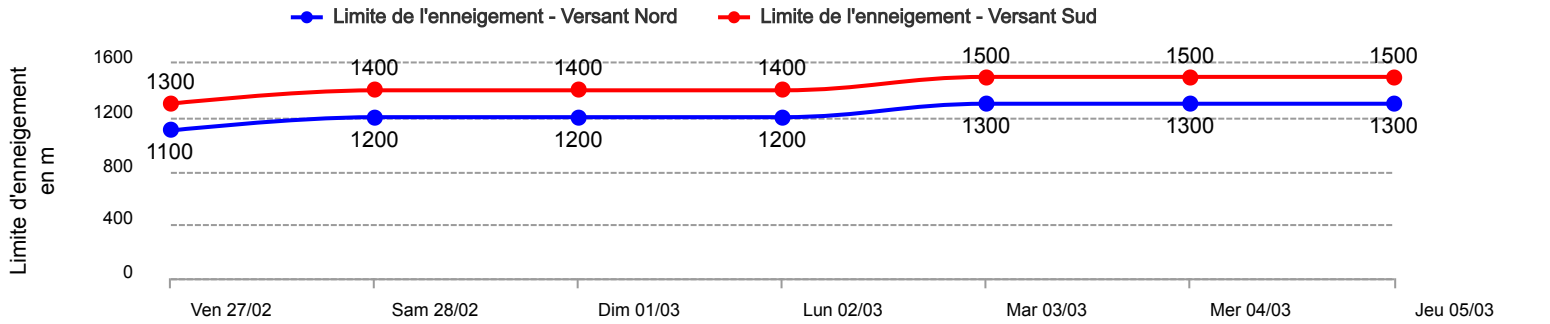

Pour consulter la vigilance en cours, veuillez vous rendre sur le site https://vigilance.meteofrance.fr/fr

Météo-France - 73 avenue de Paris, 94165 Saint-Mandé cedex - Contact : contact@meteo.fr

Rédigé par Météo-France avec la contribution des observateurs du réseau nivo-météorologiques. Partenariat : ANMSM (Maires de Stations de Montagne), DSF (Domaines Skiables de France), ADSP (Directeurs de Pistes et de la Sécurité des Stations de Sports d'Hiver) et autres acteurs de la montagne.

Bulletin neige & avalanches par téléphone au

0 892 68 10 20 Service 0,35 € / min + prix appel