Bulletin d'estimation du risque d'avalanche
(valable en dehors des pistes balisées et ouvertes)
MASSIF : Maurienne

Rédigé le jeudi 5 mars 2026 à 16h

Estimation des risques pour le : VENDREDI 06 MARS

MANTEAU PLUTÔT BIEN STABILISÉ, LES GRAINS ANGULEUX ENFOUIS SEMBLENT DÉSORMAIS TRÈS PEU RÉACTIFS.

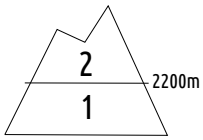

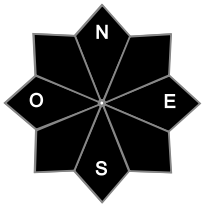

Au-dessus de 2200m indice de risque limité, plus bas indice faible.

Départs spontanés : rares avalanches de glissement.

Déclenchements provoqués : rares plaques sur couches fragiles persistantes.

Indices de risque : 5 très fort - 4 fort - 3 marqué - 2 limité - 1 faible -- En noir : les pentes les plus dangereuses

Stabilité du manteau neigeux

Situation avalancheuse typique : couche fragile persistante

Déclenchements provoqués : il subsiste de **rares instabilités liées à la présence de couches fragiles persistantes** (grains anguleux) enfouies dans le manteau. Ces instabilités sont présentes en **tous versants** :
(1) **dès 2200 m en nord** (neige froide en surface) où il convient de se méfier des zones les moins enneigées (abords de crête, croupes dégarnis) car la couche fragile est alors plus proche de la surface.
(2) **plutôt au-dessus de 2500/2600 m en versants ensoleillés** (neige humide en surface) où, après plusieurs heures de soleil, l'enfoncement dans la neige humide rend à nouveau possible la sollicitation d'une couche fragile enfouie.
Quel que soit l'aspect de la plaque en surface, des avalanches d'ampleur peuvent alors être déclenchées : généralement des **tailles moyennes**, exceptionnellement une grande.

Départs spontanés : rares **avalanches de glissement** (plaques de fond), plutôt **sous 2400 m** mais parfois plus haut sur des terrains très propices (dalles rocheuses raides notamment). Avalanches **petites** à **moyennes**.

Qualité de la neige

Enneigement : fonte rapide de la neige en sud et aux basses altitudes sous les assauts du soleil, de la douceur puis désormais du foehn. Ailleurs, malgré le tassement, l'enneigement reste très bon pour la saison.

Limite skiable : encore skiable dès 1100 m dans les prairies orientées nord, plutôt 1500/1600 m en sud pas trop raide.

Qualité de la neige : mauvais regel sous 1800/2000 m avec potentiellement une fine croute désagréable sous cette altitude. Au-dessus,
- en nord, neige encore froide, poudreuse dense à l'abri du vent, cartonnée voire dure dans les secteurs ventés (à l'approche des crêtes).
- en sud/est/ouest, neige dure qui ramollit très difficilement en journée (voile dense).

Aperçu météo pour le vendredi 06 mars

	nuit	matin	après-midi	soir

Ciel fortement voilé et chargé en poussières désertiques venues du Sahara. La visibilité est très mauvaise. Foehn modéré dans les secteurs exposés.

Pluie-Neige				
Iso 0 °C	2 600 m	2 600 m	2 600 m	2 600 m
Vent 2000 m	↑ 40 km/h	↖ 40 km/h	↖ 30 km/h	↖ 20 km/h
Vent 3000 m	↖ 35 km/h	↖ 35 km/h	↖ 35 km/h	↖ 30 km/h

Épaisseur de neige hors-piste

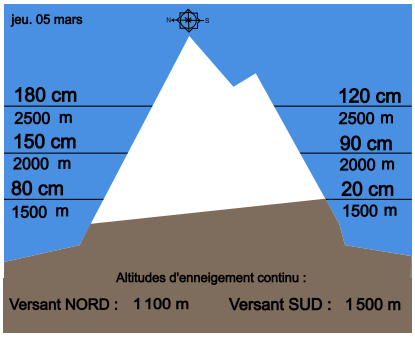

Précipitations à 1800 m

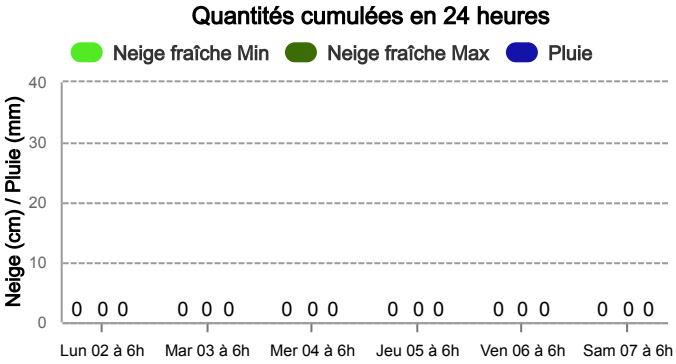

Tendance du samedi 07 mars

Indice de risque limité

Peu d'évolution. Le ciel est dégagé en journée, ce qui devrait permettre une humidification à nouveau efficace dans les versants ensoleillés. Le risque reste limité à cause des couches fragiles persistantes.

Pour consulter la vigilance en cours, veuillez vous rendre sur le site https://vigilance.meteofrance.fr/fr

Météo-France - 73 avenue de Paris, 94165 Saint-Mandé cedex - Contact : contact@meteo.fr

Rédigé par Météo-France avec la contribution des observateurs du réseau nivo-météorologiques. Partenariat : ANMSM (Maires de Stations de Montagne), DSF (Domaines Skiables de France), ADSP (Directeurs de Pistes et de la Sécurité des Stations de Sports d'Hiver) et autres acteurs de la montagne.

Bulletin neige & avalanches par téléphone au **0 892 68 10 20** Service 0,35 € / min + prix appel

RÉPUBLIQUE FRANÇAISE
Liberté Égalité Fraternité

METEO FRANCE
À VOS CÔTÉS, DANS UN CLIMAT QUI CHANGE

Bulletin d'estimation du risque d'avalanche
(valable en dehors des pistes balisées et ouvertes)
MASSIF : Maurienne

Rédigé le jeudi 5 mars 2026 à 16h

Conditions nivo-météo des 7 derniers jours

	ven. 27/02				sam. 28/02				dim. 01/03				lun. 02/03				mar. 03/03				mer. 04/03				jeu. 05/03			
	03h	09h	15h	21h	03h	09h	15h	21h	03h	09h	15h	21h	03h	09h	15h	21h	03h	09h	15h	21h	03h	09h	15h	21h	03h	09h	15h	21h
Météo																												
Vent (km/h)	10	10	10	10	10	15	15	10	10	15	15	15	20	25	25	20	15	15	15	15	10	10	10	10	20	25	25	30
à 3000m																												
Vent (km/h)	5	5	5	5	5	5	10	5	5	5	10	10	15	20	20	15	10	5	5	5	5	5	5	5	20	25	25	30
à 2000m																												

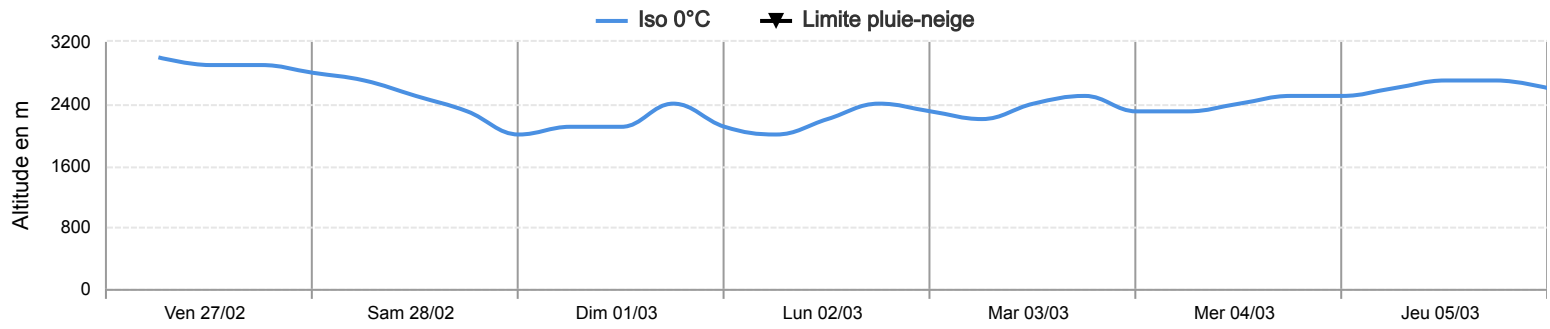

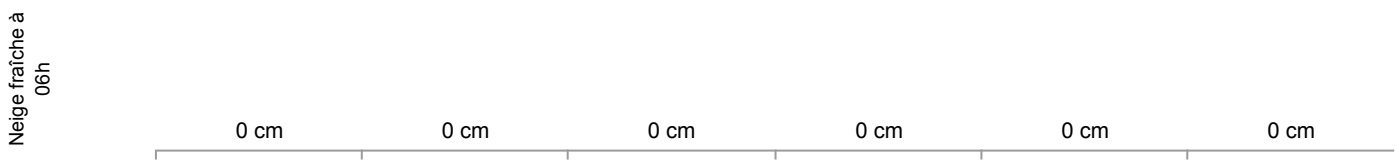

Risque d'avalanche	ven. 27/02	sam. 28/02	dim. 01/03	lun. 02/03	mar. 03/03	mer. 04/03	jeu. 05/03
	3	2	2	2	2	2	2

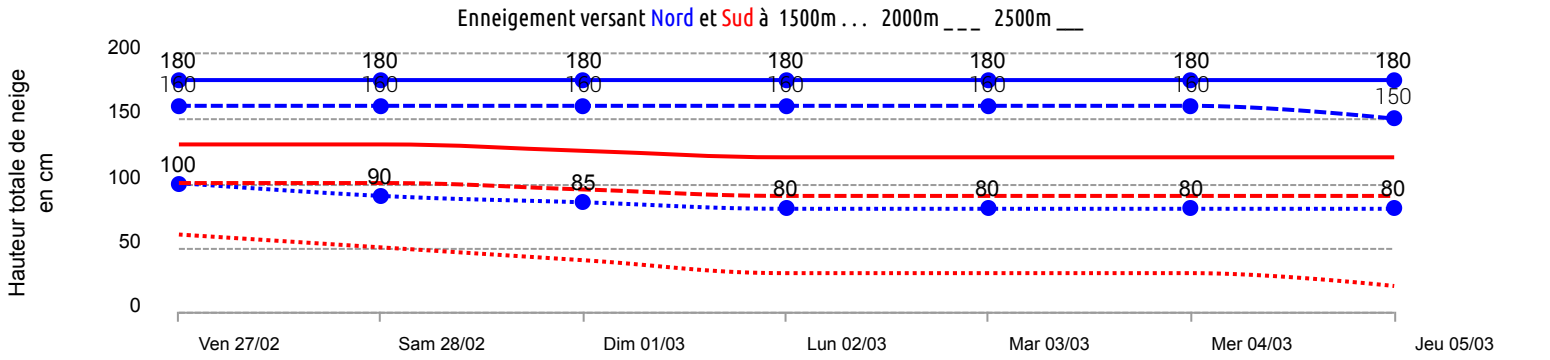

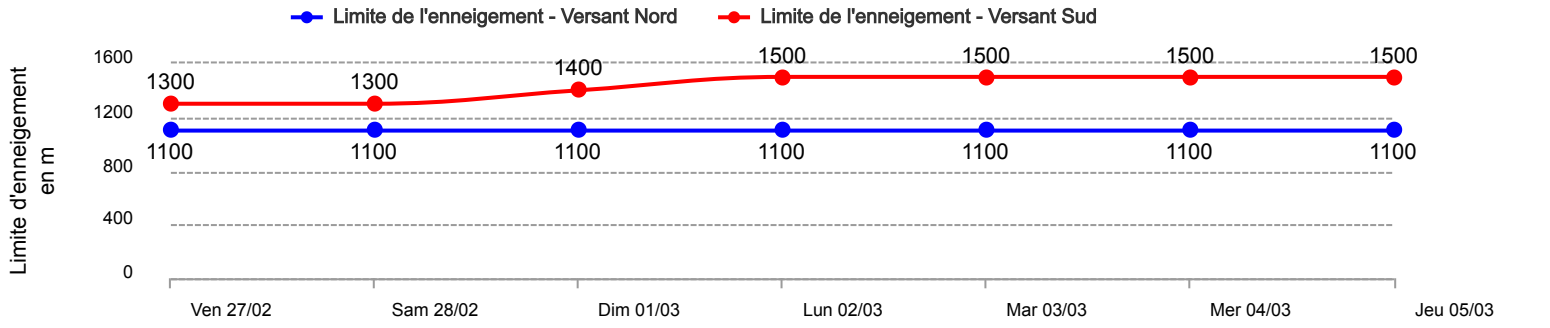

Pour consulter la vigilance en cours, veuillez vous rendre sur le site https://vigilance.meteofrance.fr/fr

Météo-France - 73 avenue de Paris, 94165 Saint-Mandé cedex - Contact : contact@meteo.fr

Rédigé par Météo-France avec la contribution des observateurs du réseau nivo-météorologiques. Partenariat : ANMSM (Maires de Stations de Montagne), DSF (Domaines Skiables de France), ADSP (Directeurs de Pistes et de la Sécurité des Stations de Sports d'Hiver) et autres acteurs de la montagne.

Bulletin neige & avalanches par téléphone au
0 892 68 10 20 Service 0,35 € / min + prix appel