Bulletin d'estimation du risque d'avalanche
(valable en dehors des pistes balisées et ouvertes)

MASSIF : Renoso Incudine

Rédigé le jeudi 5 mars 2026 à 16h

Estimation des risques pour le : VENDREDI 06 MARS

CONDITIONS PRINTANIÈRES EN VERSANTS ENSOLEILLÉS.

2

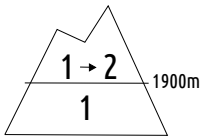

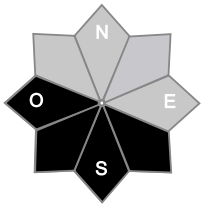

Au-dessus de 1900m indice de risque faible évoluant en limité, plus bas indice faible.

Départs spontanés : Nombreux départs en neige humides dans les versants ensoleillés.

Déclenchements provoqués : Départs ponctuels sous les skis (ou raquettes) en neige humide.

Indices de risque : 5 très fort - 4 fort - 3 marqué - 2 limité - 1 faible -- En noir : les pentes les plus dangereuses

Stabilité du manteau neigeux

Situation avalancheuse typique : neige humide

Départs spontanés : Malgré un regel quasi inexistant la neige est dure ou dense en fin de nuit puis l'humidification reprend rapidement en matinée. Elle devrait être accélérée en versants Sud et en versants occidentaux par la faible couverture nuageuse et un effet de Foehn radoucissant les températures. Au-dessus de 1900m, quelques départs spontanés d'avalanches de taille petite à moyenne (taille 1 à 2) de neige humide restent possibles dans les pentes raides encore chargées et ensoleillées. Une avalanche de fond de taille 2 (moyenne) sur les dalles rocheuses emportant la totalité du manteau neigeux en place reste possible.

Déclenchements provoqués :Peu probables, ou alors une coulée humide sous les skis aux heures chaudes.

Qualité de la neige

Qualification de l'enneigement : L'enneigement est excellent pour la saison au-dessus de 1600 m. Au Val d'Ese, on relève encore près d'1 mètre de neige à la station. À Ghisoni Capanelle, 1m70 mètres au-dessus de 1800 m et un peu moins de 3 mètres dans les combes abritées.

Limite d'enneigement skiable : autour de 1500 m.

État de la neige :Sous l'effet de plus d'une semaine de soleil et de douceur, le manteau neigeux s'est considérablement tassé et il est bien consolidé malgré un regel nocturne quasi inexistant et ne concernant souvent que les pentes nord et les hauts sommets. En journée, reprise de l'humidification au soleil avec une neige devenant lourde et humide (parfois pourrie) à basse altitude. En Nord, sous 2000 m, la surface du manteau neigeux ramollit lentement en cours de journée. Au-dessus de 2000/2200 m, neige restant dure/cartonnée surtout en approchant des sommets. Nombreuses zones de neige colorée avec les dernières remontée de sable.
À noter la présence de corniches parfois volumineuses.

Aperçu météo pour le vendredi 06 mars

	nuit	matin	après-midi	soir
Pluie-Neige	2 000 m	2 000 m	2 000 m	1 900 m
Iso 0 °C	2 500 m	2 400 m	2 500 m	2 400 m
Vent 1500 m	← 50 km/h	← 40 km/h	← 40 km/h	← 40 km/h
Vent 2000 m	↖ 70 km/h	← 70 km/h	← 60 km/h	↖ 50 km/h

Épaisseur de neige hors-piste

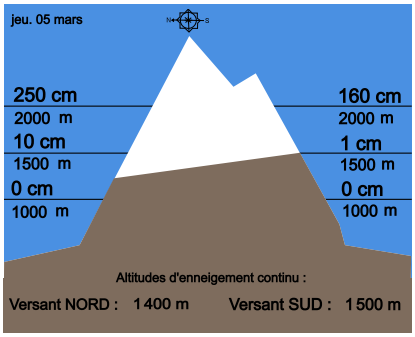

Précipitations à 1800 m

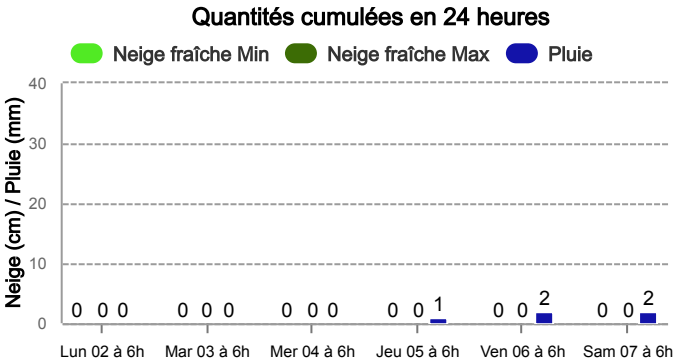

Tendance du samedi 07 mars

2

Indice de risque limité

Persistance du risque d'avalanches de neige humide.

Pour consulter la vigilance en cours, veuillez vous rendre sur le site https://vigilance.meteofrance.fr/fr

Météo-France - 73 avenue de Paris, 94165 Saint-Mandé cedex - Contact : contact@meteo.fr

Rédigé par Météo-France avec la contribution des observateurs du réseau nivo-météorologiques. Partenariat : ANMSM (Maires de Stations de Montagne), DSF (Domaines Skiables de France), ADSP (Directeurs de Pistes et de la Sécurité des Stations de Sports d'Hiver) et autres acteurs de la montagne.

Bulletin neige & avalanches par téléphone au
0 892 68 10 20 Service 0,35 € / min + prix appel

RÉPUBLIQUE FRANÇAISE
Liberté Égalité Fraternité

METEO FRANCE
À VOS CÔTÉS, DANS UN CLIMAT QUI CHANGE

Bulletin d'estimation du risque d'avalanche

(valable en dehors des pistes balisées et ouvertes)

MASSIF : Renoso Incudine

Rédigé le jeudi 5 mars 2026 à 16h

Conditions nivo-météo des 7 derniers jours

	ven. 27/02				sam. 28/02				dim. 01/03				lun. 02/03				mar. 03/03				mer. 04/03				jeu. 05/03			
	03h	09h	15h	21h	03h	09h	15h	21h	03h	09h	15h	21h	03h	09h	15h	21h	03h	09h	15h	21h	03h	09h	15h	21h	03h	09h	15h	21h
Météo																												
Vent (km/h)	15	15	15	10	10	10	10	10	5	10	10	10	15	30	15	15	10	5	5	10	10	5	5	0	20	30	60	70
à 2000m	↗	↗	→	↘	↘	→	↘	↘	↗	→	→	↗	↗	↗	↗	↑	↗	↖	↖	↑	↗	↑	↖	→	↗	↑	↖	↖
Vent (km/h)	10	10	10	5	5	10	10	10	5	10	15	10	10	20	20	15	20	30	30	25	25	20	20	15	25	40	40	40
à 1500m	→	↗	→	↘	↑	↖	↗	↗	↑	↖	↑	←	↑	↗	↑	←	←	←	←	←	←	←	←	←	←	←	←	←

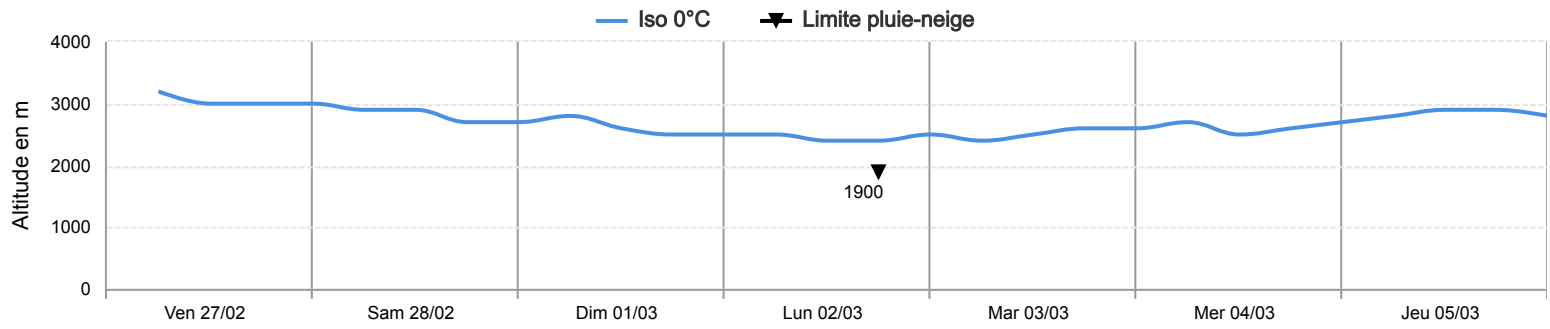

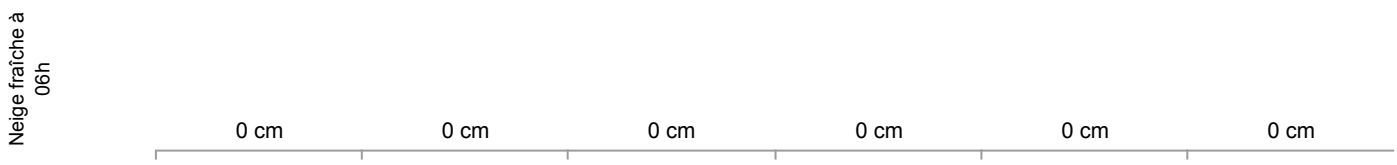

Risque d'avalanche	ven. 27/02	sam. 28/02	dim. 01/03	lun. 02/03	mar. 03/03	mer. 04/03	jeu. 05/03
	2	2	2	2	2	2	2

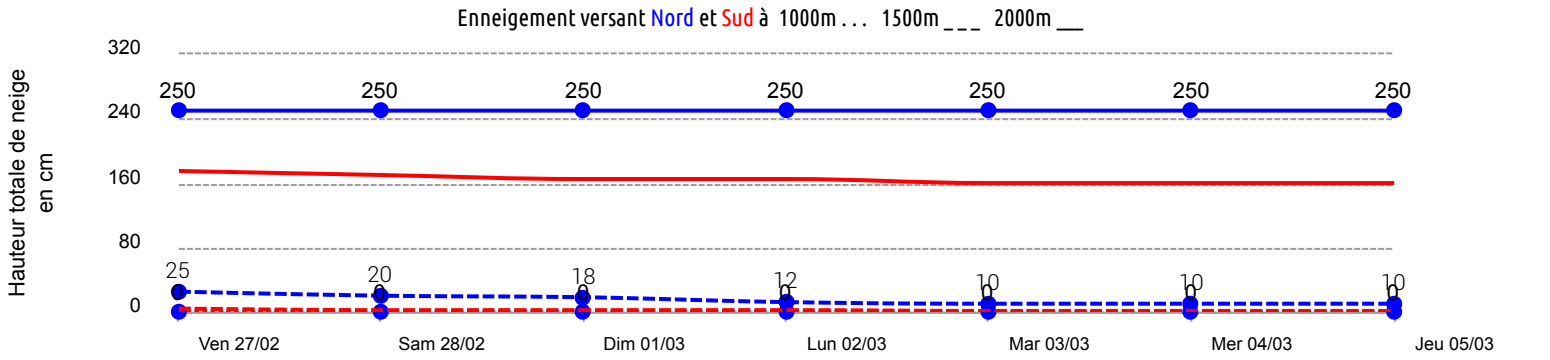

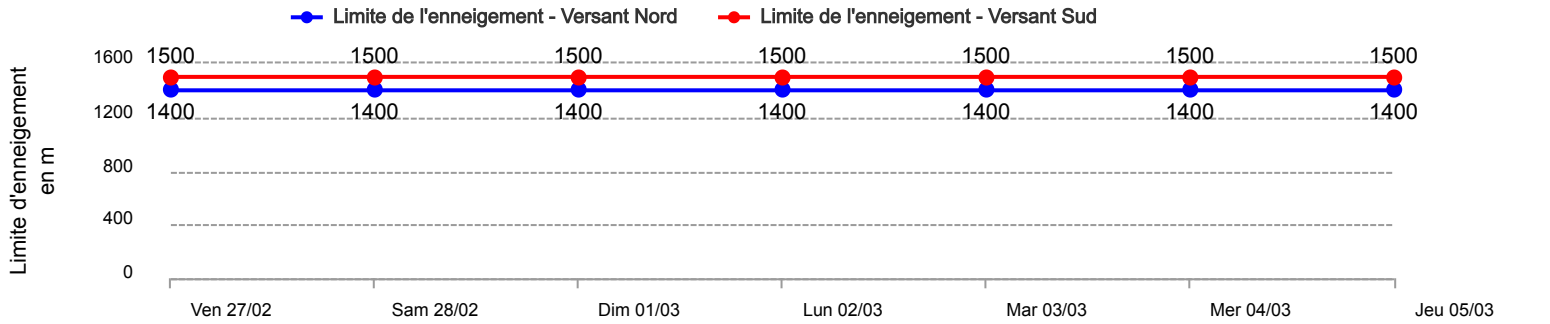

Pour consulter la vigilance en cours, veuillez vous rendre sur le site https://vigilance.meteofrance.fr/fr

Météo-France - 73 avenue de Paris, 94165 Saint-Mandé cedex - Contact : contact@meteo.fr

Bulletin neige & avalanches par téléphone au

0 892 68 10 20 Service 0,35 € / min + prix appel

Rédigé par Météo-France avec la contribution des observateurs du réseau nivo-météorologiques. Partenariat : ANMSM (Maires de Stations de Montagne), DSF (Domaines Skiables de France), ADSP (Directeurs de Pistes et de la Sécurité des Stations de Sports d'Hiver) et autres acteurs de la montagne.