Bulletin d'estimation du risque d'avalanche
(valable en dehors des pistes balisées et ouvertes)

MASSIF : Vercors

Rédigé le jeudi 5 mars 2026 à 16h

Estimation des risques pour le : VENDREDI 06 MARS

ACTIVITE POSSIBLE EN VERSANTS SUD, QUELQUES COULEES HUMIDES OU PLAQUES DE FONDS

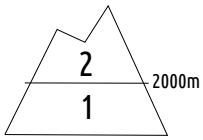

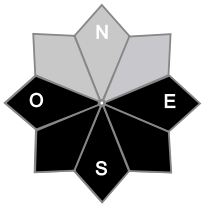

versants ensoleillés

Au-dessus de 2000m indice de risque limité, plus bas indice faible.

Départs spontanés : Encore quelques plaques de fonds ou coulées humides possibles en large secteur Sud.

Déclenchements provoqués : Départs ponctuels de petite taille en neige humide.

Indices de risque : 5 très fort - 4 fort - 3 marqué - 2 limité - 1 faible -- En noir : les pentes les plus dangereuses

Stabilité du manteau neigeux

Situation avalancheuse typique : neige humide avalanches de fond

Le temps reste stable et très doux pour la saison, ainsi le manteau neigeux s'est considérablement tassé et stabilisé.
Départs spontanés : A toute heure de la journée ou de la nuit et principalement en large secteur Sud, possible avalanche de fond en pente raide herbeuse ou sur les dalles rocheuses, de tailles moyennes. Avalanches parfois précédées par l'ouverture d'une fissure / gueule de baleine. Aux heures chaudes et toujours en large Sud, possibles coulées humides en pente raide, surtout sous les rochers.
Déclenchements provoqués : Peu probables, ou alors une coulée humide sous les skis aux heures chaudes.

Qualité de la neige

Qualification de l'enneigement : L'enneigement régresse en partie basse, mais il est toujours bon pour la saison dès 1400 m, voire très bon au dessus de 1600 m environ, notamment dans les combes d'altitude. On trouve des crêtes un peu dégarnies par le vent, ou au contraire des corniches assez conséquentes.

Limites skiables : vers 1300/1700 m.

Qualité de la neige vendredi : Manteau neigeux de type printanier avec une neige légèrement croûtée, mauvais regel dans l'ensemble, s'humidifiant en journée, parfois profondément selon l'orientation. Encore très localement un peu de neige froide en versants Nord.

Aperçu météo pour le vendredi 06 mars

nuit	matin	après-midi	soir

Encore une belle journée douce et ensoleillée. Sensation nuageuse amplifiée due à la présence de sable dans l'atmosphère.

Pluie-Neige				
Iso 0 °C	2 600 m	2 500 m	2 400 m	2 500 m
Vent 1500 m	← 15 km/h	↖ 5 km/h	↖ 10 km/h	↖ 5 km/h
Vent 2000 m	↖ 25 km/h	↖ 20 km/h	↖ 20 km/h	↖ 15 km/h

Épaisseur de neige hors-piste

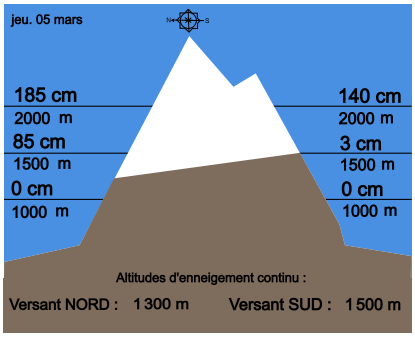

Précipitations à 1800 m

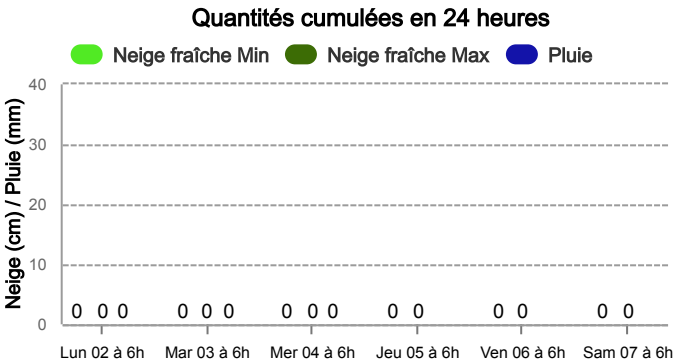

Tendance du samedi 07 mars

Indice de risque limité

Risque qui se stabilise avec la poursuite de conditions anticycloniques sans enjeux.

Pour consulter la vigilance en cours, veuillez vous rendre sur le site https://vigilance.meteofrance.fr/fr

Météo-France - 73 avenue de Paris, 94165 Saint-Mandé cedex - Contact : contact@meteo.fr

Rédigé par Météo-France avec la contribution des observateurs du réseau nivo-météorologiques. Partenariat : ANMSM (Maires de Stations de Montagne), DSF (Domaines Skiables de France), ADSP (Directeurs de Pistes et de la Sécurité des Stations de Sports d'Hiver) et autres acteurs de la montagne.

Bulletin neige & avalanches par téléphone au
0 892 68 10 20 Service 0,35 € / min + prix appel

RÉPUBLIQUE FRANÇAISE
Liberté Égalité Fraternité

METEO FRANCE
À VOS CÔTÉS, DANS UN CLIMAT QUI CHANGE

Bulletin d'estimation du risque d'avalanche

(valable en dehors des pistes balisées et ouvertes)

MASSIF : Vercors

Rédigé le jeudi 5 mars 2026 à 16h

Conditions nivo-météo des 7 derniers jours

	ven. 27/02				sam. 28/02				dim. 01/03				lun. 02/03				mar. 03/03				mer. 04/03				jeu. 05/03			
	03h	09h	15h	21h	03h	09h	15h	21h	03h	09h	15h	21h	03h	09h	15h	21h	03h	09h	15h	21h	03h	09h	15h	21h	03h	09h	15h	21h
Météo																												
Vent (km/h)	5	0	10	15	20	15	25	25	30	35	35	45	55	55	50	45	25	15	15	5	10	15	15	10	15	25	20	15
à 2000m																												
Vent (km/h)	5	5	10	10	20	15	15	15	25	25	25	40	50	45	35	20	20	15	15	5	10	10	15	10	10	15	10	10
à 1500m																												

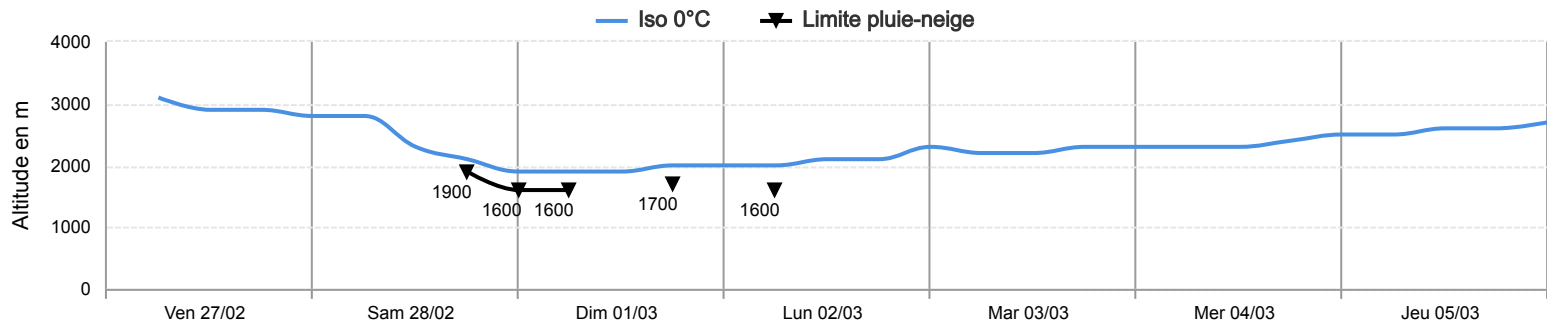

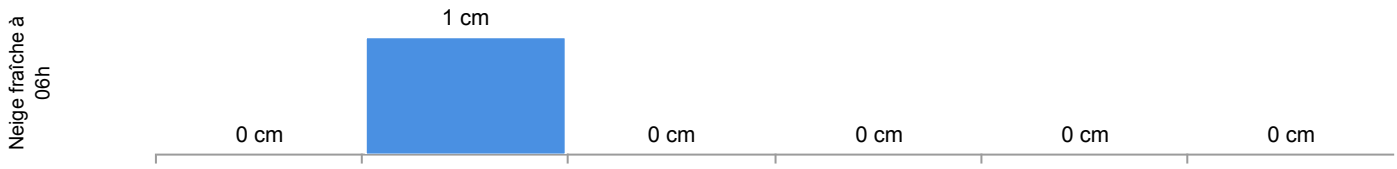

Risque d'avalanche	ven. 27/02	sam. 28/02	dim. 01/03	lun. 02/03	mar. 03/03	mer. 04/03	jeu. 05/03
	2	2	1	2	2	2	2

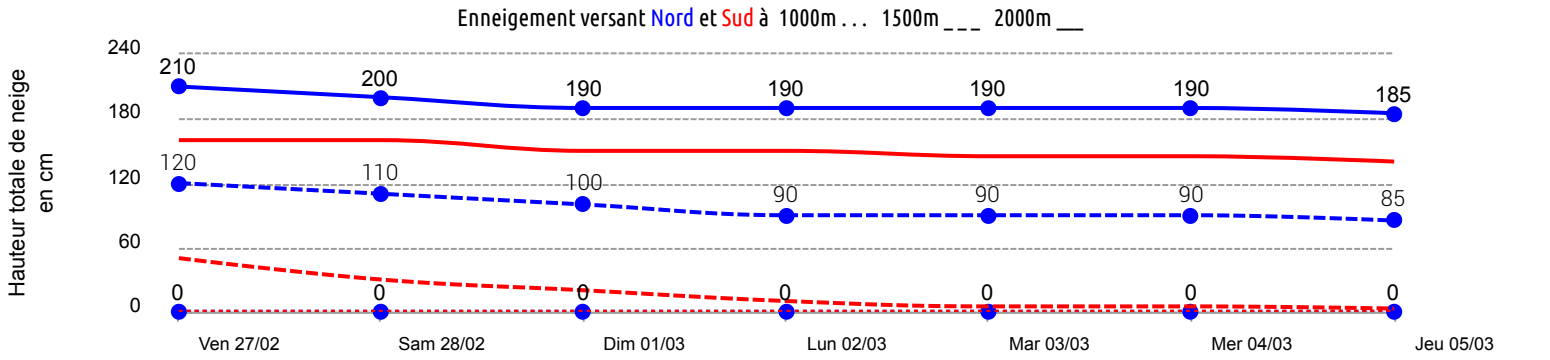

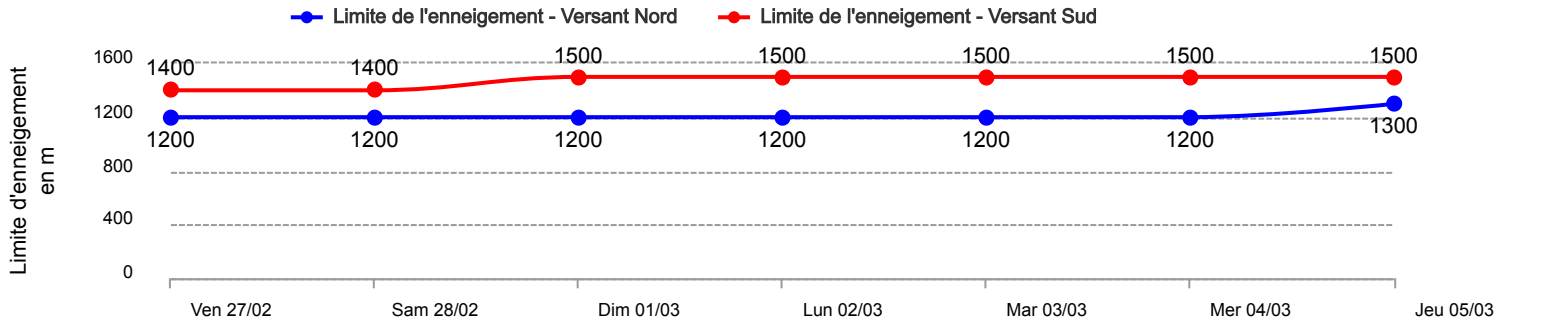

Pour consulter la vigilance en cours, veuillez vous rendre sur le site https://vigilance.meteofrance.fr/fr

Météo-France - 73 avenue de Paris, 94165 Saint-Mandé cedex - Contact : contact@meteo.fr

Rédigé par Météo-France avec la contribution des observateurs du réseau nivo-météorologiques. Partenariat : ANMSM (Maires de Stations de Montagne), DSF (Domaines Skiables de France), ADSP (Directeurs de Pistes et de la Sécurité des Stations de Sports d'Hiver) et autres acteurs de la montagne.

Bulletin neige & avalanches par téléphone au
0 892 68 10 20 Service 0,35 € / min + prix appel