RÉPUBLIQUE FRANÇAISE
Liberté Égalité Fraternité

METEO FRANCE
À VOS CÔTÉS, DANS UN CLIMAT QUI CHANGE

Bulletin d'estimation du risque d'avalanche
(valable en dehors des pistes balisées et ouvertes)
MASSIF : Capcir Puymorens

Rédigé le jeudi 5 mars 2026 à 17h

Estimation des risques pour le : VENDREDI 06 MARS

CUMULS DE PLUIES CONSÉQUENTS SOUS 2100M ET NOUVELLES INSTABILITÉS EN ALTITUDE

3

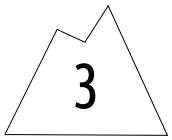

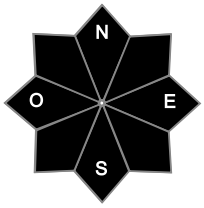

Indice de risque marqué.

Départs spontanés : Avalanche de neige humide sous 2100m, possibles départs dans la neige fraiche en altitude

Déclenchements provoqués : Manteau neigeux instable après des chutes conséquentes en altitude

Indices de risque : 5 très fort - 4 fort - 3 marqué - 2 limité - 1 faible -- En noir : les pentes les plus dangereuses

Stabilité du manteau neigeux

Situation avalancheuse typique : neige fraîche neige humide

Déclenchements provoqués :
Épisode de neige contrasté d'Ouest en Est avec des cumuls au-dessus de 2200/2300 m de 30/60 cm du Capcir au Madres, 10/30 cm côté Puymorens.
Au-dessus de 2200/2300 m, avalanches de plaques possibles en tous versants et déclenchables au passage d'un skieur emportant l'ensemble des chutes de neige. En effet, de nouvelles structures de plaques, plutôt d'aspect friables à l'abri du vent, se forment au fil de la journée et des chutes de neige qui pourraient être conséquentes. Un déclenchement peut alors entraîner l'ensemble des chutes de neige avec des avalanches plus volumineuses vers l'Est du massif là où les cumuls sont attendus les plus importants.
Observables: quantités de neige fraiche, fissures sous les skis, avalanche dans la neige récente en pente raide.

Départs spontanés :
- Avalanches de neige humide attendues sous 2100 m, moyenne à grande. Les pluies localement conséquentes (Capcir/Madres) remontant jusqu'à 2100 m à partir de ce soir et demain peuvent favoriser les départs avec une humidification encore plus en profondeur et notamment dans les pentes raides de secteur Nord-Est où les quantités de neige sont conséquentes. De plus, il est reporté dans de nombreuses orientations de larges fissures : le nouvel apport d'eau liquide, pourrait ainsi favoriser le départ d'épaisses avalanches de fond.
- Avalanches de neige sèche possibles en altitude au fil des chutes de neige, dans les pentes raides d'un large secteur Ouest à Nord. Ces avalanches pourront alors emporter l'ensemble des chutes de neige en cours.

Qualité de la neige

Enneigement :
L'enneigement est encore légèrement excédentaire dès la moyenne montagne après les nombreuses perturbations neigeuses depuis le début de l'année. Les vallons ombragés sont encore bien enneigés avec des quantités de neige importantes dès 1400 m notamment en versant Est et nord.
La limite skiable remonte autour de 1500 à 1600m plein Sud alors que certaines vallées ombragées sont encore enneigées dès 1200 à 1300m. A haute altitude, les pentes Ouest ont souvent été rabotées par le vent.

Qualité de la neige :
Vendredi matin, la neige est humide dès le matin sous 2100m avec les récentes pluies. En journée, elle s'humidifie encore plus profondément avec une neige lourde et très humide en tous versants. Plus haut, au-dessus de 2300/2400 m, on trouvera une couche de neige fraiche déjà importante le matin (localement 10/20 cm) augmentant au fil de la journée (30/60 cm). La couverture sera parfois hétérogène avec le transport de neige par le vent en journée et surtout entre les parties Est et Ouest du massif.

Aperçu météo pour le vendredi 06 mars

	nuit	matin	après-midi	soir
Précipitations conséquentes et contrastées d'Ouest en Est avec du vent de secteur Est modéré et une limite pluie neige autour de 2000m.				
Pluie-Neige	2 100 m	2 000 m	1 900 m	2 100 m
Iso 0 °C	2 400 m	2 300 m	2 300 m	2 200 m
Vent 2000 m	← 25 km/h	← 35 km/h	← 35 km/h	↖ 30 km/h
Vent 3000 m	↖ 45 km/h	← 50 km/h	← 55 km/h	↖ 40 km/h

Pour consulter la vigilance en cours, veuillez vous rendre sur le site https://vigilance.meteofrance.fr/fr

Météo-France - 73 avenue de Paris, 94165 Saint-Mandé cedex - Contact : contact@meteo.fr

Rédigé par Météo-France avec la contribution des observateurs du réseau nivo-météorologiques. Partenariat : ANMSM (Maires de Stations de Montagne), DSF (Domaines Skiables de France), ADSP (Directeurs de Pistes et de la Sécurité des Stations de Sports d'Hiver) et autres acteurs de la montagne.

Bulletin neige & avalanches par téléphone au
0 892 68 10 20 Service 0,35 € / min + prix appel

Bulletin d'estimation du risque d'avalanche

(valable en dehors des pistes balisées et ouvertes)

MASSIF : Capcir Puymorens

Rédigé le jeudi 5 mars 2026 à 17h

Épaisseur de neige hors-piste

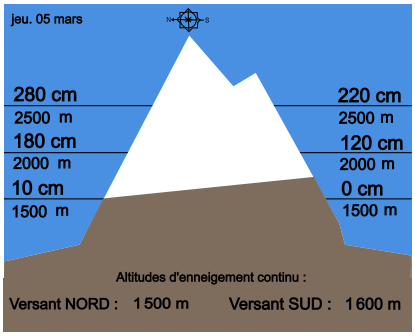

Précipitations à 1800 m

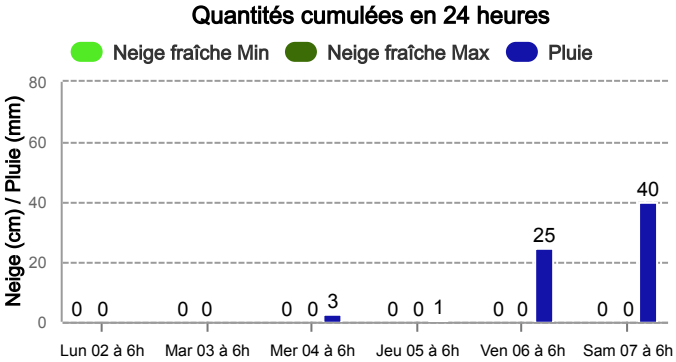

Tendance du samedi 07 mars

Indice de risque marqué

Stationnaire malgré une stabilisation progressive à venir dans la neige fraiche.

Pour consulter la vigilance en cours, veuillez vous rendre sur le site https://vigilance.meteofrance.fr/fr

Météo-France - 73 avenue de Paris, 94165 Saint-Mandé cedex - Contact : contact@meteo.fr

Rédigé par Météo-France avec la contribution des observateurs du réseau nivo-météorologiques. Partenariat : ANMSM (Maires de Stations de Montagne), DSF (Domaines Skiables de France), ADSP (Directeurs de Pistes et de la Sécurité des Stations de Sports d'Hiver) et autres acteurs de la montagne.

Bulletin neige & avalanches par téléphone au

0 892 68 10 20 Service 0,35 € / min + prix appel

RÉPUBLIQUE FRANÇAISE
Liberté Égalité Fraternité

METEO FRANCE
À VOS CÔTÉS, DANS UN CLIMAT QUI CHANGE

Bulletin d'estimation du risque d'avalanche

(valable en dehors des pistes balisées et ouvertes)

MASSIF : Capcir Puymorens

Rédigé le jeudi 5 mars 2026 à 17h

Conditions nivo-météo des 7 derniers jours

	ven. 27/02				sam. 28/02				dim. 01/03				lun. 02/03				mar. 03/03				mer. 04/03				jeu. 05/03			
	03h	09h	15h	21h	03h	09h	15h	21h	03h	09h	15h	21h	03h	09h	15h	21h	03h	09h	15h	21h	03h	09h	15h	21h	03h	09h	15h	21h
Météo																												
Vent (km/h)	20	20	25	30	20	20	20	20	20	20	25	20	30	45	45	35	35	25	20	15	25	20	35	30	35	35	40	40
à 3000m																												
Vent (km/h)	15	15	15	20	10	10	15	10	10	15	20	15	20	30	35	25	25	20	20	10	15	15	25	20	20	25	30	25
à 2000m																												

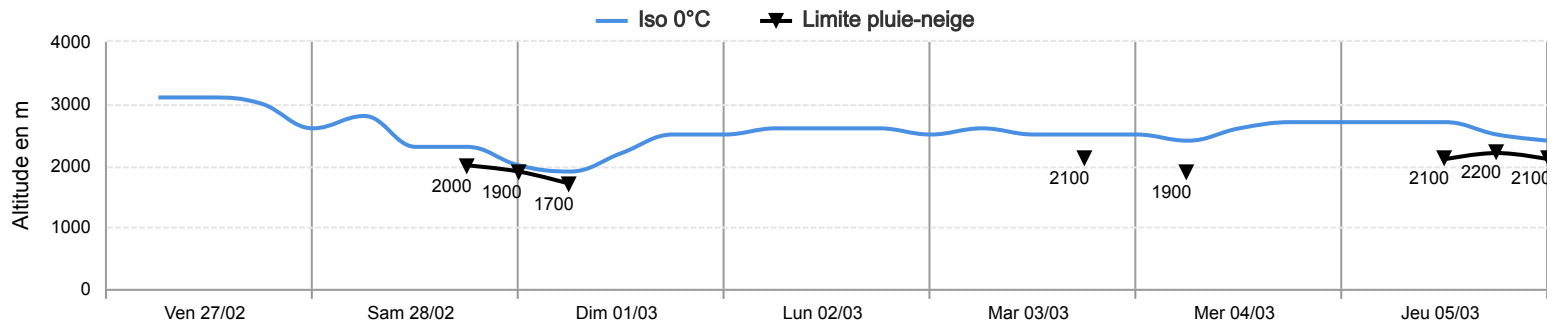

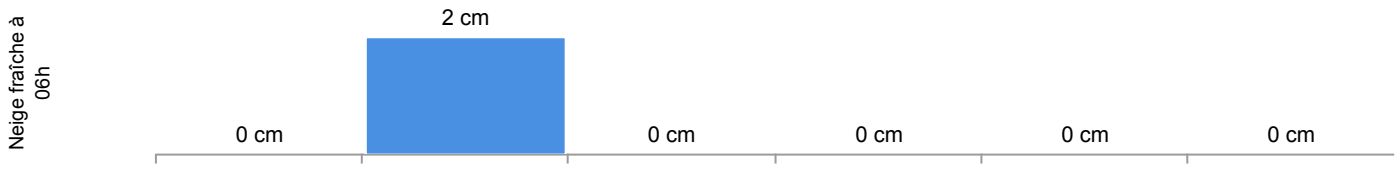

Risque d'avalanche	ven. 27/02	sam. 28/02	dim. 01/03	lun. 02/03	mar. 03/03	mer. 04/03	jeu. 05/03
	2	2	2	2	2	2	2

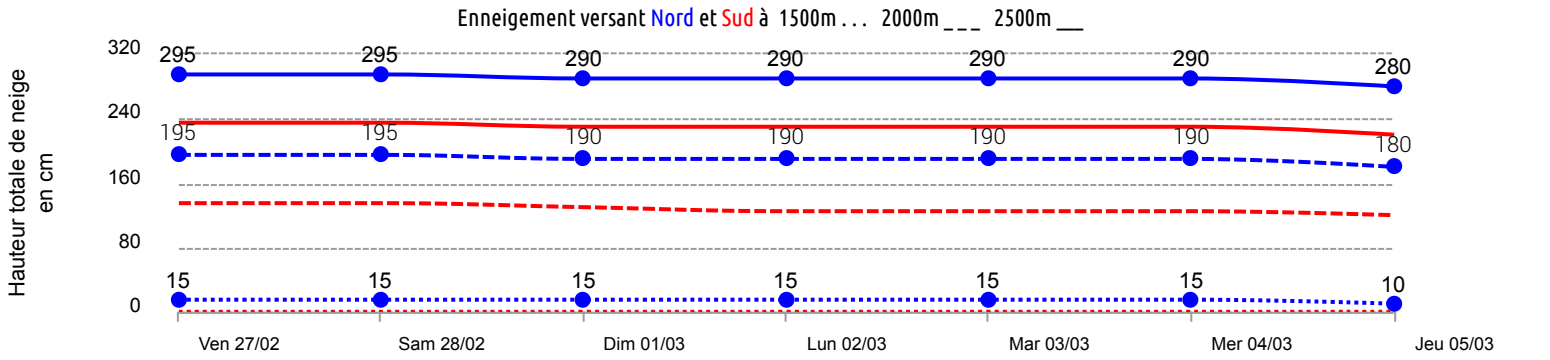

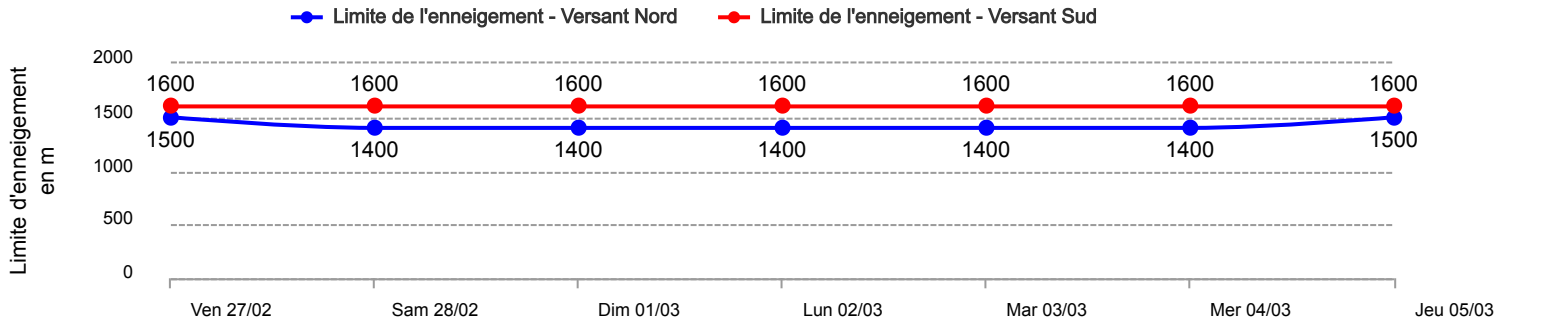

Pour consulter la vigilance en cours, veuillez vous rendre sur le site https://vigilance.meteofrance.fr/fr

Météo-France - 73 avenue de Paris, 94165 Saint-Mandé cedex - Contact : contact@meteo.fr

Rédigé par Météo-France avec la contribution des observateurs du réseau nivo-météorologiques. Partenariat : ANMSM (Maires de Stations de Montagne), DSF (Domaines Skiables de France), ADSP (Directeurs de Pistes et de la Sécurité des Stations de Sports d'Hiver) et autres acteurs de la montagne.

Bulletin neige & avalanches par téléphone au
0 892 68 10 20 Service 0,35 € / min + prix appel