Boletín de información nivológica y de peligro de aludes

Pirineo Catalán

viernes, 6 de marzo de 2026

Pronóstico hasta las 24 horas del sábado, día 7 de marzo

(Válido fuera de pistas de esquí balizadas y abiertas)

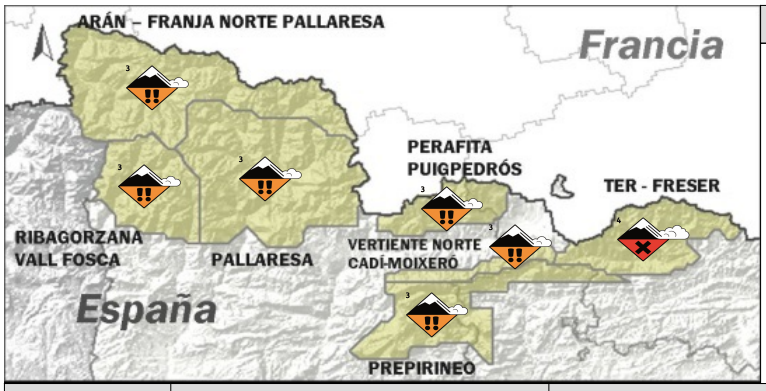

Problemas de aludes

- Placas de viento
- Nieve reciente
- Nieve húmeda

Macizo	Peligro	Problemas de aludes, cota, orientación, tamaño	Innivación observada (m)
Arán - Franja norte Pallaresa	3 / 3 2100 / 2 Notable	**Placas de viento**: 2100, N O E S, 2 **Deslizamientos basales**: 2300, N O E S, 2	2026-03-06 N S Cota más baja caras N
Ribagorzana - Vall Fosca	3 / 3 2100 / 2 Notable	**Placas de viento**: 2100, N O E S, 2 **Deslizamientos basales**: 2300, N O E S, 2	2026-03-06 N S Cota más baja caras N
Pallaresa	3 / 3 2100 / 2 Notable	**Placas de viento**: 2100, N O E S, 2 **Deslizamientos basales**: 2300, N O E S, 2	2026-03-06 N S Cota más baja caras N

AEMET. Se autoriza la reproducción de su contenido citando la fuente.

Boletín de información nivológica y de peligro de aludes

Pirineo Catalán

Perafita - Puigpedrós	3 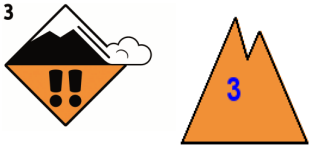 **Notable**	**Placas de viento** 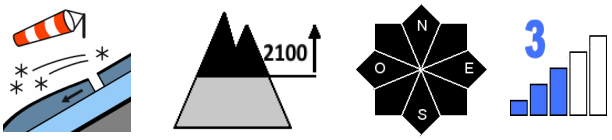	**Nieve húmeda** 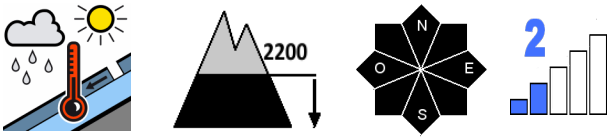	2026-03-06 Cota más baja caras N
Ter - Freser	4 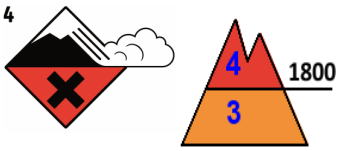 **Fuerte**	**Nieve reciente** 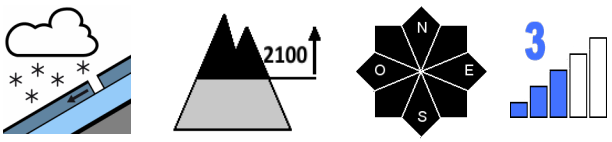	**Nieve húmeda** 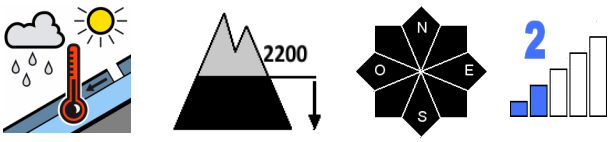	2026-03-06 Cota más baja caras N
Vertiente norte Cadí - Moixeró	3 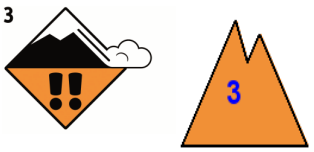 **Notable**	**Placas de viento** 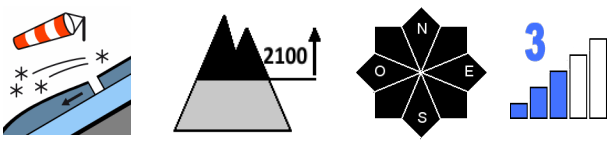	**Nieve húmeda**	2026-03-06 Cota más baja caras N
Prepirineo	3 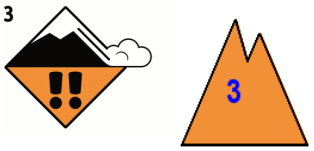 **Notable**	**Placas de viento** 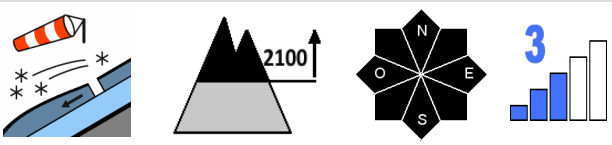	**Nieve húmeda** 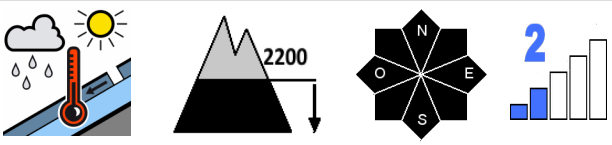	2026-03-06 Cota más baja caras N

Estado del manto y observaciones recientes

En las 24 horas previas a las 8 UTC del día de hoy, se habían registrado precipitaciones generalizadas muy significativas, alcanzando los 75-95 l/m2 en el macizo del Ter-Freser, los 30-40 l/m2 en el resto de los macizos orientales y los 10-25 l/m2 en los occidentales. Estas han ido acompañadas de una cota de nieve en el entorno de los 2100-1900 metros, dejando en cotas altas nuevos espesores muy importantes de nieve reciente. Sin embargo, en cotas medias y bajas las precipitaciones en forma de lluvia han humedecido y compactado aún más el manto, dando lugar a pérdidas de espesores notables. A pesar de ello, estos continúan

AEMET. Se autoriza la reproducción de su contenido citando la fuente.

siendo superiores a lo que sería habitual a estas alturas de la temporada. Cabe destacar que se espera que las precipitaciones continúen a lo largo del día de hoy, de manera fuerte y persistente en el Ripollès.

En cotas medias y bajas, así como en solanas a mayor altitud, el manto es primaveral y está humedecido en profundidad, sometido a ciclo de fusión-rehielo débil diario. En cotas altas, la nieve se mantiene más seca y aún podemos encontrar placas de viento antiguas que no se han estabilizado por completo. A estas se añadirán nuevas placas en proceso de formación, debido a este nuevo episodio de nevadas, acompañado de vientos moderados o fuertes de componentes este y sur. También en estas zonas podría persistir alguna capa débil enterrada que pueda seguir latente.

Evolución del manto y peligro de aludes para el sábado, día 7

Problemas de nieve reciente y placas de viento en cotas altas. Problemas de nieve húmeda y deslizamientos basales en cotas medias y bajas.

A lo largo del día de hoy se espera que continúen las precipitaciones, fuertes y persistentes en los macizos orientales, especialmente en el Ter-Freser, donde se espera que al final de la jornada de hoy se hayan podido alcanzar en cotas altas unos 100-150 cm de nieve reciente en las 48 horas previas (cota de nieve en torno a 1900-2100 metros). Estos acumulados serán menores cuanto más al oeste nos desplacemos, esperándose unos 50-80 cm en 48 horas en el resto de los macizos orientales, y unos 10-35 cm en los occidentales. Mañana se espera que continúen de manera más ocasional, pudiendo añadir tan solo unos pocos centímetros de nieve nueva.

Con todo esto, en cotas altas serán muy probables los aludes espontáneos de nieve reciente de tamaño pequeño (1, riesgo de caída), mediano (2, capaz de enterrar a una persona), o incluso grande (3, capaz de enterrar a un grupo de personas) en los macizos orientales, especialmente en el Ter-Freser. Además, los vientos que en cotas altas soplarán moderados o fuertes de componentes este y sur, formarán nuevas placas de viento a sotavento, preferentemente en orientaciones norte, oeste y sur. Estas estructuras podrán colapsar ante sobrecargas débiles (paso de un sólo esquiador), generando aludes de tamaño pequeño o mediano en los macizos occidentales, y alcanzando el tamaño grande en los macizos orientales o incluso muy grande (4, capaz de enterrar y destruir un vehículo) en el Ter-Freser. Tampoco se descarta que pueda reactivarse alguna capa débil persistente, especialmente en zonas de manto más delgado o erosionado.

En cotas medias y bajas, las copiosas lluvias junto con la ausencia de rehielo nocturno agravarán el problema de nieve húmeda, siendo probables los aludes espontáneos de tamaño pequeño o mediano (localmente grande en los macizos orientales), así como los deslizamientos basales en zonas herbosas o de roca lisa, que podrían movilizar una cantidad de nieve considerable y alcanzar el tamaño grande. Estos tipos de aludes serán muy probables en los macizos orientales, donde las lluvias serán más abundantes.

Predicción meteorológica para el sábado, día 7

Predominio de muy nuboso o cubierto, con visibilidad localmente reducida, pudiendo abrirse claros por la mañana.

AEMET. Se autoriza la reproducción de su contenido citando la fuente.

Precipitaciones débiles o localmente moderadas, a veces en forma de chubascos, que en el Arán y la franja norte de la Pallaresa serán ocasionales. No se descarta que en el Ripollès puedan ser localmente más intensas y frecuentes. Cota de nieve: en torno a 1500-1700 metros aproximadamente, alcanzando los 1300 metros a últimas horas en el Ripollès. No se descartan tormentas acompañando a los chubascos del Ripollès. Temperaturas mínimas generalmente en ligero descenso, localmente moderado en el Arán. Máximas en ligero o moderado ascenso en los macizos orientales, Arán y franja norte de la Pallaresa, sin cambios en el resto. Heladas débiles en cotas altas, localmente moderadas. Viento moderado o flojo con probables intervalos de viento fuerte en cotas altas y zonas expuestas, de componentes sur y este, aunque con predominio del sureste.

Datos en la atmósfera libre:

Altitud de la isoterma de 0 ºC: 2000 m
Altitud de la isoterma de -10 ºC: 3800 m

Viento a 1500 m: S 15 km/h
Viento a 3000 m: SE 35 km/h

Evolución para el domingo día 8

Nivel de peligro sin cambios o en ligero descenso.

Escala europea de peligro de aludes

Débil | Limitado | Notable | Fuerte | Muy Fuerte

Problemas de aludes

Nieve reciente | Placas de viento | Capas débiles persistentes | Nieve húmeda | Deslizamientos basales | Sin problema evidente

Nota1: Se recuerda que, siempre que haya nieve, la ausencia total de peligro no existe. Hay que tener presente que en circunstancias desfavorables, con aludes de tamaño 1 (alud pequeño o colada) y tamaño 2 (alud mediano), se pueden sufrir severos daños personales.

Nota2: Los BPA se elaboran en base a información meteorológica así como al estado del manto nivoso a través de sondeos puntuales. Se advierte a los usuarios de la variabilidad de esta información al extrapolarla a zonas extensas de montaña. Por ello, AEMET no se hace responsable de su uso para la toma de decisiones que conciernen a la seguridad personal, ni de los riesgos físicos o materiales de ellas derivadas.

AEMET. Se autoriza la reproducción de su contenido citando la fuente.