GOBIERNO DE ESPAÑA
VICEPRESIDENCIA TERCERA DEL GOBIERNO
MINISTERIO PARA LA TRANSICIÓN ECOLÓGICA Y EL RETO DEMOGRÁFICO

Boletín de información nivológica y de peligro de aludes

Pirineo Navarro y Aragonés

aemet Agencia Estatal de Meteorología

viernes, 6 de marzo de 2026

Pronóstico hasta las 24 horas del sábado, día 7 de marzo

(Válido fuera de pistas de esquí balizadas y abiertas)

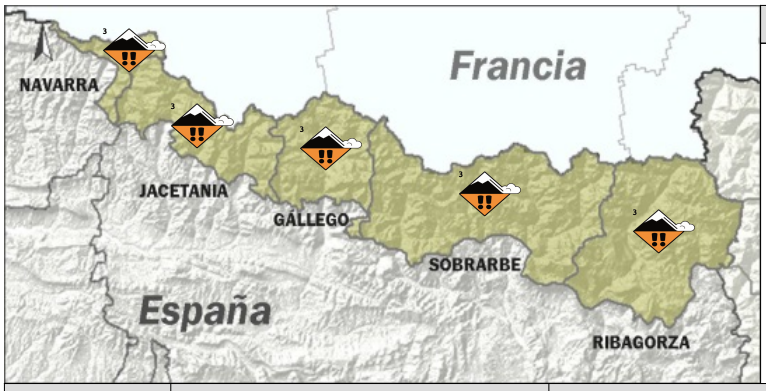

Problemas de aludes

Placas de viento

Deslizamientos basales

Macizo	Peligro	Problemas de aludes, cota, orientación, tamaño	Innivación observada (m)
Navarra	3 Notable (3 / 2 / 2000)	Placas de viento: 2100, N O E S, 2 Deslizamientos basales: 2200, N O E S, 2	2026-03-06 N S Cota más baja caras N
Jacetania	3 Notable (3 / 2 / 2000)	Placas de viento: 2100, N O E S, 2 Deslizamientos basales: 2200, N O E S, 2	2026-03-06 N S Cota más baja caras N
Gállego	3 Notable (3 / 2 / 2000)	Placas de viento: 2100, N O E S, 2 Deslizamientos basales: 2200, N O E S, 2	2026-03-06 N S Cota más baja caras N

AEMET. Se autoriza la reproducción de su contenido citando la fuente.

Sobrarbe	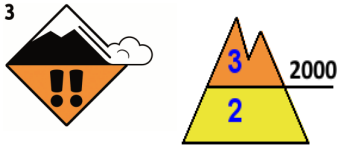 **Notable**	**Placas de viento** 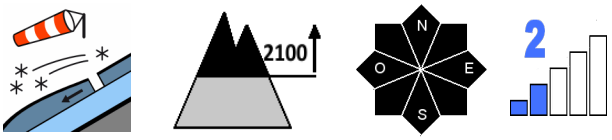 **Deslizamientos basales** 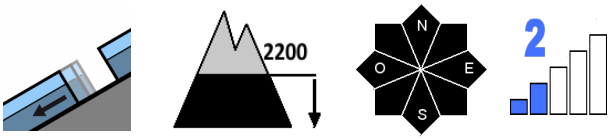	2026-03-06 Cota más baja caras N
Ribagorza	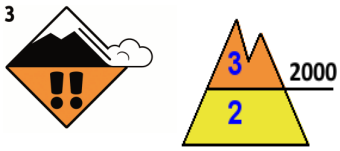 **Notable**	**Placas de viento** 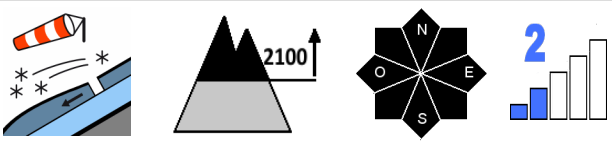 **Deslizamientos basales** 	2026-03-06 Cota más baja caras N

Estado del manto y observaciones recientes

En las 24 horas previas a las 8 UTC del día de hoy, se han registrado precipitaciones generalizadas del entorno de unos 10-20 l/m2, menos copiosas en la Jacetania y en el Pirineo navarro, donde los acumulados han sido de unos 5-10 l/m2, menores cuanto más al oeste. Estas han ido acompañadas de una cota de nieve en el entorno de los 2100-1900 metros, dejando en cotas altas nuevos espesores de nieve reciente de hasta 20 cm. Sin embargo, en cotas medias y bajas las precipitaciones en forma de lluvia han humedecido y compactado aún más el manto, dando lugar a pérdidas de espesores notables. A pesar de ello, estos continúan siendo superiores a lo que sería habitual a estas alturas de la temporada.

En general la nieve es continua desde los 1400 metros en orientaciones norte y desde los 1600-1700 metros en las sur. Aunque el manto es muy abundante desde cotas medias, se observa una asimetría norte-sur, con pérdidas notables en las solanas, donde incluso se pueden encontrar zonas desprovistas de nieve. Conforme ascendemos en altitud estos van incrementando, alcanzando los 160 cm a unos 1800 metros y los 2800 cm a unos 2300, e incluso los 4 metros en ventisqueros, hoyas y otras zonas propensas a la acumulación de cotas altas.

En cotas medias y bajas, así como en solanas a mayor altitud, el manto es primaveral y está humedecido hasta su base por debajo de los 2200 metros. Hoy no se ha observado rehielo nocturno. En cotas altas, la nieve está generalmente seca y, en umbrías, algunas zonas localizadas al abrigo del viento aún conservan algunas placas de viento antiguas que pueden descansar sobre capas débiles de facetas o nieve granulada. Los tests realizados hasta el día de ayer apuntaban que podrían desencadenarse ante sobrecargas fuertes. A estas estructuras se habrán añadido nuevas placas de viento, preferentemente en orientaciones norte, oeste y sur, debido a los vientos con predominio de componente este que han acompañado a las recientes nevadas de los días de ayer y hoy, observándose ya esta mañana transporte de nieve a estas laderas. Asimismo, en la base del manto aún siguen

AEMET. Se autoriza la reproducción de su contenido citando la fuente.

presentes algunas capas débiles persistentes, generalmente inactivas.

Cabe destacar que ayer por la mañana se observó una fina capa de polvo sahariano, distribuida por el viento de manera uniforme, que en ocasiones había quedado bajo otra de graupel grande, debido a la presencia de chubascos. Esta capa se espera que haya quedado cubierta por las nuevas nevadas, constituyendo una capa de manto débil.

Se han reportado algunas purgas de nieve reciente por encima de los 2200 metros.

Evolución del manto y peligro de aludes para el sábado, día 7

Problemas de nieve reciente y placas de viento en cotas altas. Problemas de nieve húmeda y deslizamientos basales en cotas medias y bajas.

Se espera que las precipitaciones continúen a lo largo de la tarde de hoy y el día de mañana, con una cota de nieve que irá descendiendo progresivamente, alcanzando los 1500-1600 metros a últimas horas de mañana. Así, se espera que al final de la jornada de mañana se puedan haber acumulado unos nuevos 5-10 cm de nieve reciente en cotas altas, sin descartar acumulados localmente superiores, que se añadirán a los observados esta mañana. Con todo esto, serán probables los aludes espontáneos de nieve reciente, de tamaño pequeño (1, riesgo de caída) o mediano (2, capaz de enterrar a una persona). Además, en cotas altas las nevadas irán acompañadas de vientos moderados o fuertes de componentes este y sur, por lo que se espera que formen placas de viento a sotavento, preferentemente en orientaciones norte, oeste y sur. Estas estructuras de nueva formación podrán colapsar ante sobrecargas débiles (paso de un sólo esquiador), generando aludes de tamaño pequeño o mediano. Dada la presencia en umbrías de algunas placas viejas o costras sobre capas débiles, la rotura de las placas recientes podría movilizar mayor cantidad de nieve y desencadenar aludes localmente grandes (3, capaz de enterrar a un grupo de personas). Tampoco se descarta que pueda reactivarse alguna capa débil persistente, especialmente en zonas de manto más delgado o erosionado.

En cotas medias y bajas, las lluvias copiosas junto con la ausencia de rehielo nocturno agravarán el problema de nieve húmeda, siendo probables los aludes espontáneos de tamaño pequeño o mediano, así como los deslizamientos basales en zonas herbosas o de roca lisa, que podrían movilizar una cantidad de nieve considerable y alcanzar tamaño mediano o localmente grande.

Predicción meteorológica para el sábado, día 7

Pirineo navarro:
Nuboso o muy nuboso, con apertura de claros ocasionales en las horas centrales, con visibilidad localmente reducida. Precipitaciones débiles o moderadas, en ocasiones en forma de chubasco. Cota de nieve: 1500-1800 metros. No se descartan tormentas acompañando a los chubascos. Temperaturas mínimas en moderado descenso y máximas en moderado ascenso. Heladas débiles. Viento flojo o moderado de componentes sur y este, predominando el sureste, con probables intervalos fuertes en cotas altas y zonas expuestas.

Pirineo aragonés:

AEMET. Se autoriza la reproducción de su contenido citando la fuente.

Predominio de muy nuboso o cubierto, con visibilidad localmente reducida, pudiendo abrirse claros por la mañana. Precipitaciones débiles o localmente moderadas, en ocasiones en forma de chubasco. Cota de nieve: en torno a 1500-1800 metros. No se descarta alguna tormenta acompañando a los chubascos. Temperaturas mínimas en ligero o moderado descenso. Máximas sin cambios o en ligero ascenso en zonas de la divisoria con Francia, salvo en la Jacetania donde ascenderán moderadamente. Heladas débiles, localmente moderadas en cotas altas. Viento moderado o flojo con probables intervalos fuertes en cotas altas y zonas expuestas, de componentes sur y este, aunque con predominio del sureste y este.

Datos en la atmósfera libre:

Altitud de la isoterma de 0 ºC: 1900 m
Altitud de la isoterma de -10 ºC: 3500 m

Viento a 1500 m: SE 15 km/h
Viento a 3000 m: SE 40 km/h

Evolución para el domingo día 8

Nivel de peligro sin cambios o en ligero descenso.

(Información elaborada a partir de los datos recibidos de los refugios de Linza, Lizara, Panticosa, Góriz, Pineta, Estós, Angel Orús, La Renclusa, Cap de Llauset y Belagua, de las estaciones de esquí de Candanchú, Formigal y Panticosa (lagos), de la estación de esquí de fondo de Llanos del Hospital y de Ordesa Pradera)

Escala europea de peligro de aludes

Débil Limitado Notable Fuerte Muy Fuerte

Problemas de aludes

Nieve reciente Placas de viento Capas débiles persistentes Nieve húmeda Deslizamientos basales Sin problema evidente

Nota1: Se recuerda que, siempre que haya nieve, la ausencia total de peligro no existe. Hay que tener presente que en circunstancias desfavorables, con aludes de tamaño 1 (alud pequeño o colada) y tamaño 2 (alud mediano), se pueden sufrir severos daños personales.

Nota2: Los BPA se elaboran en base a información meteorológica así como al estado del manto nivoso a través de sondeos puntuales. Se advierte a los usuarios de la variabilidad de esta información al extrapolarla a zonas extensas de montaña. Por ello, AEMET no se hace responsable de su uso para la toma de decisiones que conciernen a la seguridad personal, ni de los riesgos físicos o materiales de ellas derivadas.

AEMET. Se autoriza la reproducción de su contenido citando la fuente.