Samedi 07.03.2026

Publié 06 03 2026, 17:00

Matin

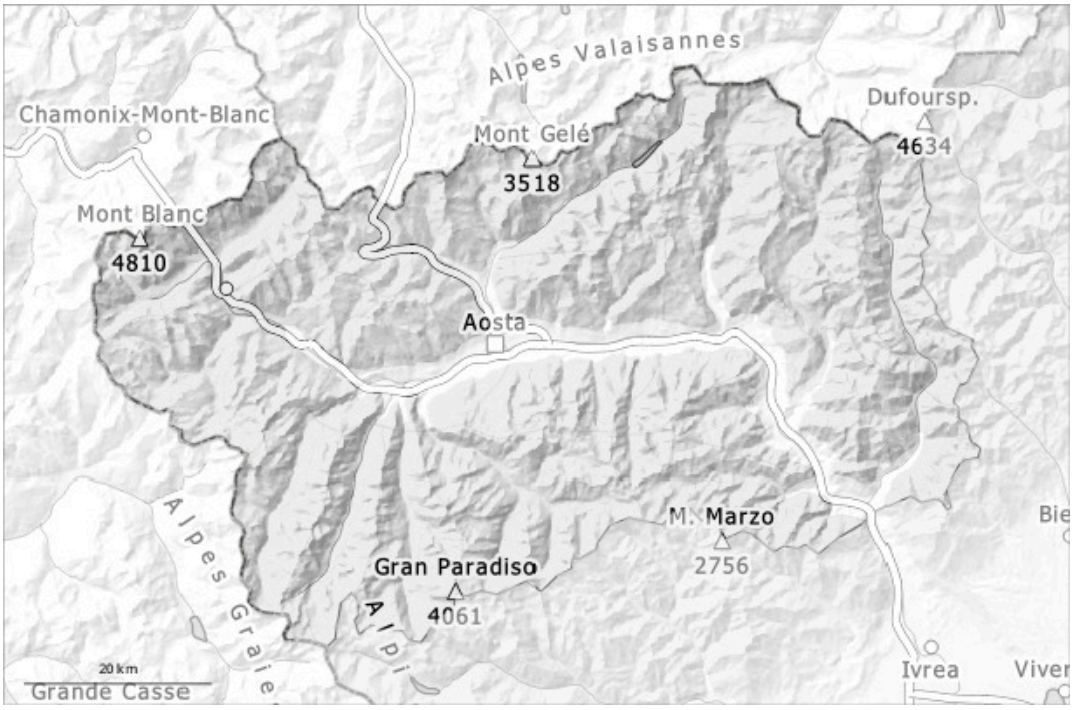

Après-midi

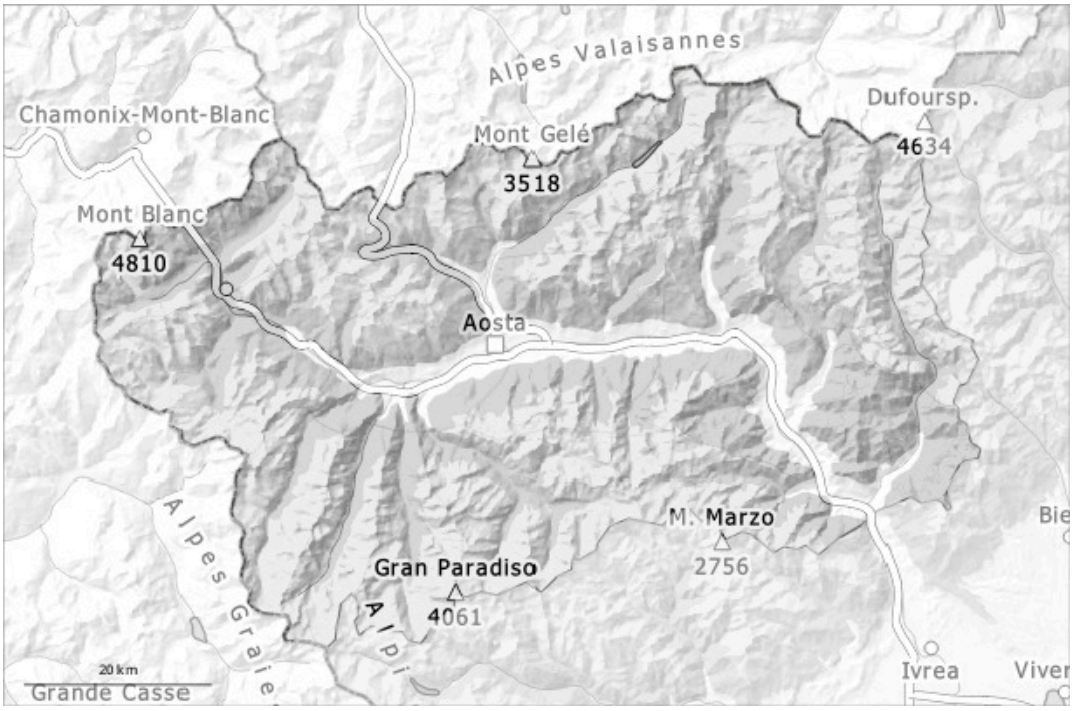

1	2	3	4	5
faible	limité	marqué	fort	très fort

Degré de danger 2 - Limité

AM:

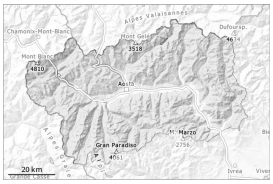

Tendance: danger d'avalanche constant
leDimanche 08 03 2026

Neige ancienne (Sous-couche fragile persistante)

2400m

PM:

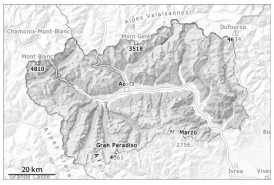

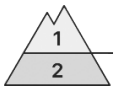

2600m

Tendance: danger d'avalanche constant
leDimanche 08 03 2026

Avalanches mouillées (Neige humide)

2600m
2000m

Neige ancienne (Sous-couche fragile persistante)

2400m

Les conditions de randonnées sont en général favorables.

La surface de la neige regèle et devient porteuse et se ramollit dès la matinée, surtout par nuit couverte, surtout en dessous d'environ 2000 m.
Augmentation légère du danger avec le réchauffement diurne. En cours de journée de rares avalanches humides et mouillées en général de petite taille sont possibles surtout à moyenne altitude, surtout à partir des zones de départ extrêmement raides pas encore totalement déchargées.
Plus profondément dans le manteau neigeux des couches fragiles sont présentes. Des avalanches peuvent de manière très isolée être déclenchées dans les couches profondes du manteau neigeux et atteindre une taille moyenne de manière isolée. Ces endroits dangereux se situent surtout aux endroits plutôt faiblement enneigés ainsi que dans les terrains de randonnée faiblement fréquentés.

Manteau neigeux

Modèles de danger md.1: sous-couche fragile persistante | md.10: situation de printemps

Les conditions météorologiques ont favorisé une solidification du manteau neigeux surtout sur les pentes

au soleil. La partie supérieure du manteau neigeux est largement stable, avec une croûte de regel souvent porteuse à la surface. A ces endroits il existe en terrain raide un risque de chute.
Spécialement sur les pentes raides à l'ombre à haute altitude et en haute montagne: Dans le manteau neigeux ancien des couches fragiles sont présentes. La partie supérieure du manteau neigeux a subi une métamorphose constructive, avec une surface constituée de cristaux ayant subi une métamorphose constructive à grains anguleux.
À proximité des crêtes et des cols ainsi qu'à haute altitude on trouve suivant l'influence du vent des hauteurs de neiges très différentes.
Presque plus d'avalanches ont été annoncées dans les derniers jours.

Tendance

Les conditions pour les randonnées et le hors-piste sont assez favorables. Sur la surface de neige dure il existe en terrain raide un risque de chute. Avec le réchauffement diurne le danger d'avalanches humides et mouillées non diminue pour l'instant.