ICGC Institut Cartogràfic i Geològic de Catalunya

Servei Meteorològic de Catalunya meteo.cat

Boletín de peligro de aludes para el Pirineo de Catalunya
Del 06/03/2026 al 07/03/2026

(Válido fuera pistas de esquí y zonas no controladas)

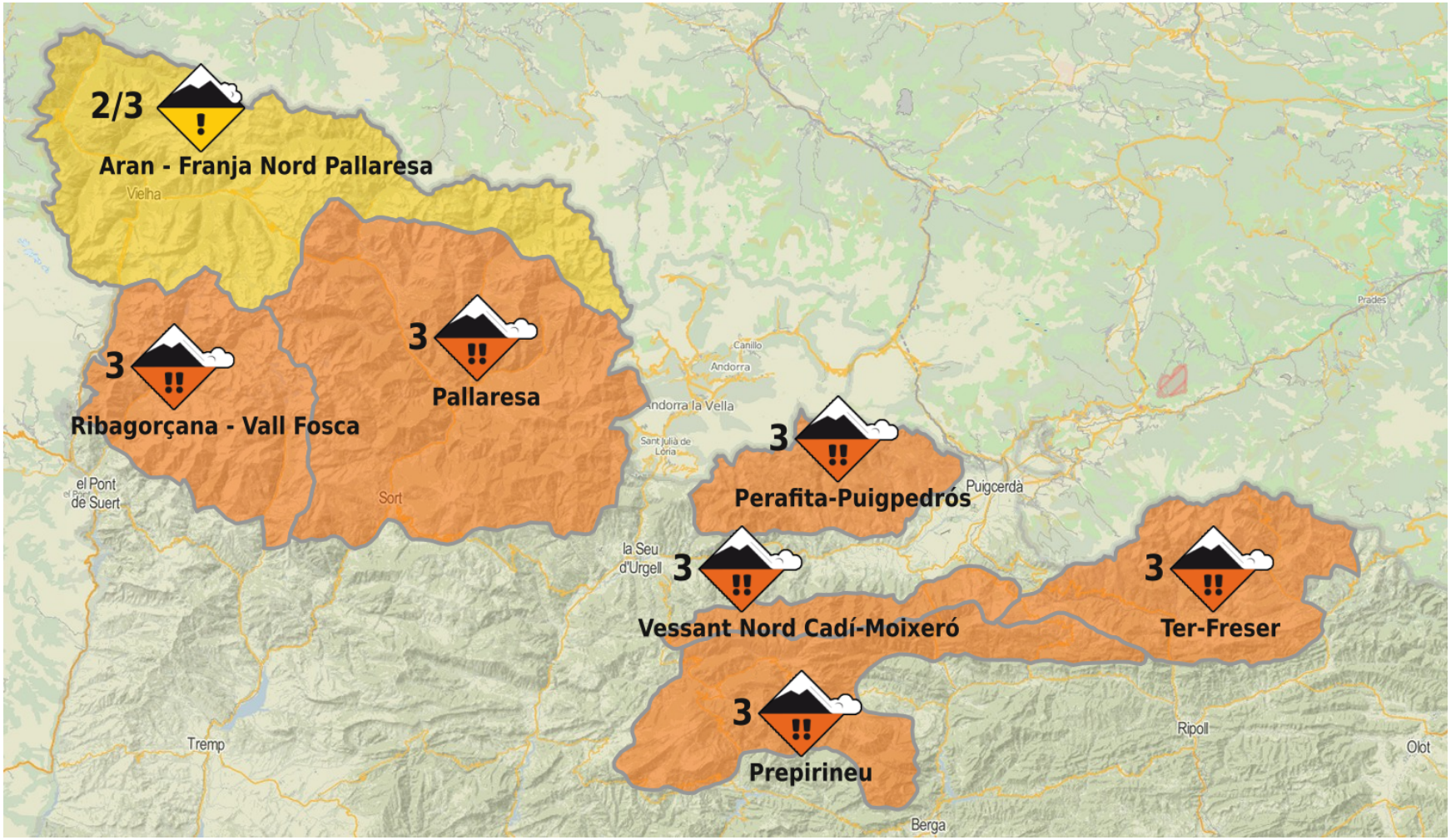

5 MUY FUERTE	4 FUERTE	3 NOTABLE	2 LIMITADO	1 DÉBIL

ICGC Institut Cartogràfic i Geològic de Catalunya

Servei Meteorològic de Catalunya meteo.cat

Boletín de peligro de aludes Aran - Franja Nord Pallaresa Del 06/03/2026 al 07/03/2026

(Válido fuera pistas de esquí y zonas no controladas)

LIMITADO (2) sábado.
NOTABLE (3) viernes.

Situación primaria

Deslizamientos basales **Distribución** **Tamaño** **Origen** **Tendencia**

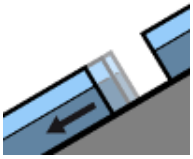

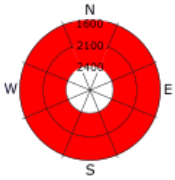

Situación secundaria

Nieve venteada **Distribución** **Tamaño** **Origen** **Tendencia**

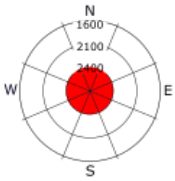

Estado del manto nivoso

El jueves empezó a llover por debajo de 2.400 m (unos 15-20 mm en el Aran, unos 10 mm en la Franja Norte de la Pallaesa), bajando la lluvia a unos 1.900 m el viernes. Se han acumulado unos 10-15 cm de nieve reciente húmeda en cotas altas. El sábado habrá ratos de sol y los deslizamientos basales se volverán a reactivar y probablemente se concentre la actividad en cotas medias de las umbrías, donde días pasados todavía no había habido actividad. Serán de tamaño 2, mediano, suficiente para enterrar a una persona, puntualmente mayor. Se desprenden en terreno herboso y liso; evitad situaros bajo fisuras en el manto. Bajo collados y cordales se irán formando placas de viento, sobre todo en las vertientes norte y oeste; podrán caer aludes de placa al paso de personas y en general serán de tamaño 1, pequeño, con capacidad de derribarnos y arrastrarnos. Habrá claros durante la madrugada del sábado, el manto puede rehelar un poco por la mañana, pero rápidamente se humedecerá.

Distribución del manto nivoso

Hay nieve por encima de unos 1.400-1-500 m en umbrías y 1.700 m en solanas. Los espesores a unos 2.200 m son superiores a los normales en la Franja Norte de la Pallaresa y en la mitad sur del Aran donde rondan los 160-200 cm. En la mitad norte de Arán hay unos 120-140 cm de grosor total.

Tendencia para las próximas 48-72h

Volveremos hacia un manto más seco en cotas altas con mayor frecuencia y mayor tamaño de placas de viento. Peligro ESTACIONARIO O EN LIGERO AUMENTO en cotas altas.

El próximo boletín será emitido el día 2026-03-07

5 MUY FUERTE	4 FUERTE	3 NOTABLE	2 LIMITADO	1 DÉBIL

EAWS EUROPEAN AVALANCHE WARNING SERVICES

ICGC Institut Cartogràfic i Geològic de Catalunya

meteo.cat Servei Meteorològic de Catalunya

Boletín de peligro de aludes Ribagorçana - Vall Fosca Del 06/03/2026 al 07/03/2026

(Válido fuera pistas de esquí y zonas no controladas)

NOTABLE (3)

Situación primaria

Nieve venteada

Distribución

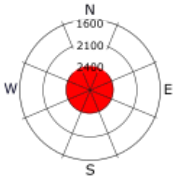

Tamaño

Origen

Tendencia

Situación secundaria

Nieve húmeda

Distribución

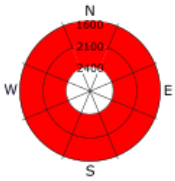

Tamaño

Origen

Tendencia

Estado del manto nivoso

El viernes hay nieve reciente húmeda (unos 15 cm) por encima de un manto húmedo y blando. Viernes tarde se esperan unos 10 cm más y el sábado unos pocos más. Por encima de 2.200 m podrán caer aludes de nieve reciente de forma natural en laderas de fuerte pendiente, cualquier orientación; serán de tamaño 2, mediano, con capacidad de enterrar a una persona. Bajo collados y cordales hay placas de viento sobre todo en orientaciones norte y oeste, que caerán al paso de una persona; por lo general de tamaño 2, mediano. Por debajo de 2.200 m caerán aludes de nieve húmeda ya que el manto está muy mojado internamente, en cualquier orientación, y pueden ser de tamaño 2, mediano. Atención si se observan fisuras en el manto, ya que son probales aludes de deslizamiento basal debido a la lluvia del viernes que ha entrado dentro del manto. Si hay algunos claros durante la madrugada del sábado, el manto puede rehelar un poco por la mañana, pero rápidamente se humedecerá y debilitará durante el día.

Distribución del manto nivoso

Hay nieve en el suelo a 1.600 m en terreno umbrío, y por encima de unos 1.800 m en laderas soleadas. El manto es esquiable por encima de unos 1.700-1.800 m en umbrías. Los grosores alcanzan los 100-130 cm a unos 2.200 m. Estos valores son aún superiores a los normales para la época.

Tendencia para las próximas 48-72h

Volveremos hacia un manto más seco en cotas altas con formación de más placas de viento en orientaciones norte. Peligro ESTACIONARIO.

El próximo boletín será emitido el día 2026-03-07

5 MUY FUERTE	4 FUERTE	3 NOTABLE	2 LIMITADO	1 DÉBIL

EAWS EUROPEAN AVALANCHE WARNING SERVICES

ICGC Institut Cartogràfic i Geològic de Catalunya

meteo.cat Servei Meteorològic de Catalunya

Boletín de peligro de aludes Pallaresa
Del 06/03/2026 al 07/03/2026

(Válido fuera pistas de esquí y zonas no controladas)

NOTABLE (3)

Situación primaria

Nieve venteada

Distribución

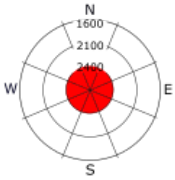

Tamaño

Origen

Tendencia

Situación secundaria

Nieve húmeda

Distribución

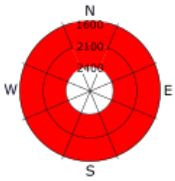

Tamaño

Origen

Tendencia

Estado del manto nivoso

El viernes hay nieve reciente húmeda (unos 15 cm) por encima de un manto húmedo y blando. Viernes tarde se esperan unos 10 cm más y el sábado unos pocos más. Por encima de 2.200 m podrán caer aludes de nieve reciente de forma natural en laderas de fuerte pendiente, cualquier orientación; serán de tamaño 2, mediano, con capacidad de enterrar a una persona. Bajo collados y cordales hay placas de viento sobre todo en orientaciones norte y oeste, que caerán al paso de una persona; por lo general de tamaño 2, mediano. Por debajo de 2.200 m caerán aludes de nieve húmeda ya que el manto está muy mojado internamente, en cualquier orientación, y pueden ser de tamaño 2, mediano. Atención si se observan fisuras en el manto, ya que son probales aludes de deslizamiento basal debido a la lluvia del viernes que ha entrado dentro del manto. Si hay algunos claros durante la madrugada del sábado, el manto puede rehelar un poco por la mañana, pero rápidamente se humedecerá y debilitará durante el día.

Distribución del manto nivoso

Hay nieve en el suelo a 1.600 m en terreno umbrío, y por encima de unos 1.800 m en laderas soleadas. El manto es esquiable por encima de unos 1.700-1.800 m en umbrías. Los grosores alcanzan los 110-150 cm a unos 2.200 m.

Tendencia para las próximas 48-72h

Volveremos hacia un manto más seco en cotas altas con formación de más placas de viento en orientaciones norte. Peligro ESTACIONARIO.

El próximo boletín será emitido el día 2026-03-07

5 MUY FUERTE	4 FUERTE	3 NOTABLE	2 LIMITADO	1 DÉBIL

EAWS EUROPEAN AVALANCHE WARNING SERVICES

ICGC Institut Cartogràfic i Geològic de Catalunya

Servei Meteorològic de Catalunya meteo.cat

Boletín de peligro de aludes Perafita-Puigpedrós Del 06/03/2026 al 07/03/2026

(Válido fuera pistas de esquí y zonas no controladas)

NOTABLE (3)

Situación primaria

Nieve venteada

Distribución

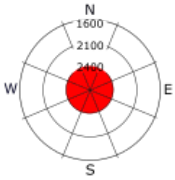

Tamaño

Origen

Tendencia

Situación secundaria

Nieve húmeda

Distribución

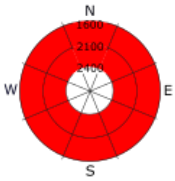

Tamaño

Origen

Tendencia

Estado del manto nivoso

Por la mañana del viernes por encima de 2.400 m hay nieve reciente húmeda (unos 10 cm) por encima de un manto húmedo y debilitado. Para el resto del viernes se esperan unos 15 cm más y el sábado unos pocos más. Por encima de 2.200 m podrán caer aludes de nieve reciente de forma natural en laderas de fuerte pendiente en cualquier orientación; serán de tamaño 2, mediano, con capacidad de enterrar a una persona. Bajo collados y cordales hay placas de viento sobre todo en orientaciones norte y oeste, que caerán al paso de una persona; por lo general de tamaño 2, mediano. Por debajo de 2.200 m caerán aludes de nieve húmeda ya que el manto está muy mojado internamente, en cualquier orientación, y pueden ser de tamaño 2, mediano. Si hay algunos claros durante la madrugada del sábado, el manto puede rehelar un poco por la mañana, pero rápidamente se humedecerá y debilitará durante el día.

Distribución del manto nivoso

Hay nieve en el suelo por encima de unos 1.600-1.700 m. El manto es esquiable por encima de unos 1.800 m. Los espesores, aunque irregulares, rondan los 80-100 cm en cotas medias. Son grosores por encima de los habituales para la época.

Tendencia para las próximas 48-72h

Volveremos hacia un manto más seco en cotas altas con formación de más placas de viento en orientaciones norte. Peligro ESTACIONARIO.

El próximo boletín será emitido el día 2026-03-07

5 MUY FUERTE	4 FUERTE	3 NOTABLE	2 LIMITADO	1 DÉBIL

EAWS EUROPEAN AVALANCHE WARNING SERVICES

ICGC Institut Cartogràfic i Geològic de Catalunya

meteo.cat Servei Meteorològic de Catalunya

Boletín de peligro de aludes
Vessant Nord Cadí-Moixeró
Del 06/03/2026 al 07/03/2026

(Válido fuera pistas de esquí y zonas no controladas)

NOTABLE (3)

Situación primaria

Nieve reciente

Distribución

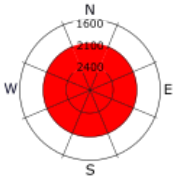

Tamaño

Origen

Tendencia

Situación secundaria

Nieve húmeda

Distribución

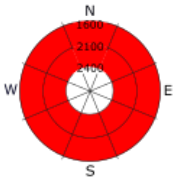

Tamaño

Origen

Tendencia

Estado del manto nivoso

Por la mañana del viernes por encima de 2.200 m hay nieve reciente húmeda, unos 10 cm, que a 2.400 puede llegar a los 20-30 cm, por encima de un manto húmedo y debilitado. Para el resto del viernes se esperan unos 10 cm más y el sábado unos pocos más. Por encima de 2.200 m podrán caer aludes de nieve reciente de forma natural en las canales y en laderas de fuerte pendiente y en cualquier orientación; serán de tamaño 2, mediano, con capacidad de enterrar a una persona. Bajo collados y cordales hay placas de viento sobre todo en orientaciones norte y oeste, que caerán al paso de una persona; por lo general de tamaño 2, mediano. Por debajo de 2.200 m caerán aludes de nieve húmeda ya que el manto está muy mojado internamente, en cualquier orientación, y pueden ser de tamaño 2, mediano. Si hay algunos claros durante la madrugada del sábado, el manto puede rehelar un poco por la mañana, pero rápidamente se humedecerá y debilitará durante el día.

Distribución del manto nivoso

En umbrías hay nieve por encima de 1.600 m, esquiable por encima de unos 1.700 m. En solanas la nieve está presente por encima de 1.800 m. Los grosores están alrededor de 150-170 cm a 2.200 m. Estos valores son muy excedentarios para la época del año.

Tendencia para las próximas 48-72h

Volveremos hacia un manto más seco en cotas altas con formación de más placas de viento en orientaciones norte. Peligro ESTACIONARIO.

El próximo boletín será emitido el día 2026-03-07

5 MUY FUERTE	4 FUERTE	3 NOTABLE	2 LIMITADO	1 DÉBIL

EAWS EUROPEAN AVALANCHE WARNING SERVICES

ICGC Institut Cartogràfic i Geològic de Catalunya

meteo.cat Servei Meteorològic de Catalunya

Boletín de peligro de aludes Prepirineu
Del 06/03/2026 al 07/03/2026

(Válido fuera pistas de esquí y zonas no controladas)

NOTABLE (3)

Situación primaria

Nieve reciente

Distribución

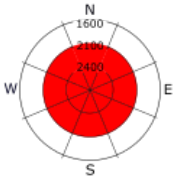

Tamaño

Origen

Tendencia

Situación secundaria

Nieve húmeda

Distribución

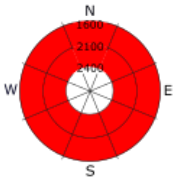

Tamaño

Origen

Tendencia

Estado del manto nivoso

Por la mañana del viernes en cotas altas hay nieve reciente húmeda (5-10 cm) por encima de un manto húmedo y debilitado. Para el resto del viernes se esperan unos 5-10 cm más y el sábado unos pocos más. Por encima de 2.200 m podrán caer aludes de nieve reciente de forma natural en laderas de fuerte pendiente y en cualquier orientación; serán de tamaño 2, mediano, con capacidad de enterrar a una persona. En las cotas más altas, bajo collados y cordales hay algunas placas de viento sobre todo en orientaciones norte y oeste, que caerán al paso de una persona; por lo general de tamaño 2, mediano. Por debajo de 2.200 m caerán aludes de nieve húmeda ya que el manto está muy mojado internamente, en cualquier orientación, y pueden ser de tamaño 2, medio. Si hay algunos claros durante la madrugada del sábado, el manto puede rehelar un poco por la mañana, pero rápidamente se humedecerá y debilitará durante el día.

Distribución del manto nivoso

En umbrías hay nieve por encima de 1.600-1700 m. En solanas la nieve está presente por encima de 1.800-1.900 m. Los espesores, aunque irregulares, rondan los 60-80 cm en cotas medias.

Tendencia para las próximas 48-72h

Volveremos hacia un manto más seco en cotas altas con formación de placas de viento en orientaciones norte. Peligro ESTACIONARIO.

El próximo boletín será emitido el día 2026-03-07

5 MUY FUERTE	4 FUERTE	3 NOTABLE	2 LIMITADO	1 DÉBIL

EAWS EUROPEAN AVALANCHE WARNING SERVICES

ICGC Institut Cartogràfic i Geològic de Catalunya

Servei Meteorològic de Catalunya meteo.cat

Boletín de peligro de aludes Ter-Freser
Del 06/03/2026 al 07/03/2026

(Válido fuera pistas de esquí y zonas no controladas)

NOTABLE (3)

Situación primaria

Nieve venteada

Distribución

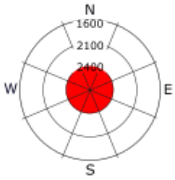

Tamaño

Origen

Tendencia

Situación secundaria

Nieve húmeda

Distribución

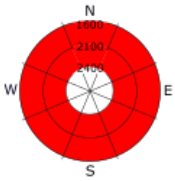

Tamaño

Origen

Tendencia

Estado del manto nivoso

Por la mañana del viernes por encima de 2.400 m hay nieve reciente húmeda (unos 30 cm) por encima de un manto húmedo y debilitado. Para el resto del viernes se esperan unos 30 cm más y el sábado unos pocos más. Por encima de 2.200 m caerán aludes de nieve reciente de forma natural en laderas de fuerte pendiente ya cualquier orientación; serán de tamaño 2, mediano, con capacidad de enterrar a una persona. Bajo collados y cordales hay placas de viento sobre todo en orientaciones norte y oeste, que caerán al paso de una persona; localmente de tamaño 3, grande, con capacidad de enterrar a un grupo de personas. Por debajo de 2.200 m caerán aludes de nieve húmeda ya que el manto está muy mojado internamente, en cualquier orientación, y pueden ser de tamaño 2, mediano. Si hay algunos claros durante la madrugada del sábado, el manto puede rehelar un poco por la mañana, pero rápidamente se humedecerá y debilitará durante el día.

Distribución del manto nivoso

El manto nivoso presenta grosores muy excedentarios para la época del año. En lugares no afectados por el viento los grosores oscila entre 80-100 cm a unos 2.000 m y 190-220 cm por encima de 2.400 m. Es esquiable a partir de unos 1.600 m.

Tendencia para las próximas 48-72h

Volveremos hacia un manto más seco en cotas altas con formación de más placas de viento en orientaciones norte. Peligro ESTACIONARIO.

El próximo boletín será emitido el día 2026-03-07

5 MUY FUERTE	4 FUERTE	3 NOTABLE	2 LIMITADO	1 DÉBIL

EAWS EUROPEAN AVALANCHE WARNING SERVICES