BUTLLETÍ DEL PERILL D'ALLAUS DEL PRINCIPAT D'ANDORRA

Servei meteorològic nacional
Principat d'Andorra

Elaborat el 06/03/2026 16:00
Propera actualització 07/03/2026 a les 16h

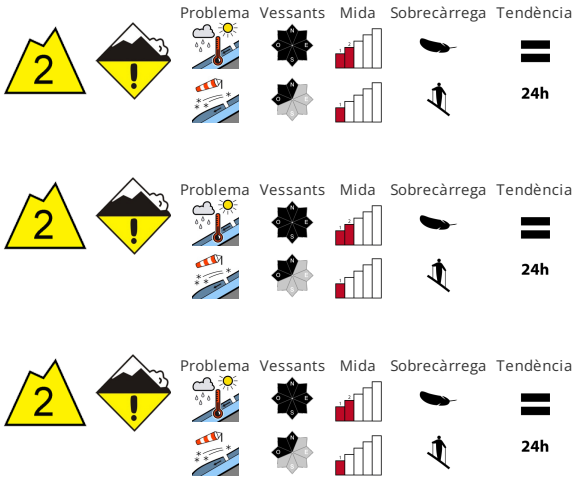

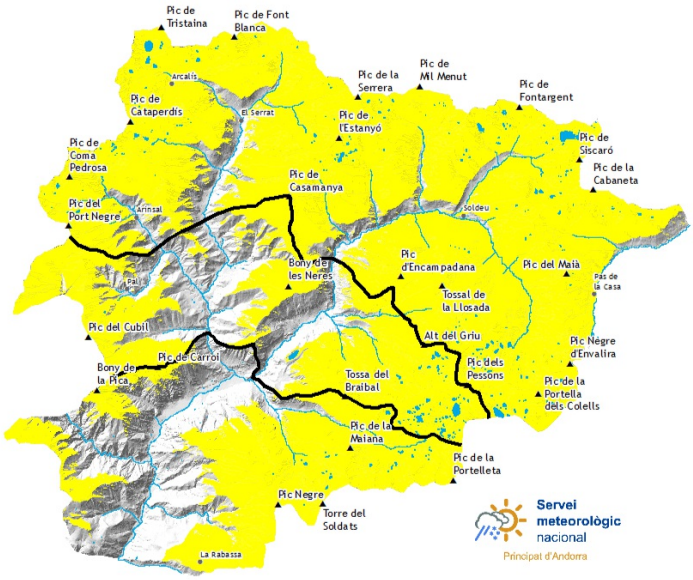

ESTABILITAT DEL MANTELL NIVAL

Amb la intensificació de la precipitació, per sota dels 2200 m aproximadament són d'esperar allaus de neu humida. Aquestes poden desencadenar-se de manera natural i assolir mida mitjana. A més, són d'esperar allaus de lliscament basal en qualsevol moment. A cotes altes :. El vent del sud-est transportarà la neu recent. Amb la neu recent i el vent les plaques de vent augmentaran de mida lleugerament. A més són possibles algunes allaus de placa humida de mida petita. Aquests indrets són parcialment coberts de neu recent i difícils de reconèixer. Els indrets perillosos són difícils de reconèixer amb mala visibilitat.

QUALITAT DE LA NEU

Caurà pluja fins a cotes altes especialment als al sud-est. Cauran localment fins a 15 cm de neu per sobre dels 2000 m aproximadament. El refredament nocturn serà reduït. Els gruixos de neu varien molt per sobre dels 2100 m aproximadament per la influència del vent. Evitar les zones amb esquerdes de lliscament basal. Dissabte :. El temps serà parcialment assolellat.

GRUIXOS DEL MANTELL NIVAL FORA DE PISTA

Zona nord		Gruix neu		
Mantell Nival		1500m	2000m	2500m
N	1600 m	0 cm	150 cm	200 cm
S	1900 m	0 cm	100 cm	150 cm

Zona centre		Gruix neu		
Mantell Nival		1500m	2000m	2500m
N	1600 m	0 cm	150 cm	200 cm
S	1900 m	0 cm	100 cm	150 cm

Zona sud		Gruix neu		
Mantell Nival		1500m	2000m	2500m
N	1600 m	0 cm	120 cm	150 cm
S	1900 m	0 cm	60 cm	100 cm

Govern d'Andorra

EAWS EUROPEAN AVALANCHE WARNING SERVICES

Aquest butlletí ha estat elaborat seguint les normes i recomanacions de l'**European Avalanche Warning Services**, del qual el **Servei meteorològic Nacional** n'és membre

BUTLLETÍ DEL PERILL D'ALLAUS DEL PRINCIPAT D'ANDORRA

Servei meteorològic nacional
Principat d'Andorra

Informació detallada per espais naturals protegits

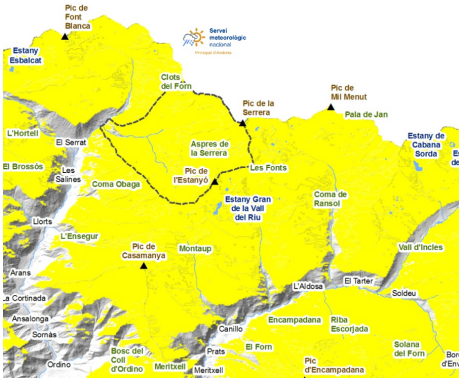

SORTENY

Continuaran les febles precipitacions amb fang i una cota de neu al voltant dels 2000 m, que humidificaran el mantell en totes les orientacions, per sota d´aquesta cota; mentre que per sobre es podran formar febles acumulacions d'uns 5 cm en aquest sector. En altura, el vent podrà transportar la poca neu disponible i formar petites acumulacions irregulars.

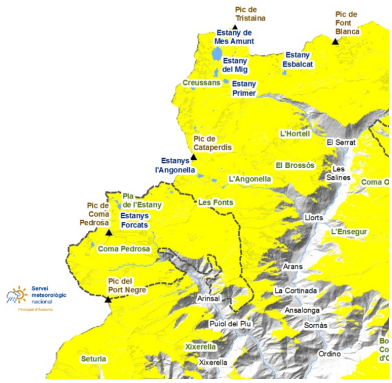

COMAPEDROSA

L´accés des d´Arinsal està quedant cada vegada amb menys neu, i la pluja prevista encara enretirarà més la línia de neu contínua. Mentre durin les precipitacions la mala visibilitat fa desaconsellar les excursions al Parc, però un cop hagin finalitzat, es podran fer nombroses excursions, sempre mantenint una elecció acurada de l´itinerari.

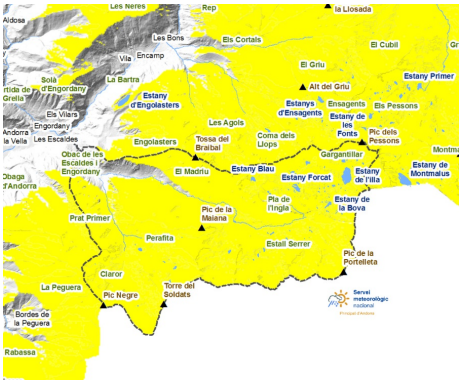

MADRIU-PERAFITA-CLAROR

El mantell és en general prim i irregular, amb millor continuïtat de neu als vessants nord i obacs. H estat el sector més afectat per les precipitacions del dijous, tot i que en alguns indrets elevats el vent ha deixat la neu vella al descobert. Fins dissabte continuarà essent el sector amb més precipitacions i, per tant, on preveiem la major activitat.

Govern d'Andorra

EAWS
EUROPEAN AVALANCHE WARNING SERVICES

Aquest butlletí ha estat elaborat seguint les normes i recomanacions de l'**European Avalanche Warning Services**, del qual el **Servei meteorològic Nacional** n'és membre

BUTLLETÍ DEL PERILL D'ALLAUS DEL PRINCIPAT D'ANDORRA

Servei meteorològic nacional
Principat d'Andorra

Gruixos de neu nova dels darrers dies (de les últimes 24h mesurat a les 06:00h UTC)

	02/03/2026	03/03/2026	04/03/2026	05/03/2026
FEDA (Central)	0 cm	0 cm	0 cm	0 cm
Engolasters - FEDA	0 cm	0 cm	0 cm	0 cm
Bony de les Neres	0 cm	0 cm	0 cm	0 cm
Sorteny	0 cm	0 cm	3 cm	10 cm
Les Fonts d'Arinsal	0 cm	4 cm	0 cm	10 cm
Perafita	0 cm	4 cm	3 cm	26 cm
Tossa Espiolets	0 cm	2 cm	0 cm	17 cm
Grau Roig - FEDA	0 cm	0 cm	0 cm	3 cm
Fontverd	0 cm	0 cm	0 cm	0 cm
Ransol - FEDA	0 cm	0 cm	0 cm	0 cm
Setúria	0 cm	0 cm	0 cm	0 cm
Caborreu	0 cm	0 cm	0 cm	0 cm
La Solana	0 cm	0 cm	0 cm	10 cm
Coll Pa	0 cm	0 cm	0 cm	9 cm
Envalira Antenes	0 cm	4 cm	0 cm	1 cm
Vall del Riu FEDA	0 cm	3 cm	0 cm	9 cm