BUTLLETÍ DEL PERILL D'ALLAUS DEL PRINCIPAT D'ANDORRA

Elaborado el 06/03/2026 16:00
Proxima actualización 07/03/2026 a las 16h

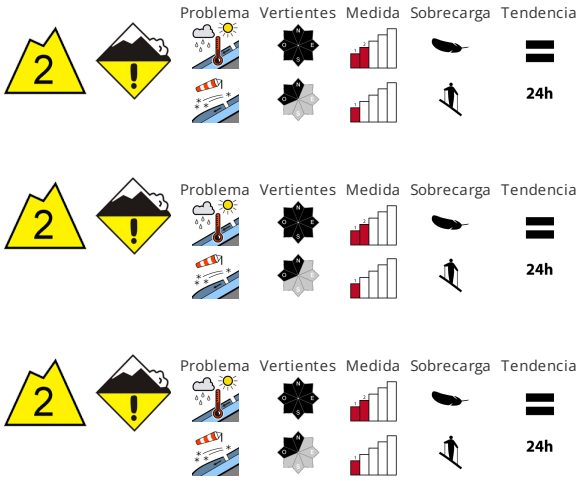

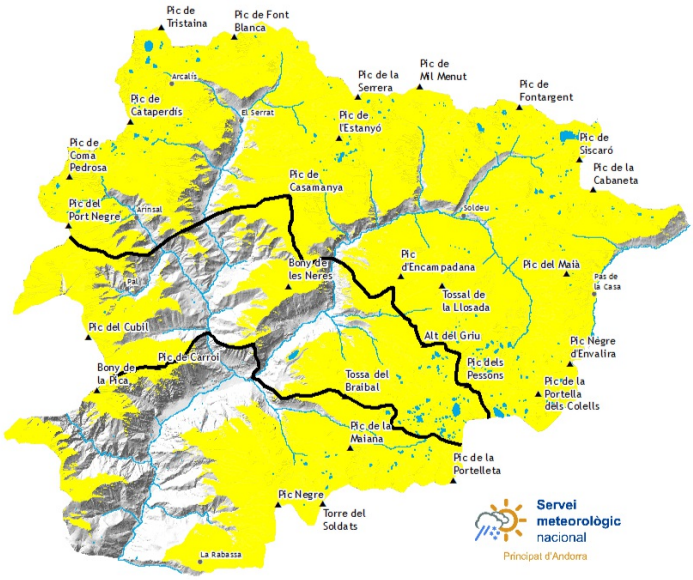

CALIDAD DE LA NIEVE

Con la intensificación de la precipitación, por debajo de los 2200 m aproximadamente son probables avalanchas de nieve húmeda. Estos pueden desencadenarse de manera natural y alcanzar un tamaño mediano. Además son de esperar aludes de deslizamiento basal en cualquier momento. En cotas altas :. El viento del sudeste transportará la nieve reciente. Con la nieve reciente y el viento las placas de viento aumentarán de tamaño ligeramente. Además son posibles algunas avalanchas de placa húmeda de tamaño pequeño. Estos lugares están parcialmente cubiertos de nieve reciente y resultan difíciles de reconocer. Los lugares peligrosos son resultan difíciles de reconocer con poca visibilidad.

ESTABILIDAD DEL MANTO NIVOSO

Caerá lluvia hasta en cotas altas especialmente en los sudeste. Caerán localmente hasta 15 cm de nieve por encima de los 2000 m aproximadamente. El enfriamiento nocturno será reducido. Los espesores de nieve varían mucho por encima de los 2100 m aproximadamente por la influencia del viento. Evitar las zonas con grietas de deslizamiento basal. Sábado :. El tiempo será parcialmente soleado.

ESPESORES DEL MANTO NIVOSO FUERA DE PISTA

Zona norte		Espesor nieve		
Manto Nival		1500m	2000m	2500m
N	1600 m	0 cm	150 cm	200 cm
S	1900 m	0 cm	100 cm	150 cm

zona centro		Espesor nieve		
Manto Nival		1500m	2000m	2500m
N	1600 m	0 cm	150 cm	200 cm
S	1900 m	0 cm	100 cm	150 cm

Zona sur		Espesor nieve		
Manto Nival		1500m	2000m	2500m
N	1600 m	0 cm	120 cm	150 cm
S	1900 m	0 cm	60 cm	100 cm

Govern d'Andorra

Aquest butlletí ha estat elaborat seguint les normes i recomanacions de l'**European Avalanche Warning Services**, del qual el **Servei meteorològic Nacional** n'és membre

BUTLLETÍ DEL PERILL D'ALLAUS DEL PRINCIPAT D'ANDORRA

Servei meteorològic nacional
Principat d'Andorra

Información detallada por espacios naturales protegidos

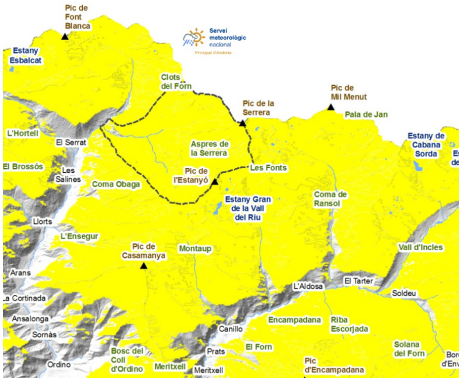

SORTENY

Continuarán las débiles precipitaciones con barro y una cota de nieve en torno a los 2000 m, que humidificarán el manto en todas las orientaciones, por debajo de esta cota; mientras que por encima se podrán formar débiles acumulaciones de unos 5 cm en este sector. En altura, el viento podrá transportar la poca nieve disponible y formar pequeñas acumulaciones irregulares.

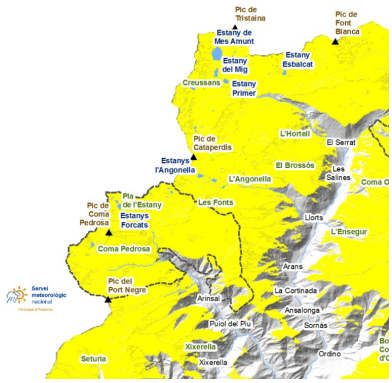

COMAPEDROSA

En el acceso desde Arinsal cada vez cae menos nieve, y las lluvias previstas retrasarán aún más la línea continua de nieve. Mientras duren las precipitaciones, la escasa visibilidad desaconseja las excursiones al Parque, pero una vez finalizadas se pueden realizar numerosas excursiones manteniendo siempre una cuidadosa elección del itinerario. , , ,

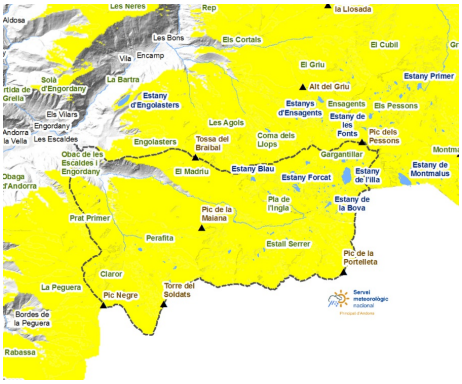

MADRIU-PERAFITA-CLAROR

El manto es en general delgado e irregular, con mejor continuidad de nieve en las vertientes norte y umbrías. Fue el sector más afectado por las precipitaciones del jueves, aunque en algunos lugares elevados el viento ha dejado la nieve vieja al descubierto. Hasta el sábado continuará siendo el sector con más precipitaciones y, por tanto, donde prevemos la mayor actividad.

Govern d'Andorra

EAWS
EUROPEAN AVALANCHE WARNING SERVICES

Aquest butlletí ha estat elaborat seguint les normes i recomanacions de l'**European Avalanche Warning Services**, del qual el **Servei meteorològic Nacional** n'és membre

BUTLLETÍ DEL PERILL D'ALLAUS DEL PRINCIPAT D'ANDORRA

Servei meteorològic nacional
Principat d'Andorra

Espesores de nieve nueva de los últimos días (de las ultimas 24h mesurado a las 06:00h UTC)

	02/03/2026	03/03/2026	04/03/2026	05/03/2026
FEDA (Central)	0 cm	0 cm	0 cm	0 cm
Engolasters - FEDA	0 cm	0 cm	0 cm	0 cm
Bony de les Neres	0 cm	0 cm	0 cm	0 cm
Sorteny	0 cm	0 cm	3 cm	10 cm
Les Fonts d'Arinsal	0 cm	4 cm	0 cm	10 cm
Perafita	0 cm	4 cm	3 cm	26 cm
Tossa Espiolets	0 cm	2 cm	0 cm	17 cm
Grau Roig - FEDA	0 cm	0 cm	0 cm	3 cm
Fontverd	0 cm	0 cm	0 cm	0 cm
Ransol - FEDA	0 cm	0 cm	0 cm	0 cm
Setúria	0 cm	0 cm	0 cm	0 cm
Caborreu	0 cm	0 cm	0 cm	0 cm
La Solana	0 cm	0 cm	0 cm	10 cm
Coll Pa	0 cm	0 cm	0 cm	9 cm
Envalira Antenes	0 cm	4 cm	0 cm	1 cm
Vall del Riu FEDA	0 cm	3 cm	0 cm	9 cm