BUTLLETÍ DEL PERILL D'ALLAUS DEL PRINCIPAT D'ANDORRA

Préparé le 06/03/2026 16:00
Prochaine mise à jour le 07/03/2026 à 16h

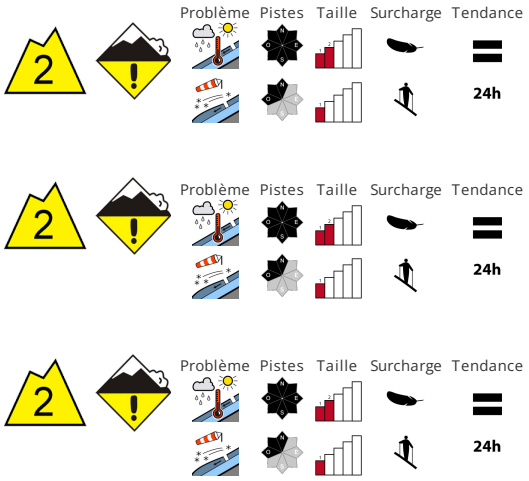

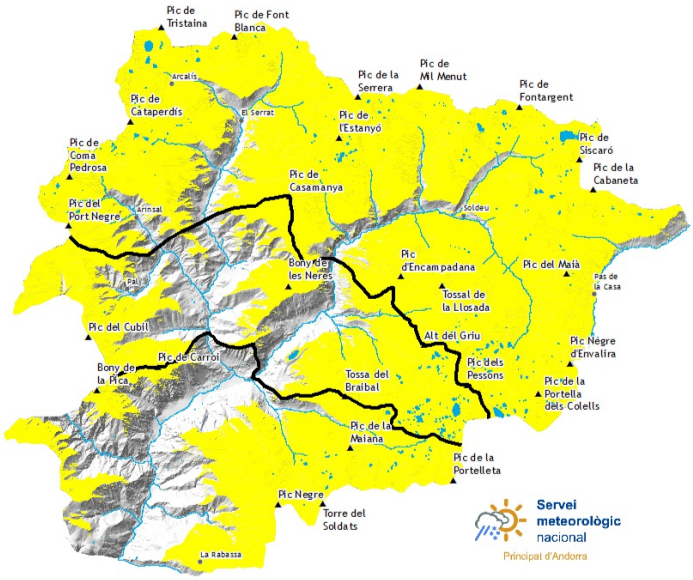

STABILITÉ DU MANTEAU NEIGEUX

Avec l'intensification des précipitations des avalanches humides sont à attendre en dessous d'environ 2200 m. Explication: celles-ci ne peut signifier que celles-ci avalanches peuvent se déclencher spontanément et atteindre une taille moyenne.. En outre, des avalanches de glissement sont à attendre à tout moment.. À haute altitude (-):. Le vent du sud-est transporte la neige fraîche.. Les accumulations de neige soufflée se développent encore un peu avec la neige fraîche et le vent. En outre , quelques avalanches de plaque de neige humide de petite taille sont possibles. Ces endroits sont en partie couverts de neige fraîche, et difficilement identifiables.. Les endroits dangereux sont à peine identifiables par mauvaise visibilité..

QUALITÈ DE LA NEIGE

Il tombe de la pluie jusqu'à haute altitude spécialement au sud-est. Il tombe au-dessus d'environ 2000 m localement jusqu'à 15 cm de neige. Le rayonnement nocturne est réduit.. On trouve suivant l'influence du vent des hauteurs de neiges très différentes au-dessus d'environ 2100 m. Les zones présentant des fissures de glissement doivent être évitées.. Samedi (-):. Il fait un temps partiellement ensoleillé.

EPAISSEUR DE NEIGE HORS PISTE

Zone nord		Epaisseur de neige		
Nival manteau		1500m	2000m	2500m
N	1600 m	0 cm	150 cm	200 cm
S	1900 m	0 cm	100 cm	150 cm

Zone centre		Epaisseur de neige		
Nival manteau		1500m	2000m	2500m
N	1600 m	0 cm	150 cm	200 cm
S	1900 m	0 cm	100 cm	150 cm

Zone sud		Epaisseur de neige		
Nival manteau		1500m	2000m	2500m
N	1600 m	0 cm	120 cm	150 cm
S	1900 m	0 cm	60 cm	100 cm

Govern d'Andorra

EAWS EUROPEAN AVALANCHE WARNING SERVICES

Aquest butlletí ha estat elaborat seguint les normes i recomanacions de l'**European Avalanche Warning Services**, del qual el **Servei meteorològic Nacional** n'és membre

BUTLLETÍ DEL PERILL D'ALLAUS DEL PRINCIPAT D'ANDORRA

Servei meteorològic nacional
Principat d'Andorra

Des informations détaillées par espace naturel protégé

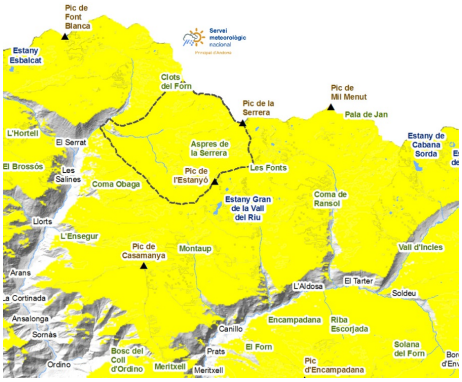

SORTENY

De faibles précipitations avec de la boue et un niveau de neige autour de 2000 m se poursuivront, ce qui humidifiera le manteau dans toutes les directions, en dessous de ce niveau ; tandis que de faibles accumulations d'environ 5 cm pourraient se former en amont dans ce secteur. En altitude, le vent pourra transporter le peu de neige disponible et former de petites accumulations irrégulières. , , , , ,

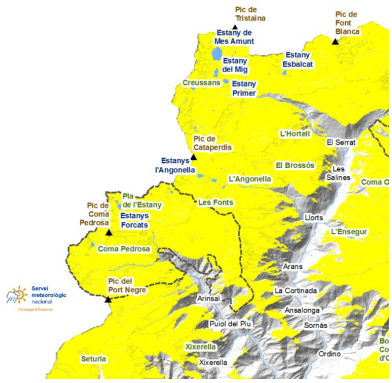

COMAPEDROSA

L'accès depuis Arinsal reçoit de moins en moins de neige, et la pluie prévue retardera encore davantage la ligne de neige continue. Tant que les précipitations durent, la mauvaise visibilité rend les excursions au Parc déconseillées, mais une fois celles-ci terminées, de nombreuses excursions peuvent être réalisées, en gardant toujours un choix attentif de l'itinéraire. , , ,

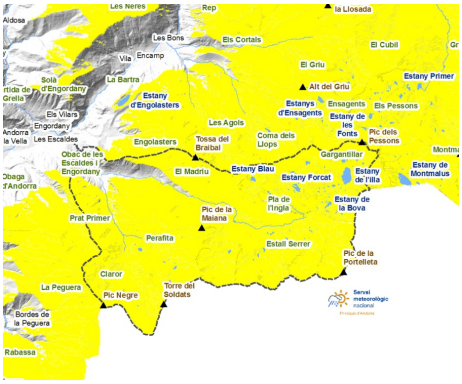

MADRIU-PERAFITA-CLAROR

Le manteau est généralement mince et irrégulier, avec une meilleure continuité neigeuse sur les versants nord et obscurs. Il s'agit du secteur le plus touché par les précipitations de jeudi, même si, dans certains endroits élevés, le vent a laissé la vieille neige exposée. Jusqu'à samedi, ce sera le secteur avec le plus de précipitations et donc celui où l'on prévoit la plus grande activité. , , , , ,

Govern d'Andorra

EAWS
EUROPEAN AVALANCHE WARNING SERVICES

Aquest butlletí ha estat elaborat seguint les normes i recomanacions de l'**European Avalanche Warning Services**, del qual el **Servei meteorològic Nacional** n'és membre

BUTLLETÍ DEL PERILL D'ALLAUS DEL PRINCIPAT D'ANDORRA

Servei meteorològic nacional
Principat d'Andorra

Couche de neige fraiche des derniers jours (De 24 h mesurée à 06:00 h UTC)

	02/03/2026	03/03/2026	04/03/2026	05/03/2026
FEDA (Central)	0 cm	0 cm	0 cm	0 cm
Engolasters - FEDA	0 cm	0 cm	0 cm	0 cm
Bony de les Neres	0 cm	0 cm	0 cm	0 cm
Sorteny	0 cm	0 cm	3 cm	10 cm
Les Fonts d'Arinsal	0 cm	4 cm	0 cm	10 cm
Perafita	0 cm	4 cm	3 cm	26 cm
Tossa Espiolets	0 cm	2 cm	0 cm	17 cm
Grau Roig - FEDA	0 cm	0 cm	0 cm	3 cm
Fontverd	0 cm	0 cm	0 cm	0 cm
Ransol - FEDA	0 cm	0 cm	0 cm	0 cm
Setúria	0 cm	0 cm	0 cm	0 cm
Caborreu	0 cm	0 cm	0 cm	0 cm
La Solana	0 cm	0 cm	0 cm	10 cm
Coll Pa	0 cm	0 cm	0 cm	9 cm
Envalira Antenes	0 cm	4 cm	0 cm	1 cm
Vall del Riu FEDA	0 cm	3 cm	0 cm	9 cm