MINISTERO DELLA DIFESA

meteomont
Servizio Nazionale di previsione neve e valanghe

EAWS EUROPEAN AVALANCHE WARNING SERVICES

CARABINIERI

AERONAUTICA MILITARE SERVIZIO METEOROLOGICO

# ALPI GIULIE

Bollettino Valanghe N. 366/2026 del 06/03/2026 ore 14.00
Validità 48 ore prossima emissione 07/03/2026

**A cura del Servizio METEOMONT dell'ARMA dei CARABINIERI**
**In collaborazione con Servizio Meteorologico dell'Aeronautica militare**

## SITUAZIONE alle 14:00 del 06/03/2026

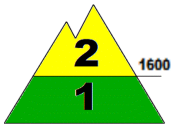


**SITUAZIONE TIPO: passaggio da poca a molta neve.**




**SITUAZIONE TIPO: situazione primaverile.**

| Quota neve (mslm) | Nord | Sud |
|---|---|---|
| | 800 - 900 | 1300 - 1700 |

| Altezza Neve (cm) | Neve al suolo | Neve Fresca | Quota (mslm) |
|---|---|---|---|
| | 95 | 000 | 1750 |
| | 78 | 00 | 1130 |

**VALANGHE OSSERVATE: Nessuna valanga.**

## PREVISIONI 07/03/2026

## GRADO DI PERICOLO: MODERATO 2

## SITUAZIONE TIPO: passaggio da poca a molta neve.

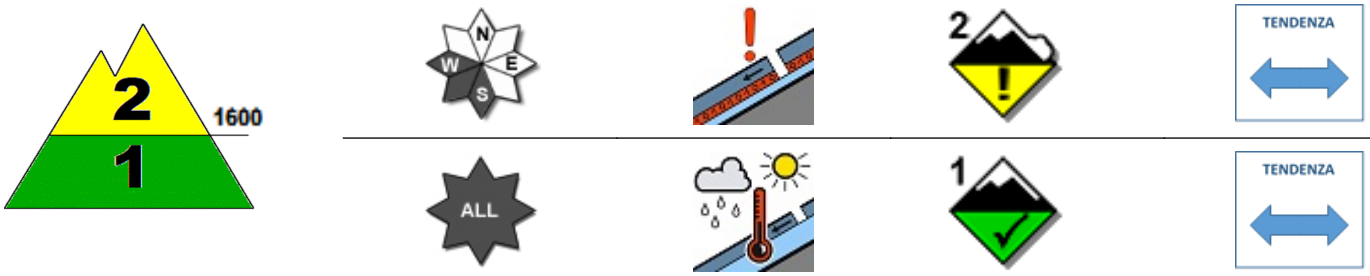


## SITUAZIONE TIPO: situazione primaverile.

**MANTO NEVOSO: La stabilità del manto nevoso è scarsa su alcuni punti (aree) per versanti sud occidentali al di sopra di 1600 mslm, possibili valanghe di dimensioni medie.**
**La stabilità del manto nevoso è discreta su pochi punti (aree) per tutte le esposizioni al di sotto di 1600 mslm, possibili valanghe di dimensioni piccole.**

## AVVERTENZE

Il rialzo termico diurno richiede un'attenta valutazione temporale dell'escursione che eviti l'attraversamento di pendii ripidi nelle ore più calde della giornata.

## SCALA EUROPEA DEL GRADO DI PERICOLO VALANGHE

## LEGENDA PROBLEMA

**Bollettino realizzato su scala sinottica-regionale (standard EAWS). La sua valutazione non può escludere in alcun modo la necessità di una seria e capace valutazione locale del pericolo (singolo pendio) che può essere anche sensibilmente diverso. Le previsioni meteorologiche sono relative all'orario UTC (per l'Italia +1 in inverno e +2 in estate).**

# ALPI GIULIE

## PREVISIONE METEO

| Quota | | 07/03/2026 h6:00 | 07/03/2026 h12:00 | 07/03/2026 h18:00 |
|---|---|---|---|---|
| 1000 | Venti | 00 Calma | 01 Nodi da S-Ovest | 02 Nodi da S-Ovest |
| | Temperature | +03 °C | +05 °C | +02 °C |
| | Temp.percepita | 3 °C | 5 °C | 2 °C |
| 2000 | Venti | 03 Nodi da S-Ovest | 02 Nodi da S-Ovest | 01 nodi da Ovest |
| | Temperature | +01 °C | +01 °C | +02 °C |
| | Temp.percepita | -1 °C | 1 °C | 2 °C |
| 3000 | Venti | 02 nodi da N-Ovest | 02 Nodi da Nord | 03 Nodi da N-Est |
| | Temperature | -02 °C | -02 °C | -02 °C |
| | Temp.percepita | -2 °C | -2 °C | -4 °C |
| Zero termico | | 1100-1300 m. | 2500-2700 m. | 2200-2400 m. |
| Fenomeno | | — | — | — |
| Stato del cielo | | | | |

## LEGENDA FENOMENI

— Assenza Fenomeni · Nebbia · Foschia · Pioggia debole · Pioggia moderata · Pioggia forte · Temporali

Nevicata debole · Nevicata moderata · Nevicata forte

## STATO DEL CIELO

Sereno · Poco nuvoloso · Nuvoloso · Molto nuvoloso · Coperto

## Parametri meteonivometrici registrati presso i campi di rilevamento il 06/03/2026.

| Località | Comune | Quota (m.s.l.m.) | Altezza neve (cm) | Neve caduta nelle 24 ore (cm) | Temp. Min (°C) | Temp. Max (°C) | Condizioni del tempo |
|---|---|---|---|---|---|---|---|
| MONTE LUSSARI | Tarvisio (UD) | 1750 | 95 | 0 | -2 | +12 | Assenza di precipitazioni |
| PASSO PREDIL | Tarvisio (UD) | 1130 | 78 | 0 | -2 | +7 | Assenza di precipitazioni |

(*) Rilievi fuori campo

**L'INFORMAZIONE E' PREVENZIONE - LEGGI L'ATTUALE GRADO DI PERICOLO VALANGHE!**

IL CAPO DEL CENTRO NAZIONALE METEOMONT
(Ten. Col. RFI Emanuela Gini)
FIRMA AUTOGRAFA OMESSA AI SENSI
DELL'ART.3 DEL D.LGS N.39/1993

Bollettino realizzato su scala sinottica-regionale (standard EAWS). La sua valutazione non può escludere in alcun modo la necessità di una seria e capace valutazione locale del pericolo (singolo pendio) che può essere anche sensibilmente diverso. Le previsioni meteorologiche sono relative all'orario UTC (per l'Italia +1 in inverno e +2 in estate).