# ALPI MARITTIME

Bollettino Valanghe N. 365/2026 del 06/03/2026 ore 14.00
Validità 48 ore prossima emissione 07/03/2026
**A cura del Servizio METEOMONT dell'ARMA dei CARABINIERI**
**In collaborazione con Servizio Meteorologico dell'Aeronautica militare**

## SITUAZIONE alle 14:00 del 06/03/2026

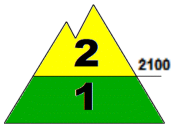


**SITUAZIONE TIPO: passaggio da poca a molta neve.**




**SITUAZIONE TIPO: situazione primaverile.**

| Quota neve (mslm) | Nord | Sud |
|---|---|---|
| | 900 - 1100 | 1400 - 1600 |

| Altezza Neve (cm) | Neve al suolo | Neve Fresca | Quota (mslm) |
|---|---|---|---|
| | 121 | 0 | 2305 |
| | 82 | 0 | 1680 |

**VALANGHE OSSERVATE: -.**

## PREVISIONI 07/03/2026

## GRADO DI PERICOLO: MODERATO 2

## SITUAZIONE TIPO: passaggio da poca a molta neve.

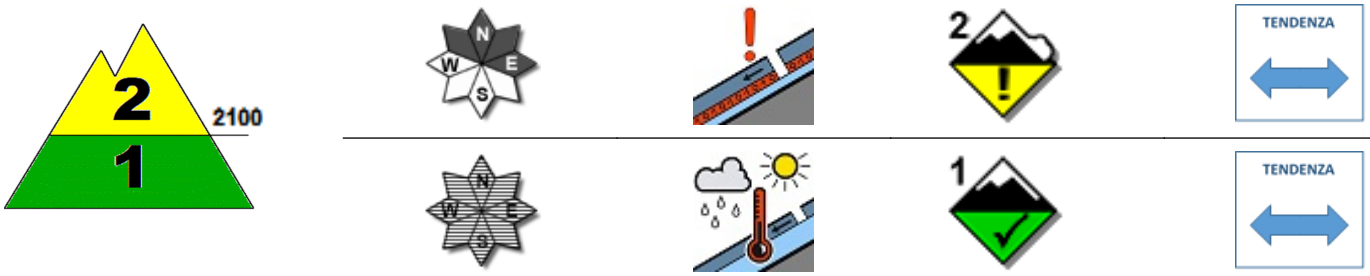


## SITUAZIONE TIPO: situazione primaverile.

**MANTO NEVOSO: La stabilità del manto nevoso è scarsa su alcuni punti (aree) per versanti in ombra al di sopra di 2100 mslm, possibili valanghe di dimensioni medie.**
**La stabilità del manto nevoso è discreta su pochi punti (aree) per isolati pendii al di sotto di 2100 mslm, possibili valanghe di dimensioni medie.**

## AVVERTENZE

Meteomont ricorda ARTVA, pala e sonda sempre al seguito.

## SCALA EUROPEA DEL GRADO DI PERICOLO VALANGHE

## LEGENDA PROBLEMA

**Bollettino realizzato su scala sinottica-regionale (standard EAWS). La sua valutazione non può escludere in alcun modo la necessità di una seria e capace valutazione locale del pericolo (singolo pendio) che può essere anche sensibilmente diverso. Le previsioni meteorologiche sono relative all'orario UTC (per l'Italia +1 in inverno e +2 in estate).**

MINISTERO DELLA DIFESA

meteomont
Servizio Nazionale di previsione neve e valanghe

EAWS EUROPEAN AVALANCHE WARNING SERVICES

CARABINIERI

# ALPI MARITTIME

## PREVISIONE METEO

| Quota | | 07/03/2026 h6:00 | 07/03/2026 h12:00 | 07/03/2026 h18:00 |
|---|---|---|---|---|
| 1000 | Venti | 01 Nodi da Sud | 01 Nodi da S-Ovest | 02 Nodi da S-Ovest |
| | Temperature | +05 °C | +05 °C | +05 °C |
| | Temp.percepita | 5 °C | 5 °C | 5 °C |
| 2000 | Venti | 04 Nodi da Nord | 02 Nodi da N-Est | 02 Nodi da N-Est |
| | Temperature | -01 °C | +00 °C | +01 °C |
| | Temp.percepita | -4 °C | 0 °C | 1 °C |
| 3000 | Venti | 06 Nodi da Est | 06 Nodi da S-Est | 04 Nodi da S-Est |
| | Temperature | -06 °C | -05 °C | -05 °C |
| | Temp.percepita | -11 °C | -10 °C | -8 °C |
| Zero termico | | 1800-2000 m. | 1800-2000 m. | 2000-2200 m. |
| Fenomeno | | — | — | — |
| Stato del cielo | | | | |

## LEGENDA FENOMENI

— Assenza Fenomeni · Nebbia · Foschia · Pioggia debole · Pioggia moderata · Pioggia forte · Temporali

Nevicata debole · Nevicata moderata · Nevicata forte

## STATO DEL CIELO

Sereno · Poco nuvoloso · Nuvoloso · Molto nuvoloso · Coperto

## Parametri meteonivometrici registrati presso i campi di rilevamento il 06/03/2026.

| Località | Comune | Quota (m.s.l.m.) | Altezza neve (cm) | Neve caduta nelle 24 ore (cm) | Temp. Min (°C) | Temp. Max (°C) | Condizioni del tempo |
|---|---|---|---|---|---|---|---|
| STREPEIS | Vinadio (CN) | 1320 | 98 | 0 | +1 | +11 | Assenza di precipitazioni |

(*) Rilievi fuori campo

**L'INFORMAZIONE E' PREVENZIONE - LEGGI L'ATTUALE GRADO DI PERICOLO VALANGHE!**

IL CAPO DEL CENTRO NAZIONALE METEOMONT
(Ten. Col. RFI Emanuela Gini)
FIRMA AUTOGRAFA OMESSA AI SENSI
DELL'ART.3 DEL D.LGS N.39/1993

Bollettino realizzato su scala sinottica-regionale (standard EAWS). La sua valutazione non può escludere in alcun modo la necessità di una seria e capace valutazione locale del pericolo (singolo pendio) che può essere anche sensibilmente diverso. Le previsioni meteorologiche sono relative all'orario UTC (per l'Italia +1 in inverno e +2 in estate).