Bulletin d'estimation du risque d'avalanche
(valable en dehors des pistes balisées et ouvertes)

MASSIF : Mercantour

Rédigé le vendredi 6 mars 2026 à 15h

Estimation des risques pour le : SAMEDI 07 MARS

MANTEAU NEIGEUX BIEN STABILISÉ

1

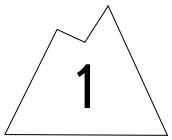

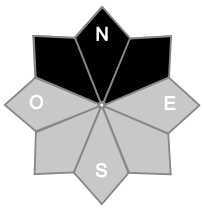

Indice de risque faible.

Départs spontanés : peu probables

Déclenchements provoqués : très rares

Indices de risque : 5 très fort - 4 fort - 3 marqué - 2 limité - 1 faible -- En noir : les pentes les plus dangereuses

Stabilité du manteau neigeux

Situation avalancheuse typique : pas de situation prédominante

Déclenchements provoqués : le manteau neigeux est bien stabilisé. Les instabilités se cantonnent à de très rares pentes d'altitude supérieure à 2200 m environ, en orientations nord-ouest, nord ou nord-est. Plaques très dures et difficilement déclenchables par un seul skieur.

Départs spontanés : peu probables

Qualité de la neige

Enneigement proche des normales pour un début mars.
Données observées : 136 cm à la nivôse de Millefonts à 2430 m.

Enneigement skiable : vers 1400/1500 m en ubacs, 1800/1900 m en adrets peu pentus.

État de la neige en surface : manteau neigeux printanier dense en adrets, ainsi qu'en ubacs de basse altitude. Samedi matin, le regel reste inexistant ou médiocre sous 2000/2200 m, et l'absence d'ensoleillement empêche l'humidification en adrets. Neige sèche fortement durcie par le vent en ubacs de haute altitude. Sur les crêtes, d'anciennes corniches épaisses côtoient des zones dégarnies par le vent. La neige est parfois légèrement colorée en ocre par le dépôt de poussières désertiques sahariennes.

Aperçu météo pour le samedi 07 mars

Couvert, vent d'est modéré à haute altitude et près de l'Italie.

	nuit	matin	après-midi	soir
Pluie-Neige				
Iso 0 °C	2 300 m	2 300 m	2 300 m	2 300 m
Vent 2000 m	30 km/h	25 km/h	20 km/h	15 km/h
Vent 3000 m	35 km/h	30 km/h	25 km/h	20 km/h

Épaisseur de neige hors-piste

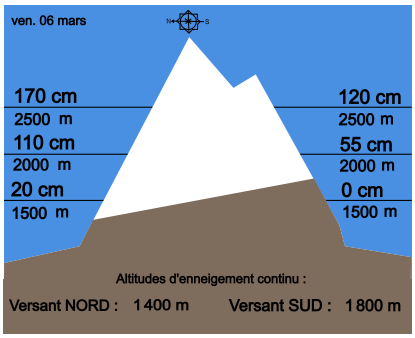

Précipitations à 1800 m

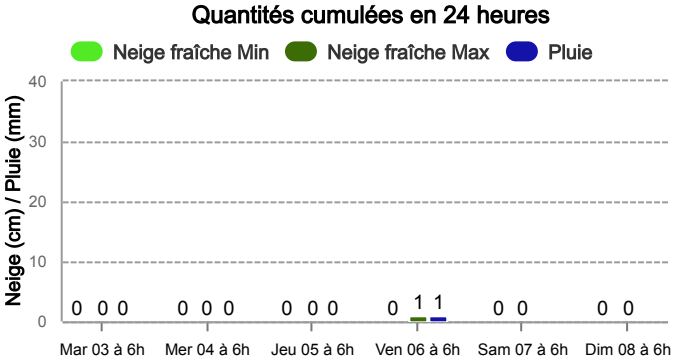

Tendance du dimanche 08 mars

1

Indice de risque faible

Peu d'évolution de la situation nivologique.
Risque faible.

Pour consulter la vigilance en cours, veuillez vous rendre sur le site https://vigilance.meteofrance.fr/fr

Météo-France - 73 avenue de Paris, 94165 Saint-Mandé cedex - Contact : contact@meteo.fr

Rédigé par Météo-France avec la contribution des observateurs du réseau nivo-météorologiques. Partenariat : ANMSM (Maires de Stations de Montagne), DSF (Domaines Skiables de France), ADSP (Directeurs de Pistes et de la Sécurité des Stations de Sports d'Hiver) et autres acteurs de la montagne.

Bulletin neige & avalanches par téléphone au
0 892 68 10 20 Service 0,35 € / min + prix appel

RÉPUBLIQUE FRANÇAISE
Liberté Égalité Fraternité

METEO FRANCE
À VOS CÔTÉS, DANS UN CLIMAT QUI CHANGE

Bulletin d'estimation du risque d'avalanche
(valable en dehors des pistes balisées et ouvertes)

MASSIF : Mercantour

Rédigé le vendredi 6 mars 2026 à 15h

Conditions nivo-météo des 7 derniers jours

	sam. 28/02				dim. 01/03				lun. 02/03				mar. 03/03				mer. 04/03				jeu. 05/03				ven. 06/03			
	03h	09h	15h	21h	03h	09h	15h	21h	03h	09h	15h	21h	03h	09h	15h	21h	03h	09h	15h	21h	03h	09h	15h	21h	03h	09h	15h	21h
Météo																												
Vent (km/h)	15	20	25	15	15	20	20	20	15	15	15	10	15	10	10	10	10	10	10	5	10	15	20	35	50	45	40	35
à 3000m																												
Vent (km/h)	5	10	15	5	5	5	15	10	5	10	15	10	10	10	15	10	10	10	10	10	15	20	25	35	30	30	30	30
à 2000m																												

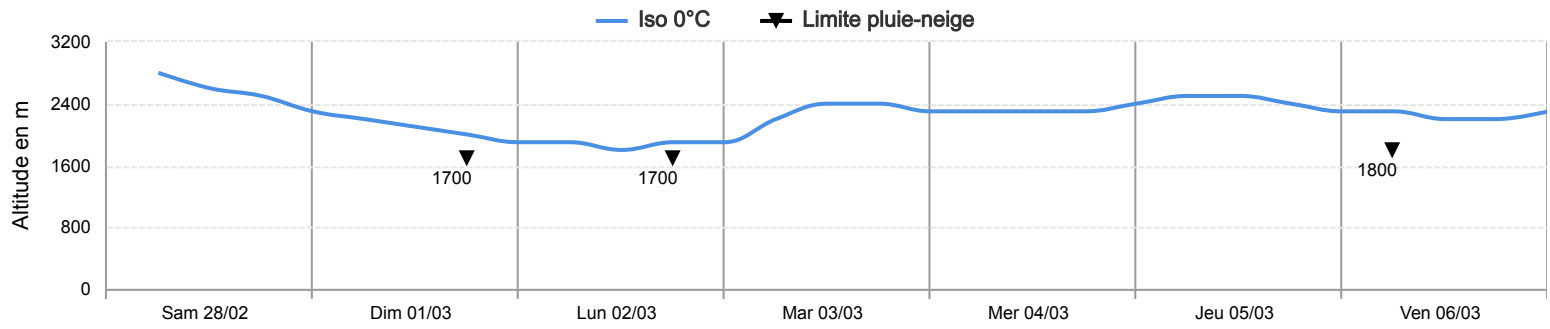

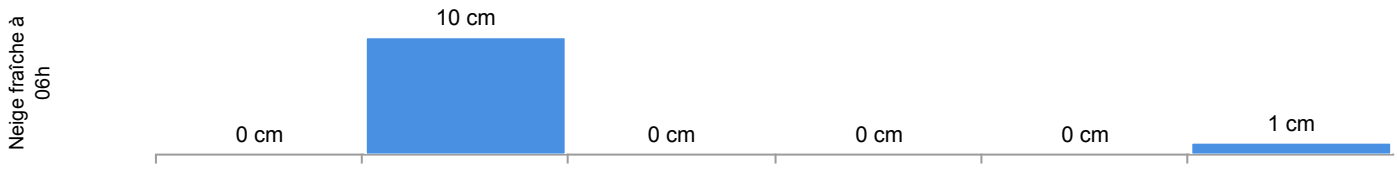

Risque d'avalanche	sam. 28/02	dim. 01/03	lun. 02/03	mar. 03/03	mer. 04/03	jeu. 05/03	ven. 06/03
	2	2	2	2	2	2	2

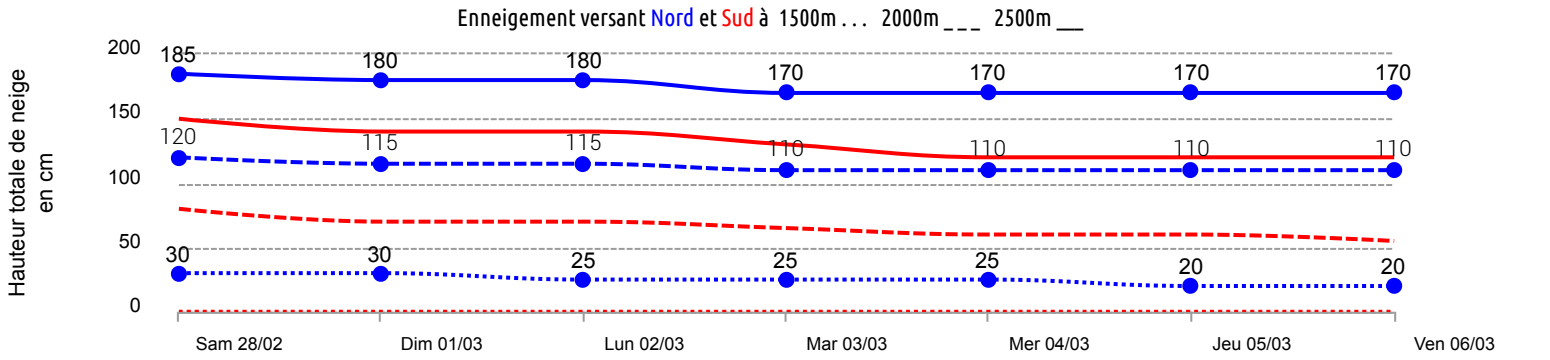

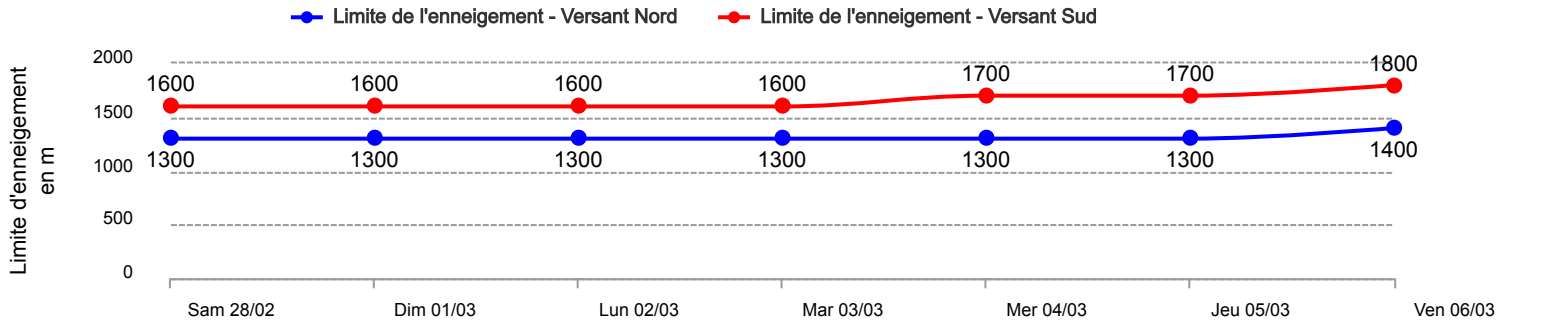

Pour consulter la vigilance en cours, veuillez vous rendre sur le site https://vigilance.meteofrance.fr/fr

Météo-France - 73 avenue de Paris, 94165 Saint-Mandé cedex - Contact : contact@meteo.fr

Bulletin neige & avalanches par téléphone au 0 892 68 10 20 Service 0,35 € / min + prix appel

Rédigé par Météo-France avec la contribution des observateurs du réseau nivo-météorologiques. Partenariat : ANMSM (Maires de Stations de Montagne), DSF (Domaines Skiables de France), ADSP (Directeurs de Pistes et de la Sécurité des Stations de Sports d'Hiver) et autres acteurs de la montagne.