Bulletin d'estimation du risque d'avalanche

(valable en dehors des pistes balisées et ouvertes)

MASSIF : Ubaye

Rédigé le vendredi 6 mars 2026 à 15h

Estimation des risques pour le : SAMEDI 07 MARS

MANTEAU NEIGEUX BIEN STABILISÉ, SAUF ÉVENTUELLEMENT EN UBACS D'ALTITUDE

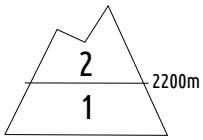

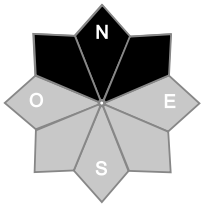

Au-dessus de 2200m indice de risque limité, plus bas indice faible.

Départs spontanés : peu probables

Déclenchements provoqués : instabilités rares et difficilement déclenchables, mais pouvant être volumineuses

Indices de risque : 5 très fort - 4 fort - 3 marqué - 2 limité - 1 faible -- En noir : les pentes les plus dangereuses

Stabilité du manteau neigeux

Situation avalancheuse typique : couche fragile persistante

Déclenchements provoqués : le manteau neigeux est bien stabilisé. Les instabilités se cantonnent à de rares pentes d'altitude supérieure à 2200 m environ, en orientations nord-ouest, nord et nord-est. Elles se présentent sous forme de plaques dures. Difficilement déclenchables par un seul skieur, elles peuvent cependant mobiliser d'importants volumes en cas de départ (taille 2, voire 3, grande, non exclue), car elles reposent sur une couche fragile persistante vers la base du manteau neigeux qui peut conduire à des cassures épaisses et larges.

Départs spontanés : peu probables, sauf éventuellement une avalanche de glissement de taille 2 en pentes d'un large secteur sud, en terrain favorable (pentes herbeuses, dalles rocheuses).

Qualité de la neige

Enneigement proche des normales pour un début mars.
Données observées : 65 cm à la Nivôse de Restefond à 2550 m (secteur venté), 88 cm au-dessus de Larche à 2270 m en adret.

Enneigement skiable : vers 1500 m en ubacs, 1900/2000 m en adrets peu pentus.

État de la neige en surface : manteau neigeux printanier dense en adrets, ainsi qu'en ubacs de basse altitude. Samedi matin, le regel reste inexistant ou médiocre sous 2000/2200 m, et l'absence d'ensoleillement empêche l'humidification en adrets. Neige sèche fortement durcie par le vent en ubacs de haute altitude, au-dessus de 2200/2300 m, plus rarement en vieille neige d'aspect poudreux dans les pentes et combes abritées. Sur les crêtes, d'anciennes corniches épaisses côtoient des zones dégarnies par le vent. La neige est parfois légèrement colorée en ocre par le dépôt de poussières désertiques sahariennes.

Aperçu météo pour le samedi 07 mars

	nuit	matin	après-midi	soir
	Couvert, vent d'est modéré à haute altitude et près de l'Italie.			
Pluie-Neige				
Iso 0 °C	2 400 m	2 300 m	2 300 m	2 300 m
Vent 2000 m	25 km/h	25 km/h	20 km/h	15 km/h
Vent 3000 m	40 km/h	30 km/h	25 km/h	20 km/h

Épaisseur de neige hors-piste

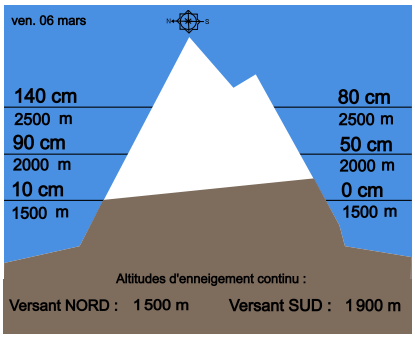

Précipitations à 1800 m

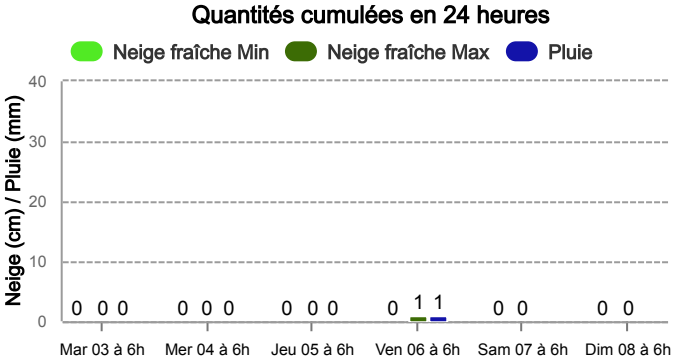

Tendance du dimanche 08 mars

Indice de risque limité

Peu d'évolution de la situation nivologique.
Risque limité aux ubacs de haute altitude.

Pour consulter la vigilance en cours, veuillez vous rendre sur le site https://vigilance.meteofrance.fr/fr

Météo-France - 73 avenue de Paris, 94165 Saint-Mandé cedex - Contact : contact@meteo.fr

Rédigé par Météo-France avec la contribution des observateurs du réseau nivo-météorologiques. Partenariat : ANMSM (Maires de Stations de Montagne), DSF (Domaines Skiables de France), ADSP (Directeurs de Pistes et de la Sécurité des Stations de Sports d'Hiver) et autres acteurs de la montagne.

Bulletin neige & avalanches par téléphone au
0 892 68 10 20 Service 0,35 € / min + prix appel

RÉPUBLIQUE FRANÇAISE
Liberté Égalité Fraternité

METEO FRANCE
À VOS CÔTÉS, DANS UN CLIMAT QUI CHANGE

Bulletin d'estimation du risque d'avalanche
(valable en dehors des pistes balisées et ouvertes)

MASSIF : Ubaye

Rédigé le vendredi 6 mars 2026 à 15h

Conditions nivo-météo des 7 derniers jours

	sam. 28/02				dim. 01/03				lun. 02/03				mar. 03/03				mer. 04/03				jeu. 05/03				ven. 06/03			
	03h	09h	15h	21h	03h	09h	15h	21h	03h	09h	15h	21h	03h	09h	15h	21h	03h	09h	15h	21h	03h	09h	15h	21h	03h	09h	15h	21h
Météo																												
Vent (km/h)	10	20	20	15	20	20	20	20	10	15	15	10	10	10	10	10	10	10	10	10	20	20	30	45	60	60	50	45
à 3000m																												
Vent (km/h)	5	10	15	5	5	10	15	10	10	15	15	10	10	5	10	10	5	5	10	10	25	30	35	40	35	30	30	30
à 2000m																												

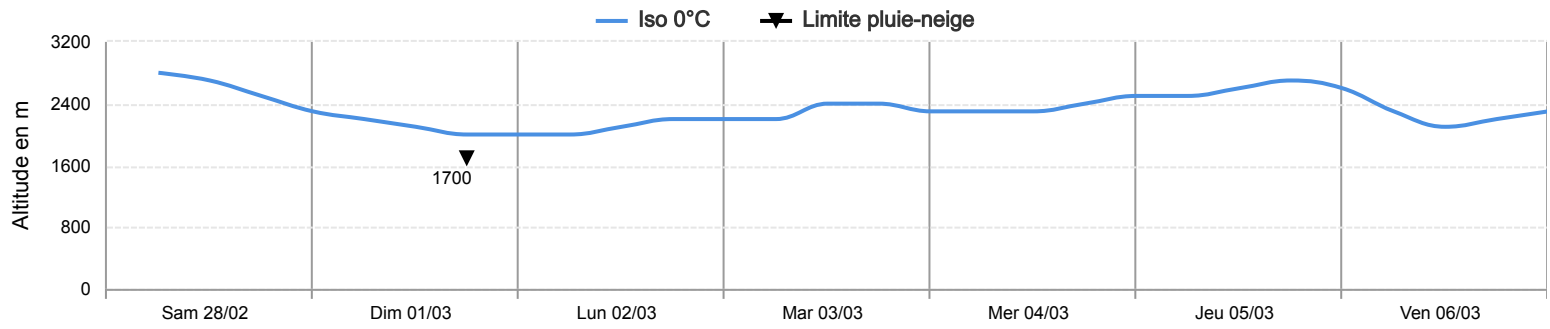

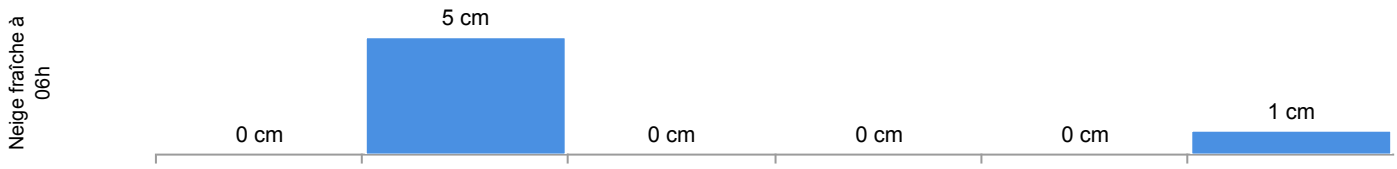

Risque d'avalanche	sam. 28/02	dim. 01/03	lun. 02/03	mar. 03/03	mer. 04/03	jeu. 05/03	ven. 06/03
	2	2	2	2	2	2	2

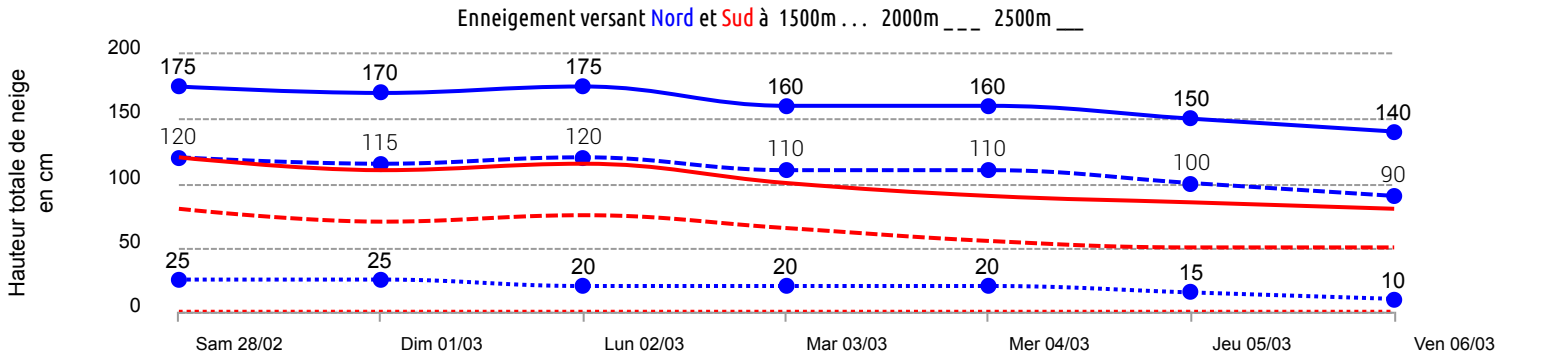

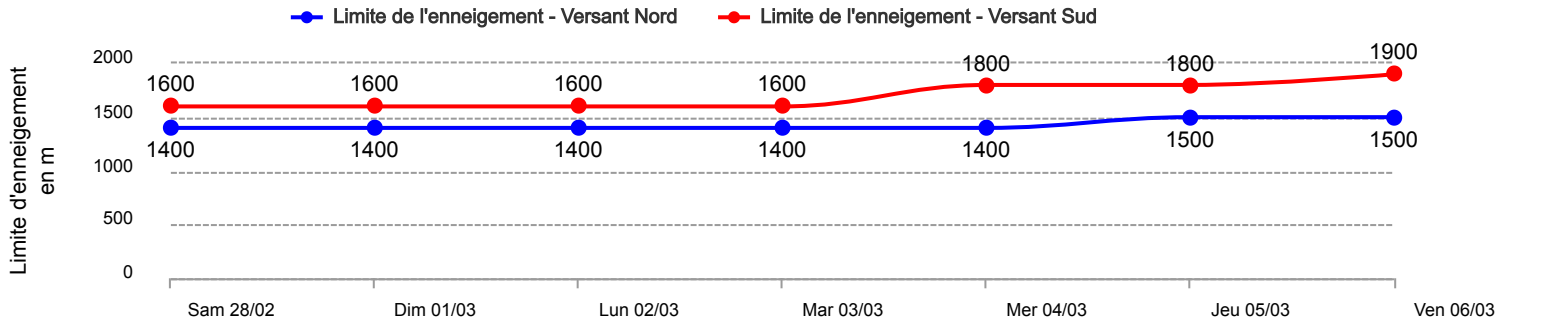

Pour consulter la vigilance en cours, veuillez vous rendre sur le site https://vigilance.meteofrance.fr/fr

Météo-France - 73 avenue de Paris, 94165 Saint-Mandé cedex - Contact : contact@meteo.fr

Rédigé par Météo-France avec la contribution des observateurs du réseau nivo-météorologiques. Partenariat : ANMSM (Maires de Stations de Montagne), DSF (Domaines Skiables de France), ADSP (Directeurs de Pistes et de la Sécurité des Stations de Sports d'Hiver) et autres acteurs de la montagne.

Bulletin neige & avalanches par téléphone au

0 892 68 10 20 Service 0,35 € / min + prix appel