# Bulletin d'estimation du risque d'avalanche
(valable en dehors des pistes balisées et ouvertes)

# MASSIF : Aure Louron

Rédigé le vendredi 6 mars 2026 à 16h

## Estimation des risques pour le : SAMEDI 07 MARS

**QUELQUES PLAQUES EN ALTITUDE, HUMIDIFICATION PLUS BAS.**

2

2

N O E S

Plaques et humide.

Indice de risque limité.

**Départs spontanés :** Ponctuels dans la neige humide, avalanches de fond possibles.

**Déclenchements provoqués :** Quelques plaques en altitude.

Indices de risque : 5 très fort - 4 fort - 3 marqué - 2 limité - 1 faible -- En noir : les pentes les plus dangereuses

## Stabilité du manteau neigeux

**Situation avalancheuse typique :** neige ventée neige humide

Déclenchements provoqués : **Au-dessus de 2200 à 2300m,** dans les pentes raides allant de l'Ouest vers le Nord-Est, quelques plaques à vent peuvent se former sous les chutes de neige et le vent de sud-est. Elles restent peu épaisses et peuvent reposer sur des couches fragiles enfouies, plus difficiles à déclencher à cause de leur profondeur. Leur déclenchement reste cependant possible dans les zones où le manteau neigeux est plus mince, rapprochant les couches fragiles de la surface (entrées de combes, ruptures de pentes...). Des avalanches moyennes sont attendues par déclenchement des plaques et par sollicitation de la couche fragile, parfois des grandes dans les zones d'accumulation plus importantes.
**Plus bas**, un simple skieur peut déclencher des avalanches dans la neige humide dans les pentes raides en toutes orientations dès le matin, de petites tailles, rarement moyennes.

Départs spontanés : **Au-dessus de 2200 à 2300m**, des départs ponctuels des plaques décrites ci-dessus restent possibles par surcharge par le vent, engendrant des avalanches moyennes, plus rarement grandes.
**Plus bas, sous 2200m**, des départs ponctuels dans la neige humide sont attendus dans les pentes raides et en toutes orientations dès le matin, avec la douceur et l'humidité présentes. Des avalanches petites à rarement moyennes sont possibles. Des avalanches de fond peuvent aussi se produire en toutes orientations, partant d'une zone d'accumulation en altitude et emportant l'intégralité du manteau. Des avalanches moyennes, parfois grandes sont possibles.
Signes parfois à observer : **gueules de baleine** (fissures qui s'ouvrent dans le manteau perpendiculairement à la pente). Trouées d'avalanche récentes jusqu'à l'herbe, à proximité.

## Qualité de la neige

**Enneigement** : La fonte reste faible en nord mais les versants sud se dégarnissent peu à peu, l'enneigement est bon au-dessus de 1800 m en nord mais bien irrégulièrement réparti, crêtes dégarnies en particulier à l'ouest, combes plus chargées et corniches restant souvent imposantes.
**Limites skiables** : à partir de 1600/1700 m.
**État de la neige** : Quelques centimètres de neige récente ce samedi dès 1700/1800m en journée, venant s'ajouter à ceux de la veille. Le manteau neigeux reste printanier en sud sous cette neige fraîche, c'est aussi le cas sous 2200/2300m en Nord. Au-dessus de 2200 à 2300m, dans les versants ombragés, alternance de neige sèche et de neige travaillée par le vent, état de la surface pouvant être irrégulier. La neige s'humidifie progressivement sous 2200m au fil de la journée.

## Aperçu météo pour le samedi 07 mars

Quelques averses de neige au-dessus de 1700/1800m surtout l'après-midi et en soirée, du vent de sud-est faible à modéré.

| | nuit | matin | après-midi | soir |
|---|---|---|---|---|
| **Pluie-Neige** | 1 700 m | 1 700 m | 1 900 m | 1 800 m |
| **Iso 0 °C** | 2 200 m | 2 100 m | 2 200 m | 2 000 m |
| **Vent 1500 m** | 10 km/h | 10 km/h | 20 km/h | 10 km/h |
| **Vent 3000 m** | 50 km/h | 40 km/h | 35 km/h | 30 km/h |

## Épaisseur de neige hors-piste

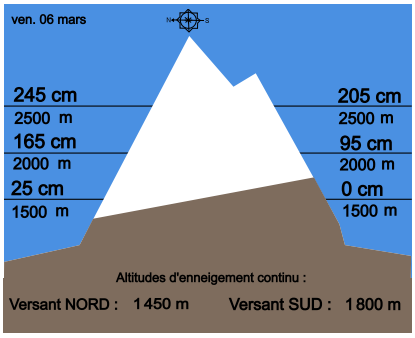


## Précipitations à 1800 m

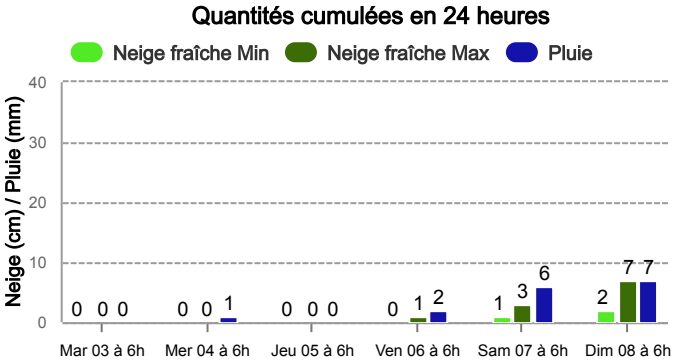


## Tendance du dimanche 08 mars

2

**Indice de risque limité**

Maintien du risque limité, quelques nouvelles averses de neige sans vent en journée.

Pour consulter la vigilance en cours, veuillez vous rendre sur le site https://vigilance.meteofrance.fr/fr

Météo-France - 73 avenue de Paris, 94165 Saint-Mandé cedex - Contact : contact@meteo.fr

Rédigé par Météo-France avec la contribution des observateurs du réseau nivo-météorologiques. Partenariat : ANMSM (Maires de Stations de Montagne), DSF (Domaines Skiables de France), ADSP (Directeurs de Pistes et de la Sécurité des Stations de Sports d'Hiver) et autres acteurs de la montagne.

Bulletin neige & avalanches par téléphone au 0 892 68 10 20 Service 0,35 € / min + prix appel

RÉPUBLIQUE FRANÇAISE
*Liberté Égalité Fraternité*

METEO FRANCE
À VOS CÔTÉS, DANS UN CLIMAT QUI CHANGE

# Bulletin d'estimation du risque d'avalanche

## (valable en dehors des pistes balisées et ouvertes)

# MASSIF : Aure Louron

Rédigé le vendredi 6 mars 2026 à 16h

## Conditions nivo-météo des 7 derniers jours

| | sam. 28/02 | | | | dim. 01/03 | | | | lun. 02/03 | | | | mar. 03/03 | | | | mer. 04/03 | | | | jeu. 05/03 | | | | ven. 06/03 | | | |
|---|---|---|---|---|---|---|---|---|---|---|---|---|---|---|---|---|---|---|---|---|---|---|---|---|---|---|---|---|
| | 03h | 09h | 15h | 21h | 03h | 09h | 15h | 21h | 03h | 09h | 15h | 21h | 03h | 09h | 15h | 21h | 03h | 09h | 15h | 21h | 03h | 09h | 15h | 21h | 03h | 09h | 15h | 21h |
| Météo | | | | | | | | | | | | | | | | | | | | | | | | | | | | |
| Vent (km/h) | 45 | 45 | 25 | 15 | 25 | 40 | 55 | 60 | 60 | 50 | 35 | 30 | 20 | 15 | 15 | 15 | 25 | 35 | 45 | 45 | 45 | 45 | 40 | 35 | 55 | 55 | 45 | 45 |
| à 3000m | | | | | | | | | | | | | | | | | | | | | | | | | | | | |
| Vent (km/h) | 10 | 10 | 15 | 5 | 10 | 20 | 25 | 35 | 35 | 30 | 20 | 15 | 20 | 10 | 10 | 10 | 10 | 20 | 25 | 30 | 30 | 25 | 20 | 20 | 10 | 10 | 15 | 5 |
| à 1500m | | | | | | | | | | | | | | | | | | | | | | | | | | | | |

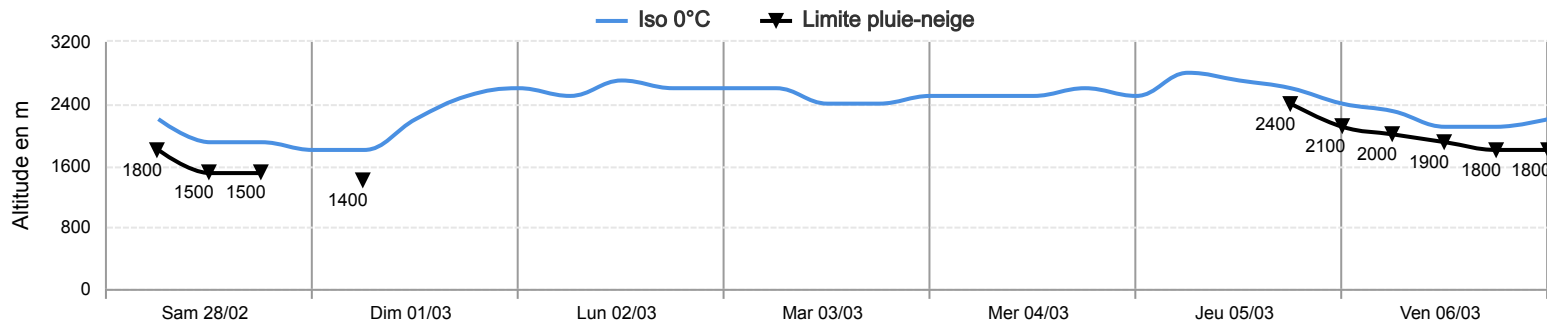


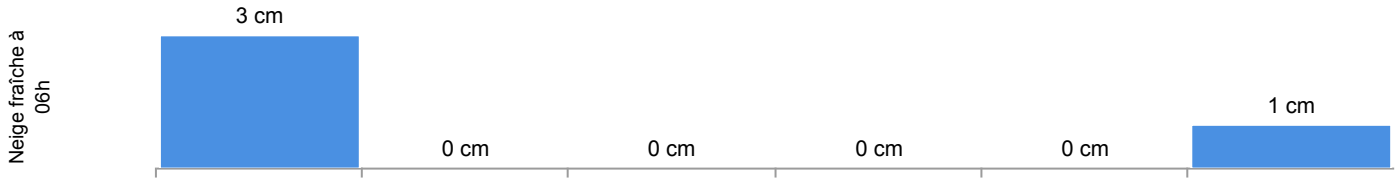


| Risque d'avalanche | sam. 28/02 | dim. 01/03 | lun. 02/03 | mar. 03/03 | mer. 04/03 | jeu. 05/03 | ven. 06/03 |
|---|---|---|---|---|---|---|---|
| | 2 | 2 | 2 | 2 | 2 | 2 | 2 |

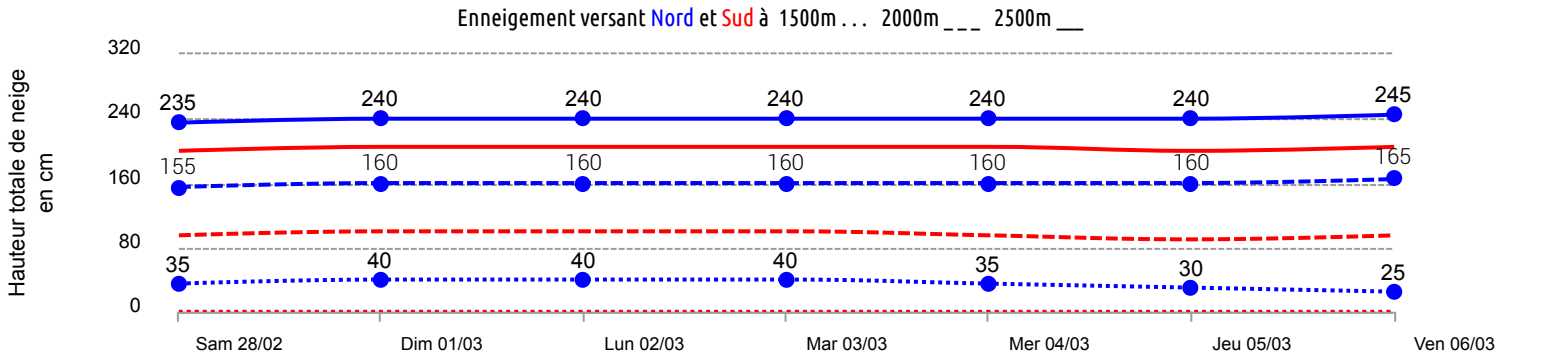


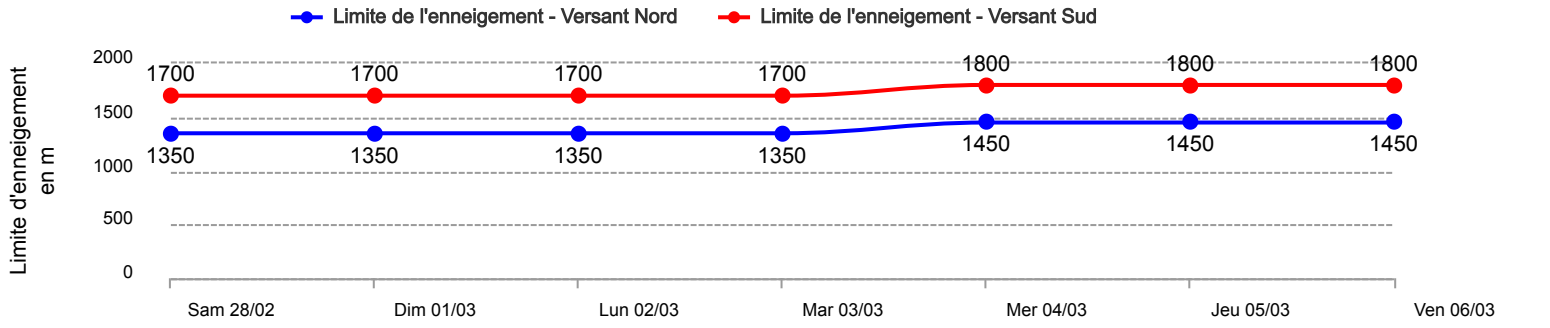


Pour consulter la vigilance en cours, veuillez vous rendre sur le site https://vigilance.meteofrance.fr/fr


Météo-France - 73 avenue de Paris, 94165 Saint-Mandé cedex - Contact : contact@meteo.fr



Rédigé par Météo-France avec la contribution des observateurs du réseau nivo-météorologiques. Partenariat : ANMSM (Maires de Stations de Montagne), DSF (Domaines Skiables de France), ADSP (Directeurs de Pistes et de la Sécurité des Stations de Sports d'Hiver) et autres acteurs de la montagne.



Bulletin neige & avalanches par téléphone au
0 892 68 10 20 Service 0,35 € / min + prix appel