RÉPUBLIQUE FRANÇAISE
Liberté Égalité Fraternité

METEO FRANCE
À VOS CÔTÉS, DANS UN CLIMAT QUI CHANGE

Bulletin d'estimation du risque d'avalanche
(valable en dehors des pistes balisées et ouvertes)

MASSIF : Chablais

Rédigé le vendredi 6 mars 2026 à 16h

Estimation des risques pour le : SAMEDI 07 MARS

2

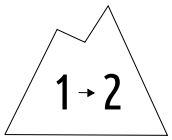

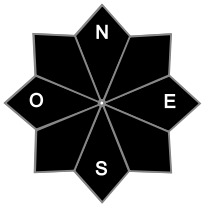

Indice de risque faible évoluant en limité.

Départs spontanés : Rares plaques de fond et coulées humides.

Déclenchements provoqués : Assez peu probables.

Indices de risque : 5 très fort - 4 fort - 3 marqué - 2 limité - 1 faible -- En noir : les pentes les plus dangereuses

Stabilité du manteau neigeux

Situation avalancheuse typique : avalanches de fond neige humide

Départs spontanés :
* Plaques de fond. En adrets en dessous de 2300 m et en versants NW en dessous 2000 m (pentes lisses, raides en herbe ou dalle) possibles à toute heure. Taille 2 (moyenne). Observables : avec ou sans gueule de baleine préalable.
* Quelques petites avalanches de neige humide. Elle se produisent dans les adrets après quelques heures de soleil. Départ ponctuel, écoulement en forme de poire. Observables : escargots, enfoncement piéton important.
* Chutes de corniches (volumineuse), pouvant éventuellement déclencher une plaque en contrebas.

Déclenchements provoqués :
* Plaque dure, très peu probable mais pas impossible. En tout versants au-dessus de 2200 m. Cassure épaisse, taille 2 (moyenne), exceptionnellement 3 (grande). Difficilement déclenchable à skis, mais pouvant être sollicitée par la chute d'une corniche ou une première avalanche de neige humide.
* Départs ponctuels de neige humide sous les skis, au fil de l'ensoleillement, majoritairement dans les pentes raides SE/S/SW. Taille 1 (petite).

Qualité de la neige

Enneigement : bon pour la période. On peut chausser les skis vers 1200/1300 m en versants E/N/W et 1400/1700 m en S. Corniches volumineuses.

Qualité de la neige vendredi :
* Légèrement saupoudrée de poussière de sable
* Regel nocturne assez efficace.
* Manteau neigeux très dense, la croute ramollit et s'humidifie suivant la course du soleil, en dessous de 2200/2300 m, voir 2500 m en S raide.
* En N au-dessus de 2100/2300 m, neige froide, plutôt dure, rares endroits abrités du vent en vielle poudre.

Aperçu météo pour le samedi 07 mars

nuit	matin	après-midi	soir

Ensoleillé, quelques petits cumulus en fin d'après-midi, +7°C à 2000 m.

Pluie-Neige				
Iso 0 °C	2 700 m	2 600 m	2 500 m	2 400 m
Vent 2000 m	↓ 5 km/h	↙ 10 km/h	↖ 5 km/h	↖ 5 km/h
Vent 2500 m	← 10 km/h	← 20 km/h	↖ 20 km/h	↖ 20 km/h

Épaisseur de neige hors-piste

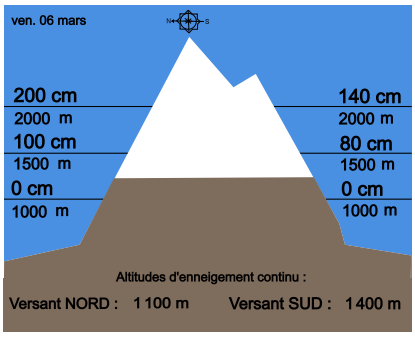

Précipitations à 1800 m

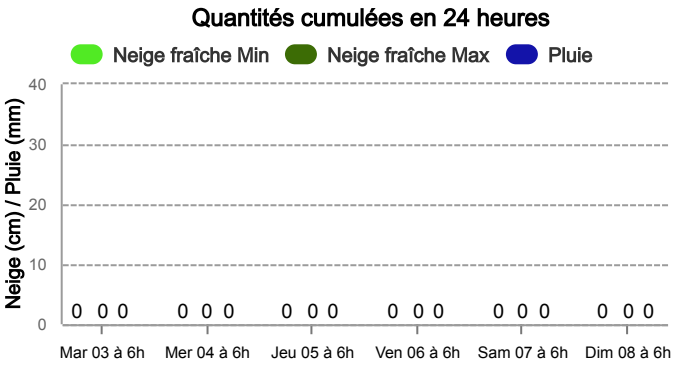

Tendance du dimanche 08 mars

2

Indice de risque limité

Encore des problématiques de neige humide et avalanches de fond.

Pour consulter la vigilance en cours, veuillez vous rendre sur le site https://vigilance.meteofrance.fr/fr

Météo-France - 73 avenue de Paris, 94165 Saint-Mandé cedex - Contact : contact@meteo.fr

Rédigé par Météo-France avec la contribution des observateurs du réseau nivo-météorologiques. Partenariat : ANMSM (Maires de Stations de Montagne), DSF (Domaines Skiables de France), ADSP (Directeurs de Pistes et de la Sécurité des Stations de Sports d'Hiver) et autres acteurs de la montagne.

Bulletin neige & avalanches par téléphone au
0 892 68 10 20 Service 0,35 € / min + prix appel

Bulletin d'estimation du risque d'avalanche

(valable en dehors des pistes balisées et ouvertes)

MASSIF : Chablais

Rédigé le vendredi 6 mars 2026 à 16h

Conditions nivo-météo des 7 derniers jours

	sam. 28/02				dim. 01/03				lun. 02/03				mar. 03/03				mer. 04/03				jeu. 05/03				ven. 06/03			
	03h	09h	15h	21h	03h	09h	15h	21h	03h	09h	15h	21h	03h	09h	15h	21h	03h	09h	15h	21h	03h	09h	15h	21h	03h	09h	15h	21h
Météo																												
Vent (km/h)	30	35	30	20	15	20	25	25	25	15	15	10	10	10	10	10	10	10	10	10	10	25	25	15	10	25	20	15
à 2500m																												
Vent (km/h)	25	25	20	10	5	10	20	20	20	10	10	5	5	5	5	5	5	5	5	5	5	20	10	10	5	20	15	10
à 2000m																												

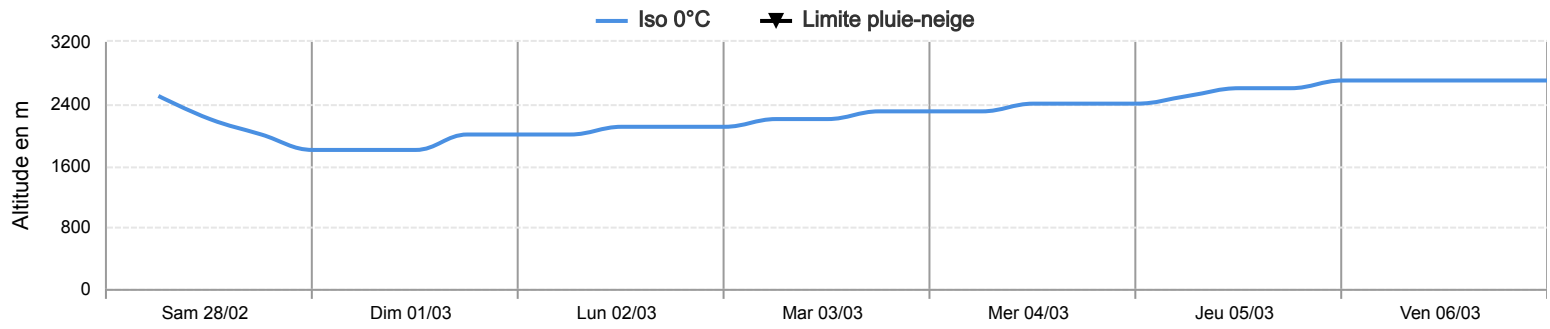

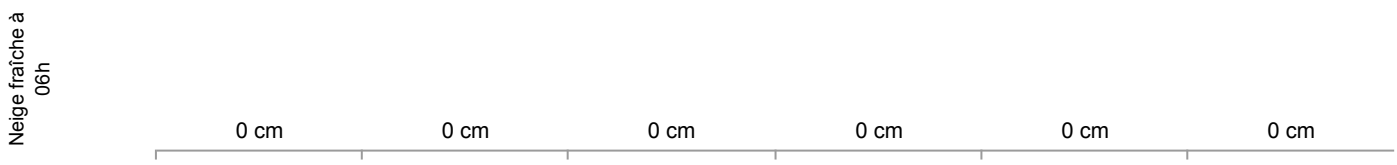

Risque d'avalanche	sam. 28/02	dim. 01/03	lun. 02/03	mar. 03/03	mer. 04/03	jeu. 05/03	ven. 06/03

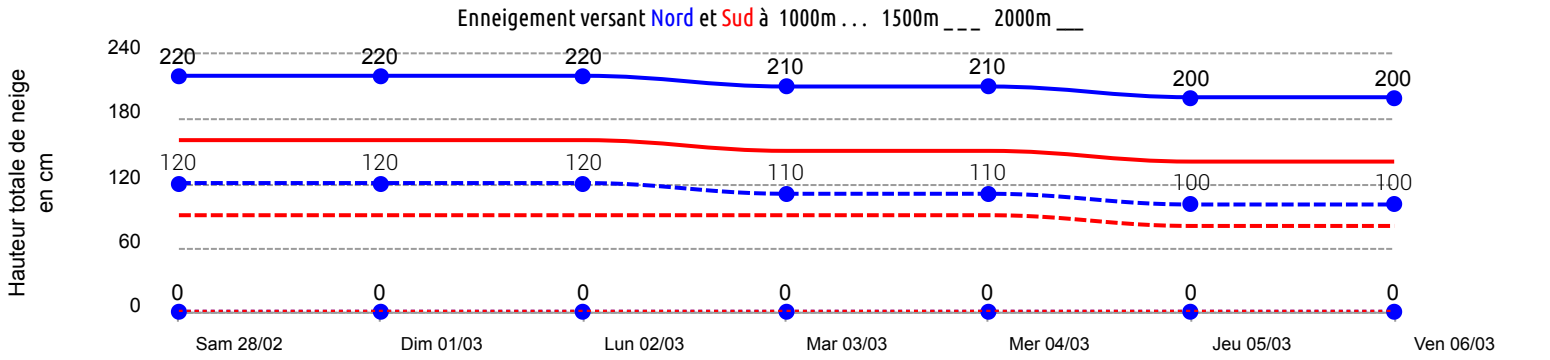

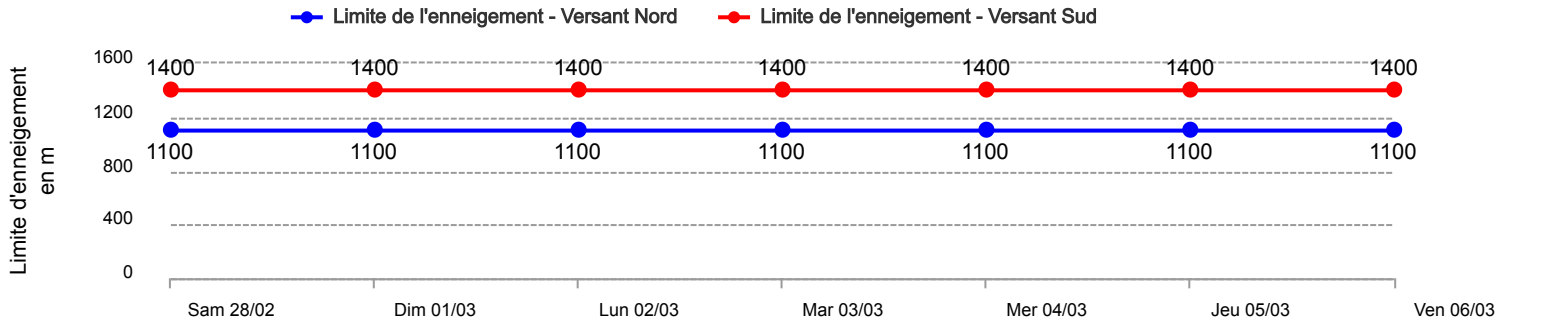

Pour consulter la vigilance en cours, veuillez vous rendre sur le site https://vigilance.meteofrance.fr/fr

Météo-France - 73 avenue de Paris, 94165 Saint-Mandé cedex - Contact : contact@meteo.fr

Rédigé par Météo-France avec la contribution des observateurs du réseau nivo-météorologiques. Partenariat : ANMSM (Maires de Stations de Montagne), DSF (Domaines Skiables de France), ADSP (Directeurs de Pistes et de la Sécurité des Stations de Sports d'Hiver) et autres acteurs de la montagne.

Bulletin neige & avalanches par téléphone au

0 892 68 10 20 Service 0,35 € / min + prix appel