Bulletin d'estimation du risque d'avalanche

(valable en dehors des pistes balisées et ouvertes)

MASSIF : Champsaur

Rédigé le vendredi 6 mars 2026 à 16h

Estimation des risques pour le : SAMEDI 07 MARS

COUCHES FRAGILES DIFFICILES À SOLLICITER, RARES DÉPARTS EN NEIGE HUMIDE

2

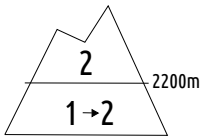

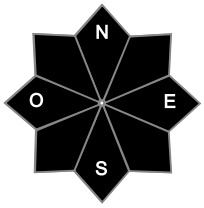

Au-dessus de 2200m indice de risque limité, plus bas indice faible évoluant en limité.

Départs spontanés : rares départs au soleil, rare avalanche de fond.

Déclenchements provoqués : rares avalanches de plaque sur couche fragile persistante.

Indices de risque : 5 très fort - 4 fort - 3 marqué - 2 limité - 1 faible -- En noir : les pentes les plus dangereuses

Stabilité du manteau neigeux

Situation avalancheuse typique : couche fragile persistante — neige humide

Déclenchements provoqués :

- une avalanche de plaque reste encore envisageable dans les versants ouest, nord et est au-dessus de 2000/2200 m. Même si leur déclenchement est généralement difficile, une couche fragile persistante insuffisamment enfouie à la base du manteau neigeux peut localement être sollicitée dans les secteurs peu enneigés, abords de croupes et bords des couloirs. Avalanche pouvant être de grande taille, avec cassure épaisse et propagation à distance.
- un skieur évoluant tardivement en pente raide ensoleillée peut provoquer un départ superficiel en neige humide sous les skis.

Départs spontanés :

- rares départs en neige humide. Peu probables en tout début de journée, puis devenant possibles à partir de la fin de matinée en pentes raides ensoleillées. Avalanche de taille petite en général, rarement moyenne (taille 1 à 2).
- une rare avalanche de fond emportant la totalité du manteau neigeux jusqu'au sol peut céder spontanément à n'importe quel moment du jour ou de la nuit sur terrain favorable (pentes herbeuses, dalles rocheuses), parfois précédée par l'ouverture d'une reptation (ou gueule de baleine). Avalanche de taille moyenne.

Qualité de la neige

L'enneigement est encore excédentaire ou se rapproche des normales avec le tassement.
Hauteurs de neige observées : 45 cm au hameau des Portes dans le Valgaudemar à 1270 m, 135 cm à la nivose d'Orcières à 2280 m, et 177 cm au-dessus de Prapic à 2480 m.

Limite d'enneigement skiable à partir de 1200/1300 m en ubacs, 1500/1700 m en adrets pas trop raides.

État de la neige de surface : en versants ensoleillés, croute souvent modérément portante le matin en dessous de 2000/2200 m, puis reprise de l'humidification en surface au fil de la journée. En versants nord-est à nord-ouest au-dessus de 2200/2300 m, vieille poudreuse encore meuble, souvent plus durcie par le vent proche des crêtes et sommets.

Aperçu météo pour le samedi 07 mars

	nuit	matin	après-midi	soir

Ciel voilé, s'éclaircissant en cours de matinée.

Pluie-Neige				
Iso 0 °C	2 500 m	2 500 m	2 500 m	2 400 m
Vent 2000 m	25 km/h	15 km/h	15 km/h	10 km/h
Vent 3000 m	35 km/h	30 km/h	25 km/h	20 km/h

Épaisseur de neige hors-piste

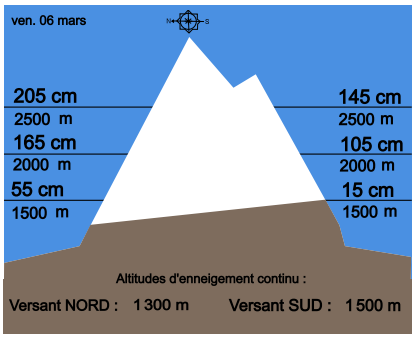

Précipitations à 1800 m

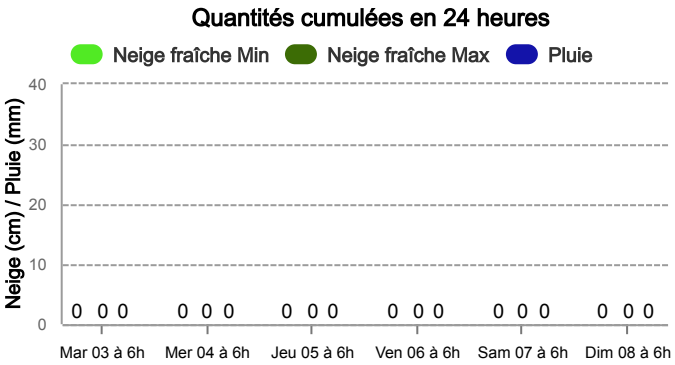

Tendance du dimanche 08 mars

2

Indice de risque limité

Maintient d'un risque limité, avec peu d'évolution des conditions météorologiques.

Pour consulter la vigilance en cours, veuillez vous rendre sur le site https://vigilance.meteofrance.fr/fr

Météo-France - 73 avenue de Paris, 94165 Saint-Mandé cedex - Contact : contact@meteo.fr

Rédigé par Météo-France avec la contribution des observateurs du réseau nivo-météorologiques. Partenariat : ANMSM (Maires de Stations de Montagne), DSF (Domaines Skiables de France), ADSP (Directeurs de Pistes et de la Sécurité des Stations de Sports d'Hiver) et autres acteurs de la montagne.

Bulletin neige & avalanches par téléphone au 0 892 68 10 20 Service 0,35 € / min + prix appel

RÉPUBLIQUE FRANÇAISE
Liberté Égalité Fraternité

METEO FRANCE
À VOS CÔTÉS, DANS UN CLIMAT QUI CHANGE

Bulletin d'estimation du risque d'avalanche

(valable en dehors des pistes balisées et ouvertes)

MASSIF : Champsaur

Rédigé le vendredi 6 mars 2026 à 16h

Conditions nivo-météo des 7 derniers jours

	sam. 28/02				dim. 01/03				lun. 02/03				mar. 03/03				mer. 04/03				jeu. 05/03				ven. 06/03			
	03h	09h	15h	21h	03h	09h	15h	21h	03h	09h	15h	21h	03h	09h	15h	21h	03h	09h	15h	21h	03h	09h	15h	21h	03h	09h	15h	21h
Météo																												
Vent (km/h)	20	25	25	15	10	15	15	10	15	15	15	15	15	10	10	10	10	5	10	10	15	20	30	30	35	40	30	35
à 3000m																												
Vent (km/h)	5	5	10	5	5	5	15	10	10	10	10	10	10	5	10	10	5	5	10	10	10	15	15	20	25	25	20	25
à 2000m																												

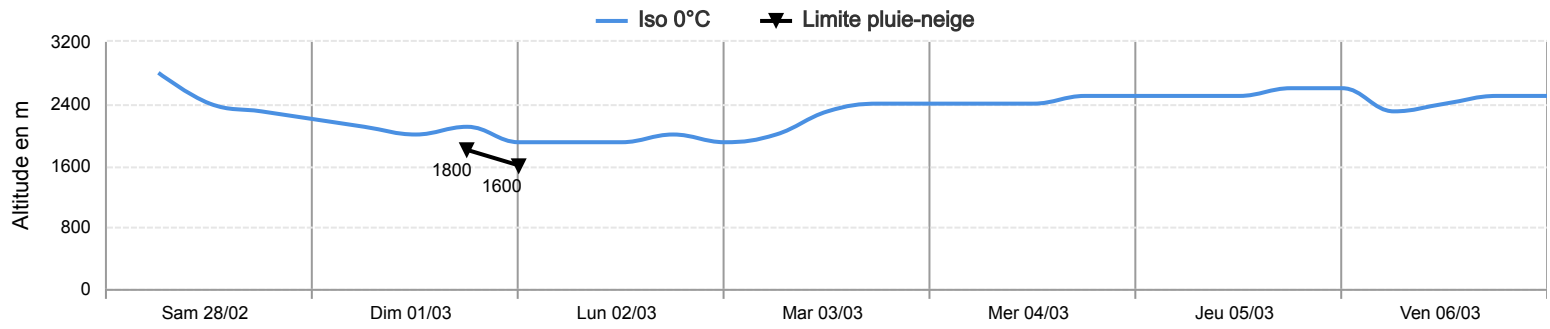

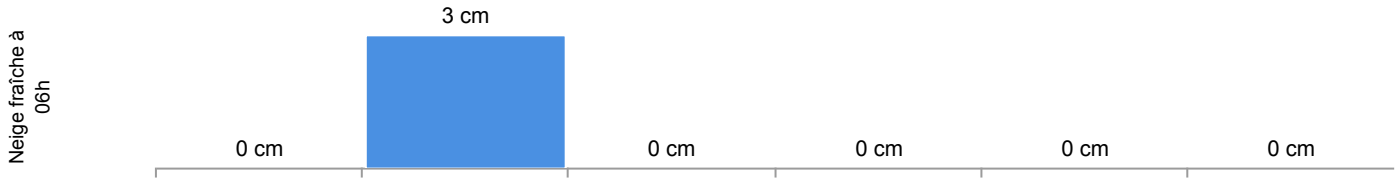

Risque d'avalanche	sam. 28/02	dim. 01/03	lun. 02/03	mar. 03/03	mer. 04/03	jeu. 05/03	ven. 06/03
	2	2	2	2	2	2	2

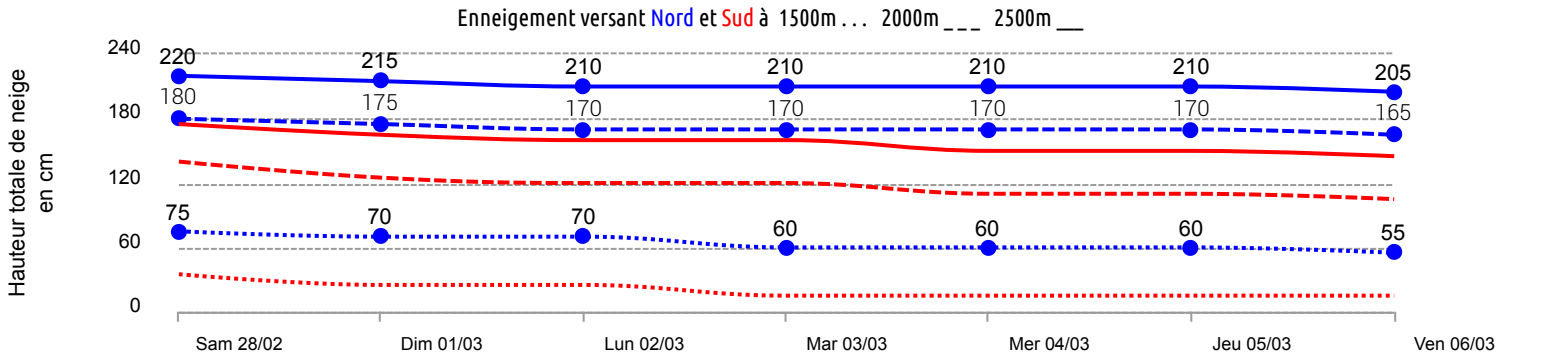

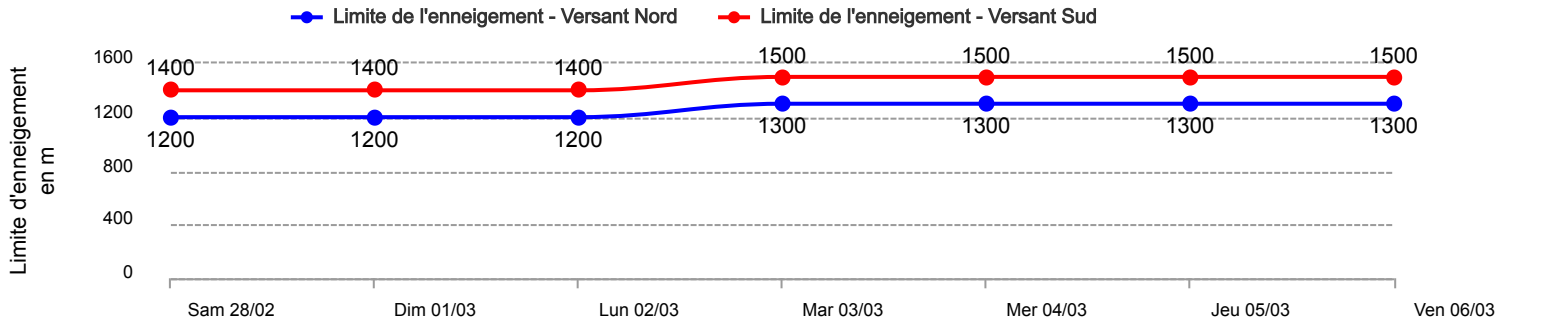

Pour consulter la vigilance en cours, veuillez vous rendre sur le site https://vigilance.meteofrance.fr/fr

Météo-France - 73 avenue de Paris, 94165 Saint-Mandé cedex - Contact : contact@meteo.fr

Rédigé par Météo-France avec la contribution des observateurs du réseau nivo-météorologiques. Partenariat : ANMSM (Maires de Stations de Montagne), DSF (Domaines Skiables de France), ADSP (Directeurs de Pistes et de la Sécurité des Stations de Sports d'Hiver) et autres acteurs de la montagne.

Bulletin neige & avalanches par téléphone au
0 892 68 10 20 Service 0,35 € / min + prix appel