Bulletin d'estimation du risque d'avalanche
(valable en dehors des pistes balisées et ouvertes)

MASSIF : Grandes-Rousses

Rédigé le vendredi 6 mars 2026 à 16h

Estimation des risques pour le : SAMEDI 07 MARS

QUELQUES INSTABILITES ENCORE PRESENTES EN NORD D'ALTITUDE, ACTIVITE HUMIDE AU SOLEIL.

2

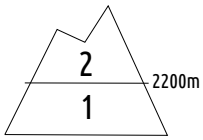

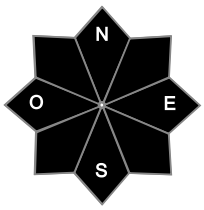

neige humide

Indices de risque : 5 très fort - 4 fort - 3 marqué - 2 limité - 1 faible -- En noir : les pentes les plus dangereuses

Au-dessus de 2200m indice de risque limité, plus bas indice faible.

Départs spontanés : Avalanches de neige humide et plaques de fond en secteurs ensoleillés.

Déclenchements provoqués : Présence de rares plaques en versant froid de haute altutde.

Stabilité du manteau neigeux

Situation avalancheuse typique : avalanches de fond couche fragile persistante

Avec la poursuite d'un temps sec et ensoleillée ces derniers jours, le manteau neigeux s'est considérablement tassé et stabilisé en dessous de 2200/2400 m selon les versants. A plus haute altitude, il reste de rares instabilités en neige froide.

Départs spontanés : A toute heure de la journée ou de la nuit et principalement en large secteur Sud, possible avalanche de fond en pente raide herbeuse ou sur les dalles rocheuses, de tailles moyennes. Avalanches parfois précédées par l'ouverture d'une fissure / gueule de baleine. Aux heures chaudes et toujours en large Sud, le manteau neigeux s'humidifie parfois profondément et des coulées humides, parfois de tailles moyennes, peuvent partir spontanément près des rochers. Quelques chutes de corniche sont également possibles à moyennes altitudes (plutôt sous 2500m en général).

Déclenchements provoqués : Dans les versants ombragés de haute montagne, des départs de plaque de neige compactée par le vent (qui repose parfois sur une couche fragile persistante) sont encore possibles. On les trouve par exemple en bordure de zone d'accumulation ou à proximité des rochers. Le risque est globalement assez faible, mais en cas d'avalanche la cassure peut facilement dépasser un mètre. Sous 2000/2200m, ce risque est faible. Au soleil, plutôt l'après_midi, possibilité de faire partir une coulée humide sous les skis.

Qualité de la neige

Qualification de l'enneigement : L'enneigement régresse en partie basse, mais il est toujours bon pour la saison dès 1400 m, voire très bon au dessus de 1600 m environ, notamment dans les combes d'altitude. On trouve des crêtes un peu dégarnies par le vent, ou au contraire des corniches assez conséquentes.

Limites skiables : vers 1400/1700 m.

Qualité de la neige samedi : Dans un large secteur Sud (Ouest et Est inclus), manteau de type printanier, avec une neige légèrement croûtée, regel nocturne moyen. Manteau s'humidifiant en journée, parfois profondément selon l'orientation. En versants ombragés, neige restée froide, quelquefois en vieille poudre, mais plus souvent compactée par le vent.

Aperçu météo pour le samedi 07 mars

	nuit	matin	après-midi	soir

Belle journée ensoleillée et douce. Présence de sable dans l'air (moins que les journées précédentes).

Pluie-Neige				
Iso 0 °C	2 500 m	2 700 m	2 700 m	2 300 m
Vent 2000 m	← 10 km/h	← 5 km/h	↘ 5 km/h	↓ 5 km/h
Vent 3000 m	↖ 10 km/h	← 10 km/h	← 15 km/h	↖ 15 km/h

Épaisseur de neige hors-piste

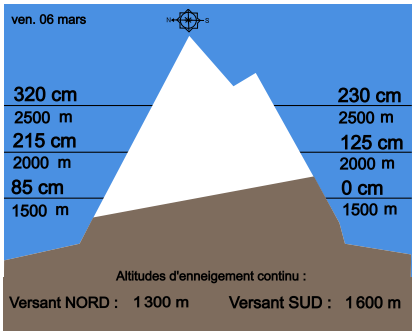

Précipitations à 1800 m

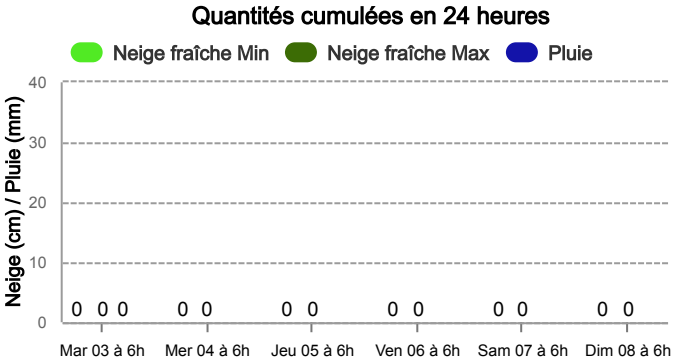

Tendance du dimanche 08 mars

2

Indice de risque limité

Risque en légère baisse avec le redoux et le tassement du manteau en cours.

Pour consulter la vigilance en cours, veuillez vous rendre sur le site https://vigilance.meteofrance.fr/fr

Météo-France - 73 avenue de Paris, 94165 Saint-Mandé cedex - Contact : contact@meteo.fr

Rédigé par Météo-France avec la contribution des observateurs du réseau nivo-météorologiques. Partenariat : ANMSM (Maires de Stations de Montagne), DSF (Domaines Skiables de France), ADSP (Directeurs de Pistes et de la Sécurité des Stations de Sports d'Hiver) et autres acteurs de la montagne.

Bulletin neige & avalanches par téléphone au **0 892 68 10 20** Service 0,35 € / min + prix appel

RÉPUBLIQUE FRANÇAISE
Liberté Égalité Fraternité

METEO FRANCE
À VOS CÔTÉS, DANS UN CLIMAT QUI CHANGE

Bulletin d'estimation du risque d'avalanche

(valable en dehors des pistes balisées et ouvertes)

MASSIF : Grandes-Rousses

Rédigé le vendredi 6 mars 2026 à 16h

Conditions nivo-météo des 7 derniers jours

	sam. 28/02				dim. 01/03				lun. 02/03				mar. 03/03				mer. 04/03				jeu. 05/03				ven. 06/03			
	03h	09h	15h	21h	03h	09h	15h	21h	03h	09h	15h	21h	03h	09h	15h	21h	03h	09h	15h	21h	03h	09h	15h	21h	03h	09h	15h	21h
Météo																												
Vent (km/h)	15	15	25	30	30	30	30	35	40	40	35	30	15	10	10	10	10	10	10	15	15	20	15	10	20	25	20	20
à 3000m																												
Vent (km/h)	10	10	20	20	20	20	20	30	35	35	25	25	10	5	5	5	5	5	5	5	10	10	5	20	25	25	15	15
à 2000m																												

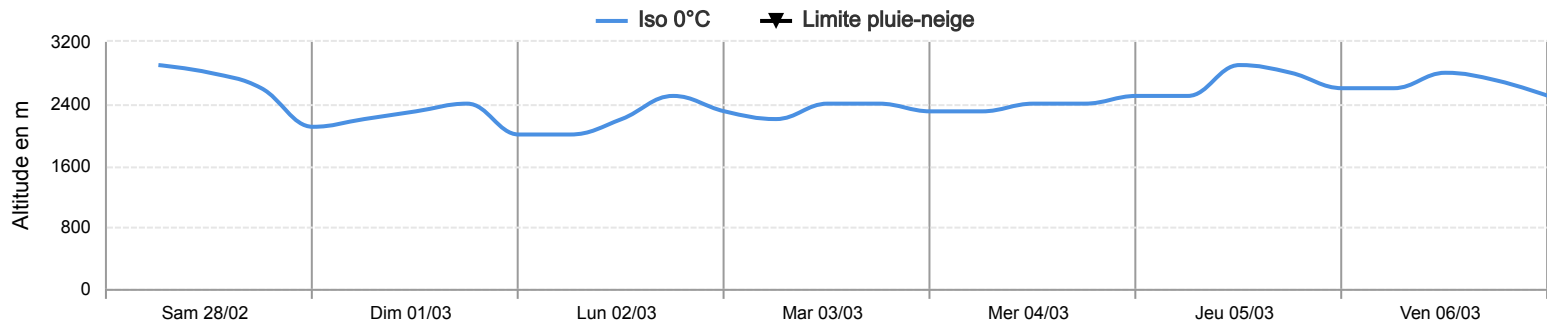

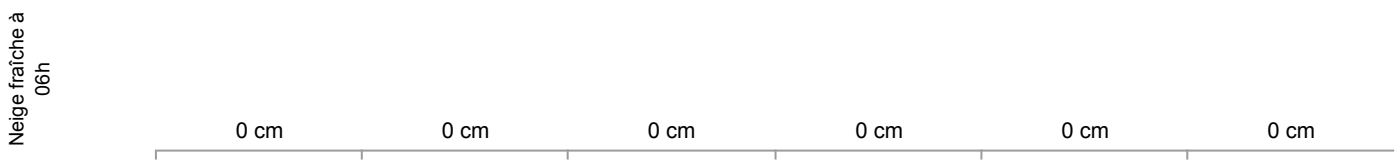

Risque d'avalanche	sam. 28/02	dim. 01/03	lun. 02/03	mar. 03/03	mer. 04/03	jeu. 05/03	ven. 06/03
	2	2	2	2	2	2	2

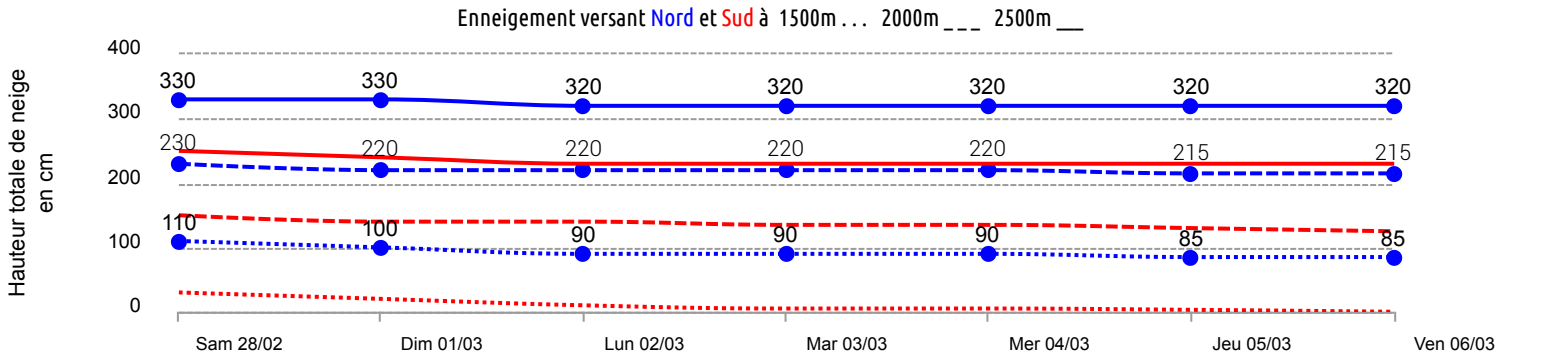

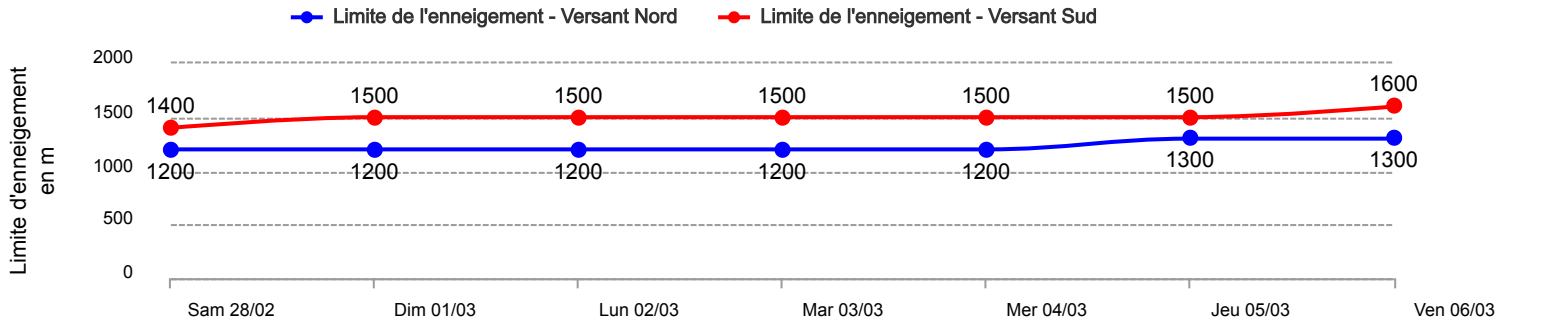

Pour consulter la vigilance en cours, veuillez vous rendre sur le site https://vigilance.meteofrance.fr/fr

Météo-France - 73 avenue de Paris, 94165 Saint-Mandé cedex - Contact : contact@meteo.fr

Rédigé par Météo-France avec la contribution des observateurs du réseau nivo-météorologiques. Partenariat : ANMSM (Maires de Stations de Montagne), DSF (Domaines Skiables de France), ADSP (Directeurs de Pistes et de la Sécurité des Stations de Sports d'Hiver) et autres acteurs de la montagne.

Bulletin neige & avalanches par téléphone au
0 892 68 10 20 Service 0,35 € / min + prix appel