Bulletin d'estimation du risque d'avalanche

(valable en dehors des pistes balisées et ouvertes)

MASSIF : Haute-Ariege

Rédigé le vendredi 6 mars 2026 à 16h

Estimation des risques pour le : SAMEDI 07 MARS

HUMIDIFICATION GÉNÉRALISÉE SOUS 2100 M; QUELQUES STRUCTURES DE PLAQUES EN ALTITUDE AVEC LE TRANSPORT DE NEIGE PAR LE VENT

2

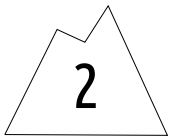

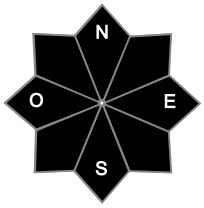

Indice de risque limité.

Départs spontanés : Avalanches de neige humide, rarement grandes

Déclenchements provoqués : Fines structures de plaques en altitude

Indices de risque : 5 très fort - 4 fort - 3 marqué - 2 limité - 1 faible -- En noir : les pentes les plus dangereuses

Stabilité du manteau neigeux

Situation avalancheuse typique : neige humide neige ventée

Départs spontanés :
Du fait de la douceur, des éclaircies et des averses des avalanches de neige humide de taille petite à moyenne sont attendues sous 2200m, un peu plus haut au soleil. De plus, souvent associées à de larges fissures, des avalanches de fond en neige humide en dessous de 2000m ont été signalées et sont à nouveau susceptibles de se produire d'ici demain soir.

Déclenchements provoqués :
Avalanches de plaques parfois facilement déclenchables dans la neige récente plutôt au-dessus de 2200/2400m. Ces plaques sont souvent assez fines et localisées dans les versants nord à nord-ouest d'altitude, plutôt proche des crêtes. On trouve aussi localement des couches fragiles plus enfouies en nord d'altitude difficilement déclenchables.
Observables : neige travaillée par le vent en surface, corniche surplombant la pente

Qualité de la neige

Enneigement :
L'enneigement est encore excédentaire dès la moyenne montagne suite aux perturbations neigeuses depuis le début de l'année.
La limite skiable se situe vers 1600m plein Sud alors que certaines vallées ombragées sont encore enneigées dès 1300m. Sur les parties hautes du massif, les pentes Ouest ont souvent été rabotées par le vent.

Qualité de la neige :
Neige humide en profondeur sous 2000/2200m. Plus haut, on trouvera une fine couche de neige récente, souvent compacte sous 2500 m, plus froide en altitude et restant poudreuse dans les combes abritées de haute montagne.

Aperçu météo pour le samedi 07 mars

	nuit	matin	après-midi	soir
	Quelques averses l'après-midi			
Pluie-Neige	1 800 m		2 000 m	
Iso 0 °C	2 200 m	2 300 m	2 500 m	2 200 m
Vent 2000 m	20 km/h	40 km/h	35 km/h	30 km/h
Vent 3000 m	40 km/h	45 km/h	45 km/h	40 km/h

Épaisseur de neige hors-piste

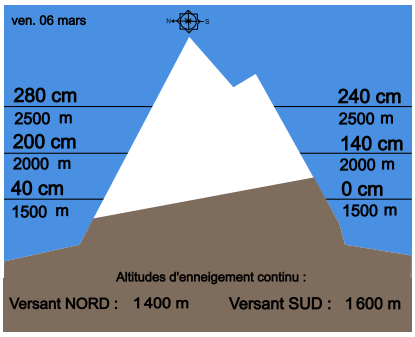

Précipitations à 1800 m

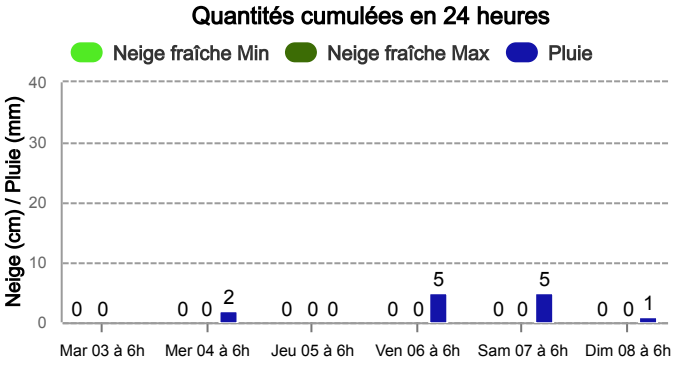

Tendance du dimanche 08 mars

2

Indice de risque limité

Maintien d'un risque limité vu le peu d'évolution des conditions nivo-météorologiques

Pour consulter la vigilance en cours, veuillez vous rendre sur le site https://vigilance.meteofrance.fr/fr

Météo-France - 73 avenue de Paris, 94165 Saint-Mandé cedex - Contact : contact@meteo.fr

Rédigé par Météo-France avec la contribution des observateurs du réseau nivo-météorologiques. Partenariat : ANMSM (Maires de Stations de Montagne), DSF (Domaines Skiables de France), ADSP (Directeurs de Pistes et de la Sécurité des Stations de Sports d'Hiver) et autres acteurs de la montagne.

Bulletin neige & avalanches par téléphone au **0 892 68 10 20** Service 0,35 € / min + prix appel

RÉPUBLIQUE FRANÇAISE
Liberté Égalité Fraternité

METEO FRANCE
À VOS CÔTÉS, DANS UN CLIMAT QUI CHANGE

Bulletin d'estimation du risque d'avalanche

(valable en dehors des pistes balisées et ouvertes)

MASSIF : Haute-Ariege

Rédigé le vendredi 6 mars 2026 à 16h

Conditions nivo-météo des 7 derniers jours

	sam. 28/02				dim. 01/03				lun. 02/03				mar. 03/03				mer. 04/03				jeu. 05/03				ven. 06/03			
	03h	09h	15h	21h	03h	09h	15h	21h	03h	09h	15h	21h	03h	09h	15h	21h	03h	09h	15h	21h	03h	09h	15h	21h	03h	09h	15h	21h
Météo																												
Vent (km/h)	30	20	20	15	20	25	30	40	40	50	50	45	35	25	20	20	25	25	30	40	40	35	30	30	40	25	25	25
à 3000m																												
Vent (km/h)	10	10	15	5	10	20	25	30	30	35	35	30	35	25	20	15	20	20	25	30	35	30	20	20	25	15	20	20
à 2000m																												

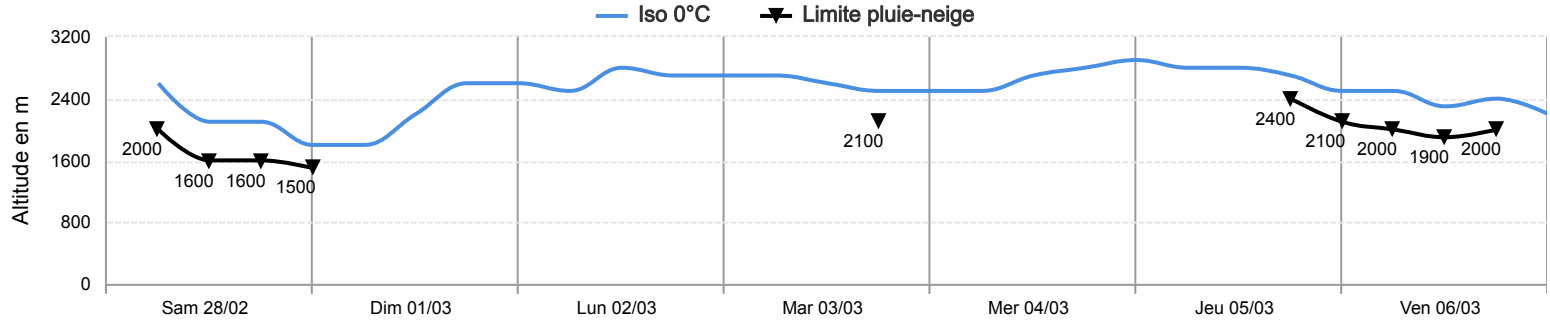

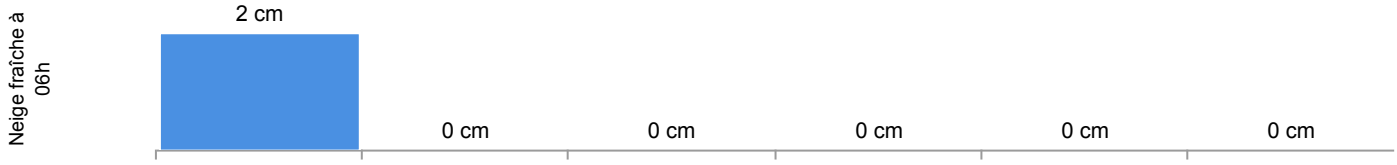

Risque d'avalanche	sam. 28/02	dim. 01/03	lun. 02/03	mar. 03/03	mer. 04/03	jeu. 05/03	ven. 06/03
	2	2	2	2	2	2	2



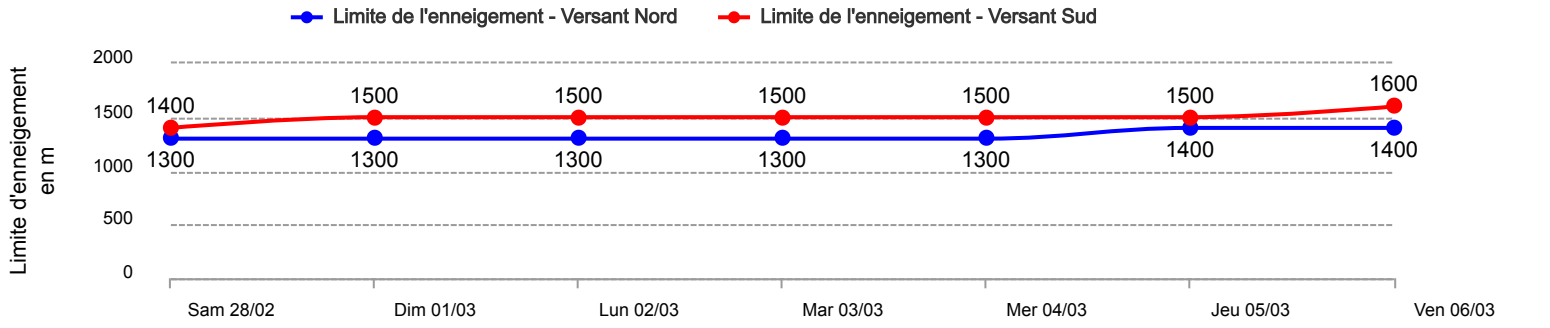

Pour consulter la vigilance en cours, veuillez vous rendre sur le site https://vigilance.meteofrance.fr/fr

Météo-France - 73 avenue de Paris, 94165 Saint-Mandé cedex - Contact : contact@meteo.fr

Rédigé par Météo-France avec la contribution des observateurs du réseau nivo-météorologiques. Partenariat : ANMSM (Maires de Stations de Montagne), DSF (Domaines Skiables de France), ADSP (Directeurs de Pistes et de la Sécurité des Stations de Sports d'Hiver) et autres acteurs de la montagne.

Bulletin neige & avalanches par téléphone au
0 892 68 10 20 Service 0,35 € / min + prix appel