Bulletin d'estimation du risque d'avalanche
(valable en dehors des pistes balisées et ouvertes)

MASSIF : Pays-Basque

Rédigé le vendredi 6 mars 2026 à 16h

Estimation des risques pour le : SAMEDI 07 MARS

PLAQUES PEU ÉPAISSES EN ALTITUDE, HUMIDIFICATION AILLEURS.

2

2

N O E S

Humidification.

Indice de risque limité.

Départs spontanés : Départs ponctuels dans la neige humide, avalanches de fond possibles.

Déclenchements provoqués : Plaques peu épaisses en altitude.

Indices de risque : 5 très fort - 4 fort - 3 marqué - 2 limité - 1 faible -- En noir : les pentes les plus dangereuses

Stabilité du manteau neigeux

Situation avalancheuse typique : neige ventée — neige humide

Déclenchements provoqués : **Au plus haut du massif**, dans les versants allant de l'Ouest au Nord-Est, des plaques peu épaisses peuvent se former avec les chutes de neige récentes et le vent de sud-est. Leur déclenchement par un simple skieur peut engendrer de petites avalanches, rarement moyennes.
Partout ailleurs, un simple skieur peut déclencher dans la neige humide un départ ponctuel dans les pentes raides en toutes orientations dès le matin, engendrant de petites avalanches, rarement des moyennes.

Départs spontanés : **Au plus haut du massif**, des départs ponctuels de plaques décrites ci-dessus restent possibles par surcharge par le vent, engendrant de petites avalanches, rarement moyennes.
Partout ailleurs, des départs ponctuels dans la neige humide sont attendus dans les pentes raides et en toutes orientations dès le matin, avec la douceur et l'humidité présentes. Des avalanches petites à rarement moyennes sont possibles. Des avalanches de fond peuvent aussi se produire en toutes orientations, partant d'une zone d'accumulation en altitude et emportant l'intégralité du manteau. Des avalanches moyennes, parfois grandes sont possibles.

Qualité de la neige

Enneigement : faible enneigement sous 1600 m, l'enneigement est bon plus haut, mais bien irrégulièrement réparti, crêtes dégarnies en particulier les versants ouest, combes plus chargées, et corniches parfois imposantes.
Limites skiables : à partir de 1600 m en versants froids.
État de la neige : Quelques centimètres de neige fraîche au-dessus de 1700/1800m ce samedi, venant s'ajouter à ceux de la veille. La neige peut être travaillée par le vent dans les versants ombragés au plus haut du massif. Le manteau neigeux poursuit son humidification ailleurs.

Aperçu météo pour le samedi 07 mars

Quelques averses de neige au-dessus de 1700/1800m surtout l'après-midi et en soirée, du vent de sud-est faible à modéré.

	nuit	matin	après-midi	soir
Pluie-Neige	1700 m	1800 m	1800 m	1700 m
Iso 0 °C	2100 m	2100 m	2100 m	2100 m
Vent 1000 m	↓ 10 km/h	↖ 10 km/h	↙ 20 km/h	↑ 15 km/h
Vent 2000 m	↓ 25 km/h	← 25 km/h	← 35 km/h	↑ 25 km/h

Épaisseur de neige hors-piste

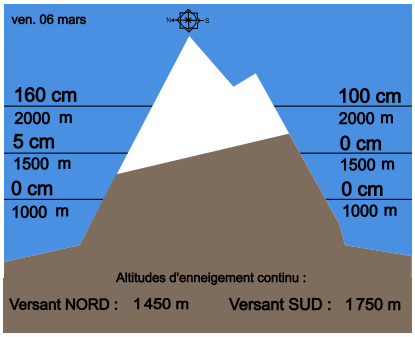

Précipitations à 1800 m

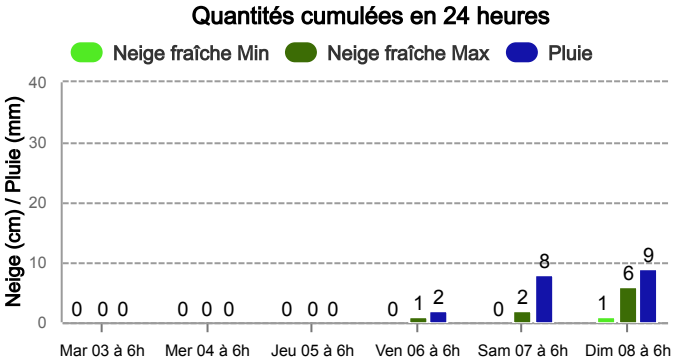

Tendance du dimanche 08 mars

2

Indice de risque limité

Risque stationnaire, quelques averses de neige sans vent à venir.

Pour consulter la vigilance en cours, veuillez vous rendre sur le site https://vigilance.meteofrance.fr/fr

Météo-France - 73 avenue de Paris, 94165 Saint-Mandé cedex - Contact : contact@meteo.fr

Rédigé par Météo-France avec la contribution des observateurs du réseau nivo-météorologiques. Partenariat : ANMSM (Maires de Stations de Montagne), DSF (Domaines Skiables de France), ADSP (Directeurs de Pistes et de la Sécurité des Stations de Sports d'Hiver) et autres acteurs de la montagne.

Bulletin neige & avalanches par téléphone au 0 892 68 10 20 Service 0,35 € / min + prix appel

RÉPUBLIQUE FRANÇAISE
Liberté Égalité Fraternité

METEO FRANCE
À VOS CÔTÉS, DANS UN CLIMAT QUI CHANGE

Bulletin d'estimation du risque d'avalanche
(valable en dehors des pistes balisées et ouvertes)
MASSIF : Pays-Basque

Rédigé le vendredi 6 mars 2026 à 16h

Conditions nivo-météo des 7 derniers jours

	sam. 28/02				dim. 01/03				lun. 02/03				mar. 03/03				mer. 04/03				jeu. 05/03				ven. 06/03			
	03h	09h	15h	21h	03h	09h	15h	21h	03h	09h	15h	21h	03h	09h	15h	21h	03h	09h	15h	21h	03h	09h	15h	21h	03h	09h	15h	21h
Météo																												
Vent (km/h)	25	25	25	25	30	50	75	85	85	80	80	70	50	25	15	20	25	25	55	70	70	60	45	35	30	25	25	20
à 2000m																												
Vent (km/h)	10	10	15	15	15	25	50	55	60	55	45	40	35	20	15	10	15	15	25	50	50	35	25	20	15	15	20	15
à 1000m																												

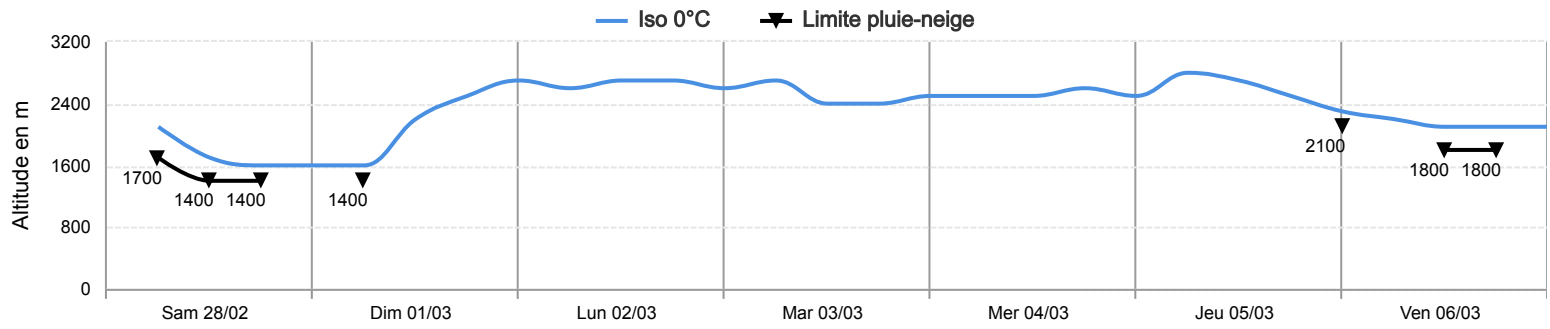

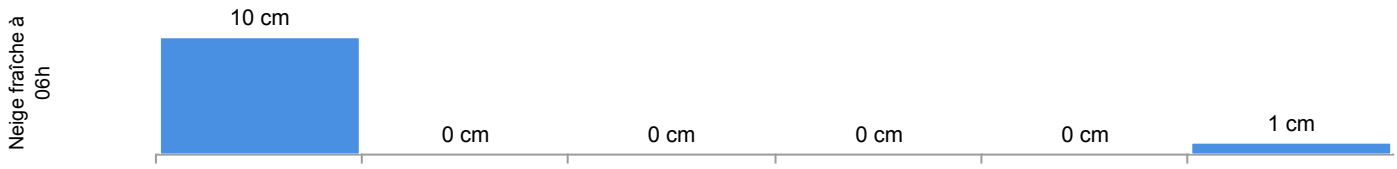

Risque d'avalanche	sam. 28/02	dim. 01/03	lun. 02/03	mar. 03/03	mer. 04/03	jeu. 05/03	ven. 06/03
	1	1	1	2	2	2	2

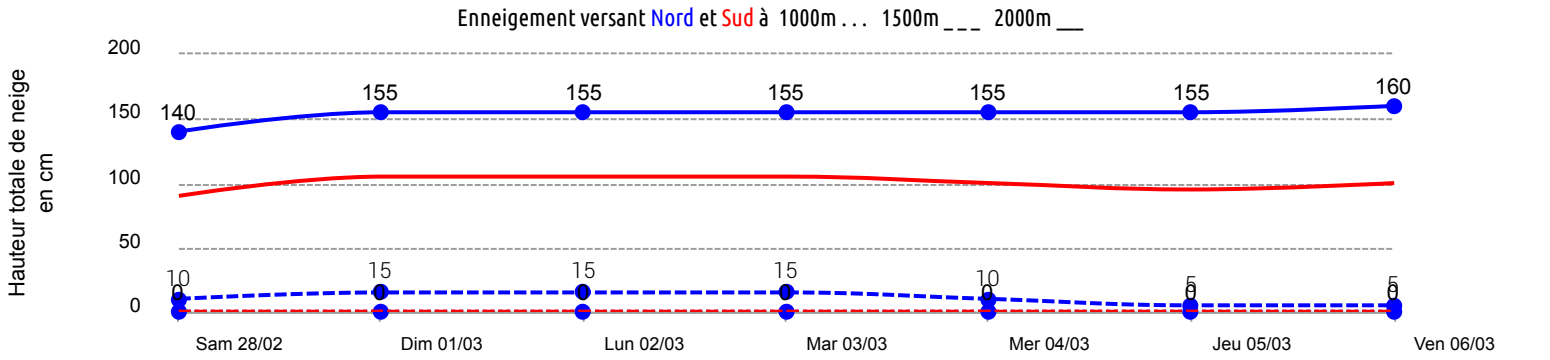

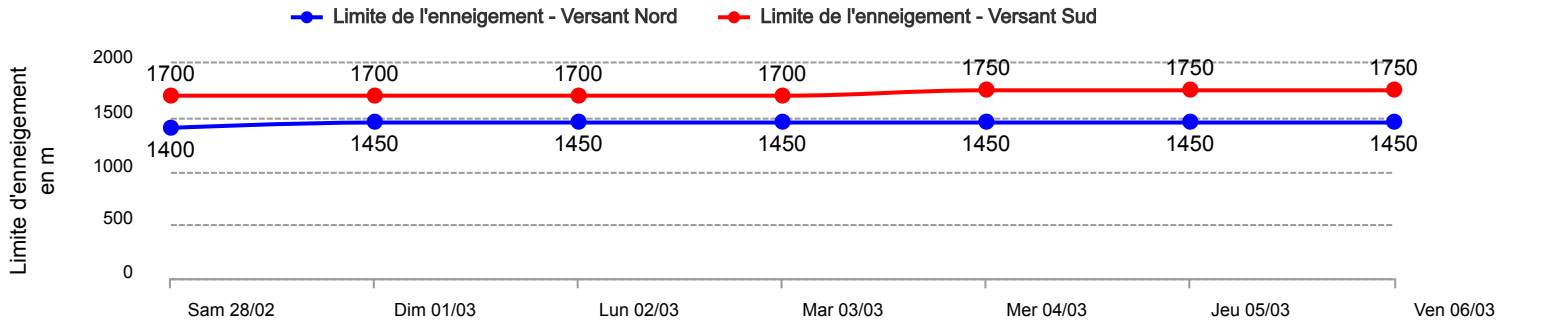

Pour consulter la vigilance en cours, veuillez vous rendre sur le site https://vigilance.meteofrance.fr/fr

Météo-France - 73 avenue de Paris, 94165 Saint-Mandé cedex - Contact : contact@meteo.fr

Rédigé par Météo-France avec la contribution des observateurs du réseau nivo-météorologiques. Partenariat : ANMSM (Maires de Stations de Montagne), DSF (Domaines Skiables de France), ADSP (Directeurs de Pistes et de la Sécurité des Stations de Sports d'Hiver) et autres acteurs de la montagne.

Bulletin neige & avalanches par téléphone au
0 892 68 10 20 Service 0,35 € / min + prix appel