Bulletin d'estimation du risque d'avalanche
(valable en dehors des pistes balisées et ouvertes)

MASSIF : Renoso Incudine

Rédigé le vendredi 6 mars 2026 à 16h

Estimation des risques pour le : SAMEDI 07 MARS

NEIGE HUMIDE

2

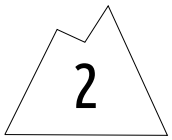

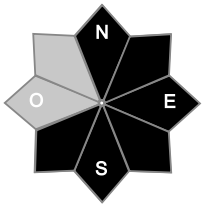

Indice de risque limité.

Départs spontanés : Nombreux départs en neige humides.

Déclenchements provoqués : petites plaques en altitude.

Indices de risque : 5 très fort - 4 fort - 3 marqué - 2 limité - 1 faible -- En noir : les pentes les plus dangereuses

Stabilité du manteau neigeux

Situation avalancheuse typique : neige humide

Déclenchements provoqués :
En dessous de 2000 m activité attendue avec des avalanches de neige humide de taille petite à moyenne, plus rarement grande. Les pluies attendues en versants Est jusqu'à 2100 m peuvent favoriser ces départs avec une humidification encore plus en profondeur et notamment dans quelques versants ombragés où le manteau neigeux n'est pas encore humidifié totalement. Une avalanche de fond de taille 2 (moyenne) sur les dalles rocheuses emportant la totalité du manteau neigeux en place reste possible.
Au dessus de 2000 m avalanches de neige sèche possibles au fil des chutes de neige, dans les pentes raides d'un large secteur Ouest à Nord. Ces avalanches pourront alors emporter l'ensemble des chutes de neige en cours mais, la sous-couche étant bien dense ou dure, seule cette neige récente (7 à 15 cm) est mobilisable.

Départs spontanés : Avec la neige fraîche au dessus de 2000 m et un peu de vent, quelques nouvelles petites plaques superficielles, peuvent se former plutôt en secteur Nord et Ouest à proximité des crêtes et des cols. Déclenchement possible au passage d'un skieur, pouvant engendrer des avalanches généralement de taille 1 (petite), ne mobilisant pas beaucoup de neige. Départs ponctuels sous les skis ou raquettes de neige humide taille 1 à 2 suivant l'altitude.

Qualité de la neige

Qualification de l'enneigement : L'enneigement est excellent pour la saison au-dessus de 1600 m. Au Val d'Ese, on relève encore près d'1 mètre de neige à la station. À Ghisoni Capanelle, 1m70 mètres au-dessus de 1800 m et un peu moins de 3 mètres dans les combes abritées.

Limite d'enneigement skiable : autour de 1500 m.

État de la neige :Sous l'effet de plus d'une semaine de soleil et de douceur, le manteau neigeux s'est considérablement tassé et il est bien consolidé malgré un regel nocturne quasi inexistant et ne concernant souvent que les pentes nord et les hauts sommets. L'humidification est fortement accélérée sous 2000m avec les pluies. La neige y devient rapidement lourde et humide. En Nord, l'humidification est plus lente, elle ne se produit qu'en dessous de 2000m. Au-dessus de 2000 m, la neige reste dure ou cartonnée parfois avec quelques cm de neige récente. Nombreuses zones de neige colorée avec les dernières remontée de sable.
À noter la présence de corniches parfois volumineuses.

Aperçu météo pour le samedi 07 mars

	nuit	matin	après-midi	soir
Pluie-Neige	1 700 m	1 800 m	2 000 m	
Iso 0 °C	2 100 m	2 200 m	2 300 m	2 300 m
Vent 1500 m	← 45 km/h	← 30 km/h	← 20 km/h	← 20 km/h
Vent 2000 m	← 45 km/h	← 35 km/h	↑ 10 km/h	↑ 10 km/h

Épaisseur de neige hors-piste

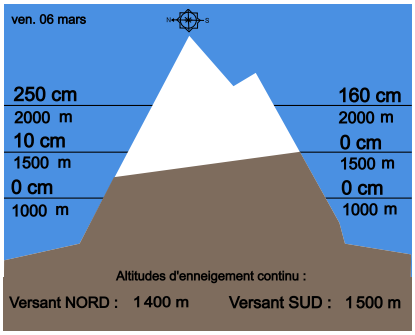

Précipitations à 1800 m

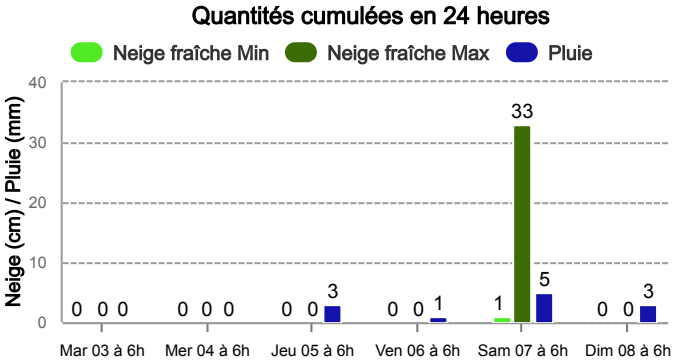

Tendance du dimanche 08 mars

2

Indice de risque limité

Persistance du risque d'avalanches de neige humide.

Pour consulter la vigilance en cours, veuillez vous rendre sur le site https://vigilance.meteofrance.fr/fr

Météo-France - 73 avenue de Paris, 94165 Saint-Mandé cedex - Contact : contact@meteo.fr

Rédigé par Météo-France avec la contribution des observateurs du réseau nivo-météorologiques. Partenariat : ANMSM (Maires de Stations de Montagne), DSF (Domaines Skiables de France), ADSP (Directeurs de Pistes et de la Sécurité des Stations de Sports d'Hiver) et autres acteurs de la montagne.

Bulletin neige & avalanches par téléphone au
0 892 68 10 20 Service 0,35 € / min + prix appel

RÉPUBLIQUE FRANÇAISE
Liberté Égalité Fraternité

METEO FRANCE
À VOS CÔTÉS, DANS UN CLIMAT QUI CHANGE

Bulletin d'estimation du risque d'avalanche

(valable en dehors des pistes balisées et ouvertes)

MASSIF : Renoso Incudine

Rédigé le vendredi 6 mars 2026 à 16h

Conditions nivo-météo des 7 derniers jours

	sam. 28/02				dim. 01/03				lun. 02/03				mar. 03/03				mer. 04/03				jeu. 05/03				ven. 06/03			
	03h	09h	15h	21h	03h	09h	15h	21h	03h	09h	15h	21h	03h	09h	15h	21h	03h	09h	15h	21h	03h	09h	15h	21h	03h	09h	15h	21h
Météo																												
Vent (km/h)	10	10	10	10	5	10	10	10	15	30	15	15	10	5	5	10	10	5	5	0	30	45	45	40	60	70	60	50
à 2000m																												
Vent (km/h)	5	10	10	10	5	10	15	10	10	20	20	15	20	30	30	25	25	20	20	15	25	40	40	35	45	55	50	40
à 1500m																												

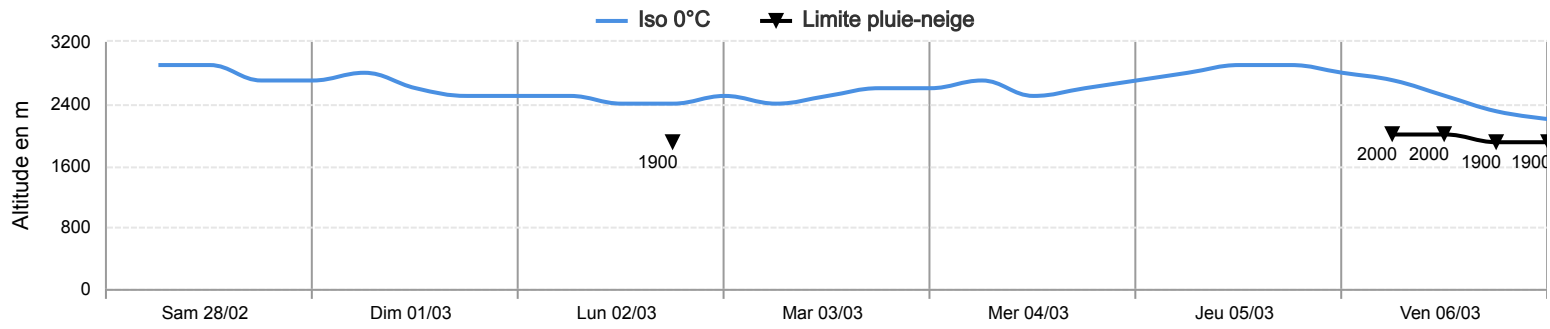

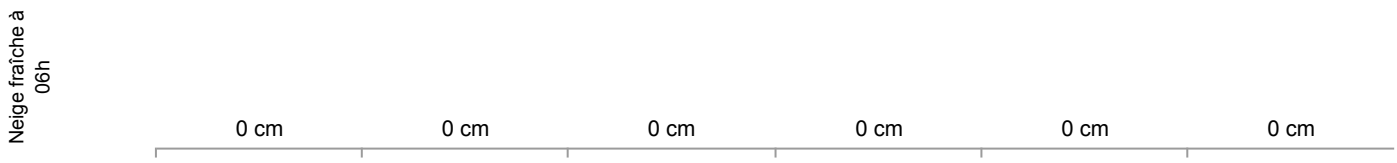

Risque d'avalanche	sam. 28/02	dim. 01/03	lun. 02/03	mar. 03/03	mer. 04/03	jeu. 05/03	ven. 06/03
	2	2	2	2	2	2	2

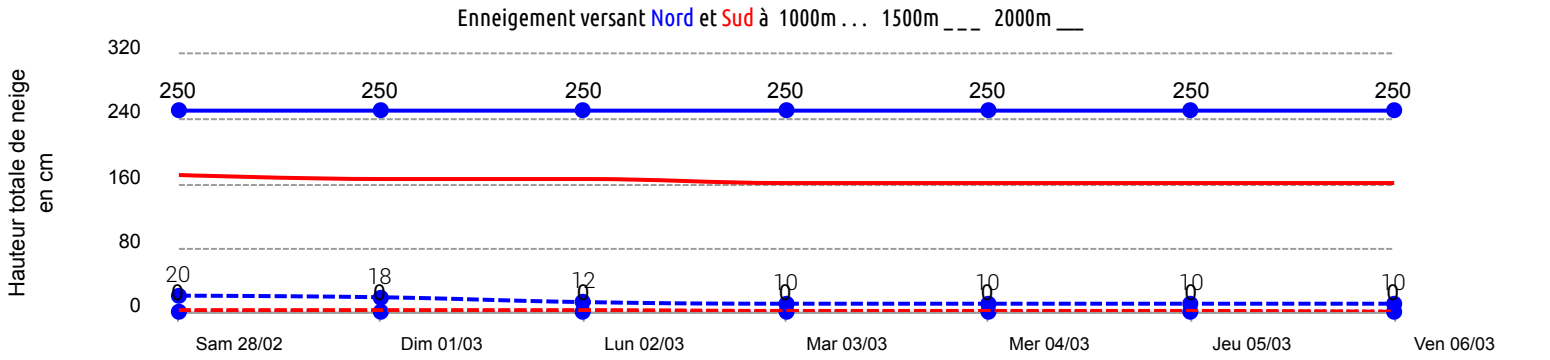

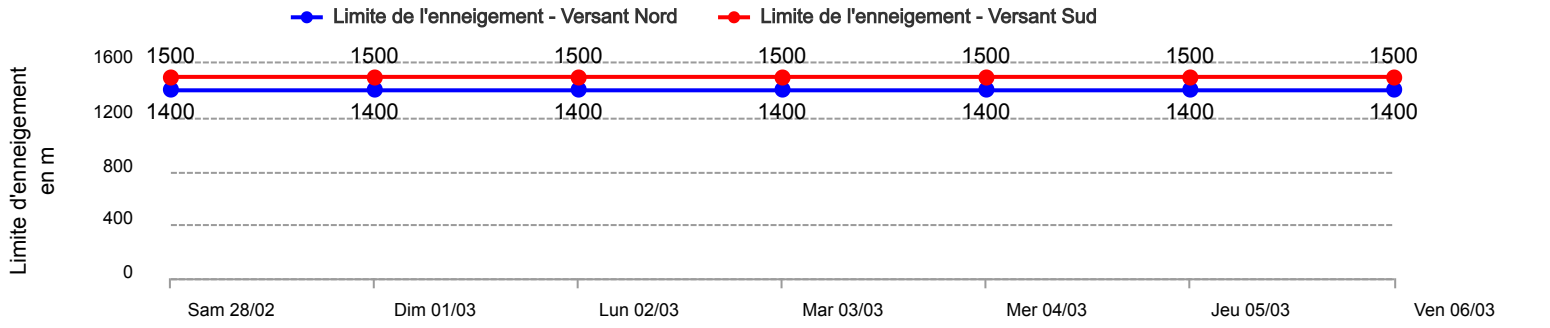

Pour consulter la vigilance en cours, veuillez vous rendre sur le site https://vigilance.meteofrance.fr/fr

Météo-France - 73 avenue de Paris, 94165 Saint-Mandé cedex - Contact : contact@meteo.fr

Rédigé par Météo-France avec la contribution des observateurs du réseau nivo-météorologiques. Partenariat : ANMSM (Maires de Stations de Montagne), DSF (Domaines Skiables de France), ADSP (Directeurs de Pistes et de la Sécurité des Stations de Sports d'Hiver) et autres acteurs de la montagne.

Bulletin neige & avalanches par téléphone au
0 892 68 10 20 Service 0,35 € / min + prix appel