Bulletin d'estimation du risque d'avalanche

(valable en dehors des pistes balisées et ouvertes)

MASSIF : Cerdagne Canigou

Rédigé le vendredi 6 mars 2026 à 17h

Estimation des risques pour le : SAMEDI 07 MARS

MANTEAU NEIGEUX INSTABLE DU FAIT DES CUMULS DE NEIGE FRAÎCHE CONSÉQUENTS EN ALTITUDE ET D'UN MANTEAU PROFONDÉMENT HUMIDIFIÉ AUX ALTITUDES INFÉRIEURES

3

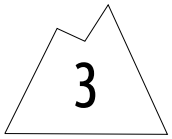

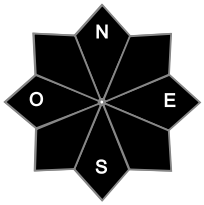

Indice de risque marqué.

Départs spontanés : Avalanches de neige humide possible jusqu'au sol sous 2100m, quelques grandes avalanches de neige sèche en altitude

Déclenchements provoqués : Nombreuses structures de plaques dans la neige fraîche

Indices de risque : 5 très fort - 4 fort - 3 marqué - 2 limité - 1 faible -- En noir : les pentes les plus dangereuses

Stabilité du manteau neigeux

Situation avalancheuse typique : neige fraîche neige humide

Cumuls de neige fraîche conséquents en haute-montagne avec plus d'un mètre sur l'ensemble de l'épisode vers le Canigou, un peu moins vers le Puigmal

Déclenchements provoqués :

En tous versants, mais surtout sous le vent d'Est à Sud-Est, au-dessus de 2200/2300m, des déclenchements d'avalanches sont possibles au passage d'un skieur. Les avalanches sont plutôt de taille moyenne ou grande vu les cumuls de neige fraîche disponibles, voire très grande du massif du Canigou au Roca Colom. En effet, des structures de plaques se sont formées pendant les chutes de neige et continuent de se former. Ces plaques sont difficilement détectables.

En tous versants sous 2200/2300m un skieur peut facilement provoquer des coulées de neige humide sous les skis dans la neige récente gorgée d'eau sans cohésion, pouvant provoquer la chute du skieur. Selon la configuration du terrain, un skieur peut se retrouver enseveli.

Observables: en altitude quantités critiques de neige fraiche (30/50 cm et localement plus), fissures sous les skis, avalanche dans la neige récente en pente raide ; plus bas neige humide sans cohésion partant sous les skis

Départs spontanés :

- Avalanches de neige humide attendues sous 2100 m, moyenne à grande, du fait d'une humidification toujours plus en profondeur notamment dans les pentes raides de secteur Nord-Est où les quantités de neige en place sont conséquentes.
- Avalanches de neige sèche possibles en altitude avec les averses par surcharge des plaques présentes dans la neige récente. Ces avalanches pourront alors emporter l'ensemble de la neige récente d'où de possibles grandes avalanches, parfois très grandes dans les secteurs d'accumulation de haute-montagne.

Qualité de la neige

Enneigement :

L'enneigement en altitude est largement supérieur à celui des cinq dernières années et se situe au plus haut par rapport aux statistiques plus anciennes. Malgré la douceur il est en général possible de chausser dès 1600m d'altitude. La limite skiable remonte toutefois dans les pentes ensoleillées. Le manteau neigeux atteint rapidement 1m d'épaisseur et dépasse encore les 2m au-dessus de 2200m avec localement en haute-montagne plus d'un mètre de neige fraîche notamment sur le massif du Canigou.

Qualité de la neige :

Neige lourde et très humide en tous versants sous 2000/2200m, dense aux altitudes les plus basses. Plus haut, plutôt à partir de 2400 m, on trouvera une épaisse couche de neige fraîche.

Aperçu météo pour le samedi 07 mars

	nuit	matin	après-midi	soir
Averses plus fréquentes l'après-midi				
Pluie-Neige	1 800 m	1 800 m	1 800 m	1 700 m
Iso 0 °C	2 100 m	2 200 m	2 300 m	2 100 m
Vent 2000 m	40 km/h	40 km/h	40 km/h	30 km/h
Vent 3000 m	65 km/h	60 km/h	50 km/h	45 km/h

Épaisseur de neige hors-piste

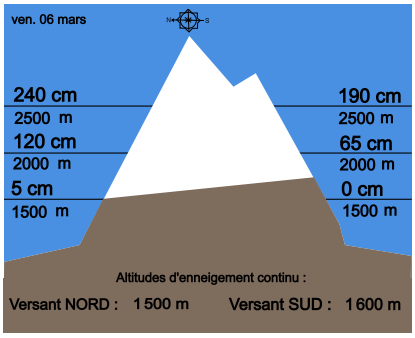

Précipitations à 1800 m

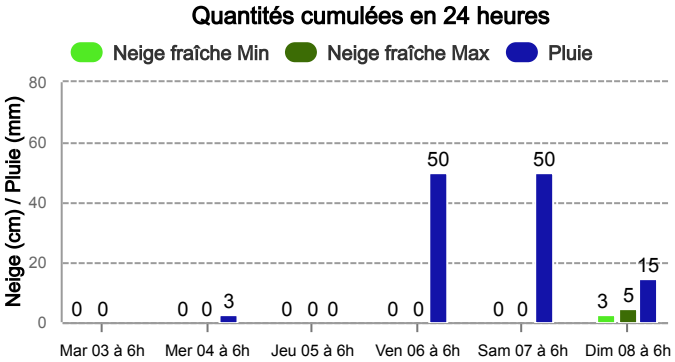

Tendance du dimanche 08 mars

3

Indice de risque marqué

Maintien probable d'un risque marqué en haute-montagne malgré un début de stabilisation

Pour consulter la vigilance en cours, veuillez vous rendre sur le site https://vigilance.meteofrance.fr/fr

Météo-France - 73 avenue de Paris, 94165 Saint-Mandé cedex - Contact : contact@meteo.fr

Bulletin neige & avalanches par téléphone au 0 892 68 10 20 Service 0,35 € / min + prix appel

Rédigé par Météo-France avec la contribution des observateurs du réseau nivo-météorologiques. Partenariat : ANMSM (Maires de Stations de Montagne), DSF (Domaines Skiables de France), ADSP (Directeurs de Pistes et de la Sécurité des Stations de Sports d'Hiver) et autres acteurs de la montagne.

RÉPUBLIQUE FRANÇAISE
Liberté Égalité Fraternité

METEO FRANCE
À VOS CÔTÉS, DANS UN CLIMAT QUI CHANGE

Bulletin d'estimation du risque d'avalanche

(valable en dehors des pistes balisées et ouvertes)

MASSIF : Cerdagne Canigou

Rédigé le vendredi 6 mars 2026 à 17h

Conditions nivo-météo des 7 derniers jours

	sam. 28/02				dim. 01/03				lun. 02/03				mar. 03/03				mer. 04/03				jeu. 05/03				ven. 06/03			
	03h	09h	15h	21h	03h	09h	15h	21h	03h	09h	15h	21h	03h	09h	15h	21h	03h	09h	15h	21h	03h	09h	15h	21h	03h	09h	15h	21h
Météo																												
Vent (km/h)	30	30	30	20	20	25	25	25	40	50	50	40	45	35	25	25	40	35	40	25	45	50	50	50	60	60	60	55
à 3000m																												
Vent (km/h)	15	15	20	10	10	15	20	15	20	30	30	25	30	25	20	15	25	20	25	15	30	30	30	30	35	35	45	30
à 2000m																												

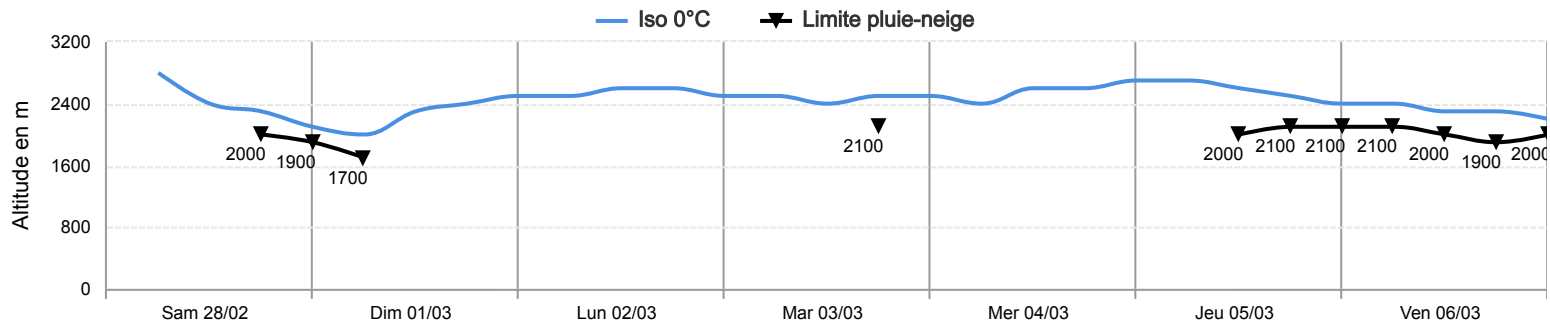

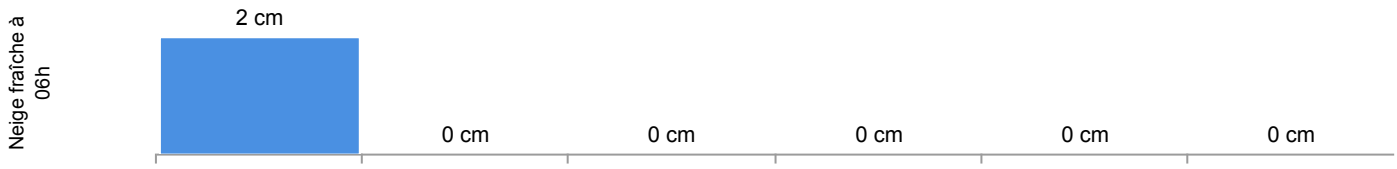

Risque d'avalanche	sam. 28/02	dim. 01/03	lun. 02/03	mar. 03/03	mer. 04/03	jeu. 05/03	ven. 06/03
	2	2	2	2	2	3	3

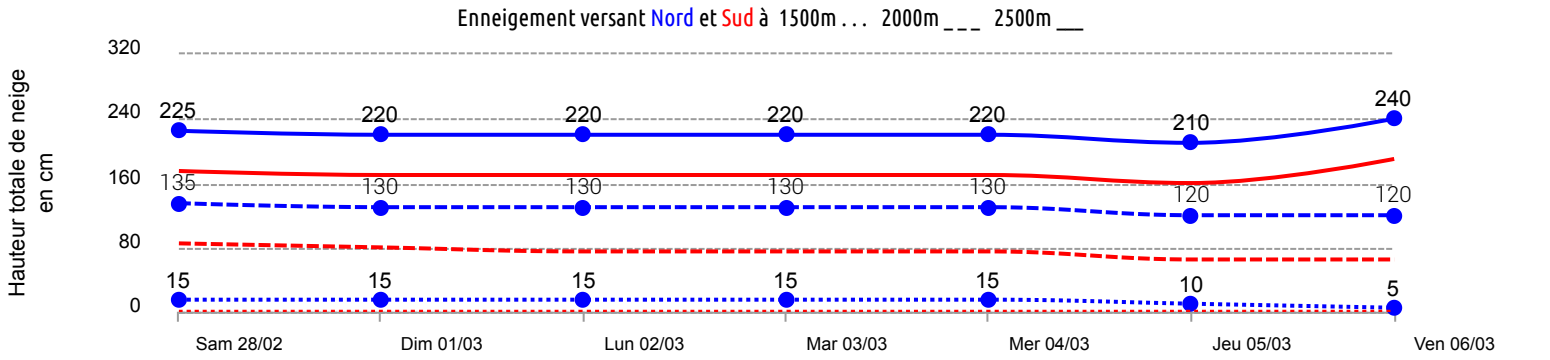

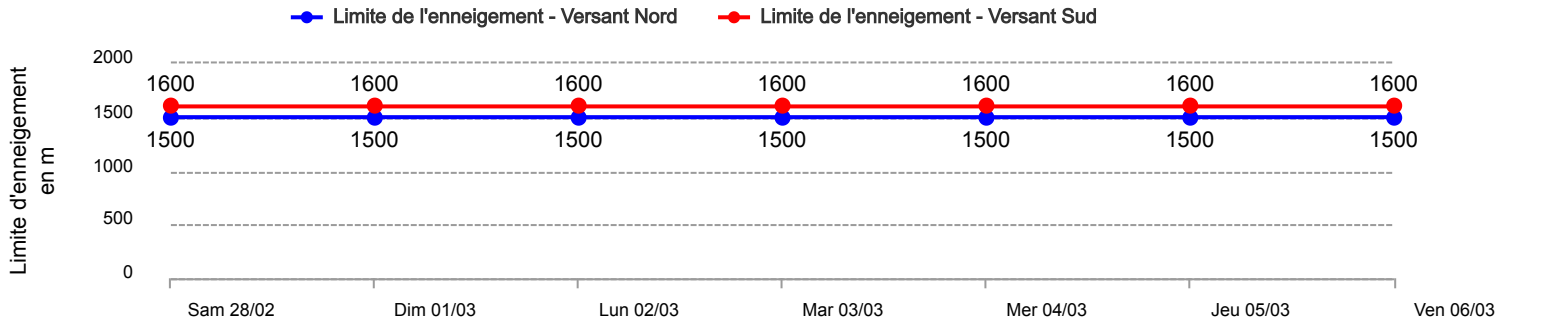

Pour consulter la vigilance en cours, veuillez vous rendre sur le site https://vigilance.meteofrance.fr/fr

Météo-France - 73 avenue de Paris, 94165 Saint-Mandé cedex - Contact : contact@meteo.fr

Rédigé par Météo-France avec la contribution des observateurs du réseau nivo-météorologiques. Partenariat : ANMSM (Maires de Stations de Montagne), DSF (Domaines Skiables de France), ADSP (Directeurs de Pistes et de la Sécurité des Stations de Sports d'Hiver) et autres acteurs de la montagne.

Bulletin neige & avalanches par téléphone au
0 892 68 10 20 Service 0,35 € / min + prix appel