GOBIERNO DE ESPAÑA
VICEPRESIDENCIA TERCERA DEL GOBIERNO
MINISTERIO PARA LA TRANSICIÓN ECOLÓGICA Y EL RETO DEMOGRÁFICO

Boletín de información nivológica y de peligro de aludes

Pirineo Navarro y Aragonés

aemet Agencia Estatal de Meteorología

sábado, 7 de marzo de 2026

Pronóstico hasta las 24 horas del domingo, día 8 de marzo

(Válido fuera de pistas de esquí balizadas y abiertas)

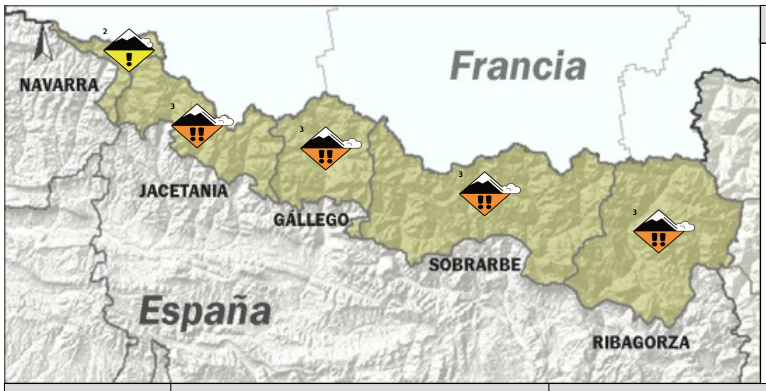

Problemas de aludes

- Nieve reciente
- Placas de viento
- Nieve húmeda

Macizo	Peligro	Problemas de aludes, cota, orientación, tamaño	Innivación observada (m)
Navarra	2 / 2 — Limitado	Nieve reciente: 2100; N, O, E, S; 2 Nieve húmeda: 2100; N, O, E, S; 2	2026-03-07 N / S Cota más baja caras N
Jacetania	3 / 3 2200 / 2 — Notable	Nieve reciente: 2100; N, O, E, S; 2 Placas de viento: 2400; N, O, E, S; 2	2026-03-07 N / S Cota más baja caras N
Gállego	3 / 3 2200 / 2 — Notable	Nieve reciente: 2100; N, O, E, S; 2 Placas de viento: 2400; N, O, E, S; 2	2026-03-07 N / S Cota más baja caras N

AEMET. Se autoriza la reproducción de su contenido citando la fuente.

Sobrarbe	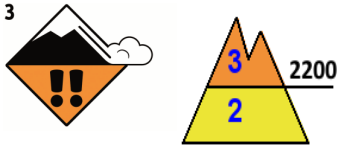 **Notable**	**Nieve reciente** 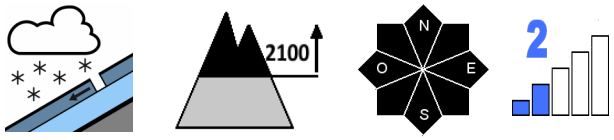 **Placas de viento** 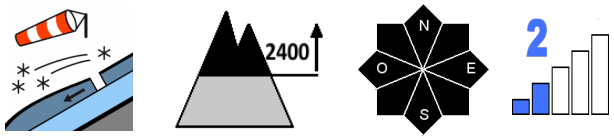	2026-03-07 Cota más baja caras N
Ribagorza	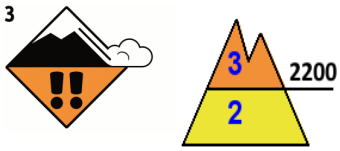 **Notable**	**Nieve reciente** 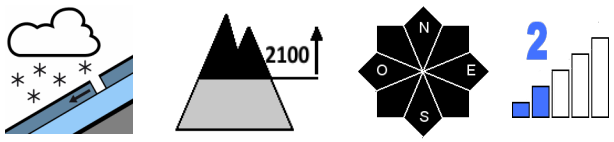 **Placas de viento** 	2026-03-07 Cota más baja caras N

Estado del manto y observaciones recientes

Pese a la presencia de nieve en numerosos fondos de valle el manto ha perdido continuidad en cotas bajas, siendo todavía abundante desde medianías, aunque se empieza a notar cierta erosión en las solanas. Los espesores se van incrementando conforme ascendemos, de tal manera que siguen superándose los 120 a 200 cm por encima de 2.100 metros, cantidades que pueden verse incrementadas notablemente en ventisqueros, hoyas y otras zonas propensas a la acumulación.

El manto está humedecido hasta su base en cotas medias y bajas. Por encima de unos 2.100 ó 2.200 metros la nieve se presenta generalmente más seca y venteada, y aún podemos encontrar en umbrías de la alta montaña estratos débiles en la base del manto, generalmente inactivos. En capas superficiales se ha depositado algo de polvo sahariano que ha podido quedar enterrado por las últimas nevadas.

Evolución del manto y peligro de aludes para el domingo, día 8

Situación de nieve reciente, y placas de viento en la alta montaña.

Durante las próximas 24 horas se prevén nevadas en la cordillera, que irán depositando nuevos espesores de nieve reciente sobre los ya acumulados en jornadas previas, principalmente en cotas altas, donde es probable que puedan darse algunas purgas espontáneas en pendientes con suficiente inclinación y sin orientación preferente, siendo, por lo general, de tamaño pequeño o mediano, sin descartarse tampoco alguna salida local de nieve húmeda en medianías y zonas bajas.

En la alta montaña se formarán nuevas placas de viento en orientaciones oeste y norte, principalmente en las cercanías de crestas y collados, que vendrán a sumarse a las que ya existen en diferentes orientaciones y que permanecen aún activas. Estas estructuras podrán

AEMET. Se autoriza la reproducción de su contenido citando la fuente.

fracturarse ante sobrecargas débiles, como es el paso de un esquiador, dando lugar a aludes de dimensiones medianas, tamaño más que suficiente para enterrar a una persona, por lo que se recomienda tomar precauciones si se va a transitar por la zona.

Predicción meteorológica para el domingo, día 8

Predominio de cielos muy nubosos o cubiertos, aunque con apertura ocasional de claros. Se esperan precipitaciones débiles o localmente moderadas, en ocasiones en forma de chubascos. Cota de nieve: 1.200 a 1.400 metros, aunque podrá subir algo por la tarde. Temperaturas sin cambios o en ligero descenso. Heladas débiles, moderadas y persistentes en cotas altas, donde podrán ser localmente fuertes. Soplarán vientos flojos o moderados del sur y sudeste.

Datos en la atmósfera libre:

Altitud de la isoterma de 0 ºC: 1.800 m
Altitud de la isoterma de -10 ºC: 3.300 m

Viento a 1500 m: SE 20 km/h
Viento a 3000 m: SE 30 km/h

Evolución para el lunes día 9

Nivel de peligro con pocos cambios.

(Información elaborada a partir de los datos recibidos de los refugios de Linza, Lizara, Panticosa, Góriz, Pineta, Estós, Angel Orús, La Renclusa, Cap de Llauset y Belagua, de las estaciones de esquí de Formigal y Panticosa (lagos), de la estación de esquí de fondo de Llanos del Hospital y de Ordesa Pradera)

Escala europea de peligro de aludes

Débil | Limitado | Notable | Fuerte | Muy Fuerte

Problemas de aludes

Nieve reciente | Placas de viento | Capas débiles persistentes | Nieve húmeda | Deslizamientos basales | Sin problema evidente

Nota1: Se recuerda que, siempre que haya nieve, la ausencia total de peligro no existe. Hay que tener presente que en circunstancias desfavorables, con aludes de tamaño 1 (alud pequeño o colada) y tamaño 2 (alud mediano), se pueden sufrir severos daños personales.

Nota2: Los BPA se elaboran en base a información meteorológica así como al estado del manto nivoso a través de sondeos puntuales. Se advierte a los usuarios de la variabilidad de esta información al extrapolarla a zonas extensas de montaña. Por ello, AEMET no se hace responsable de su uso para la toma de decisiones que conciernen a la seguridad personal, ni de los riesgos físicos o materiales de ellas derivadas.

AEMET. Se autoriza la reproducción de su contenido citando la fuente.