Sonntag 08.03.2026

Veröffentlicht am 07.03.2026 um 17:00

Vormittag

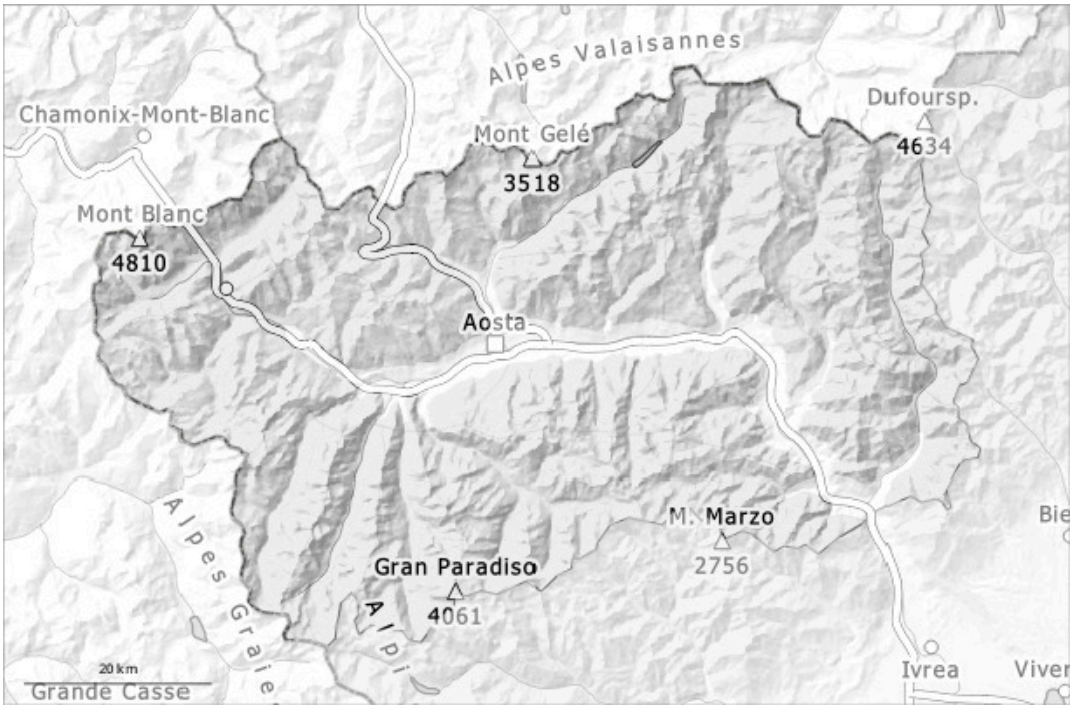

Nachmittag

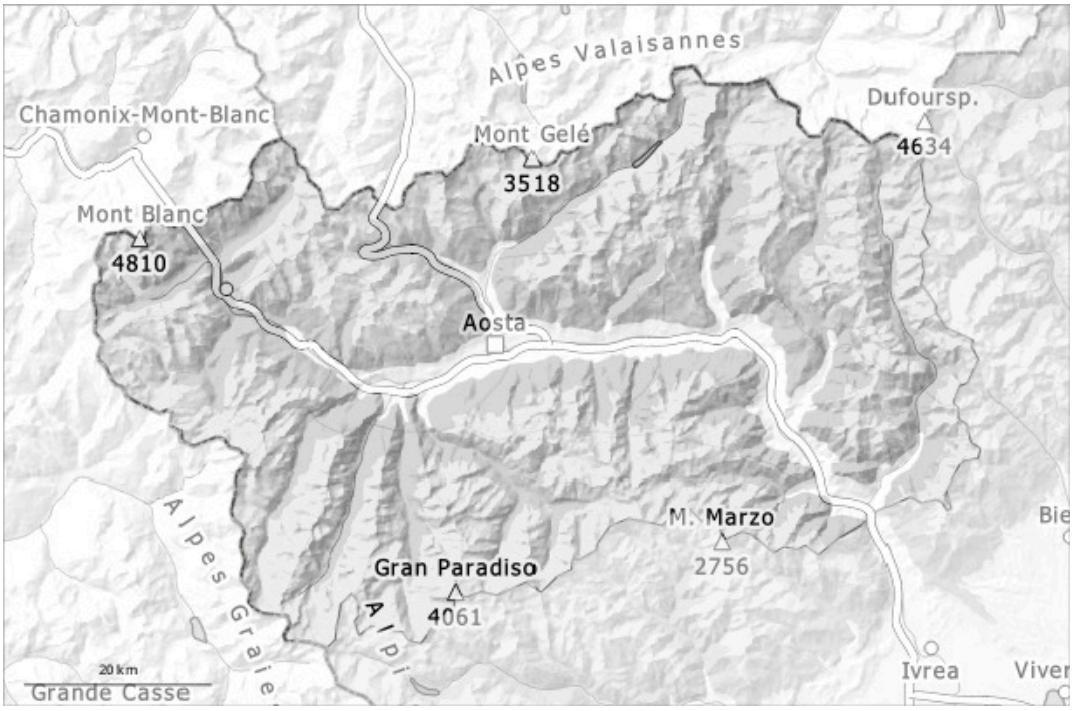

1	2	3	4	5
gering	mäßig	erheblich	groß	sehr groß

Gefahrenstufe 2 - Mäßig

AM:

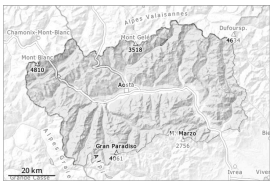

Tendenz: Lawinengefahr bleibt gleich
am Montag, den 09.03.2026

Altschnee

2400m

PM:

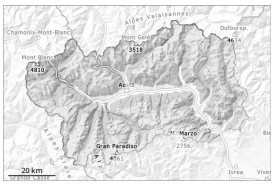

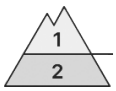

2400m

Tendenz: Lawinengefahr bleibt gleich
am Montag, den 09.03.2026

Nassschnee

2400m
2000m

Altschnee

2400m

Die Tourenverhältnisse sind mehrheitlich günstig.

Die Schneeoberfläche gefriert tragfähig weicht im Tagesverlauf auf, vor allem unterhalb von rund 2000 m. Leichter Anstieg der Gefahr mit der tageszeitlichen Erwärmung.
Vor allem in mittleren Lagen sind im Tagesverlauf einzelne meist kleine feuchte und nasse Lawinen möglich, v.a. aus extrem steilen noch nicht vollständig entladenen Einzugsgebieten.
Tiefer in der Schneedecke sind Schwachschichten vorhanden. Lawinen können sehr vereinzelt in tiefen Schichten ausgelöst werden und vereinzelt mittlere Größe erreichen. Diese Gefahrenstellen liegen vor allem an eher schneearmen Stellen sowie im selten befahrenen Tourengelände.

Schneedecke

Gefahrenmuster gm.1: bodennahe schwachschicht | gm.10: frühjahrssituation

Die Wetterbedingungen begünstigten v.a. an Sonnenhängen eine Verfestigung der Schneedecke. Der obere Teil der Schneedecke ist weitgehend stabil, mit einer oft tragfähigen Schmelzharschkruste an der Oberfläche. Dort besteht im Steilgelände Absturzgefahr.
Besonders steile Schattenhänge hohe Lagen und Hochgebirge: In der Altschneedecke sind Schwachschichten vorhanden. Der obere Teil der Schneedecke ist aufbauend umgewandelt, mit einer Oberfläche aus kantig aufgebauten Kristallen.
In Kamm- und Passlagen sowie in hohen Lagen liegen je nach Windeinfluss sehr unterschiedliche Schneehöhen.
In den letzten Tagen wurden kaum mehr Lawinen gemeldet.

Tendenz

Die Verhältnisse für Touren und zum Freeriden sind meist günstig. Auf der harten Schneeoberfläche besteht im Steilgelände Absturzgefahr. Allmählicher Rückgang der Gefahr von feuchten und nassen Lawinen mit der Abkühlung.