# Domenica 08.03.2026

Pubblicato il 07.03.2026 alle ore 17:00

## Mattina

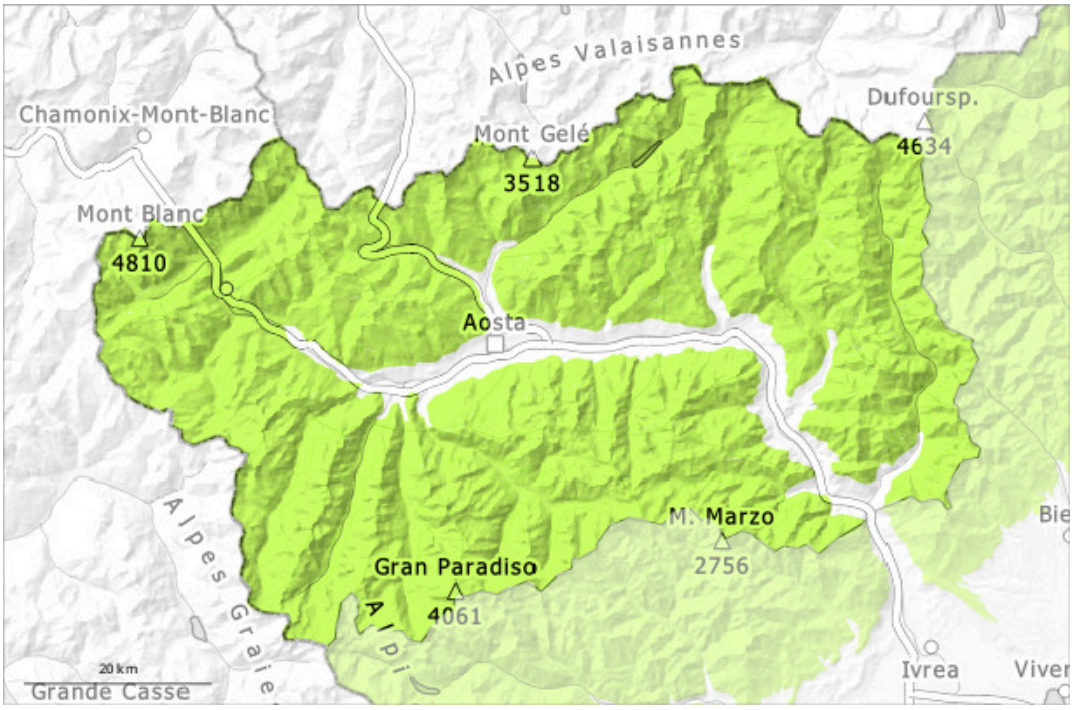


## pomeriggio

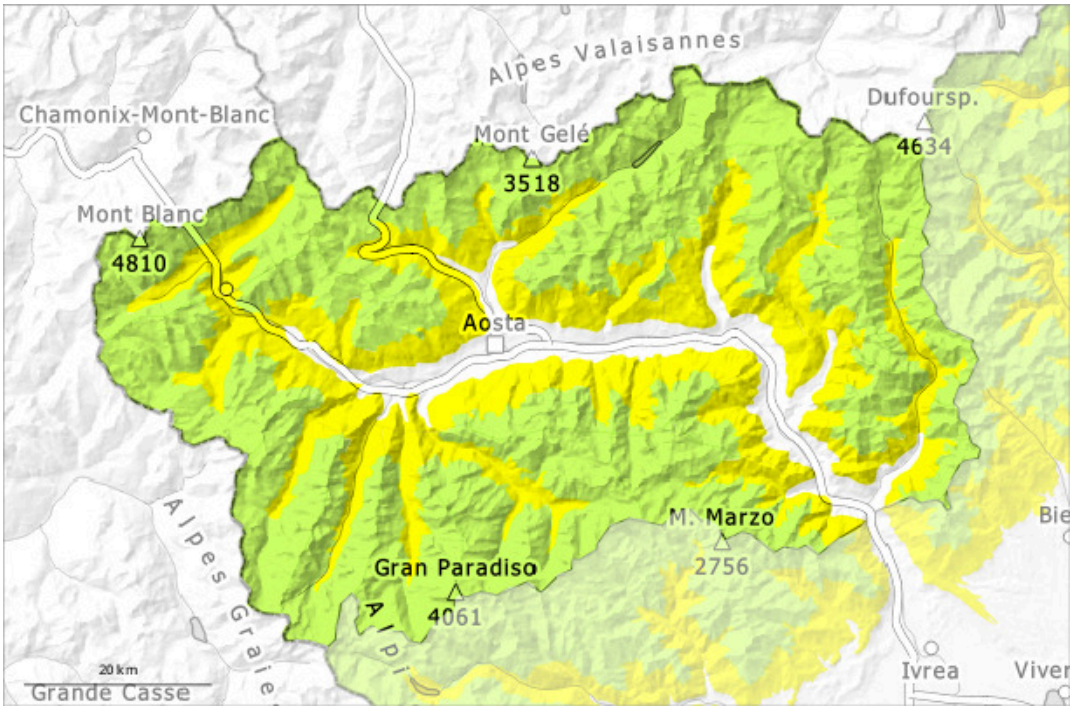


| 1 | 2 | 3 | 4 | 5 |
|---|---|---|---|---|
| debole | moderato | marcato | forte | molto forte |

# Domenica 08.03.2026

Pubblicato il 07.03.2026 alle ore 17:00

## Grado di pericolo 2 - Moderato

### AM:

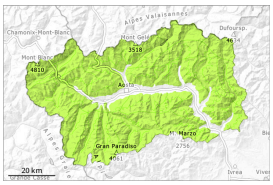

**Tendenza: pericolo valanghe stabile**
per Lunedì il 09.03.2026

Strati deboli persistenti

2400m

### PM:

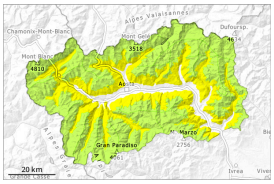

2400m

**Tendenza: pericolo valanghe stabile**
per Lunedì il 09.03.2026

Neve bagnata

2400m
2000m

Strati deboli persistenti

2400m

## Le condizioni per le escursioni sono per lo più favorevoli.

La superficie del manto nevoso riuscirà a rigelarsi e a essere portante si ammorbidirà nel corso della giornata, specialmente al di sotto dei 2000 m circa.
Con il rialzo termico diurno, leggero aumento del pericolo.
Nel corso della giornata, soprattutto alle quote di media montagna sono possibili isolate valanghe umide e bagnate per lo più di piccole dimensioni, principalmente dai bacini di alimentazione ripidi estremi non ancora completamente scaricati.
Negli strati più profondi del manto nevoso si trovano strati fragili. Le valanghe possono a livello molto isolato subire un distacco negli strati più profondi e raggiungere dimensioni medie a livello isolato. Questi punti pericolosi si trovano soprattutto nelle zone scarsamente innevate come pure nelle zone escursionistiche poco frequentate.

## Manto nevoso

**Situazione tipo** st.1: strato debole persistente basale | st.10: situazione primaverile

Le condizioni meteo hanno favorito un consolidamento del manto nevoso specialmente sui pendii soleggiati. La parte superiore del manto nevoso è per lo più stabile, con una crosta da rigelo spesso portante in superficie. Qui sussiste un pericolo di caduta nelle zone ripide.
Principalmente sui pendii ripidi ombreggiati ad alta quota e in alta montagna: All'interno del manto di neve vecchia si trovano strati fragili. La parte superiore del manto nevoso ha subito un metamorfismo costruttivo, con una superficie trasformata in cristalli sfaccettati.

Nelle zone in prossimità delle creste e dei passi così come ad alta quota l'innevamento è estremamente variabile a seconda dell'azione del vento.
Negli ultimi giorni, non sono praticamente più state segnalate valanghe.

## Tendenza

Le condizioni per le escursioni e il freeride sono generalmente favorevoli. Sulla dura superficie del manto nevoso sussiste un pericolo di caduta nelle zone ripide. Con il raffreddamento, progressivo calo del pericolo di valanghe umide e bagnate.