ICGC Institut Cartogràfic i Geològic de Catalunya

Servei Meteorològic de Catalunya meteo.cat

Boletín de peligro de aludes para el Pirineo de Catalunya
Del 07/03/2026 al 09/03/2026

(Válido fuera pistas de esquí y zonas no controladas)

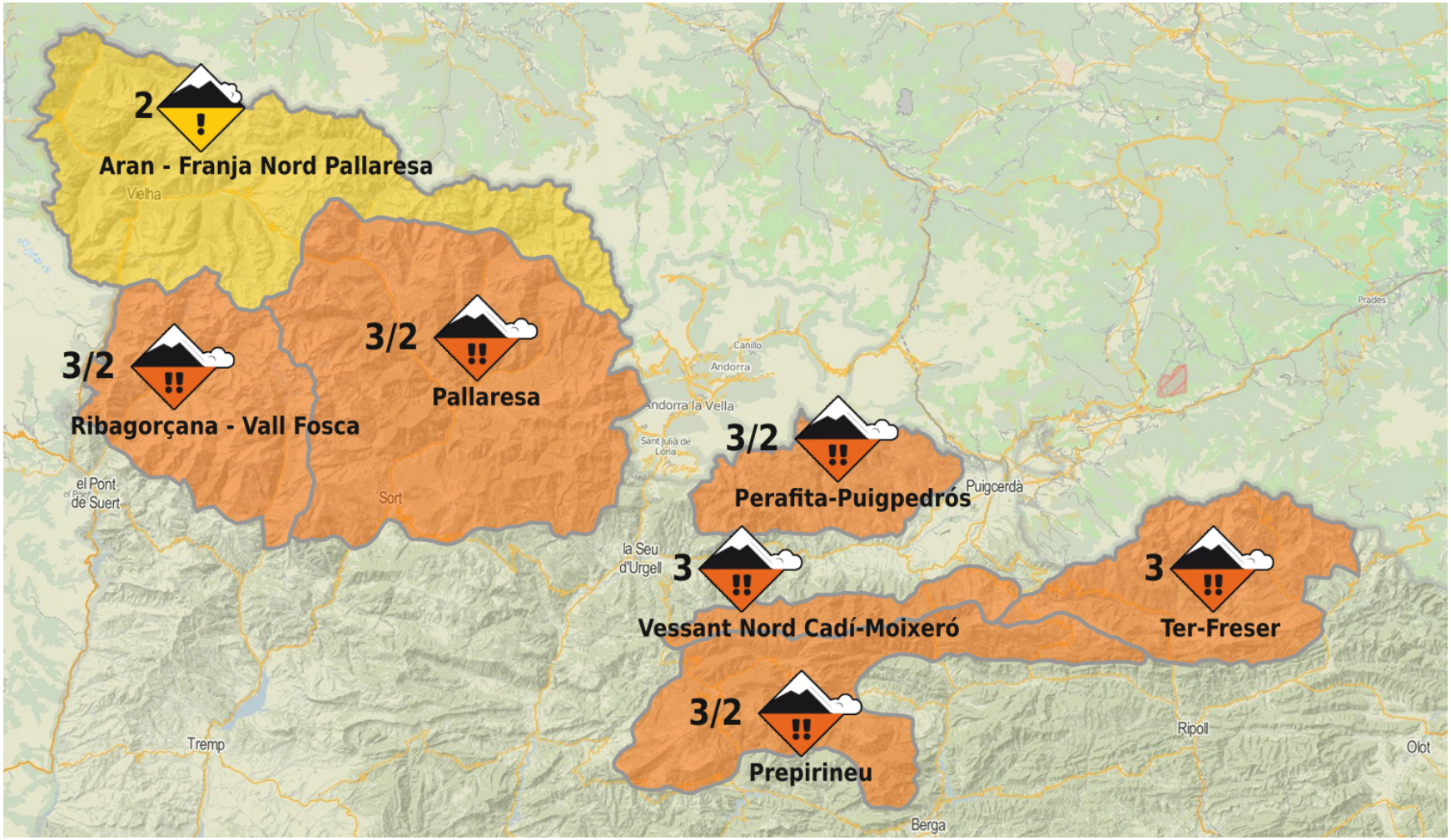

5 MUY FUERTE	4 FUERTE	3 NOTABLE	2 LIMITADO	1 DÉBIL

ICGC Institut Cartogràfic i Geològic de Catalunya

meteo.cat Servei Meteorològic de Catalunya

Boletín de peligro de aludes Aran - Franja Nord Pallaresa Del 07/03/2026 al 09/03/2026

(Válido fuera pistas de esquí y zonas no controladas)

LIMITADO (2).

Situación primaria

Nieve venteada

Distribución

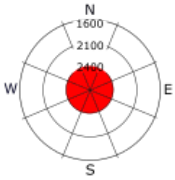

Tamaño

Origen

Tendencia

Situación secundaria

Nieve húmeda

Distribución

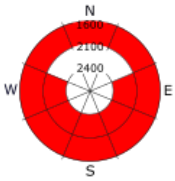

Tamaño

Origen

Tendencia

Estado del manto nivoso

El domingo por encima de 2.200 m encontraremos unos 10-20 cm de nieve reciente (sólo unos pocos cm en la mitad norte del Aran), más seca que días atrás, por encima de un manto ligeramente encostrado internamente. En las cotas más altas, bajo collados y cordales se han formado placas de viento sobre todo en orientaciones norte y oeste, que caen al paso de una persona como placas blandas; por lo general de tamaño 2, mediano, suficiente para cubrir una persona. Debido a los ratos de insolación caerán aludes de nieve húmeda en las vertientes soleadas, en general serán de tamaño 1, pequeño, suficiente para hacernos caer y arrastrarnos. Todavía se espera algún deslizamiento basal en las vertientes típicamente herbosas, por lo general de tamaño 2, mediano. El lunes se mantiene la misma situación.

Distribución del manto nivoso

Hay nieve por encima de unos 1.400-1-500 m en umbrías y 1.700 m en solanas. Los espesores a unos 2.200 m son superiores a los normales en la Franja Norte de la Pallaresa y en la mitad sur del Aran donde rondan los 180-220 cm. En la mitad norte de Arán hay unos 120-140 cm de grosor total.

Tendencia para las próximas 48-72h

Se tiende hacia un manto más seco en cotas altas con formación de más placas de viento en orientaciones norte. Peligro ESTACIONARIO.

El próximo boletín será emitido el día 2026-03-09

5 MUY FUERTE	4 FUERTE	3 NOTABLE	2 LIMITADO	1 DÉBIL

EAWS EUROPEAN AVALANCHE WARNING SERVICES

ICGC Institut Cartogràfic i Geològic de Catalunya

meteo.cat Servei Meteorològic de Catalunya

Boletín de peligro de aludes Ribagorçana - Vall Fosca Del 07/03/2026 al 09/03/2026

(Válido fuera pistas de esquí y zonas no controladas)

NOTABLE (3) por encima de 2.200 m.
ºLIMTADO (2) por debajo.

Situación primaria

Nieve reciente

Distribución

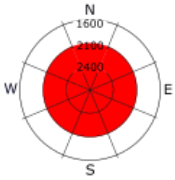

Tamaño

Origen

Tendencia

Situación secundaria

Nieve venteada

Distribución

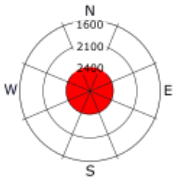

Tamaño

Origen

Tendencia

Estado del manto nivoso

El sábado se puede acumular algo más de nieve reciente (máximo unos 5 cm). Por la mañana del domingo por encima de 2.300 m encontraremos unos 30 cm de nieve reciente, más seca que días atrás, por encima de un manto ligeramente encostrado internamente. Por encima de 2.200 m caerán aludes de nieve reciente de forma natural en laderas de fuerte pendiente y en cualquier orientación; serán de tamaño 2, mediano, con capacidad de enterrar a una persona; caerán como placas blandas. En las cotas más altas, bajo collados y cordales se puede haber formado alguna placa de viento sobre todo en orientaciones norte y oeste, que caerá al paso de una persona; en general de tamaño 2, madiano. El lunes se mantiene la misma situación. Se recomienda no aventurarse por sitios no conocidos, ya que la falta de visibilidad a ratos nos impedirá identificar terreno avalanchoso.

Distribución del manto nivoso

Hay nieve en el suelo a 1.600 m en terreno umbrío, y por encima de unos 1.800 m en laderas soleadas. El manto es esquiable por encima de unos 1.700-1.800 m en umbrías. Los grosores alcanzan los 100-130 cm a unos 2.200 m. Estos valores son aún superiores a los normales para la época.

Tendencia para las próximas 48-72h

Se tiende hacia un manto más seco en cotas altas con formación de más placas de viento en orientaciones norte. Peligro ESTACIONARIO.

El próximo boletín será emitido el día 2026-03-09

5 MUY FUERTE	4 FUERTE	3 NOTABLE	2 LIMITADO	1 DÉBIL

EAWS EUROPEAN AVALANCHE WARNING SERVICES

ICGC Institut Cartogràfic i Geològic de Catalunya

Servei Meteorològic de Catalunya meteo.cat

Boletín de peligro de aludes Pallaresa
Del 07/03/2026 al 09/03/2026

(Válido fuera pistas de esquí y zonas no controladas)

NOTABLE (3) por encima de 2.200 m.
LIMITADO (2) por debajo.

Situación primaria

Nieve reciente

Distribución

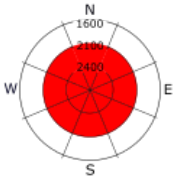

Tamaño

Origen

Tendencia

Situación secundaria

Nieve venteada

Distribución

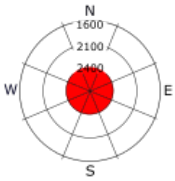

Tamaño

Origen

Tendencia

Estado del manto nivoso

El sábado se puede acumular algo más de nieve reciente (máximo unos 5 cm). Por la mañana del domingo por encima de 2.300 m encontraremos unos 20-25 cm de nieve reciente, más seca que días atrás, por encima de un manto ligeramente encostrado internamente. Por encima de 2.200 m caerán aludes de nieve reciente de forma natural en laderas de fuerte pendiente y en cualquier orientación; serán de tamaño 2, mediano, con capacidad de enterrar a una persona; caerán como placas blandas. En las cotas más altas, bajo collados y cordales se puede haber formado alguna placa de viento sobre todo en orientaciones norte y oeste, que caerá al paso de una persona; en general de tamaño 2, mediano. El lunes se mantiene la misma situación. Se recomienda no aventurarse por sitios no conocidos, ya que la falta de visibilidad a ratos nos impedirá identificar terreno avalanchoso.

Distribución del manto nivoso

Hay nieve en el suelo a 1.600 m en terreno umbrío, y por encima de unos 1.800 m en laderas soleadas. El manto es esquiable por encima de unos 1.700-1.800 m en umbrías. Los grosores alcanzan los 120-160 cm a unos 2.200 m.

Tendencia para las próximas 48-72h

Se tiende hacia un manto más seco en cotas altas con formación de más placas de viento en orientaciones norte. Peligro ESTACIONARIO.

El próximo boletín será emitido el día 2026-03-09

5 MUY FUERTE	4 FUERTE	3 NOTABLE	2 LIMITADO	1 DÉBIL

EAWS EUROPEAN AVALANCHE WARNING SERVICES

ICGC Institut Cartogràfic i Geològic de Catalunya

Servei Meteorològic de Catalunya meteo.cat

Boletín de peligro de aludes Perafita-Puigpedrós Del 07/03/2026 al 09/03/2026

(Válido fuera pistas de esquí y zonas no controladas)

NOTABLE (3) por encima de 2.200 m.
LIMITADO (2) por debajo.

Situación primaria

Nieve reciente

Distribución

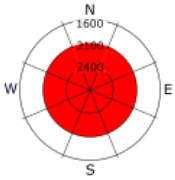

Tamaño

Origen

Tendencia

Situación secundaria

Nieve venteada

Distribución

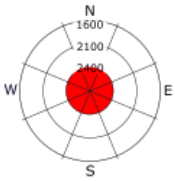

Tamaño

Origen

Tendencia

Estado del manto nivoso

El sábado se puede acumular algo más de nieve reciente (máximo unos 5 cm). Por la mañana del domingo por encima de 2.300 m encontraremos unos 20-25 cm de nieve reciente, más seca que días atrás, por encima de un manto ligeramente encostrado internamente. Por encima de 2.200 m caerán aludes de nieve reciente de forma natural en laderas de fuerte pendiente y en cualquier orientación; serán de tamaño 2, mediano, con capacidad de enterrar a una persona; caerán como placas blandas. En las cotas más altas, bajo collados y cordales se puede haber formado alguna placa de viento sobre todo en orientaciones norte y oeste, que caerá al paso de una persona; en general de tamaño 2, mediano. El lunes se mantiene la misma situación. Se recomienda no aventurarse por sitios no conocidos, ya que la falta de visibilidad a ratos nos impedirá identificar terreno avalanchoso.

Distribución del manto nivoso

Hay nieve en el suelo por encima de unos 1.600-1.700 m. El manto es esquiable por encima de unos 1.800 m. Los espesores, aunque irregulares, rondan los 80-100 cm a 2.200 m. Son grosores por encima de los habituales para la época.

Tendencia para las próximas 48-72h

Se tiende hacia un manto más seco en cotas altas con formación de más placas de viento en orientaciones norte. Peligro ESTACIONARIO.

El próximo boletín será emitido el día 2026-03-09

5 MUY FUERTE	4 FUERTE	3 NOTABLE	2 LIMITADO	1 DÉBIL

EAWS EUROPEAN AVALANCHE WARNING SERVICES

ICGC Institut Cartogràfic i Geològic de Catalunya

Servei Meteorològic de Catalunya meteo.cat

Boletín de peligro de aludes
Vessant Nord Cadí-Moixeró
Del 07/03/2026 al 09/03/2026

(Válido fuera pistas de esquí y zonas no controladas)

NOTABLE (3)

Situación primaria

Nieve reciente	Distribución	Tamaño	Origen	Tendencia
	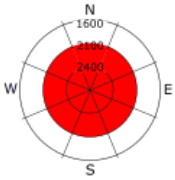			

Estado del manto nivoso

El sábado se puede acumular algo más de nieve reciente (5-10 cm). El domingo encontraremos nieve reciente, a 2.200 m unos 20-30 cm, más seca que días atrás, sobre un manto ligeramente encostrado. En la parte superior de las canales del Cadí puede haber unos 30-40 cm de nieve reciente. Por encima de 2.200 m caerán aludes de nieve reciente de forma natural en laderas de fuerte pendiente en cualquier orientación; serán de tamaño 2, mediano, con capacidad de enterrar a una persona; en el sector más oriental de hasta tamaño 3, grande, con capacidad de cubrir un grupo de personas; caerán como placas blandas. En las cotas más altas, bajo collados y cordales del sector Moixeró podría haber placas de viento sobre todo en orientaciones norte y oeste, que caerán al paso de una persona; por lo general de tamaño 2. El lunes se mantiene la misma situación. Se recomienda no aventurarse por sitios no conocidos, ya que la falta de visibilidad a ratos nos impedirá identificar terreno avalanchoso.

Distribución del manto nivoso

En umbrías hay nieve por encima de 1.600 m, esquiable por encima de unos 1.700 m. En solanas la nieve está presente por encima de 1.800 m. Los grosores están alrededor de 160-180 cm a 2.200 m. Estos valores son muy excedentarios para la época del año.

Tendencia para las próximas 48-72h

Se tiende hacia un manto más seco en cotas altas con formación de más placas de viento en orientaciones norte. Peligro ESTACIONARIO.

El próximo boletín será emitido el día 2026-03-09

5 MUY FUERTE	4 FUERTE	3 NOTABLE	2 LIMITADO	1 DÉBIL

EAWS EUROPEAN AVALANCHE WARNING SERVICES

ICGC Institut Cartogràfic i Geològic de Catalunya

Servei Meteorològic de Catalunya

Boletín de peligro de aludes Prepirineu
Del 07/03/2026 al 09/03/2026

(Válido fuera pistas de esquí y zonas no controladas)

NOTABLE (3) por encima de 2.200 m.
LIMITADO (2) por debajo.

Situación primaria

Nieve reciente

Distribución

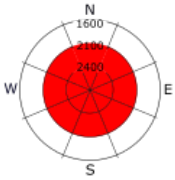

Tamaño

Origen

Tendencia

Estado del manto nivoso

El sábado se puede acumular algo más de nieve reciente (se prevé unos 5-10 cm). Por la mañana del domingo por encima de 2.300 m encontraremos unos 20-25 cm de nieve reciente, más seca que días atrás, por encima de un manto ligeramente encostrado internamente. Por encima de 2.200 m caerán aludes de nieve reciente de forma natural en laderas de fuerte pendiente en cualquier orientación; serán de tamaño 2, mediano, con capacidad de enterrar a una persona; caerán como placas blandas. En las cotas más altas, bajo collados y cordales se puede haber formado alguna placa de viento sobre todo en orientaciones norte y oeste, que caerá al paso de una persona; en general de tamaño 2, mediano. El lunes se mantiene la misma situación. Se recomienda no aventurarse por sitios no conocidos, ya que la falta de visibilidad a ratos nos impedirá identificar terreno avalanchoso.

Distribución del manto nivoso

En umbrías hay nieve por encima de 1.600-1700 m. En solanas la nieve está presente por encima de 1.800-1.900 m. Los espesores, aunque irregulares, rondan los 60-80 cm en cotas medias.

Tendencia para las próximas 48-72h

Se tiende hacia un manto más seco en cotas altas con formación de más placas de viento en orientaciones norte. Peligro ESTACIONARIO.

El próximo boletín será emitido el día 2026-03-09

5 MUY FUERTE	4 FUERTE	3 NOTABLE	2 LIMITADO	1 DÉBIL

EAWS EUROPEAN AVALANCHE WARNING SERVICES

ICGC Institut Cartogràfic i Geològic de Catalunya

Servei Meteorològic de Catalunya meteo.cat

Boletín de peligro de aludes Ter-Freser Del 07/03/2026 al 09/03/2026

(Válido fuera pistas de esquí y zonas no controladas)

NOTABLE (3)

Situación primaria

Nieve reciente

Distribución

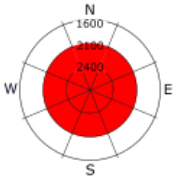

Tamaño

Origen

Tendencia

Situación secundaria

Nieve venteada

Distribución

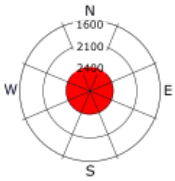

Tamaño

Origen

Tendencia

Estado del manto nivoso

El sábado se puede acumular algo más de nieve reciente (10 cm). Se observa actividad de aludes, en general de placa blanda. Domingo por encima de 2.400 m encontraremos nieve reciente, más seca que días atrás, unos 40-50 cm, incluso más en el sector Costabona, por encima de un manto ligeramente encostrado. Por encima de 2.200 m caerán aludes de nieve reciente, como placas blandas, de forma natural en laderas de fuerte pendiente en cualquier orientación; serán de tamaño 2, mediano, con capacidad de enterrar a una persona, incluso de tamaño 3, grande, con capacidad de enterrar a un grupo de personas en el sector del Costabona. En las cotas más altas, bajo collados y cordales hay placas de viento sobre todo en orientaciones norte y oeste, que caerán al paso de una persona; localmente de tamaño 3, grande. El lunes se mantiene la misma situación. Se recomienda no aventurarse por sitios no conocidos, ya que la falta de visibilidad a ratos nos impedirá identificar terreno avalanchoso.

Distribución del manto nivoso

Hay nieve en el suelo por encima de 1.600-1.700 m. Es esquiable a partir de unos 1.700 m. El manto nivoso presenta grosores muy excedentarios para la época del año. En lugares no afectados por el viento los grosores oscilan entre 80-100 cm a unos 2.000 my más de 200 cm por encima de 2.400 m.

Tendencia para las próximas 48-72h

Se tiende hacia un manto más seco en cotas altas con formación de más placas de viento en orientaciones norte. Peligro ESTACIONARIO.

El próximo boletín será emitido el día 2026-03-09

5 MUY FUERTE	4 FUERTE	3 NOTABLE	2 LIMITADO	1 DÉBIL

EAWS EUROPEAN AVALANCHE WARNING SERVICES